RÉPUBLIQUE FRANÇAISE
Liberté Égalité Fraternité

METEO FRANCE
À VOS CÔTÉS, DANS UN CLIMAT QUI CHANGE

Bulletin d'estimation du risque d'avalanche
(valable en dehors des pistes balisées et ouvertes)

MASSIF : Aravis

Rédigé le lundi 16 mars 2026 à 16h

Estimation des risques pour le : MARDI 17 MARS

INSTABILITÉS DANS LA NEIGE TOMBÉE CE WEEKEND

2

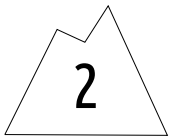

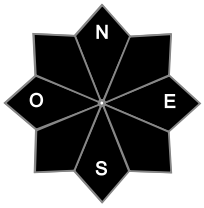

Indice de risque limité.

Départs spontanés : Avalanches humides au soleil.

Déclenchements provoqués : Plaques à vent

Indices de risque : 5 très fort - 4 fort - 3 marqué - 2 limité - 1 faible -- En noir : les pentes les plus dangereuses

Stabilité du manteau neigeux

Situation avalancheuse typique : neige ventée neige humide

Déclenchements provoqués :
* Au-dessus de 1800/2000 m : **Plaques à vent**. Formés par le **vent de N/NW** des derniers jours et en cours de formation en journée par le vent de **N/NE**. Elles se situent principalement dans les **ubacs d'altitude**. Elles sont **assez nombreuses près des crêtes**, mais elles sont **aussi présentes plus loin des crêtes** dans les secteurs les plus exposés au vent de N. **Assez facile à déclencher**. Taille 1 à 2 (petite à moyenne).
Observables : vaguelettes, fissures devant les skis, zones d'accumulations…
* Au-dessus de 1800m en NW/N/NE et 2500m ailleurs, une couche fragile est encore présente sous environ 1m de neige, mais très difficilement sollicitable. Dans le cas d'une avalanche en cascade, elle pourrait être sollicitée et engendrer des avalanches de taille 3 (grandes).
* L'après-midi : dans les adrets raides, de la neige humide peut partir sous les skis. Ces coulées peuvent prendre de l'ampleur en fonction de la pente.

Départs spontanés :
* Avalanches de neige humide dans les adrets. De plus en plus nombreuses au fil de l'ensoleillement. Taille 1 à 2 dans les adrets les plus raides.
* En dessous de 2200/2400 m : rares avalanches de fond, dans les zones herbeuses ou les dalles rocheuses. Taille 1 à 2 (petite à moyenne).

Qualité de la neige

Enneigement :
Il est correct pour la saison. En matinée, on retrouve de la neige dès 1000/1200 m. On retrouve un manteau réellement skiable à partir de 1200/1300 m en Nord et 1500/1600m en Sud.

Qualité de la neige mardi :
* Neige ventée près des crêtes d'un large secteur nord. La neige reste plus souple loin des crêtes en ubacs au-dessus de 1800/2000 m.
* En adrets neige regelée le matin qui transforme de plus en plus au fil de la course du soleil.

Aperçu météo pour le mardi 17 mars

nuit	matin	après-midi	soir

Grand soleil et vent de N/NE sensible. Températures en hausse : à 2000 m : de -3 à 6°C.

Pluie-Neige				
Iso 0 °C	1 900 m	2 600 m	2 700 m	2 800 m
Vent 2000 m	10 km/h	15 km/h	15 km/h	15 km/h
Vent 2500 m	25 km/h	30 km/h	30 km/h	35 km/h

Épaisseur de neige hors-piste

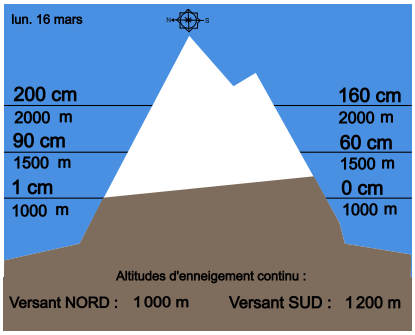

Précipitations à 1800 m

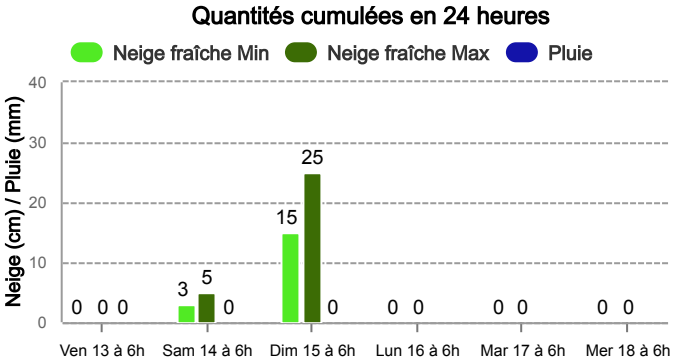

Tendance du mercredi 18 mars

2

Indice de risque limité

Risque stationnaire. Encore des instabilités dans les secteurs exposés au vent de N/NE en ubacs. Grand soleil.

Pour consulter la vigilance en cours, veuillez vous rendre sur le site https://vigilance.meteofrance.fr/fr

Météo-France - 73 avenue de Paris, 94165 Saint-Mandé cedex - Contact : contact@meteo.fr

Rédigé par Météo-France avec la contribution des observateurs du réseau nivo-météorologiques. Partenariat : ANMSM (Maires de Stations de Montagne), DSF (Domaines Skiables de France), ADSP (Directeurs de Pistes et de la Sécurité des Stations de Sports d'Hiver) et autres acteurs de la montagne.

Bulletin neige & avalanches par téléphone au
0 892 68 10 20 Service 0,35 € / min + prix appel

Bulletin d'estimation du risque d'avalanche

(valable en dehors des pistes balisées et ouvertes)

MASSIF : Aravis

Rédigé le lundi 16 mars 2026 à 16h

Conditions nivo-météo des 7 derniers jours

	mar. 10/03				mer. 11/03				jeu. 12/03				ven. 13/03				sam. 14/03				dim. 15/03				lun. 16/03			
	03h	09h	15h	21h	03h	09h	15h	21h	03h	09h	15h	21h	03h	09h	15h	21h	03h	09h	15h	21h	03h	09h	15h	21h	03h	09h	15h	21h
Météo																												
Vent (km/h)	25	40	40	40	40	50	60	45	30	20	5	10	30	45	50	70	55	30	20	45	45	20	15	15	15	20	20	20
à 2500m																												
Vent (km/h)	10	20	30	30	30	40	50	30	20	10	5	5	20	40	40	55	45	20	15	40	35	10	5	5	5	10	10	10
à 2000m																												

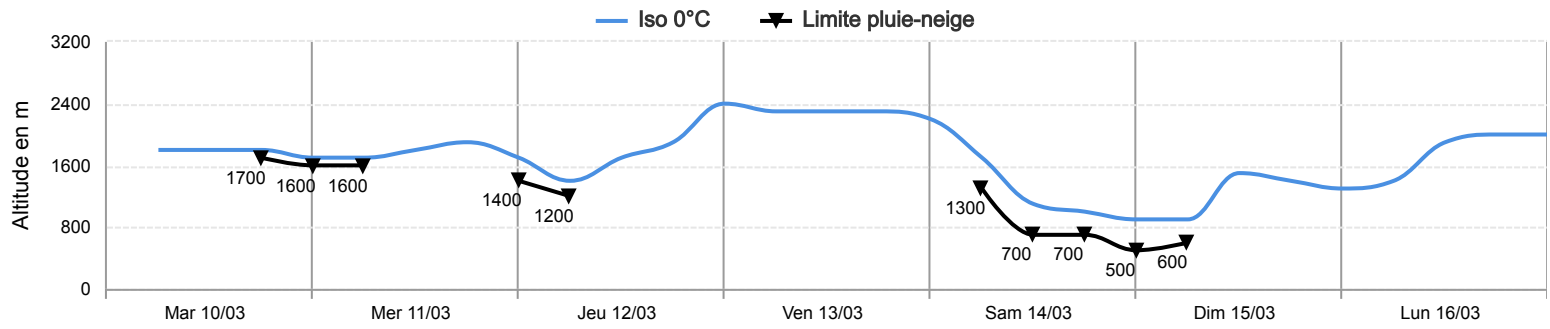

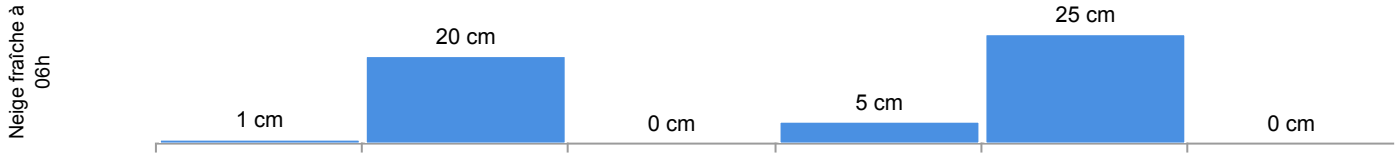

Risque d'avalanche	mar. 10/03	mer. 11/03	jeu. 12/03	ven. 13/03	sam. 14/03	dim. 15/03	lun. 16/03
	2	1	2	2	3	3	3

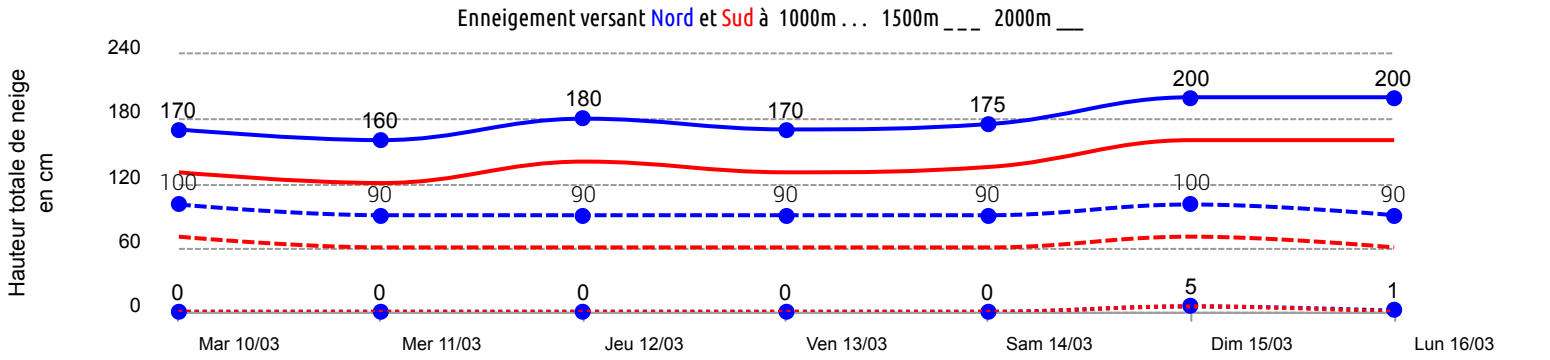

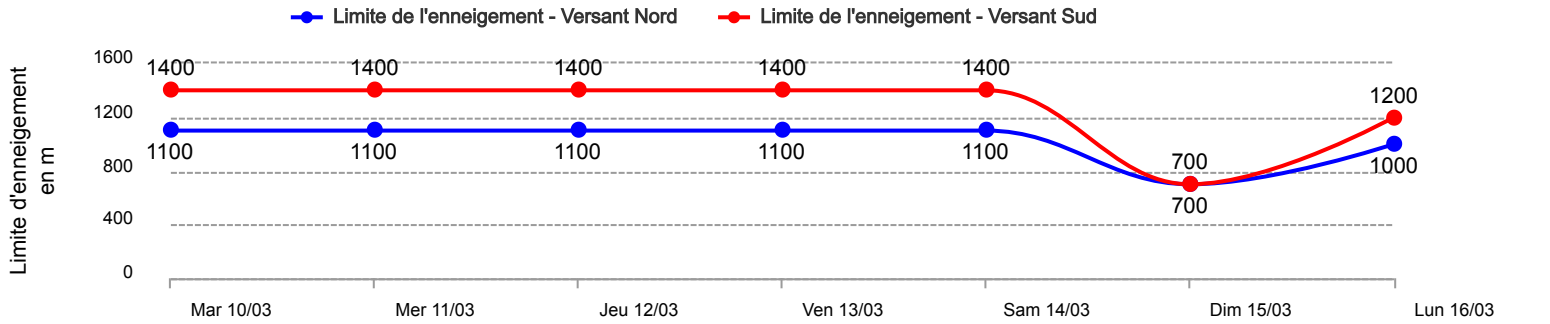

Pour consulter la vigilance en cours, veuillez vous rendre sur le site https://vigilance.meteofrance.fr/fr

Météo-France - 73 avenue de Paris, 94165 Saint-Mandé cedex - Contact : contact@meteo.fr

Rédigé par Météo-France avec la contribution des observateurs du réseau nivo-météorologiques. Partenariat : ANMSM (Maires de Stations de Montagne), DSF (Domaines Skiables de France), ADSP (Directeurs de Pistes et de la Sécurité des Stations de Sports d'Hiver) et autres acteurs de la montagne.

Bulletin neige & avalanches par téléphone au

0 892 68 10 20 Service 0,35 € / min + prix appel