RÉPUBLIQUE FRANÇAISE
Liberté Égalité Fraternité

METEO FRANCE
À VOS CÔTÉS, DANS UN CLIMAT QUI CHANGE

Bulletin d'estimation du risque d'avalanche
(valable en dehors des pistes balisées et ouvertes)

MASSIF : Bauges

Rédigé le lundi 16 mars 2026 à 16h

Estimation des risques pour le : MARDI 17 MARS

ENCORE QUELQUES INSTABILITÉS DANS LA NEIGE TOMBÉE CE WEEKEND

2

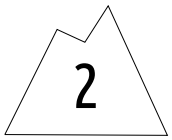

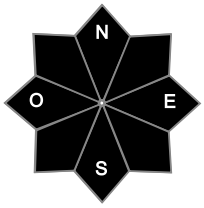

Indice de risque limité.

Départs spontanés : Avalanches humides au soleil.

Déclenchements provoqués : Plaques à vent en altitude.

Indices de risque : 5 très fort - 4 fort - 3 marqué - 2 limité - 1 faible -- En noir : les pentes les plus dangereuses

Stabilité du manteau neigeux

Situation avalancheuse typique : neige ventée neige humide

Départs spontanés :
* Avalanches de neige humide dans les adrets. De plus en plus nombreuses au fil de l'ensoleillement. Taille 1 à 2 dans les adrets les plus raides.
* Rares avalanches de fond, dans les zones herbeuses ou les dalles rocheuses. Taille 1 à 2 (petite à moyenne).

Déclenchements provoqués :
* **Au-dessus de 1800 m** : **Plaques à vent.** Formés par le vent de N/NW des derniers jours et en cours de formation en journée par le vent de N/NE. Elles sont **assez nombreuses près des crêtes en ubacs. Assez facile à déclencher**. Taille 1 à 2 (petite à moyenne).

Observables : vaguelettes, fissures devant les skis, zones d'accumulations…

Qualité de la neige

Enneigement :
Il est correct pour la saison. En matinée, on retrouve de la neige dès 1000/1200 m. On retrouve un manteau réellement skiable à partir de 1200/1300 m en Nord et 1500/1600m en Sud.

Qualité de la neige mardi :
* Neige ventée près des crêtes d'un large secteur nord.
* En adrets neige regelée le matin qui transforme de plus en plus au fil de la course du soleil.

Aperçu météo pour le mardi 17 mars

	nuit	matin	après-midi	soir

Grand soleil et bise sensible. Températures en hausse : à 1500 m : de -3 à 10°C.

Pluie-Neige				
Iso 0 °C	2 000 m	2 400 m	2 700 m	2 700 m
Vent 1500 m	10 km/h	10 km/h	15 km/h	15 km/h
Vent 2000 m	15 km/h	15 km/h	25 km/h	25 km/h

Épaisseur de neige hors-piste

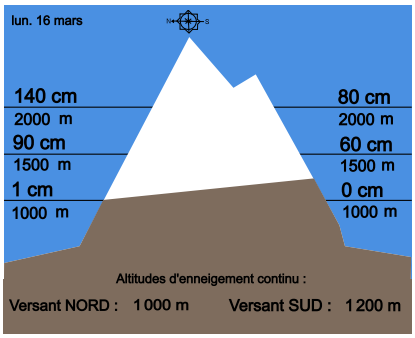

Précipitations à 1800 m

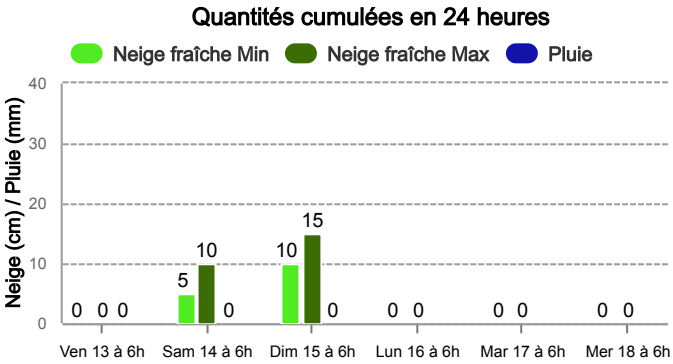

Tendance du mercredi 18 mars

2

Indice de risque limité

Risque en baisse. Grand soleil.

Pour consulter la vigilance en cours, veuillez vous rendre sur le site https://vigilance.meteofrance.fr/fr

Météo-France - 73 avenue de Paris, 94165 Saint-Mandé cedex - Contact : contact@meteo.fr

Rédigé par Météo-France avec la contribution des observateurs du réseau nivo-météorologiques. Partenariat : ANMSM (Maires de Stations de Montagne), DSF (Domaines Skiables de France), ADSP (Directeurs de Pistes et de la Sécurité des Stations de Sports d'Hiver) et autres acteurs de la montagne.

Bulletin neige & avalanches par téléphone au
0 892 68 10 20 Service 0,35 € / min + prix appel

RÉPUBLIQUE FRANÇAISE
Liberté Égalité Fraternité

METEO FRANCE
À VOS CÔTÉS, DANS UN CLIMAT QUI CHANGE

Bulletin d'estimation du risque d'avalanche

(valable en dehors des pistes balisées et ouvertes)

MASSIF : Bauges

Rédigé le lundi 16 mars 2026 à 16h

Conditions nivo-météo des 7 derniers jours

	mar. 10/03				mer. 11/03				jeu. 12/03				ven. 13/03				sam. 14/03				dim. 15/03				lun. 16/03			
	03h	09h	15h	21h	03h	09h	15h	21h	03h	09h	15h	21h	03h	09h	15h	21h	03h	09h	15h	21h	03h	09h	15h	21h	03h	09h	15h	21h
Météo																												
Vent (km/h)	15	30	30	30	30	40	40	40	20	10	5	5	20	30	40	60	45	35	25	25	35	25	30	15	15	20	20	15
à 2000m																												
Vent (km/h)	10	20	20	20	20	20	30	30	15	5	0	0	10	20	25	50	35	25	20	20	30	20	25	10	10	15	15	10
à 1500m																												

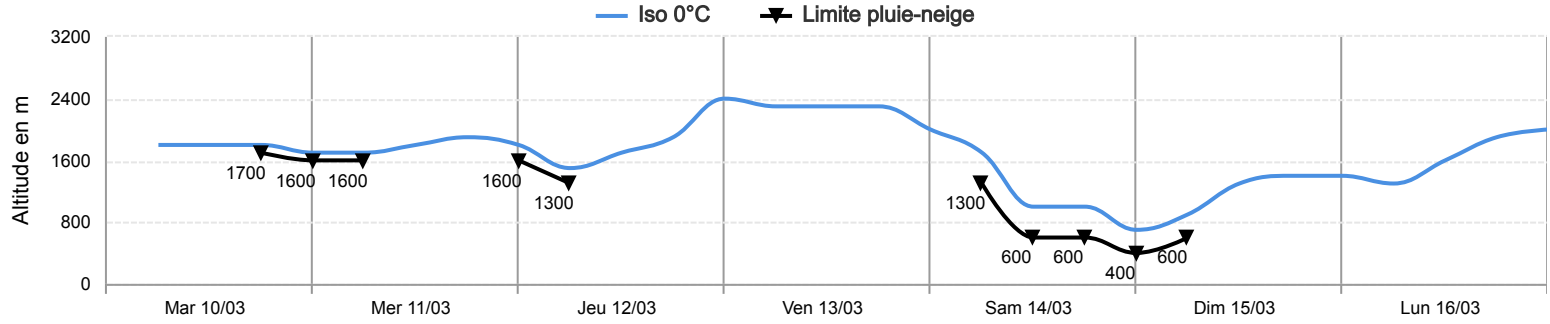

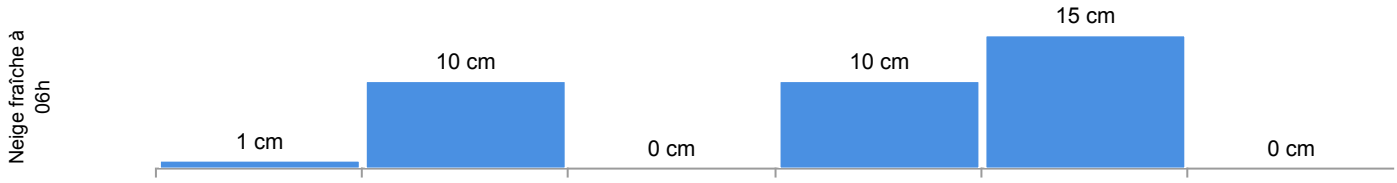

Risque d'avalanche	mar. 10/03	mer. 11/03	jeu. 12/03	ven. 13/03	sam. 14/03	dim. 15/03	lun. 16/03
	1	1	2	2	3	3	2

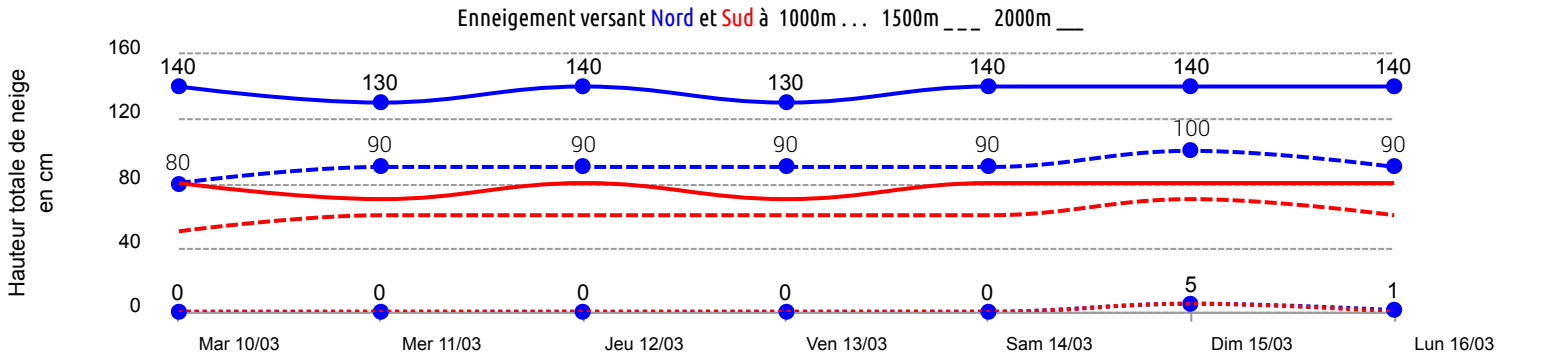

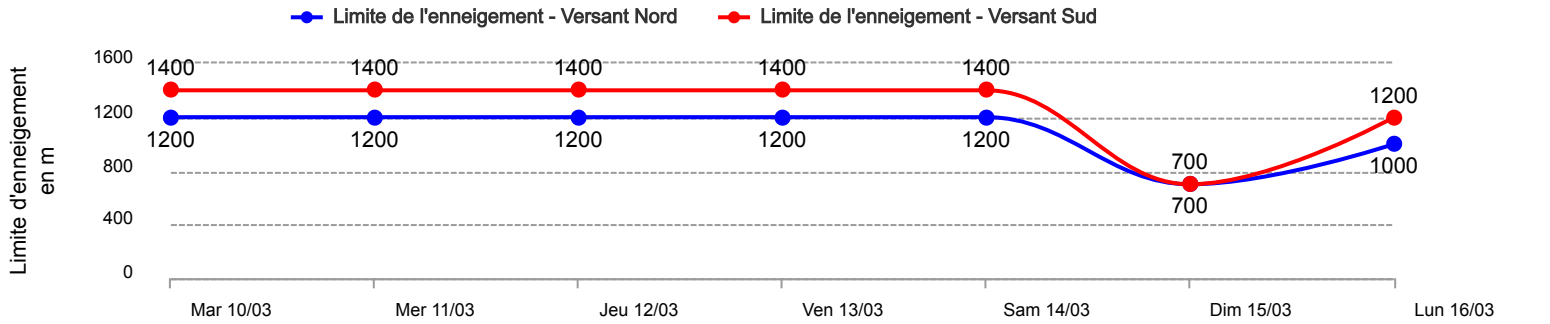

Pour consulter la vigilance en cours, veuillez vous rendre sur le site https://vigilance.meteofrance.fr/fr

Météo-France - 73 avenue de Paris, 94165 Saint-Mandé cedex - Contact : contact@meteo.fr

Bulletin neige & avalanches par téléphone au

0 892 68 10 20 Service 0,35 € / min + prix appel

Rédigé par Météo-France avec la contribution des observateurs du réseau nivo-météorologiques. Partenariat : ANMSM (Maires de Stations de Montagne), DSF (Domaines Skiables de France), ADSP (Directeurs de Pistes et de la Sécurité des Stations de Sports d'Hiver) et autres acteurs de la montagne.