Bulletin d'estimation du risque d'avalanche

(valable en dehors des pistes balisées et ouvertes)

MASSIF : Beaufortain

Rédigé le lundi 16 mars 2026 à 16h

Estimation des risques pour le : MARDI 17 MARS

STABILISATION DU MANTEAU NEIGEUX EN COURS, ENCORE QUELQUES PLAQUES EN PERTE DE RÉACTIVITÉ.

2

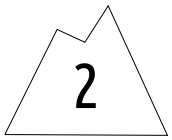

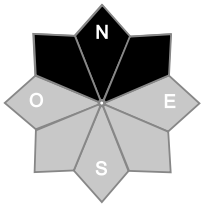

Indice de risque limité.

Départs spontanés : quelques départs en neige humide dans les versants ensoleillés.

Déclenchements provoqués : quelques plaques, principalement en neige ventée.

Indices de risque : 5 très fort - 4 fort - 3 marqué - 2 limité - 1 faible -- En noir : les pentes les plus dangereuses

Stabilité du manteau neigeux

Situation avalancheuse typique : neige ventée neige humide

Déclenchements provoqués : encore **quelques plaques en perte de réactivité, plutôt au-dessus de 2000 m et dans les versants ombragés.** Ces plaques résident **principalement près des crêtes** où le vent a fortement travaillé le manteau, elles sont alors **dures** et **identifiables** (neige ferme voire dure sous les skis). A l'inverse, en milieu et bas de pentes, les plaques se font **rares** mais revêtent encore un **aspect poudreux**. **Cassures généralement 10-30 cm**, avalanches de **taille moyenne**.

Départs spontanés : comme la veille, quelques départs ponctuels sont possibles dans la neige humide en versants ensoleillés. Les couloirs raides finissent de se purger. Petites à moyennes avalanches.

Qualité de la neige

Enneigement : généralement très bon, sauf aux basses altitudes où les hauteurs de neige sont tout juste correctes pour la saison.

Limite skiable : encore skiable dès 1100/1200 m dans les prairies orientées nord, plutôt 1400/1500 m en sud pas trop raide.

Qualité de la neige :
- en versants ombragés, crouté sous 1700/1900 m puis couche de neige récente meuble de plus en plus conséquente avec l'altitude (15/20 cm vers 2500 m), parfois redistribuée ou densifiée par le vent (neige dure sur les crêtes).
- en versants ensoleillés, mauvais printemps n'ayant pas encore subi suffisamment de cycles gel/dégel (sauf aux très basses altitudes). Croute, colle, bottage... on y verra tout !

Aperçu météo pour le mardi 17 mars

nuit	matin	après-midi	soir

Très beau temps ensoleillé, il fait doux dans les adrets.

Pluie-Neige				
Iso 0 °C	2 000 m	2 600 m	2 700 m	2 800 m
Vent 2000 m	↓ 10 km/h	↙ 10 km/h	↓ 10 km/h	↓ 20 km/h
Vent 3000 m	↓ 20 km/h	↓ 20 km/h	↓ 20 km/h	↙ 30 km/h

Épaisseur de neige hors-piste

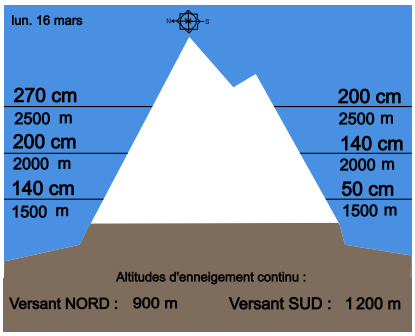

Précipitations à 1800 m

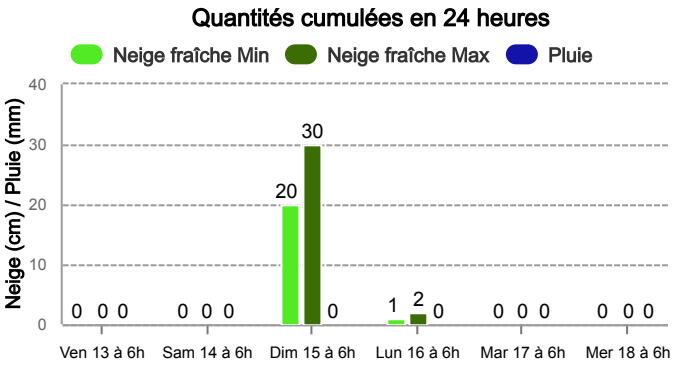

Tendance du mercredi 18 mars

2

Indice de risque limité

Encore du beau temps, un poil plus frais que les jours précédents : la stabilisation se poursuit, les plaques commencent à se faire rares... Encore temporairement un risque "limité".

Pour consulter la vigilance en cours, veuillez vous rendre sur le site https://vigilance.meteofrance.fr/fr

Météo-France - 73 avenue de Paris, 94165 Saint-Mandé cedex - Contact : contact@meteo.fr

Rédigé par Météo-France avec la contribution des observateurs du réseau nivo-météorologiques. Partenariat : ANMSM (Maires de Stations de Montagne), DSF (Domaines Skiables de France), ADSP (Directeurs de Pistes et de la Sécurité des Stations de Sports d'Hiver) et autres acteurs de la montagne.

Bulletin neige & avalanches par téléphone au

0 892 68 10 20 Service 0,35 € / min + prix appel

Bulletin d'estimation du risque d'avalanche

(valable en dehors des pistes balisées et ouvertes)

MASSIF : Beaufortain

Rédigé le lundi 16 mars 2026 à 16h

Conditions nivo-météo des 7 derniers jours

	mar. 10/03				mer. 11/03				jeu. 12/03				ven. 13/03				sam. 14/03				dim. 15/03				lun. 16/03			
	03h	09h	15h	21h	03h	09h	15h	21h	03h	09h	15h	21h	03h	09h	15h	21h	03h	09h	15h	21h	03h	09h	15h	21h	03h	09h	15h	21h
Météo																												
Vent (km/h)	25	25	20	25	25	25	30	40	30	25	20	20	20	25	30	65	50	25	30	40	35	40	15	10	20	30	30	20
à 3000m																												
Vent (km/h)	15	15	10	15	15	15	20	30	20	15	10	10	10	10	15	40	35	15	20	30	30	30	10	5	10	15	20	10
à 2000m																												

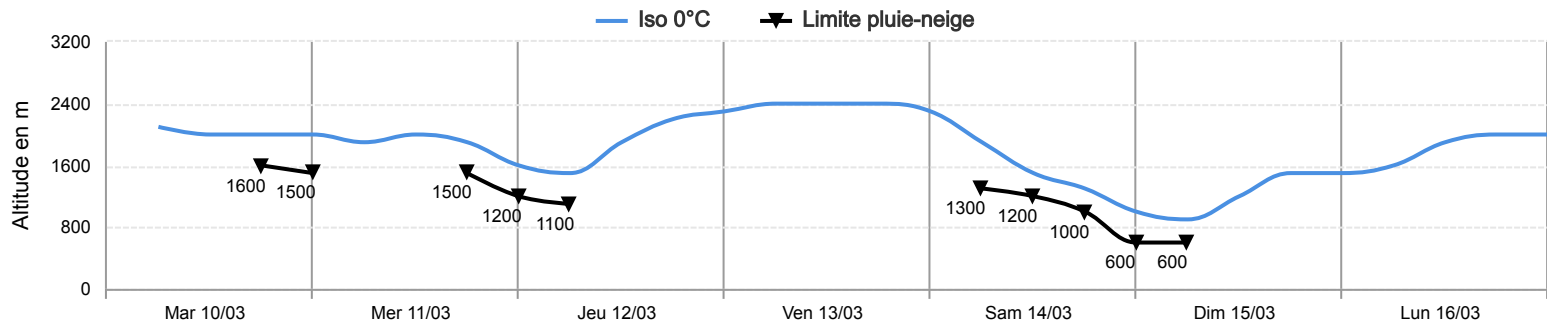

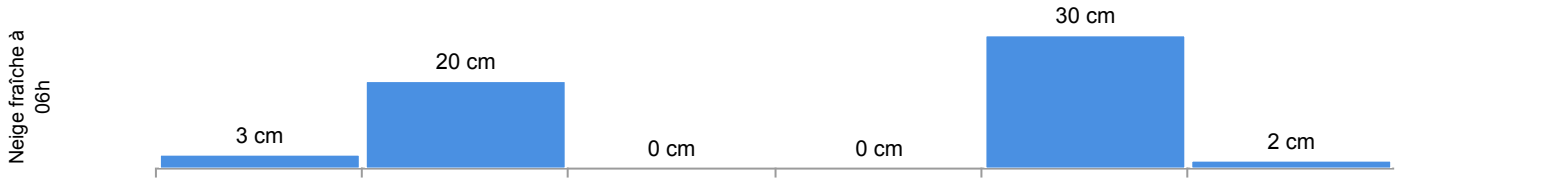

Risque d'avalanche	mar. 10/03	mer. 11/03	jeu. 12/03	ven. 13/03	sam. 14/03	dim. 15/03	lun. 16/03
	1	1	2	2	3	3	3

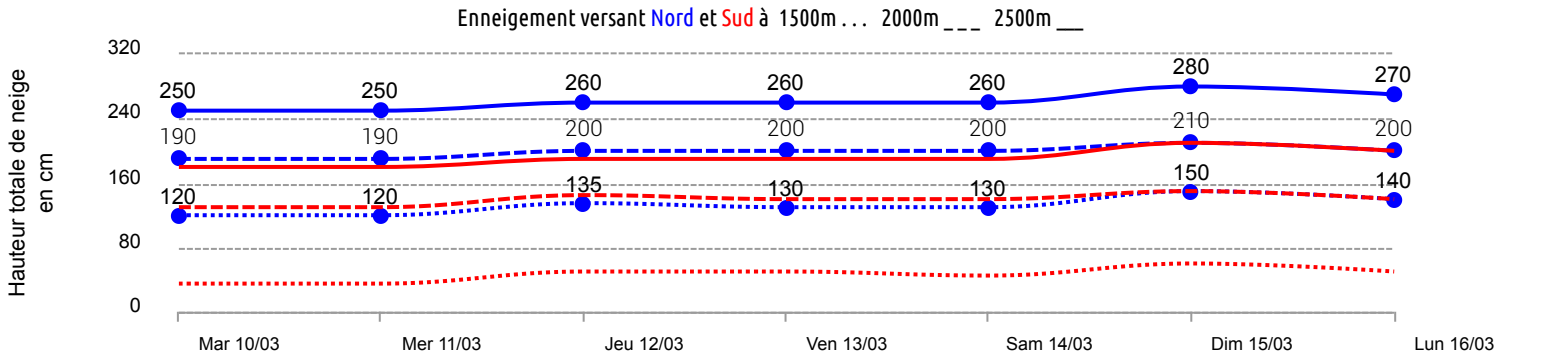

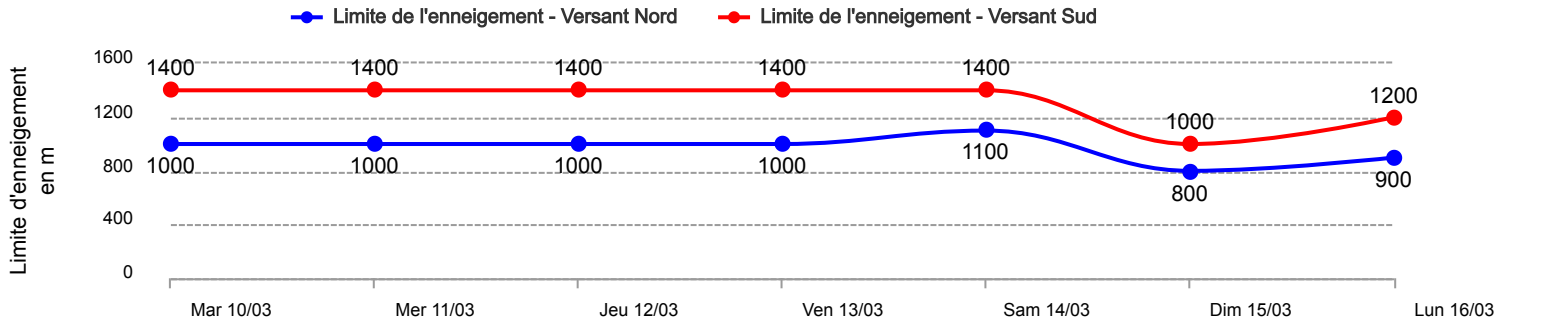

Pour consulter la vigilance en cours, veuillez vous rendre sur le site https://vigilance.meteofrance.fr/fr

Météo-France - 73 avenue de Paris, 94165 Saint-Mandé cedex - Contact : contact@meteo.fr

Bulletin neige & avalanches par téléphone au

0 892 68 10 20 Service 0,35 € / min + prix appel

Rédigé par Météo-France avec la contribution des observateurs du réseau nivo-météorologiques. Partenariat : ANMSM (Maires de Stations de Montagne), DSF (Domaines Skiables de France), ADSP (Directeurs de Pistes et de la Sécurité des Stations de Sports d'Hiver) et autres acteurs de la montagne.