Bulletin d'estimation du risque d'avalanche
(valable en dehors des pistes balisées et ouvertes)

MASSIF : Champsaur

Rédigé le lundi 16 mars 2026 à 16h

Estimation des risques pour le : MARDI 17 MARS

INSTABILITÉS EN UBACS D'ALTITUDE DANS LA NEIGE RÉCENTE VENTÉE. QUELQUES DÉPARTS EN NEIGE HUMIDE AU SOLEIL

3

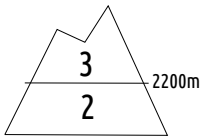

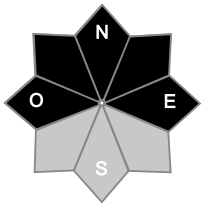

Au-dessus de 2200m indice de risque marqué, plus bas indice limité.

Départs spontanés : quelques départs ponctuels en neige humide

Déclenchements provoqués : avalanches de plaque encore fréquentes en ubacs d'altitude, faciles à déclencher.

Indices de risque : 5 très fort - 4 fort - 3 marqué - 2 limité - 1 faible -- En noir : les pentes les plus dangereuses

Stabilité du manteau neigeux

Situation avalancheuse typique : neige ventée neige humide

Déclenchements provoqués :
- Plaques à vent encore fréquentes au-dessus de 2200/2400 m dans les orientations ouest / nord / est ou à très haute altitude dans les adrets. Ces instabilités restent facilement déclenchables par un skieur. Avalanches souvent de taille moyenne, mobilisant la neige récente.
- À plus basses altitudes ou en adrets d'altitude, les instabilités sont en cours de stabilisation. Un déclenchement semble plus difficile.

Départs spontanés :
- Jusqu'en cours de nuit de lundi à mardi, rares départs sous forme de plaque par la surcharge liée au transport de la neige par le vent de nord. Plutôt haute altitude, taille petite à moyenne.
- Mardi en journée, possibles départs ponctuels de neige humide en pente raide, près des rochers, suivant la course du soleil. Taille petite, voire moyenne. L'humidification de la neige récente gagne ce mardi en altitude et en profondeur.

Qualité de la neige

L'enneigement est proche des normales pour une mi-mars.
Hauteurs de neige observées : 39 cm au hameau des Portes dans le Valgaudemar à 1270 m, 142 cm à la Nivôse d'Orcières à 2280 m, et 183 cm au-dessus de Prapic à 2480 m.

Limite d'enneigement skiable : vers 1400 m en ubacs, 1700/1800 m en adrets pas trop raides.

État de la neige de surface : neige récente (20/30 cm) cartonnée voire durcie par le vent en altitude et déjà alourdie sous 2200 m. En adrets, neige déjà humidifiée en altitude croutée après un bon regel nocturne. L'humidification se poursuit ce mardi au soleil gagnant en profondeur et en altitude.

Aperçu météo pour le mardi 17 mars

	nuit	matin	après-midi	soir
	1900 m			
Ensoleillé, redoux plus marqué				
Pluie-Neige				
Iso 0 °C	2 800 m	2 900 m	2 800 m	2 900 m
Vent 2000 m	10 km/h	5 km/h	10 km/h	5 km/h
Vent 3000 m	20 km/h	10 km/h	10 km/h	10 km/h

Épaisseur de neige hors-piste

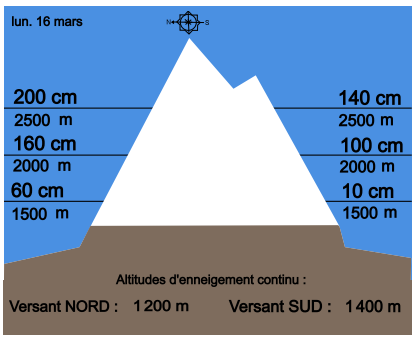

Précipitations à 1800 m

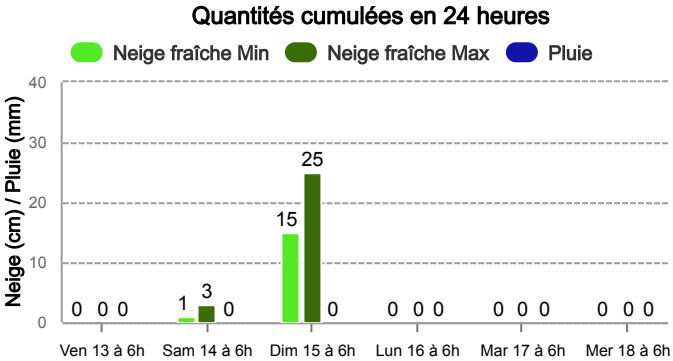

Tendance du mercredi 18 mars

2

Indice de risque limité

Risque stable ou en baisse. Poursuite de la stabilisation du manteau neigeux, même si quelques nouvelles instabilités peuvent se former avec le renforcement du vent d'est.

Pour consulter la vigilance en cours, veuillez vous rendre sur le site https://vigilance.meteofrance.fr/fr

Météo-France - 73 avenue de Paris, 94165 Saint-Mandé cedex - Contact : contact@meteo.fr

Rédigé par Météo-France avec la contribution des observateurs du réseau nivo-météorologiques. Partenariat : ANMSM (Maires de Stations de Montagne), DSF (Domaines Skiables de France), ADSP (Directeurs de Pistes et de la Sécurité des Stations de Sports d'Hiver) et autres acteurs de la montagne.

Bulletin neige & avalanches par téléphone au
0 892 68 10 20 Service 0,35 € / min + prix appel

RÉPUBLIQUE FRANÇAISE
Liberté Égalité Fraternité

METEO FRANCE
À VOS CÔTÉS, DANS UN CLIMAT QUI CHANGE

Bulletin d'estimation du risque d'avalanche
(valable en dehors des pistes balisées et ouvertes)
MASSIF : Champsaur

Rédigé le lundi 16 mars 2026 à 16h

Conditions nivo-météo des 7 derniers jours

	mar. 10/03				mer. 11/03				jeu. 12/03				ven. 13/03				sam. 14/03				dim. 15/03				lun. 16/03			
	03h	09h	15h	21h	03h	09h	15h	21h	03h	09h	15h	21h	03h	09h	15h	21h	03h	09h	15h	21h	03h	09h	15h	21h	03h	09h	15h	21h
Météo																												
Vent (km/h)	30	25	15	10	15	20	25	35	40	25	15	10	10	10	15	30	45	5	10	15	60	80	50	10	10	50	30	30
à 3000m																												
Vent (km/h)	20	15	15	5	5	5	15	10	15	15	10	10	5	5	10	10	10	20	20	30	70	80	50	5	10	40	20	15
à 2000m																												

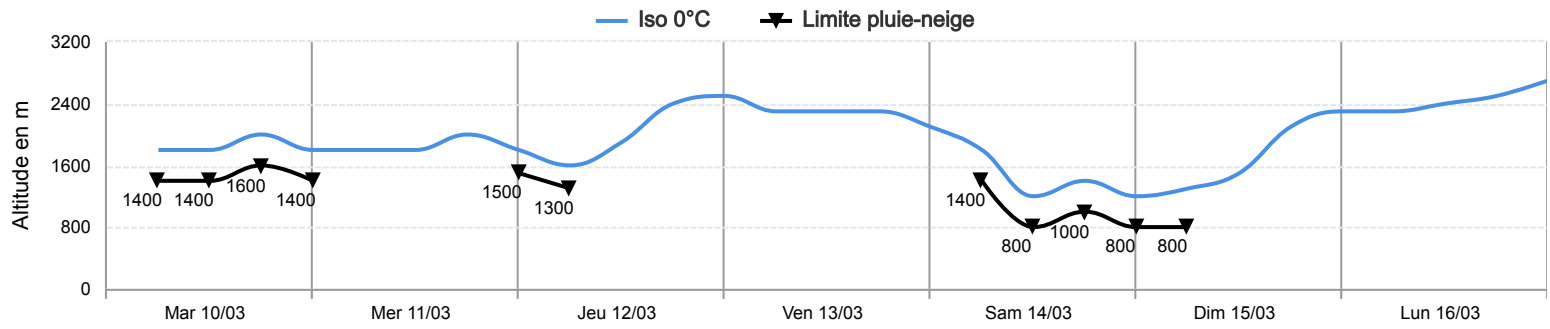

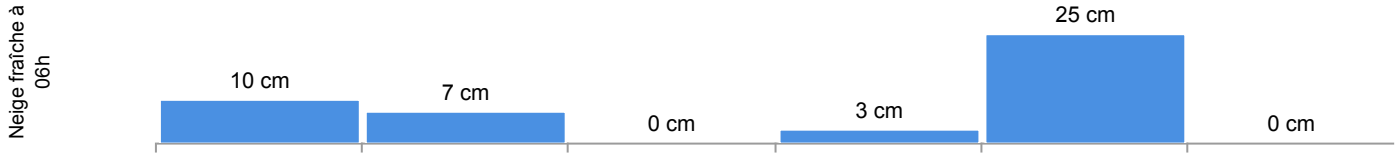

Risque d'avalanche	mar. 10/03	mer. 11/03	jeu. 12/03	ven. 13/03	sam. 14/03	dim. 15/03	lun. 16/03
	2	2	2	2	3	3	3

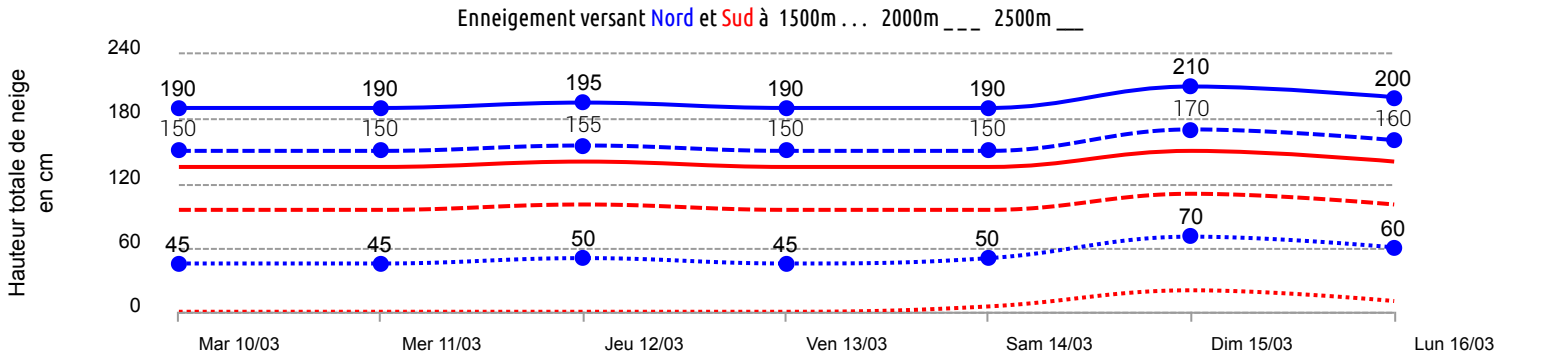

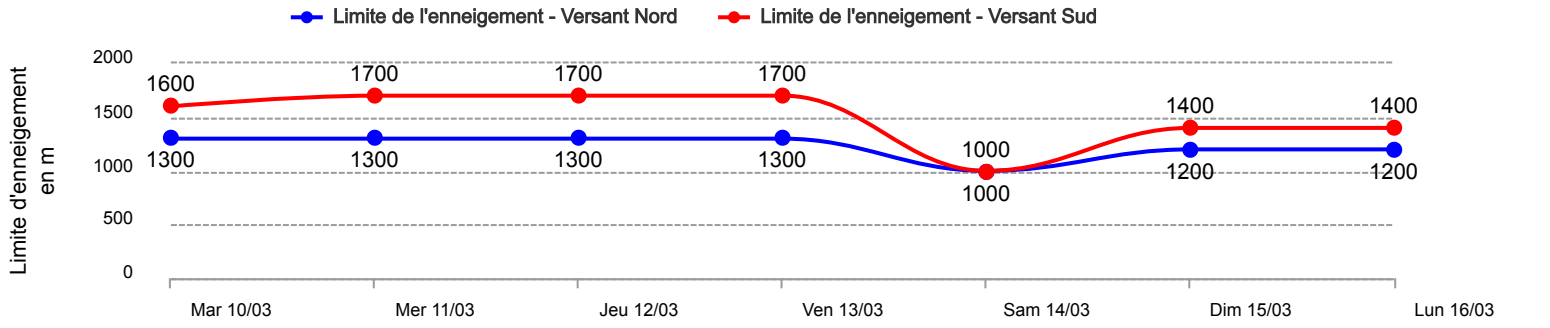

Pour consulter la vigilance en cours, veuillez vous rendre sur le site https://vigilance.meteofrance.fr/fr

Météo-France - 73 avenue de Paris, 94165 Saint-Mandé cedex - Contact : contact@meteo.fr

Rédigé par Météo-France avec la contribution des observateurs du réseau nivo-météorologiques. Partenariat : ANMSM (Maires de Stations de Montagne), DSF (Domaines Skiables de France), ADSP (Directeurs de Pistes et de la Sécurité des Stations de Sports d'Hiver) et autres acteurs de la montagne.

Bulletin neige & avalanches par téléphone au
0 892 68 10 20 Service 0,35 € / min + prix appel