Bulletin d'estimation du risque d'avalanche
(valable en dehors des pistes balisées et ouvertes)

MASSIF : Chartreuse

Rédigé le lundi 16 mars 2026 à 16h

Estimation des risques pour le : MARDI 17 MARS

QUELQUES INSTABILITÉS EN VERSANT FROID.

2

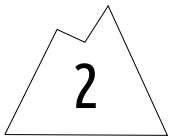

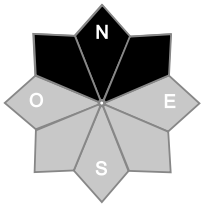

Indice de risque limité.

Départs spontanés : De plus en plus rares.

Déclenchements provoqués : Plaques de neige soufflée dans les versants ombragés.

Indices de risque : 5 très fort - 4 fort - 3 marqué - 2 limité - 1 faible -- En noir : les pentes les plus dangereuses

Stabilité du manteau neigeux

Situation avalancheuse typique : neige ventée

Déclenchements provoqués : la neige récente est en cours de tassement, mais la stabilisation est plus lente dans les versants froids où le vent a créé des accumulations de neige soufflée qui peuvent être mises en mouvement même par un skieur isolé.

Départs spontanés : l'essentiel des avalanches naturelles s'est déjà produit. Mardi, les coulées seront beaucoup moins fréquentes que ces dernières 48 heures, même si un départ spontané de neige humide sera encore possible localement (taille 1 à 2).

Qualité de la neige

Qualification de l'enneigement : L'enneigement est bon pour la saison en versants ombragés au dessus de 1300 m. Il est correct en Sud mais les sous-couches sont rares sous 1700/1800 m.
Limites skiables : Vers 1200/1600 m selon les versants.

Qualité de la neige mardi : Neige croûtée puis humide et lourde en journée de mardi dans les versants au soleil. Neige froide souvent travaillée par le vent dans les ubacs.

Aperçu météo pour le mardi 17 mars

	nuit	matin	après-midi	soir
Pluie-Neige				
Iso 0 °C	1 900 m	2 800 m	2 800 m	2 900 m
Vent 1500 m	15 km/h	15 km/h	10 km/h	10 km/h
Vent 2000 m	35 km/h	35 km/h	35 km/h	25 km/h

Épaisseur de neige hors-piste

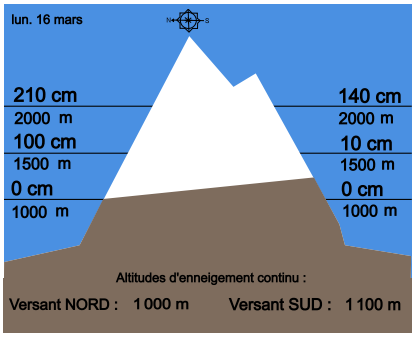

Précipitations à 1800 m

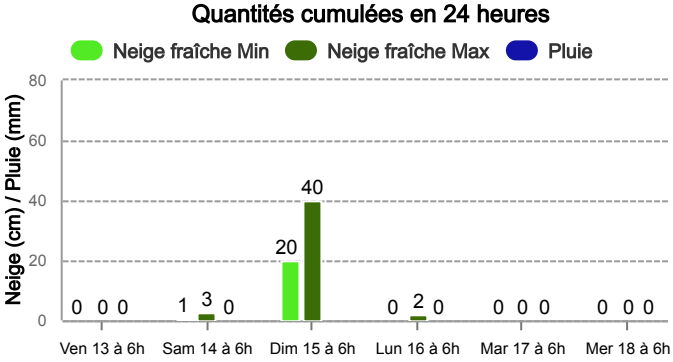

Tendance du mercredi 18 mars

2

Indice de risque limité

Poursuite de la stabilisation du manteau neigeux mercredi. Risques probablement en légère baisse.

Pour consulter la vigilance en cours, veuillez vous rendre sur le site https://vigilance.meteofrance.fr/fr

Météo-France - 73 avenue de Paris, 94165 Saint-Mandé cedex - Contact : contact@meteo.fr

Rédigé par Météo-France avec la contribution des observateurs du réseau nivo-météorologiques. Partenariat : ANMSM (Maires de Stations de Montagne), DSF (Domaines Skiables de France), ADSP (Directeurs de Pistes et de la Sécurité des Stations de Sports d'Hiver) et autres acteurs de la montagne.

Bulletin neige & avalanches par téléphone au 0 892 68 10 20 Service 0,35 € / min + prix appel

RÉPUBLIQUE FRANÇAISE
Liberté Égalité Fraternité

METEO FRANCE
À VOS CÔTÉS, DANS UN CLIMAT QUI CHANGE

Bulletin d'estimation du risque d'avalanche

(valable en dehors des pistes balisées et ouvertes)

MASSIF : Chartreuse

Rédigé le lundi 16 mars 2026 à 16h

Conditions nivo-météo des 7 derniers jours

	mar. 10/03				mer. 11/03				jeu. 12/03				ven. 13/03				sam. 14/03				dim. 15/03				lun. 16/03			
	03h	09h	15h	21h	03h	09h	15h	21h	03h	09h	15h	21h	03h	09h	15h	21h	03h	09h	15h	21h	03h	09h	15h	21h	03h	09h	15h	21h
Météo																												
Vent (km/h)	30	20	25	30	30	30	35	45	45	30	20	10	20	25	40	55	70	40	40	65	80	65	50	45	50	45	40	35
à 2000m																												
Vent (km/h)	20	15	20	15	20	25	30	20	25	20	15	5	10	15	30	40	45	20	25	50	70	45	40	25	35	30	25	20
à 1500m																												

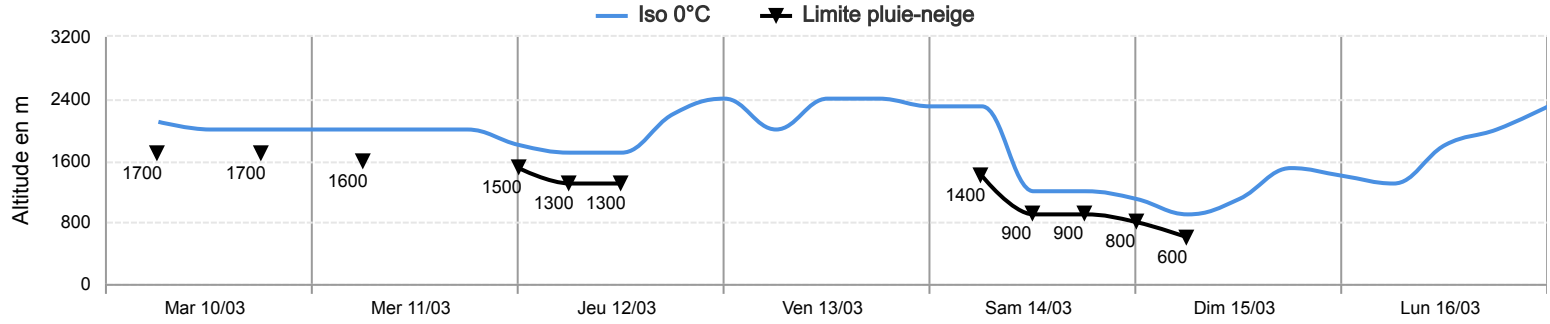

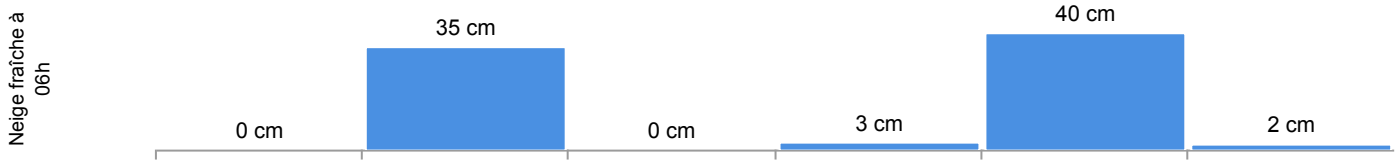

Risque d'avalanche	mar. 10/03	mer. 11/03	jeu. 12/03	ven. 13/03	sam. 14/03	dim. 15/03	lun. 16/03
	1	1	2	2	3	3	3

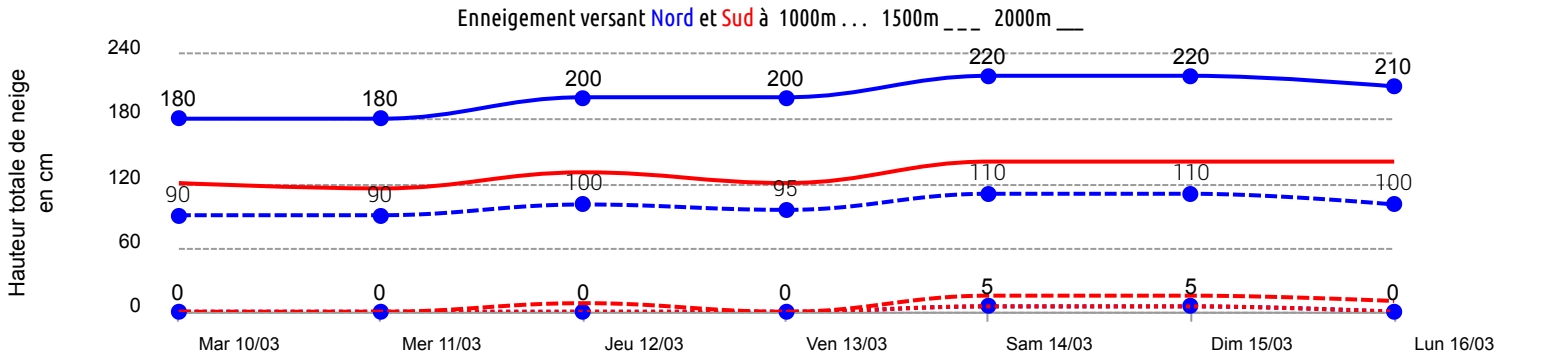

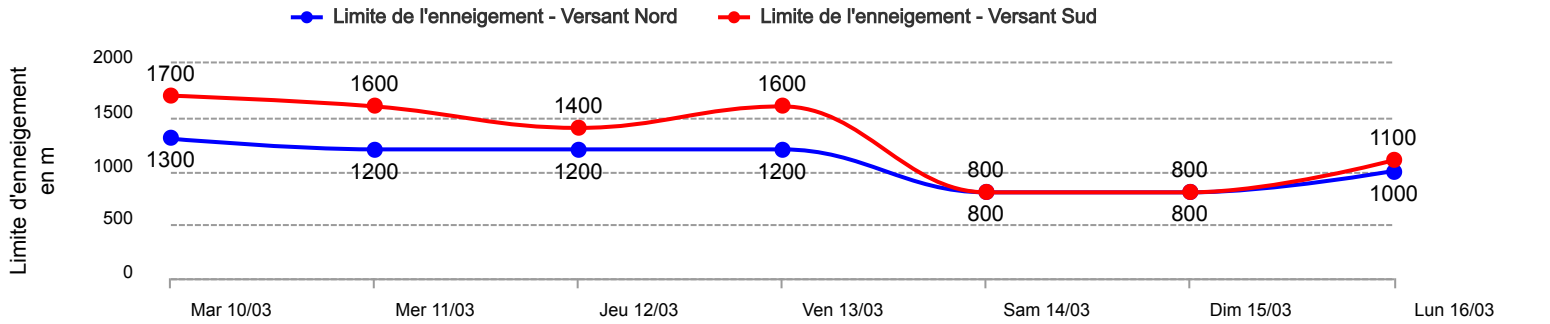

Pour consulter la vigilance en cours, veuillez vous rendre sur le site https://vigilance.meteofrance.fr/fr

Météo-France - 73 avenue de Paris, 94165 Saint-Mandé cedex - Contact : contact@meteo.fr

Rédigé par Météo-France avec la contribution des observateurs du réseau nivo-météorologiques. Partenariat : ANMSM (Maires de Stations de Montagne), DSF (Domaines Skiables de France), ADSP (Directeurs de Pistes et de la Sécurité des Stations de Sports d'Hiver) et autres acteurs de la montagne.

Bulletin neige & avalanches par téléphone au
0 892 68 10 20 Service 0,35 € / min + prix appel