RÉPUBLIQUE FRANÇAISE
*Liberté Égalité Fraternité*

METEO FRANCE
À VOS CÔTÉS, DANS UN CLIMAT QUI CHANGE

# Bulletin d'estimation du risque d'avalanche
## (valable en dehors des pistes balisées et ouvertes)
# MASSIF : Haute-Maurienne

Rédigé le lundi 16 mars 2026 à 16h

## Estimation des risques pour le : MARDI 17 MARS

**MANTEAU NEIGEUX ENCORE LOCALEMENT INSTABLE EN ALTITUDE, QUELQUES PLAQUES ÉPAISSES ET RÉACTIVES.**

3

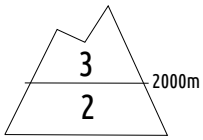


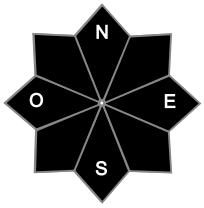


Au-dessus de 2000m indice de risque marqué, plus bas indice limité.

**Départs spontanés :** quelques départs en neige humide dans les versants ensoleillés.

**Déclenchements provoqués :** encore quelques plaques épaisses et faciles à déclencher.

Indices de risque : 5 très fort - 4 fort - 3 marqué - 2 limité - 1 faible -- En noir : les pentes les plus dangereuses

## Stabilité du manteau neigeux

**Situation avalancheuse typique :** neige ventée neige humide

**Déclenchements provoqués :** il subsiste **quelques plaques faciles à déclencher dans la neige récente**, entretenues par le vent modéré des derniers jours. C'est notamment **au-dessus de 2000 m** que ces plaques sont les plus réactives. Généralement d'**aspect poudreux**, ou légèrement **densifiées en approchant les crêtes**, ces plaques sont surtout **très épaisses dans les secteurs frontaliers** (Avérole/Evettes/Carro/Bonneval) : **les cassures peuvent alors atteindre 1 m à 1 m 20** et engendrer de **grandes avalanches (taille 3)**. Dans les autres secteurs, les plaques sont moins épaisses et perdent en réactivité : cassures max 40 à 70 cm. **Facteur aggravant :** la dernière chute de neige s'est localement déposée sur une fine couche de grains anguleux, ce qui tend à ralentir la stabilisation de ces plaques.
Enfin, en journée dans les versants ensoleillés, il sera possible de déclencher une avalanche de neige humide en coupant une pente surchauffée.

**Départs spontanés** : quelques départs ponctuels sont possibles dans la neige humide en versants ensoleillés. Les couloirs raides finissent de se purger. **Petites à moyennes avalanches, exceptionnellement une taille 3** si une plaque est ensuite mobilisée en cascade.

## Qualité de la neige

**Enneigement :** globalement très bon pour la saison.

**Limite skiable :** encore skiable dès 1100/1200 m dans les prairies orientées nord, plutôt 1400/1500 m en sud pas trop raide.

**Qualité de la neige :**
- en versants ombragés, grandes quantités de neige récente poudreuse, surtout dans les secteurs frontaliers (Carro/Evettes/Avérole), parfois légèrement densifiée près des crêtes (signe de plaque!)
- en versants ensoleillés, mauvais printemps n'ayant pas encore subi suffisamment de cycles gel/dégel (sauf aux très basses altitudes). Croute, colle, bottage... on y verra tout !

## Aperçu météo pour le mardi 17 mars

| nuit | matin | après-midi | soir |
|---|---|---|---|
| | | | |

Très beau temps ensoleillé, il fait doux dans les adrets. Petit vent de nord près des crêtes.

| Pluie-Neige | | | | |
|---|---|---|---|---|
| Iso 0 °C | 2 300 m | 2 700 m | 2 800 m | 2 800 m |
| Vent 2500 m | ↘ 20 km/h | ↘ 20 km/h | ↓ 20 km/h | ↓ 25 km/h |
| Vent 3500 m | ↓ 30 km/h | ↓ 30 km/h | ↓ 30 km/h | ↓ 40 km/h |

## Épaisseur de neige hors-piste

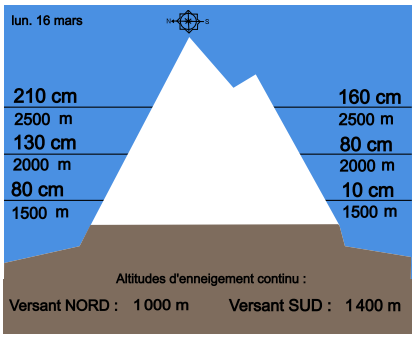


## Précipitations à 1800 m

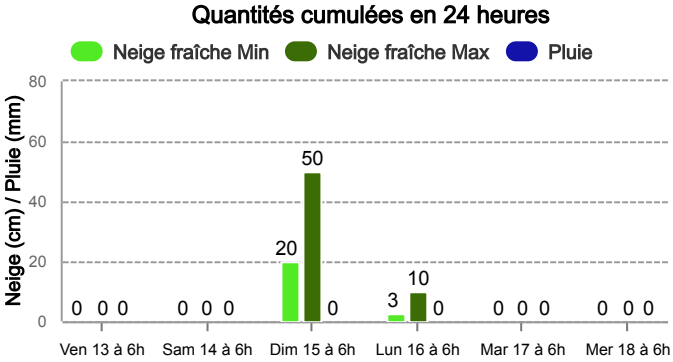


## Tendance du mercredi 18 mars

2

**Indice de risque limité**

Temps calme et peu venté, souvent nuageux en journée. Manteau neigeux en voie de stabilisation, le risque diminue et devient "limité".

Pour consulter la vigilance en cours, veuillez vous rendre sur le site https://vigilance.meteofrance.fr/fr

Météo-France - 73 avenue de Paris, 94165 Saint-Mandé cedex - Contact : contact@meteo.fr

Rédigé par Météo-France avec la contribution des observateurs du réseau nivo-météorologiques. Partenariat : ANMSM (Maires de Stations de Montagne), DSF (Domaines Skiables de France), ADSP (Directeurs de Pistes et de la Sécurité des Stations de Sports d'Hiver) et autres acteurs de la montagne.

Bulletin neige & avalanches par téléphone au
**0 892 68 10 20** Service 0,35 € / min + prix appel

RÉPUBLIQUE FRANÇAISE
*Liberté Égalité Fraternité*

METEO FRANCE
À VOS CÔTÉS, DANS UN CLIMAT QUI CHANGE

# Bulletin d'estimation du risque d'avalanche

(valable en dehors des pistes balisées et ouvertes)

# MASSIF : Haute-Maurienne

Rédigé le lundi 16 mars 2026 à 16h

## Conditions nivo-météo des 7 derniers jours

| | mar. 10/03 | | | | mer. 11/03 | | | | jeu. 12/03 | | | | ven. 13/03 | | | | sam. 14/03 | | | | dim. 15/03 | | | | lun. 16/03 | | | |
|---|---|---|---|---|---|---|---|---|---|---|---|---|---|---|---|---|---|---|---|---|---|---|---|---|---|---|---|---|
| | 03h | 09h | 15h | 21h | 03h | 09h | 15h | 21h | 03h | 09h | 15h | 21h | 03h | 09h | 15h | 21h | 03h | 09h | 15h | 21h | 03h | 09h | 15h | 21h | 03h | 09h | 15h | 21h |
| Météo | | | | | | | | | | | | | | | | | | | | | | | | | | | | |
| Vent (km/h) | 30 | 30 | 30 | 20 | 20 | 25 | 35 | 45 | 30 | 20 | 20 | 10 | 10 | 10 | 15 | 55 | 40 | 20 | 30 | 30 | 20 | 40 | 30 | 20 | 20 | 50 | 50 | 30 |
| à 3500m | ↑ | ↖ | ↗ | → | → | → | → | → | ↘ | ↘ | ↘ | ↘ | ↓ | ↓ | ↘ | ↗ | ↗ | ↘ | ↘ | ↘ | ← | ← | ↖ | → | ↘ | ↓ | ↓ | ↓ |
| Vent (km/h) | 25 | 20 | 15 | 10 | 10 | 10 | 25 | 35 | 20 | 10 | 10 | 5 | 5 | 5 | 10 | 40 | 30 | 10 | 25 | 25 | 10 | 25 | 10 | 10 | 10 | 40 | 40 | 20 |
| à 2500m | ← | ← | ← | ↑ | ↗ | ↗ | → | → | ↘ | ↘ | ↘ | ↘ | ↑ | ↑ | ↖ | ↗ | ↗ | ↘ | ↘ | ↘ | ↘ | ← | ↖ | ↘ | ↘ | ↘ | ↘ | ↘ |

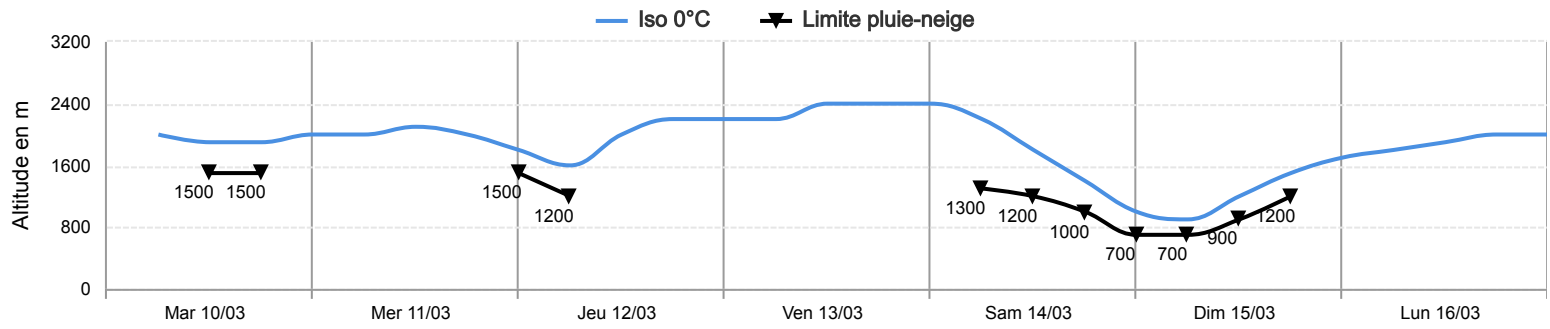


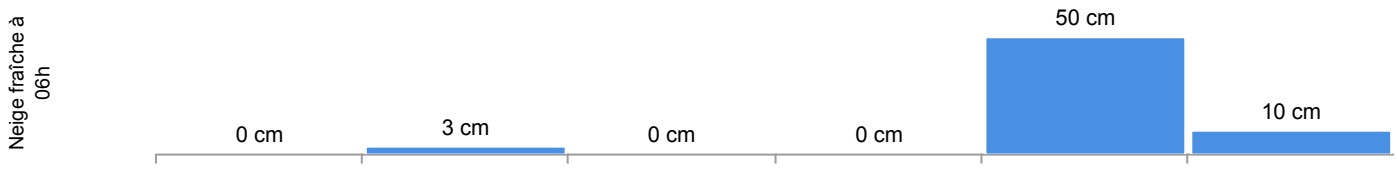


| Risque d'avalanche | mar. 10/03 | mer. 11/03 | jeu. 12/03 | ven. 13/03 | sam. 14/03 | dim. 15/03 | lun. 16/03 |
|---|---|---|---|---|---|---|---|
| | 2 | 2 | 2 | 2 | 3 | 4 | 3 |

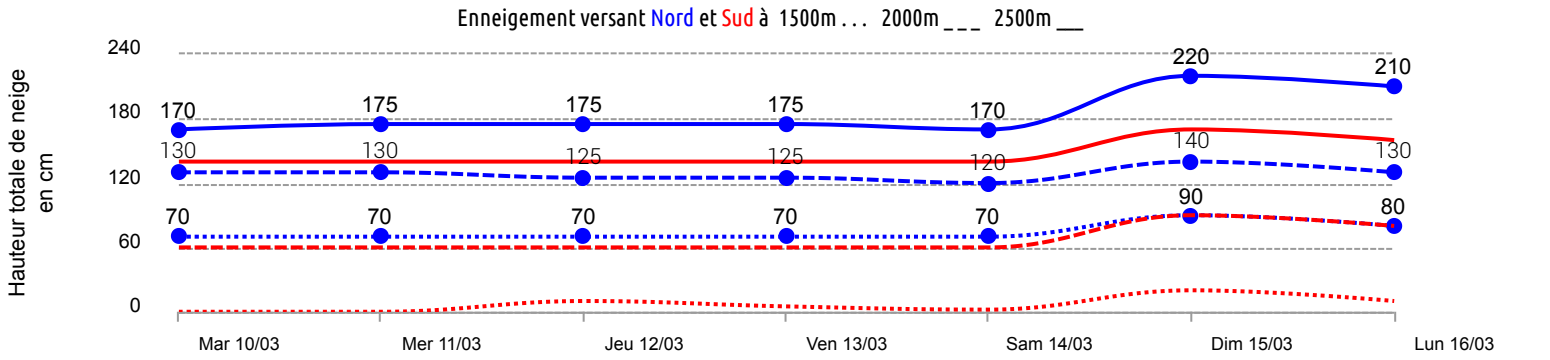


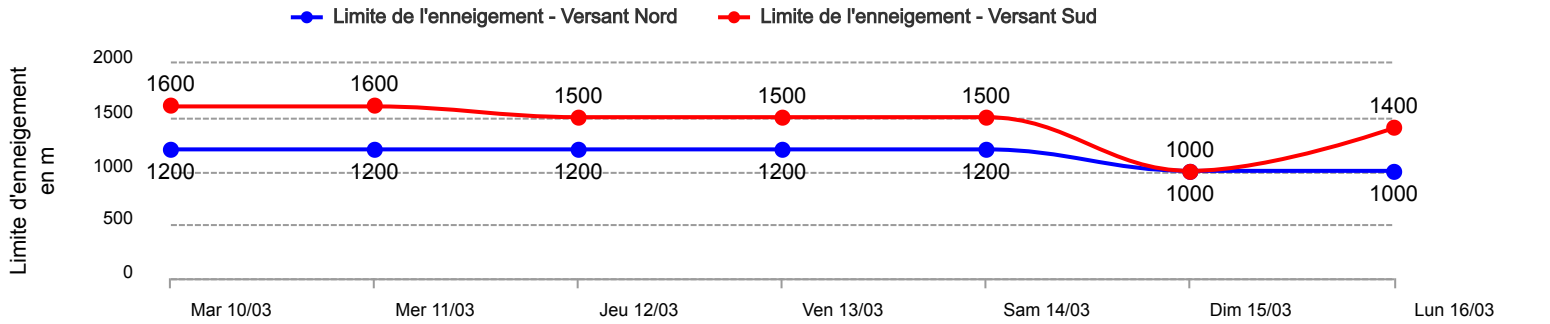


Pour consulter la vigilance en cours, veuillez vous rendre sur le site https://vigilance.meteofrance.fr/fr


Météo-France - 73 avenue de Paris, 94165 Saint-Mandé cedex - Contact : contact@meteo.fr



Rédigé par Météo-France avec la contribution des observateurs du réseau nivo-météorologiques. Partenariat : ANMSM (Maires de Stations de Montagne), DSF (Domaines Skiables de France), ADSP (Directeurs de Pistes et de la Sécurité des Stations de Sports d'Hiver) et autres acteurs de la montagne.



Bulletin neige & avalanches par téléphone au
0 892 68 10 20 Service 0,35 € / min + prix appel