Bulletin d'estimation du risque d'avalanche

(valable en dehors des pistes balisées et ouvertes)

MASSIF : Mercantour

Rédigé le lundi 16 mars 2026 à 16h

Estimation des risques pour le : MARDI 17 MARS

PLAQUES EN DANS LA NEIGE RÉCENTE VENTÉE EN ALTITUDE, PLUS ÉPAISSES EN ROYA - QUELQUES DÉPARTS NATURELS EN NEIGE HUMIDE.

3

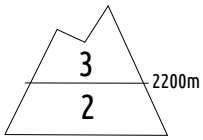

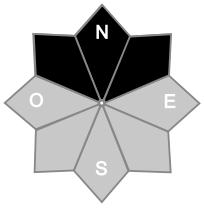

Au-dessus de 2200m indice de risque marqué, plus bas indice limité.

Départs spontanés : départs en neige récente s'humidifiant au soleil.

Déclenchements provoqués : plaques en ubacs d'altitude, plus épaisses vers la Roya.

Indices de risque : 5 très fort - 4 fort - 3 marqué - 2 limité - 1 faible -- En noir : les pentes les plus dangereuses

Stabilité du manteau neigeux

Situation avalancheuse typique : neige ventée neige humide

Déclenchements provoqués :
plaques en place dans la neige récente ventée, principalement dans les ubacs au-dessus de 2000/2200 m, où la neige est restée froide. Ces plaques peuvent encore céder au passage d'un skieur malgré leur stabilisation progressive, et génèrent des avalanches de taille moyenne voir grande en secteurs frontaliers de la Vésubie et la Roya (taille 2 à 3). Plaques généralement durcies par le vent, mais parfois d'aspect poudreux dans les combes nord plus abrités.
À plus basse altitude et en versant sud, manteau neigeux regelé et stable au levé du jour. Quelques départs sous les skis sont possibles au soleil dans les pentes fortement humidifiées, restants de petite taille, rarement moyenne en Roya.

Départs spontanés :
Avalanches de neige récente s'humidifiant au soleil au fil de la journée. Départs ponctuels en pentes raides ensoleillées, de taille petite à moyenne. Rares cassures linéaires à proximité des crêtes, générant des avalanches de taille moyenne voir grande.

Qualité de la neige

Enneigement excédentaire dans la Roya, sinon dans les normales.
Données observées : 162 cm à la nivôse de Millefonts à 2430 m, 122 cm à Isola 2000 à 1912 m.

Enneigement skiable : vers 1300/1400 m en ubacs, 1700/1800 m en adrets peu pentus.

État de la neige en surface : neige généralement croutée au levé du jour après un bon regel nocturne, s'humidifiant rapidement en journée au fil de l'ensoleillement. On retrouve de la neige froide encore légère ou densifiée par le vent en ubacs au-dessus de 2000/2200 m. Sur les crêtes, des corniches épaisses côtoient des zones dégarnies par le vent.

Aperçu météo pour le mardi 17 mars

	nuit	matin	après-midi	soir
	Temps sec, doux et ensoleillé.			
Pluie-Neige				
Iso 0 °C	2 800 m	2 800 m	2 700 m	2 700 m
Vent 2000 m	↓ 15 km/h	↓ 15 km/h	↘ 15 km/h	↘ 15 km/h
Vent 3000 m	↘ 20 km/h	↘ 15 km/h	↘ 20 km/h	↘ 20 km/h

Épaisseur de neige hors-piste

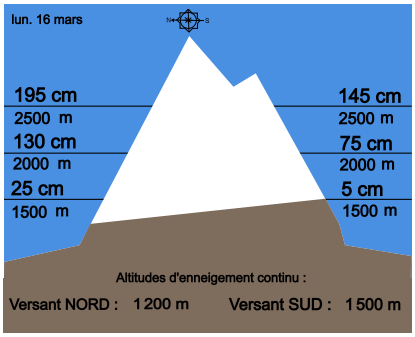

Précipitations à 1800 m

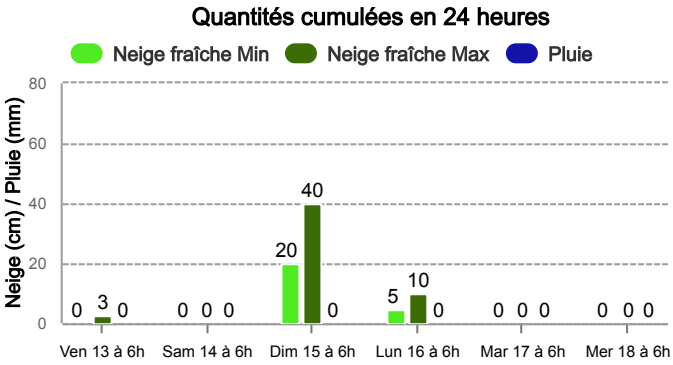

Tendance du mercredi 18 mars

2

Indice de risque limité

Plaques se stabilisant progressivement, encore localement sensibles en ubacs d'altitude notamment l'après-midi avec le renforcement de la lombarde. Pas d'activité en neige humide.

Pour consulter la vigilance en cours, veuillez vous rendre sur le site https://vigilance.meteofrance.fr/fr

Météo-France - 73 avenue de Paris, 94165 Saint-Mandé cedex - Contact : contact@meteo.fr

Rédigé par Météo-France avec la contribution des observateurs du réseau nivo-météorologiques. Partenariat : ANMSM (Maires de Stations de Montagne), DSF (Domaines Skiables de France), ADSP (Directeurs de Pistes et de la Sécurité des Stations de Sports d'Hiver) et autres acteurs de la montagne.

Bulletin neige & avalanches par téléphone au 0 892 68 10 20 Service 0,35 € / min + prix appel

Bulletin d'estimation du risque d'avalanche

(valable en dehors des pistes balisées et ouvertes)

MASSIF : Mercantour

Rédigé le lundi 16 mars 2026 à 16h

Conditions nivo-météo des 7 derniers jours

	mar. 10/03				mer. 11/03				jeu. 12/03				ven. 13/03				sam. 14/03				dim. 15/03				lun. 16/03			
	03h	09h	15h	21h	03h	09h	15h	21h	03h	09h	15h	21h	03h	09h	15h	21h	03h	09h	15h	21h	03h	09h	15h	21h	03h	09h	15h	21h
Météo																												
Vent (km/h)	45	40	30	20	25	35	45	40	40	40	40	30	25	20	30	25	60	55	40	25	60	80	50	35	45	40	35	30
à 3000m																												
Vent (km/h)	20	10	15	10	10	15	20	15	20	40	35	25	30	10	15	10	15	35	25	15	30	55	40	25	35	30	25	15
à 2000m																												

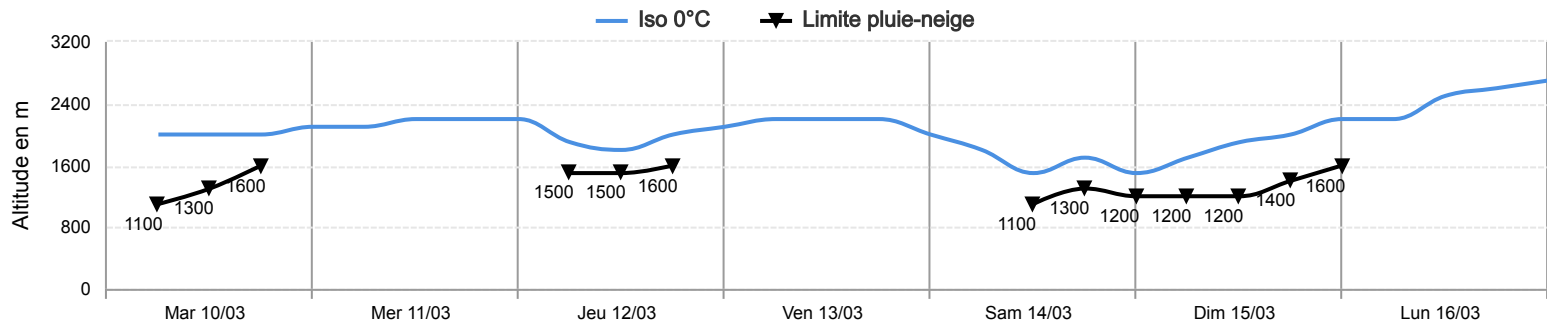

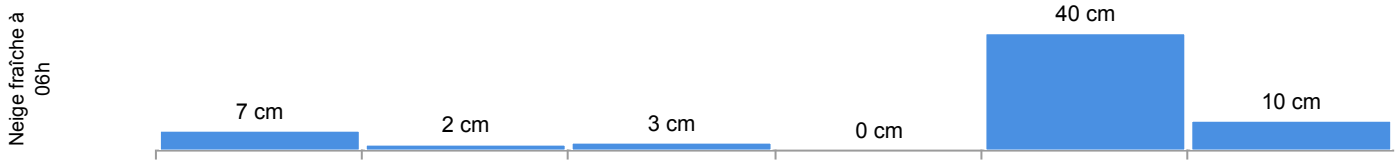

Risque d'avalanche	mar. 10/03	mer. 11/03	jeu. 12/03	ven. 13/03	sam. 14/03	dim. 15/03	lun. 16/03
	2	2	2	2	3	3	3

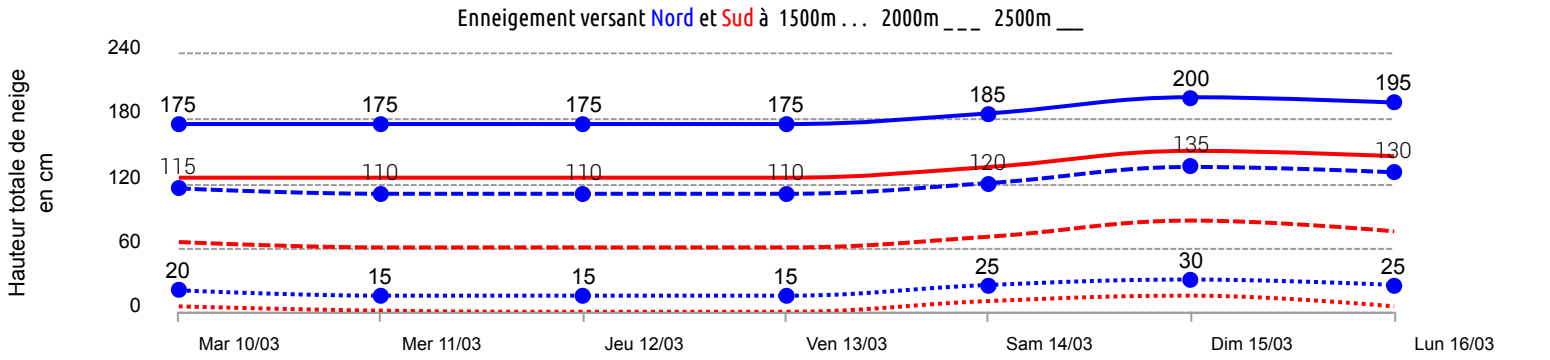

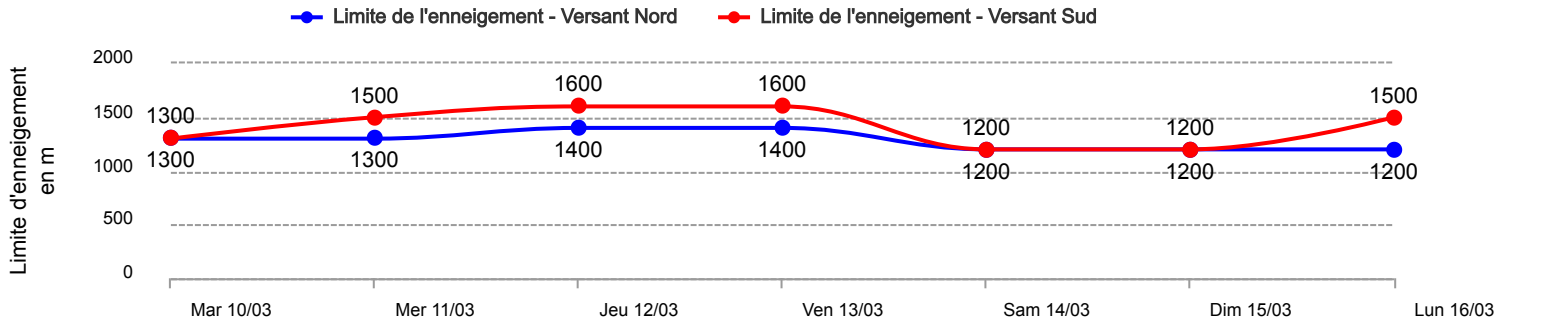

Pour consulter la vigilance en cours, veuillez vous rendre sur le site https://vigilance.meteofrance.fr/fr

Météo-France - 73 avenue de Paris, 94165 Saint-Mandé cedex - Contact : contact@meteo.fr

Rédigé par Météo-France avec la contribution des observateurs du réseau nivo-météorologiques. Partenariat : ANMSM (Maires de Stations de Montagne), DSF (Domaines Skiables de France), ADSP (Directeurs de Pistes et de la Sécurité des Stations de Sports d'Hiver) et autres acteurs de la montagne.

Bulletin neige & avalanches par téléphone au

0 892 68 10 20 Service 0,35 € / min + prix appel