RÉPUBLIQUE FRANÇAISE
Liberté Égalité Fraternité

METEO FRANCE
À VOS CÔTÉS, DANS UN CLIMAT QUI CHANGE

Bulletin d'estimation du risque d'avalanche
(valable en dehors des pistes balisées et ouvertes)

MASSIF : Pays-Basque

Rédigé le lundi 16 mars 2026 à 16h

Estimation des risques pour le : MARDI 17 MARS

HUMIDIFICATION, ENCORE QUELQUES RARES PLAQUES EN ALTITUDE

2

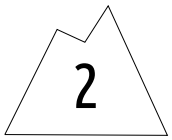

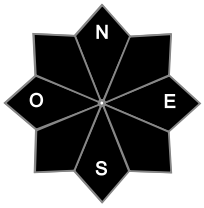

Plaques et soleil

Indice de risque limité.

Départs spontanés : Au fil de l'ensoleillement

Déclenchements provoqués : Rares plaques instables dans la neige récente à l'ombre

Indices de risque : 5 très fort - 4 fort - 3 marqué - 2 limité - 1 faible -- En noir : les pentes les plus dangereuses

Stabilité du manteau neigeux

Situation avalancheuse typique : neige humide neige ventée

DECLENCHEMENTS PROVOQUES :
Des plaques persistent dans les expositions nord bien ombragées, plutôt loin des crêtes et cols, dans les secteurs abrités du vent, et ont un aspect poudreux ou dur. Dans les autres expositions plus ensoleillées, les plaques en place sont en cours d'humidification et deviennent moins réactives. Observables : neige de surface encore seiche, fissures devant les skis, signes de transport passé (surface de la neige hétérogène, vagues, accumulations)

DEPARTS SPONTANES :
Peu d'activité en tout début de journée avec un bon regel. Puis, d'est en ouest au fil de l'ensoleillement, des départs spontanés sont attendus, souvent ponctuels, de taille petite à moyenne. Plus rarement, des départs linéaires sont possibles, avec le déclenchement spontané d'une plaque, engendrant une grande avalanche. Observables : neige devenant très humidie au soleil, enfoncement important des batons.

Qualité de la neige

Enneigement : L'enneigement est correct pour la saison, surtout au-dessus de 1800 m, mais reste assez maigre en versants exposés au vent d'ouest. Il débute assez bas, mais n'est skiable qu'à partir de 1600m en nord, plutôt 1800 en sud, faute de sous-couche.
État de la neige : en expositions ombragées, la neige reste sèche au-dessus de 1800m, mais de qualité très variable, alternant zones pelées en glace, accumulations dures ou croutées, et zones en neige plus tendre dans les secteurs abrités. Ailleurs, la neige a repris un aspect printanier, regelée le matin, dégelant rapidement en est et sud, plus tardivement à l'ouest

Aperçu météo pour le mardi 17 mars

	nuit	matin	après-midi	soir

Très bien ensoleillé, sans vent. Faibles gelées puis nette montée des températures.

Pluie-Neige				
Iso 0 °C	3 100 m	3 400 m	3 400 m	3 500 m
Vent 1000 m	10 km/h	15 km/h	15 km/h	20 km/h
Vent 2000 m	20 km/h	15 km/h	20 km/h	20 km/h

Épaisseur de neige hors-piste

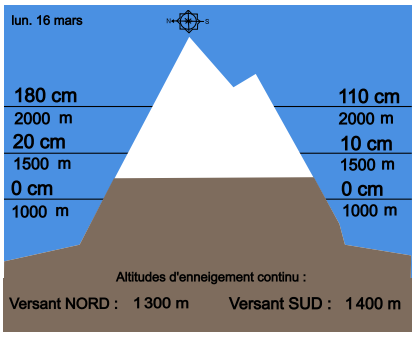

Précipitations à 1800 m

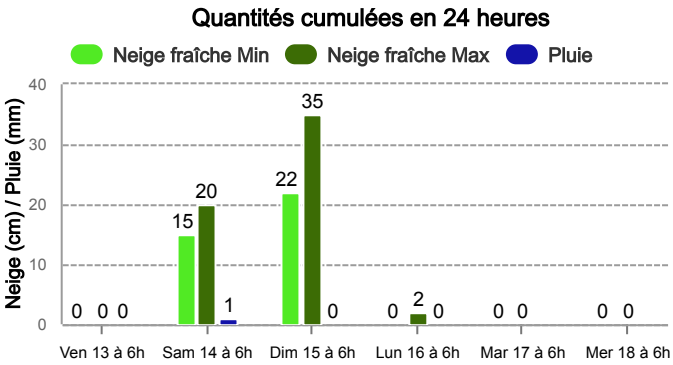

Tendance du mercredi 18 mars

2

Indice de risque limité

Le tassement des plaques continue, l'humidification progresse

Pour consulter la vigilance en cours, veuillez vous rendre sur le site https://vigilance.meteofrance.fr/fr

Météo-France - 73 avenue de Paris, 94165 Saint-Mandé cedex - Contact : contact@meteo.fr

Rédigé par Météo-France avec la contribution des observateurs du réseau nivo-météorologiques. Partenariat : ANMSM (Maires de Stations de Montagne), DSF (Domaines Skiables de France), ADSP (Directeurs de Pistes et de la Sécurité des Stations de Sports d'Hiver) et autres acteurs de la montagne.

Bulletin neige & avalanches par téléphone au
0 892 68 10 20 Service 0,35 € / min + prix appel

RÉPUBLIQUE FRANÇAISE
Liberté Égalité Fraternité

METEO FRANCE
À VOS CÔTÉS, DANS UN CLIMAT QUI CHANGE

Bulletin d'estimation du risque d'avalanche
(valable en dehors des pistes balisées et ouvertes)
MASSIF : Pays-Basque

Rédigé le lundi 16 mars 2026 à 16h

Conditions nivo-météo des 7 derniers jours

	mar. 10/03				mer. 11/03				jeu. 12/03				ven. 13/03				sam. 14/03				dim. 15/03				lun. 16/03			
	03h	09h	15h	21h	03h	09h	15h	21h	03h	09h	15h	21h	03h	09h	15h	21h	03h	09h	15h	21h	03h	09h	15h	21h	03h	09h	15h	21h
Météo																												
Vent (km/h)	15	15	30	60	50	45	60	50	30	35	20	20	30	60	55	55	65	60	55	70	70	75	65	50	50	35	30	20
à 2000m																												
Vent (km/h)	10	10	15	10	15	10	20	15	10	15	5	5	15	20	20	15	25	20	20	35	40	50	35	20	20	20	20	10
à 1000m																												

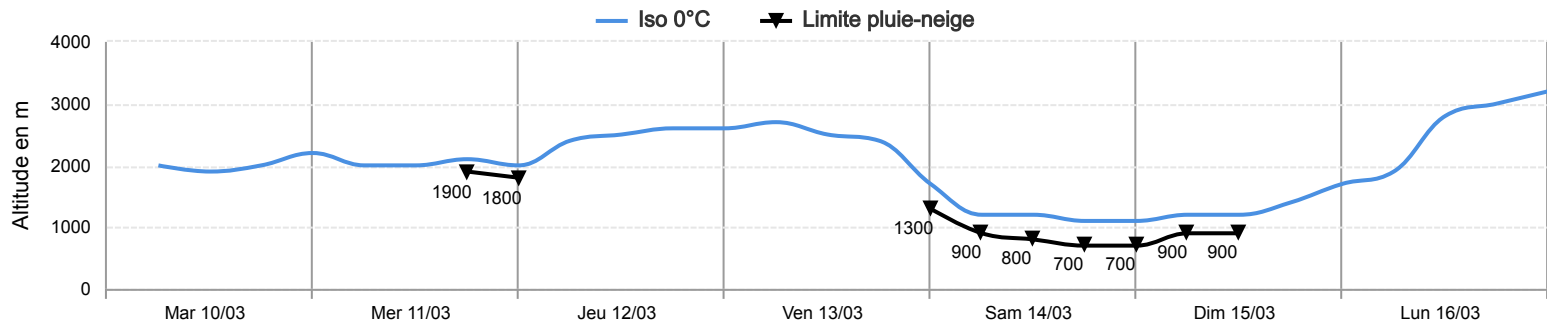

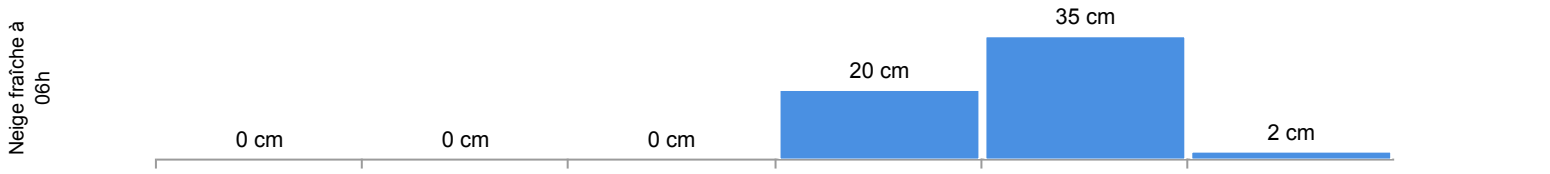

Risque d'avalanche	mar. 10/03	mer. 11/03	jeu. 12/03	ven. 13/03	sam. 14/03	dim. 15/03	lun. 16/03
	2	2	2	1	3	3	3

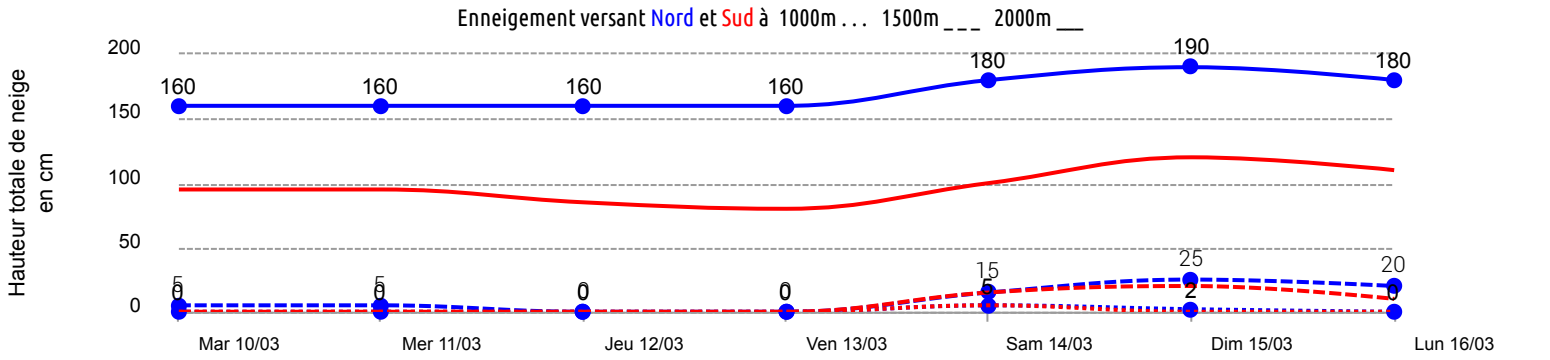

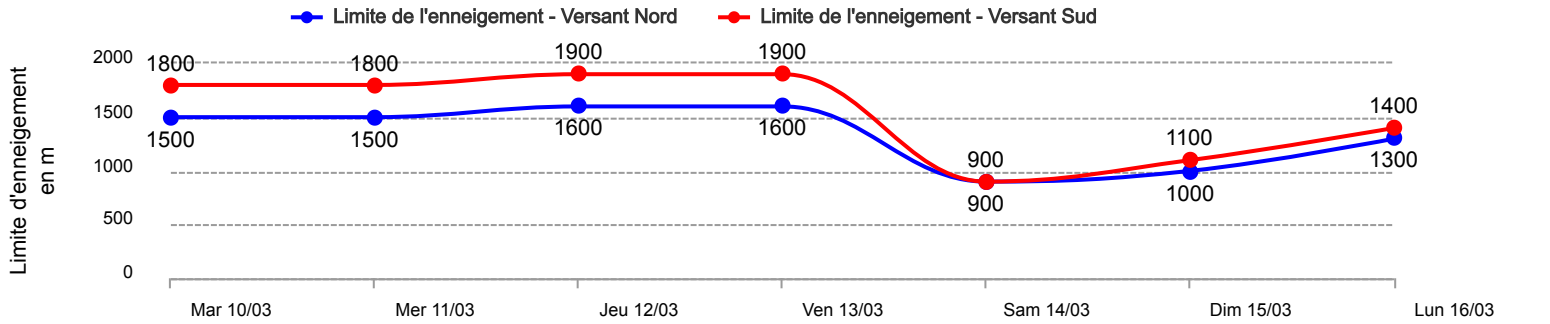

Pour consulter la vigilance en cours, veuillez vous rendre sur le site https://vigilance.meteofrance.fr/fr

Météo-France - 73 avenue de Paris, 94165 Saint-Mandé cedex - Contact : contact@meteo.fr

Rédigé par Météo-France avec la contribution des observateurs du réseau nivo-météorologiques. Partenariat : ANMSM (Maires de Stations de Montagne), DSF (Domaines Skiables de France), ADSP (Directeurs de Pistes et de la Sécurité des Stations de Sports d'Hiver) et autres acteurs de la montagne.

Bulletin neige & avalanches par téléphone au
0 892 68 10 20 Service 0,35 € / min + prix appel