RÉPUBLIQUE FRANÇAISE
Liberté Égalité Fraternité

METEO FRANCE
À VOS CÔTÉS, DANS UN CLIMAT QUI CHANGE

Bulletin d'estimation du risque d'avalanche
(valable en dehors des pistes balisées et ouvertes)
MASSIF : Renoso Incudine

Rédigé le lundi 16 mars 2026 à 16h

Estimation des risques pour le : MARDI 17 MARS

INSTABILITÉS EN ALTITUDE DANS LA NEIGE FRAICHE VENTÉE.

2

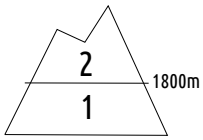

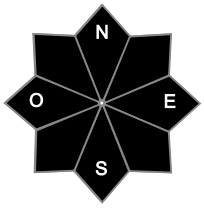

Au-dessus de 1800m indice de risque limité, plus bas indice faible.

Départs spontanés : Rares départs en neige humide dans les pentes ensoleillées

Déclenchements provoqués : Nombreuses plaques à vent en altitude au-dessus de 1800 m, risque de départs ponctuels sous les skis en neige humide

Indices de risque : 5 très fort - 4 fort - 3 marqué - 2 limité - 1 faible -- En noir : les pentes les plus dangereuses

Stabilité du manteau neigeux

Situation avalancheuse typique : neige ventée neige humide

Déclenchements provoqués : Le vent a soufflé dans toutes les directions pendant les récentes chutes de neige. Il a formé des plaques dures dans les pentes orientées Nord, Ouest et Sud, surtout au-dessus de 1800 m. Ces plaques reposent sur une couche fragile principalement composée de neige roulée, généralement déclenchables par forte surcharge. Elles engendrent des coulées ou avalanches de taille moyenne (taille 1 à 2). Toutefois, en pentes ombragées, une plaque peut encore être sensible au simple passage d'un randonneur ou skieur. En dessous de 1800 m, des départs ponctuels sont possibles sous les skis ou raquettes en neige humide, notamment dans les pentes raides et ensoleillées.
Départs spontanés : Dans les pentes Sud-Est à Sud-Ouest, quelques coulées ou avalanches de neige humide (taille 1 à 2) sont possibles dans les pentes raides bien ensoleillées.
Autres : Surfaces dures ou glacées aux abords des crêtes ventées.

Qualité de la neige

Qualification de l'enneigement : L'enneigement est excellent pour la saison au-dessus de 1600 m. Au Val d'Ese, on relève 2m00 de neige à 1800 m. À Ghisoni Capanelle, on mesure environ 3m00 dans les combes abritées.
Limite d'enneigement skiable : 1500 m.
État de la neige : Le manteau neigeux est recouvert d'une nouvelle couche de neige fraîche, 20 à 30 cm, localement plus dans les combes et secteurs abrités du vent. En moyenne montagne, la neige est souvent humide et collante. Elle n'est portante qu'au-dessus de 1800 m, où l'on trouve plus de surfaces en neige sèche, alternant avec de la neige roulée. Près des crêtes, la neige est fortement travaillée par le vent, avec de nombreuses **surfaces dures.** Des surfaces glacées peuvent persister dans certains couloirs raides ne voyant pas le soleil. Dans les pentes humidifiées par la douceur de la journée, une croûte de regel se forme durant la nuit. Dans les secteurs les plus ventés, la vieille neige colorée refait parfois son apparition.
À noter également la présence de **corniches parfois volumineuses**.

Aperçu météo pour le mardi 17 mars

	nuit	matin	après-midi	soir
Nuit claire, journée ensoleillée. Températures douces.				
Pluie-Neige				
Iso 0 °C	2 600 m	2 700 m	2 400 m	2 300 m
Vent 1500 m	↓ 10 km/h	↙ 10 km/h	← 5 km/h	↘ 5 km/h
Vent 2000 m	↙ 30 km/h	↙ 35 km/h	→ 5 km/h	↘ 10 km/h

Épaisseur de neige hors-piste

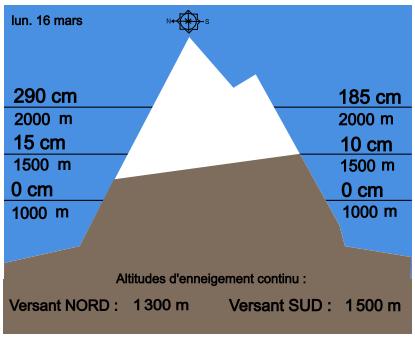

Précipitations à 1800 m

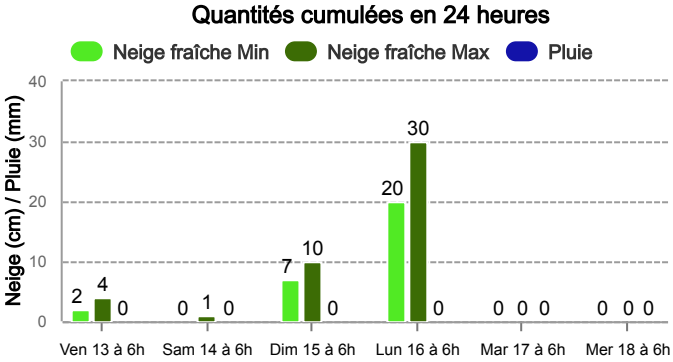

Tendance du mercredi 18 mars

2

Indice de risque limité

Net refroidissement mercredi avec de faibles chutes de neige à basse altitude. Maintien d'un risque limité.

Pour consulter la vigilance en cours, veuillez vous rendre sur le site https://vigilance.meteofrance.fr/fr

Météo-France - 73 avenue de Paris, 94165 Saint-Mandé cedex - Contact : contact@meteo.fr

Rédigé par Météo-France avec la contribution des observateurs du réseau nivo-météorologiques. Partenariat : ANMSM (Maires de Stations de Montagne), DSF (Domaines Skiables de France), ADSP (Directeurs de Pistes et de la Sécurité des Stations de Sports d'Hiver) et autres acteurs de la montagne.

Bulletin neige & avalanches par téléphone au
0 892 68 10 20 Service 0,35 € / min + prix appel

RÉPUBLIQUE FRANÇAISE
Liberté Égalité Fraternité

METEO FRANCE
À VOS CÔTÉS, DANS UN CLIMAT QUI CHANGE

Bulletin d'estimation du risque d'avalanche

(valable en dehors des pistes balisées et ouvertes)

MASSIF : Renoso Incudine

Rédigé le lundi 16 mars 2026 à 16h

Conditions nivo-météo des 7 derniers jours

	mar. 10/03				mer. 11/03				jeu. 12/03				ven. 13/03				sam. 14/03				dim. 15/03				lun. 16/03			
	03h	09h	15h	21h	03h	09h	15h	21h	03h	09h	15h	21h	03h	09h	15h	21h	03h	09h	15h	21h	03h	09h	15h	21h	03h	09h	15h	21h
Météo																												
Vent (km/h)	20	30	20	20	20	30	40	40	30	30	30	30	25	15	5	5	10	30	50	35	25	40	70	60	60	45	15	35
à 2000m																												
Vent (km/h)	15	20	15	10	15	20	30	20	30	20	25	15	20	20	15	10	10	20	50	45	45	40	65	45	50	40	10	15
à 1500m																												

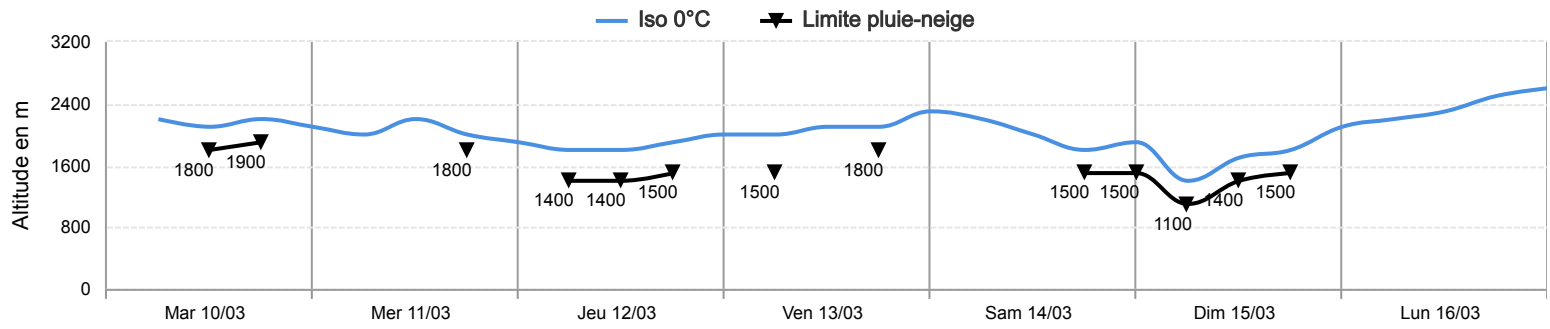

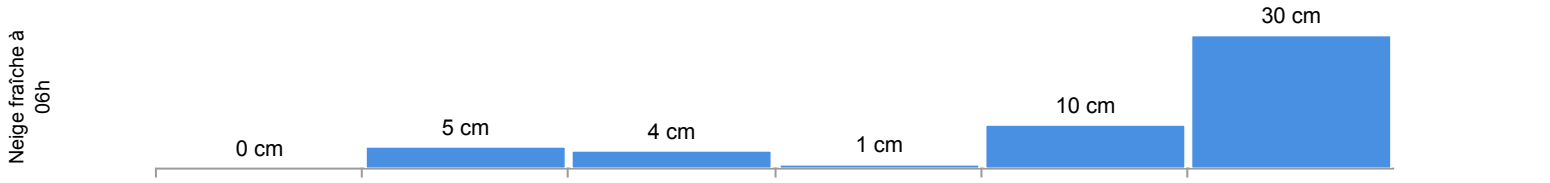

Risque d'avalanche	mar. 10/03	mer. 11/03	jeu. 12/03	ven. 13/03	sam. 14/03	dim. 15/03	lun. 16/03
	1	1	1	1	2	2	3

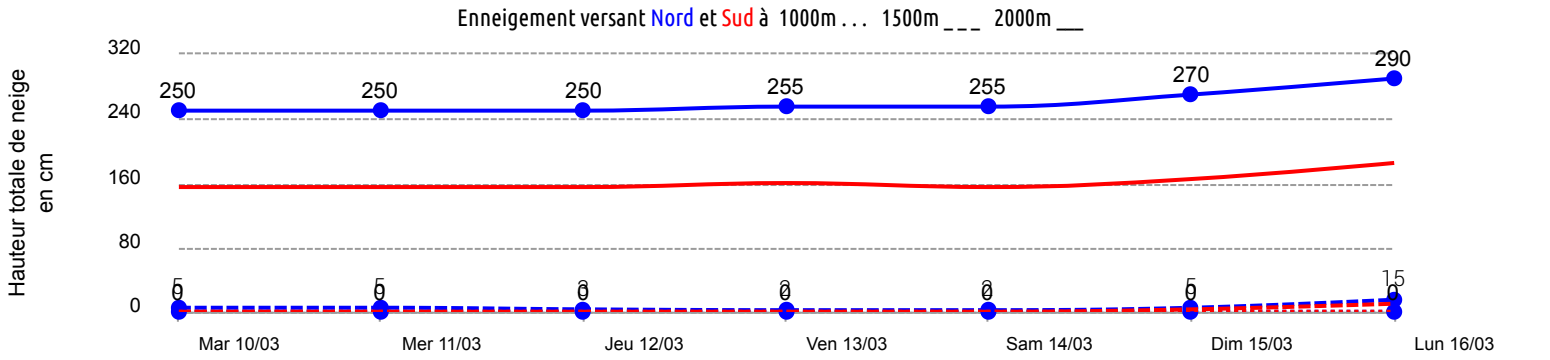

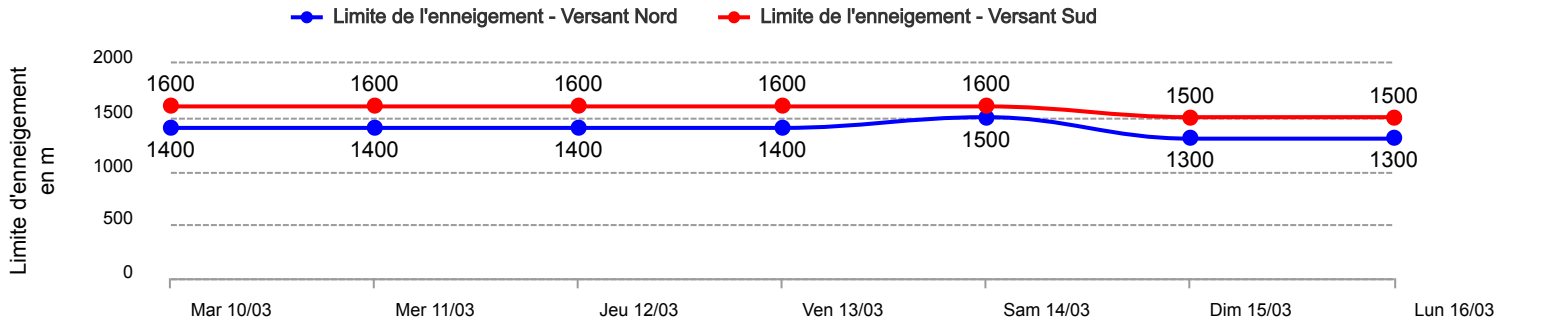

Pour consulter la vigilance en cours, veuillez vous rendre sur le site https://vigilance.meteofrance.fr/fr

Météo-France - 73 avenue de Paris, 94165 Saint-Mandé cedex - Contact : contact@meteo.fr

Rédigé par Météo-France avec la contribution des observateurs du réseau nivo-météorologiques. Partenariat : ANMSM (Maires de Stations de Montagne), DSF (Domaines Skiables de France), ADSP (Directeurs de Pistes et de la Sécurité des Stations de Sports d'Hiver) et autres acteurs de la montagne.

Bulletin neige & avalanches par téléphone au
0 892 68 10 20 Service 0,35 € / min + prix appel