RÉPUBLIQUE FRANÇAISE
Liberté Égalité Fraternité

METEO FRANCE
À VOS CÔTÉS, DANS UN CLIMAT QUI CHANGE

Bulletin d'estimation du risque d'avalanche
(valable en dehors des pistes balisées et ouvertes)

MASSIF : Ubaye

Rédigé le lundi 16 mars 2026 à 16h

Estimation des risques pour le : MARDI 17 MARS

QUELQUES PLAQUES EN DANS LA NEIGE RÉCENTE VENTÉE EN ALTITUDE - QUELQUES DÉPARTS NATURELS EN NEIGE HUMIDE.

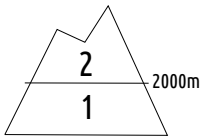

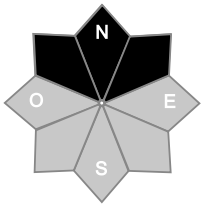

Au-dessus de 2000m indice de risque limité, plus bas indice faible.

Départs spontanés : départs en neige récente s'humidifiant au soleil.

Déclenchements provoqués : quelques plaques en ubacs d'altitude.

Indices de risque : 5 très fort - 4 fort - 3 marqué - 2 limité - 1 faible -- En noir : les pentes les plus dangereuses

Stabilité du manteau neigeux

Situation avalancheuse typique : neige ventée couche fragile persistante

Déclenchements provoqués :
plaques en place dans la neige récente ventée, principalement dans les ubacs au-dessus de 2000/2200 m, où la neige est restée froide. Ces plaques peuvent encore céder au passage d'un skieur malgré leur stabilisation progressive, et génèrent des avalanches de taille petite à moyenne. (taille 1 à 2). Plaques généralement durcies par le vent, mais parfois d'aspect poudreux dans les combes nord plus abrités.
Une rare grande avalanche est possible en ubacs, ou en haute altitude dans les autres orientations, si la surcharge d'une avalanche de surface provoque la rupture d'une couche fragile persistante enfouie en profondeur du manteau neigeux.
À plus basse altitude et en versant sud, manteau neigeux regelé et stable au levé du jour. Quelques départs sous les skis sont possibles au soleil dans les pentes fortement humidifiées, restants de petite taille.

Départs spontanés :
Peu probables en début de journée après un bon regel nocturne, puis avalanches de neige récente s'humidifiant au soleil au fil de la journée. Départs ponctuels de petite taille en pentes raides ensoleillées, rarement de taille moyenne en cas de cassure linéaire à proximité des crêtes.

Qualité de la neige

Enneigement proche des normales.
Données observées : 81 cm à la Nivôse de Restefond à 2550 m (secteur venté), 96 cm au-dessus de Larche à 2270 m en adret.

Enneigement skiable : vers 1500 m en ubacs, 1700/1900 m en adrets peu pentus.

État de la neige en surface : neige généralement croutée au levé du jour après un bon regel nocturne, s'humidifiant rapidement en journée au fil de l'ensoleillement. On retrouve de la neige froide encore légère ou densifiée par le vent en ubacs au-dessus de 2000/2200 m. Sur les crêtes, des corniches épaisses côtoient des zones dégarnies par le vent.

Aperçu météo pour le mardi 17 mars

	nuit	matin	après-midi	soir
Temps sec, doux et ensoleillé.				
Pluie-Neige				
Iso 0 °C	2 800 m	2 900 m	2 900 m	2 900 m
Vent 2000 m	← 10 km/h	↗ 10 km/h	→ 15 km/h	← 10 km/h
Vent 3000 m	↓ 25 km/h	↓ 20 km/h	↓ 20 km/h	↘ 20 km/h

Épaisseur de neige hors-piste

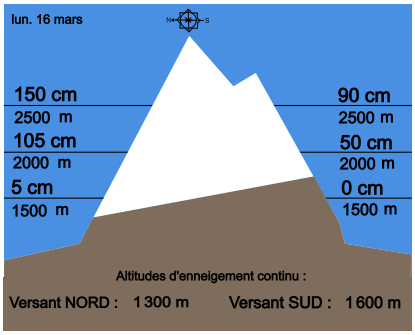

Précipitations à 1800 m

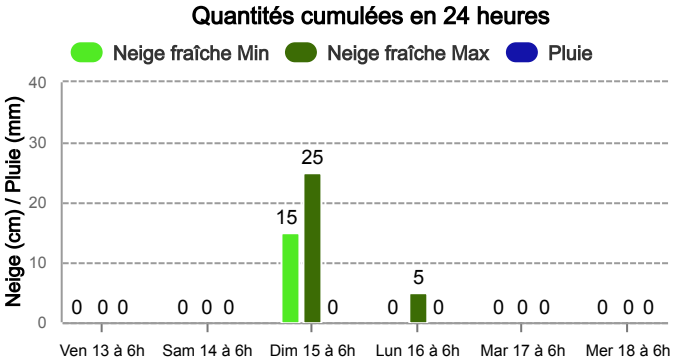

Tendance du mercredi 18 mars

Indice de risque limité

Plaques encore localement sensibles en ubacs d'altitude, entretenues par la lombarde qui se renforce de nouveau. Pas d'activité en neige humide.

Pour consulter la vigilance en cours, veuillez vous rendre sur le site https://vigilance.meteofrance.fr/fr

Météo-France - 73 avenue de Paris, 94165 Saint-Mandé cedex - Contact : contact@meteo.fr

Rédigé par Météo-France avec la contribution des observateurs du réseau nivo-météorologiques. Partenariat : ANMSM (Maires de Stations de Montagne), DSF (Domaines Skiables de France), ADSP (Directeurs de Pistes et de la Sécurité des Stations de Sports d'Hiver) et autres acteurs de la montagne.

Bulletin neige & avalanches par téléphone au
0 892 68 10 20 Service 0,35 € / min + prix appel

Bulletin d'estimation du risque d'avalanche

(valable en dehors des pistes balisées et ouvertes)

MASSIF : Ubaye

Rédigé le lundi 16 mars 2026 à 16h

Conditions nivo-météo des 7 derniers jours

	mar. 10/03				mer. 11/03				jeu. 12/03				ven. 13/03				sam. 14/03				dim. 15/03				lun. 16/03			
	03h	09h	15h	21h	03h	09h	15h	21h	03h	09h	15h	21h	03h	09h	15h	21h	03h	09h	15h	21h	03h	09h	15h	21h	03h	09h	15h	21h
Météo																												
Vent (km/h)	40	40	30	15	20	30	45	40	35	25	20	15	15	15	20	20	40	60	30	25	65	75	45	35	50	40	35	35
à 3000m																												
Vent (km/h)	15	10	5	5	5	10	20	15	15	15	15	10	10	10	20	10	15	30	20	15	20	40	20	10	15	20	25	15
à 2000m																												

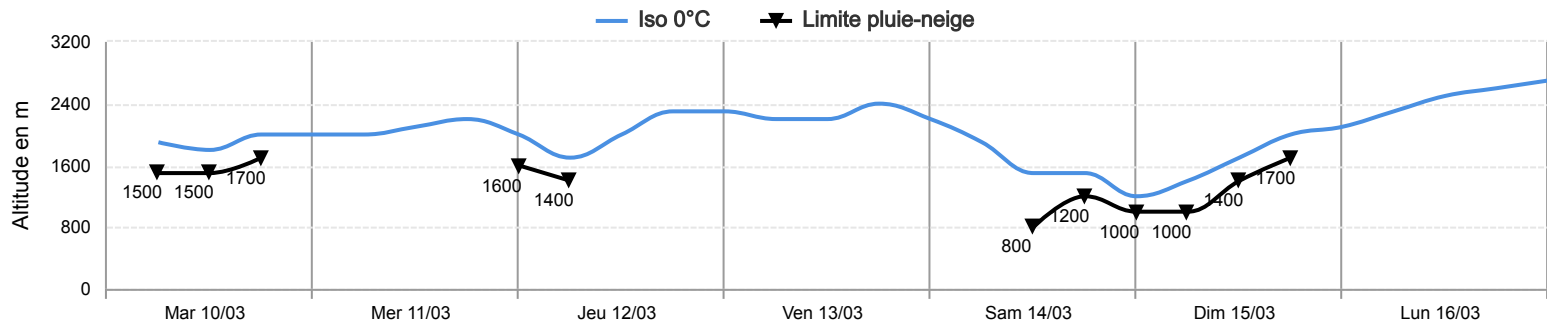

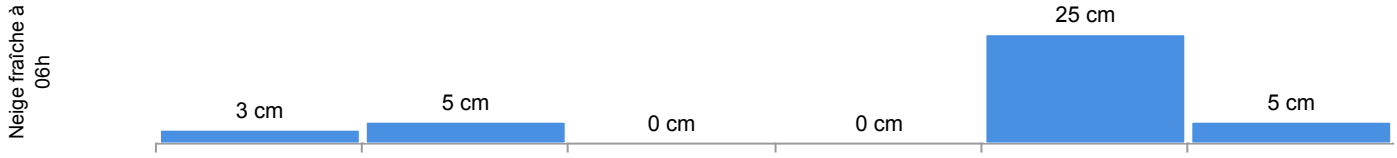

Risque d'avalanche	mar. 10/03	mer. 11/03	jeu. 12/03	ven. 13/03	sam. 14/03	dim. 15/03	lun. 16/03
	2	2	2	2	3	3	3

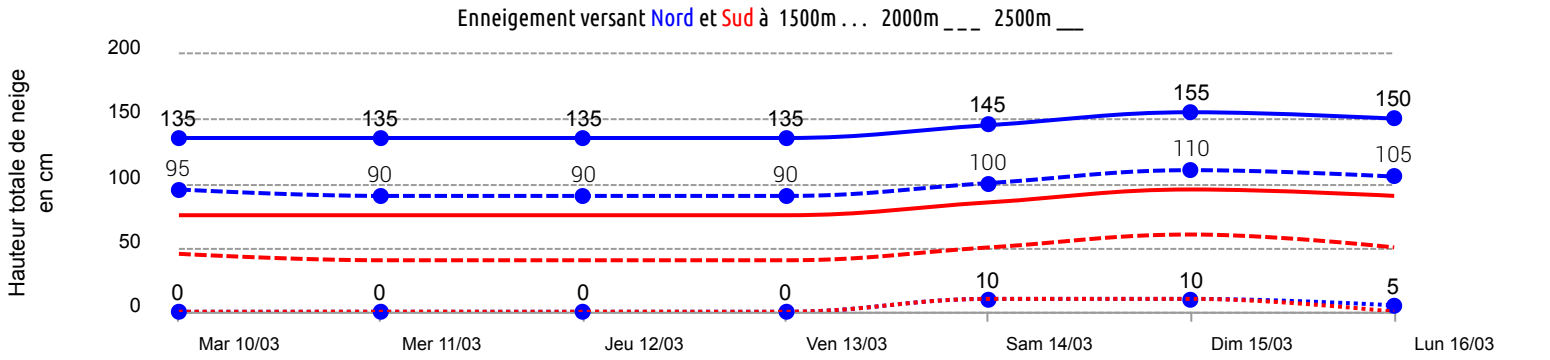

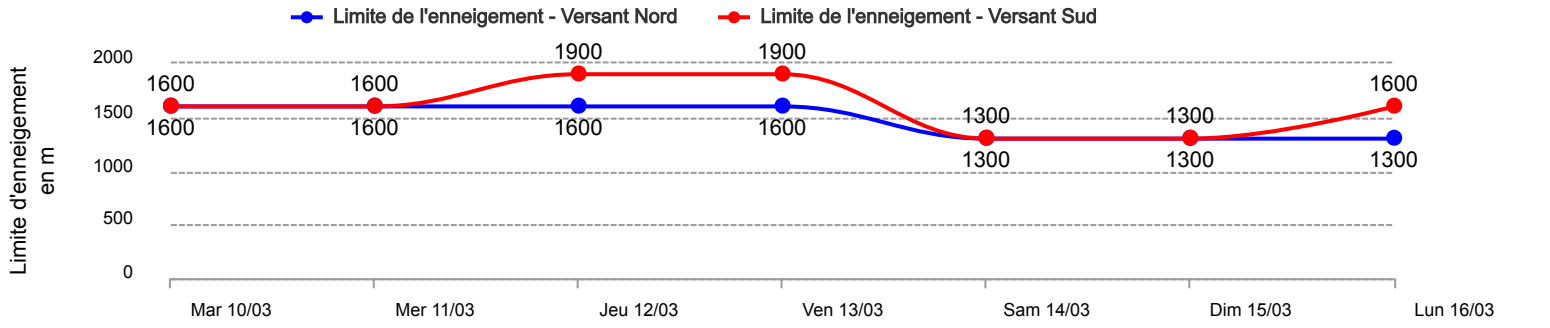

Pour consulter la vigilance en cours, veuillez vous rendre sur le site https://vigilance.meteofrance.fr/fr

Météo-France - 73 avenue de Paris, 94165 Saint-Mandé cedex - Contact : contact@meteo.fr

Bulletin neige & avalanches par téléphone au 0 892 68 10 20 Service 0,35 € / min + prix appel

Rédigé par Météo-France avec la contribution des observateurs du réseau nivo-météorologiques. Partenariat : ANMSM (Maires de Stations de Montagne), DSF (Domaines Skiables de France), ADSP (Directeurs de Pistes et de la Sécurité des Stations de Sports d'Hiver) et autres acteurs de la montagne.