RÉPUBLIQUE FRANÇAISE
Liberté Égalité Fraternité

METEO FRANCE
À VOS CÔTÉS, DANS UN CLIMAT QUI CHANGE

Bulletin d'estimation du risque d'avalanche

(valable en dehors des pistes balisées et ouvertes)

MASSIF : Capcir Puymorens

Rédigé le lundi 16 mars 2026 à 17h

Estimation des risques pour le : MARDI 17 MARS

NOMBREUSES PLAQUES EN ALTITUDE DANS LES SECTEURS OMBRAGÉS; HUMIDIFICATION AU SOLEIL

3

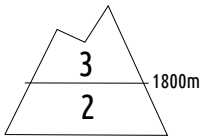

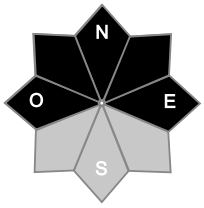

plaques en nord

Au-dessus de 1800m indice de risque marqué, plus bas indice limité.

Départs spontanés : Poursuite de l'humidification dans les secteurs ensoleillés

Déclenchements provoqués : Nombreuses plaques encore facilement déclenchables dans la neige récente

Indices de risque : 5 très fort - 4 fort - 3 marqué - 2 limité - 1 faible -- En noir : les pentes les plus dangereuses

Stabilité du manteau neigeux

Situation avalancheuse typique : neige ventée neige humide

Déclenchements provoqués :
Dans les secteurs ombragés, au-dessus de 1800m, de nombreuses structures de plaques facilement déclenchables dans la neige récente sont encore présentes. Elles sont en cours de stabilisation mais sont encore susceptibles de produire des avalanches de taille 1 à 2. Elles se sont formées ce week-end par un vent violent et tourbillonnant. Ces plaques se situent parfois loin des crêtes, sont plutôt dures dans les zones ventées, plutôt friables dans des zones un peu plus protégées. La couche fragile est majoritairement constituée de neige fraiche moins ventée, voire de neige roulée tombée par endroits en abondance dans la nuit de samedi à dimanche. Localement, il est possible que des grains facettés ou du givre de surface formés lors des nuits claires de la semaine dernière puissent aussi jouer ce rôle. Dans les secteurs ensoleillés ainsi qu'en toute orientation sous 1800m, le risque de déclenchement est moindre par le tassement de la couche de neige.
(Observables : traces d'avalanches récentes, fissures sous les skis, affaissement accompagné de 'whoomf', signes de transport par le vent)

Départs spontanés :
Dans les pentes est, sud puis ouest chauffées par le soleil de mars, des départs ponctuels sont possibles, causés par la poursuite de l'humidification de la couche de neige récente. Avalanches de surface de taille 1 à 2 attendues. Un départ linéaire causé par l'humidification d'une sous-couche fragile est possible. Une rare avalanche de taille 3 est alors possible.
(Observables : neige très humide, gorgée d'eau; enfoncement important)

Autres :
Les fissures ou gueules de baleine reportées la semaine passée en bon nombre d'endroits, parfois de profondeur imposante, peuvent être masquées sans être complètement comblées par les chutes de neige de ce week-end.

Qualité de la neige

Enneigement :
Après plusieurs hivers déficitaires, l'enneigement sur le massif est cette année largement excédentaire. Une trentaine de centimètres sont tombés en altitude ce week-end, très hétérogènes à cause du vent. La fonte débute avec le redoux en cours.

Limites skiables :
Mardi matin, on pourra envisager de chausser les skis vers 1200/1300m en terrain herbeux en nord, mais sans véritable sous-couche en dessous de 1500m en versants froids, 1800/1900m en versants sud.

État de la neige :
Neige restée froide et légère à l'ombre et en altitude. Bon regel matinal là où le soleil de ce lundi a chauffé et sous 1800m. Dans les secteurs ombragés ou peu pentus, la neige sera frittée à cartonnée près des crêtes, cols et sommets, restant meuble à l'abri du vent (clairières et combes déventées notamment). Elle s'humidifiera en surface avec le soleil en journée dans les pentes voyant le soleil ainsi qu'en toute orientation sous 1800/2000m.

Aperçu météo pour le mardi 17 mars

	nuit	matin	après-midi	soir
Grand beau, douceur				
Pluie-Neige				
Iso 0 °C	3 000 m	3 200 m	3 200 m	3 300 m
Vent 2000 m	30 km/h	15 km/h	15 km/h	10 km/h
Vent 3000 m	40 km/h	20 km/h	10 km/h	10 km/h

Pour consulter la vigilance en cours, veuillez vous rendre sur le site https://vigilance.meteofrance.fr/fr

Météo-France - 73 avenue de Paris, 94165 Saint-Mandé cedex - Contact : contact@meteo.fr

Rédigé par Météo-France avec la contribution des observateurs du réseau nivo-météorologiques. Partenariat : ANMSM (Maires de Stations de Montagne), DSF (Domaines Skiables de France), ADSP (Directeurs de Pistes et de la Sécurité des Stations de Sports d'Hiver) et autres acteurs de la montagne.

Bulletin neige & avalanches par téléphone au
0 892 68 10 20 Service 0,35 € / min + prix appel

Bulletin d'estimation du risque d'avalanche

(valable en dehors des pistes balisées et ouvertes)

MASSIF : Capcir Puymorens

Rédigé le lundi 16 mars 2026 à 17h

Épaisseur de neige hors-piste

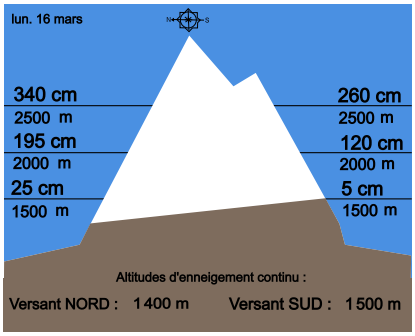

Précipitations à 1800 m

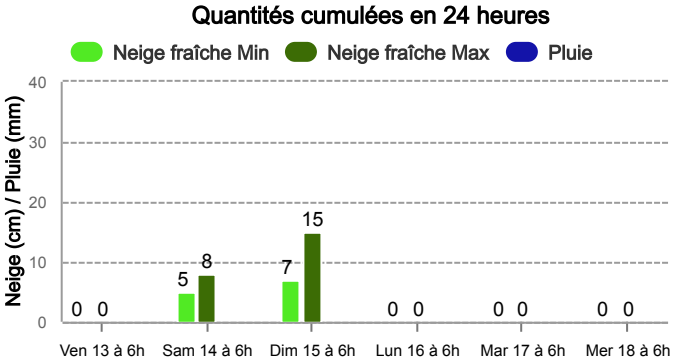

Tendance du mercredi 18 mars

Indice de risque marqué

Persistance de structures de plaques, en cours de stabilisation

Pour consulter la vigilance en cours, veuillez vous rendre sur le site https://vigilance.meteofrance.fr/fr

Météo-France - 73 avenue de Paris, 94165 Saint-Mandé cedex - Contact : contact@meteo.fr

Rédigé par Météo-France avec la contribution des observateurs du réseau nivo-météorologiques. Partenariat : ANMSM (Maires de Stations de Montagne), DSF (Domaines Skiables de France), ADSP (Directeurs de Pistes et de la Sécurité des Stations de Sports d'Hiver) et autres acteurs de la montagne.

Bulletin neige & avalanches par téléphone au

0 892 68 10 20 Service 0,35 € / min + prix appel

Bulletin d'estimation du risque d'avalanche

(valable en dehors des pistes balisées et ouvertes)

MASSIF : Capcir Puymorens

Rédigé le lundi 16 mars 2026 à 17h

Conditions nivo-météo des 7 derniers jours

	mar. 10/03				mer. 11/03				jeu. 12/03				ven. 13/03				sam. 14/03				dim. 15/03				lun. 16/03			
	03h	09h	15h	21h	03h	09h	15h	21h	03h	09h	15h	21h	03h	09h	15h	21h	03h	09h	15h	21h	03h	09h	15h	21h	03h	09h	15h	21h
Météo																												
Vent (km/h)	15	15	20	15	15	25	40	55	40	30	25	25	25	25	30	40	50	50	55	70	95	120	85	65	75	60	60	35
à 3000m																												
Vent (km/h)	5	5	10	10	10	10	25	35	30	20	15	15	15	15	15	25	30	30	35	45	75	100	80	50	60	50	40	30
à 2000m																												

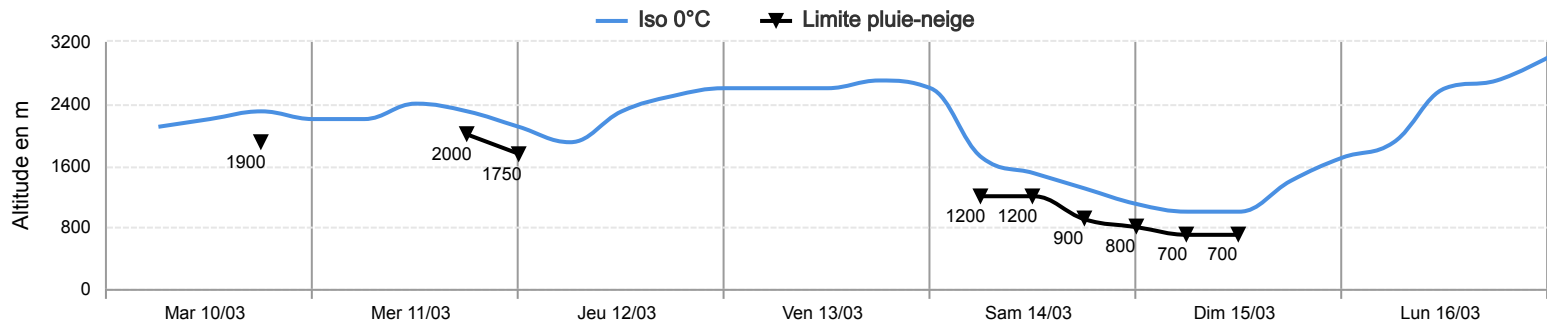

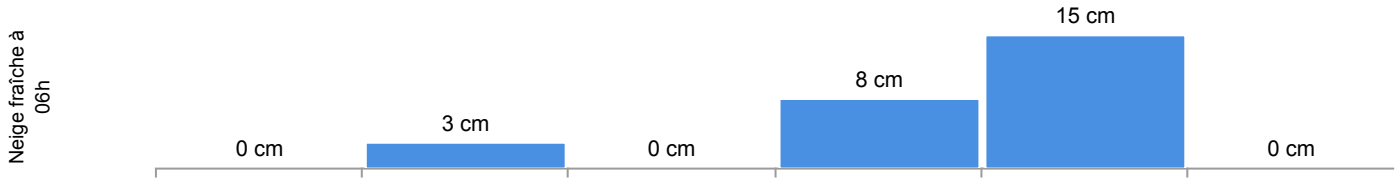

Risque d'avalanche	mar. 10/03	mer. 11/03	jeu. 12/03	ven. 13/03	sam. 14/03	dim. 15/03	lun. 16/03
	2	2	2	2	3	3	3

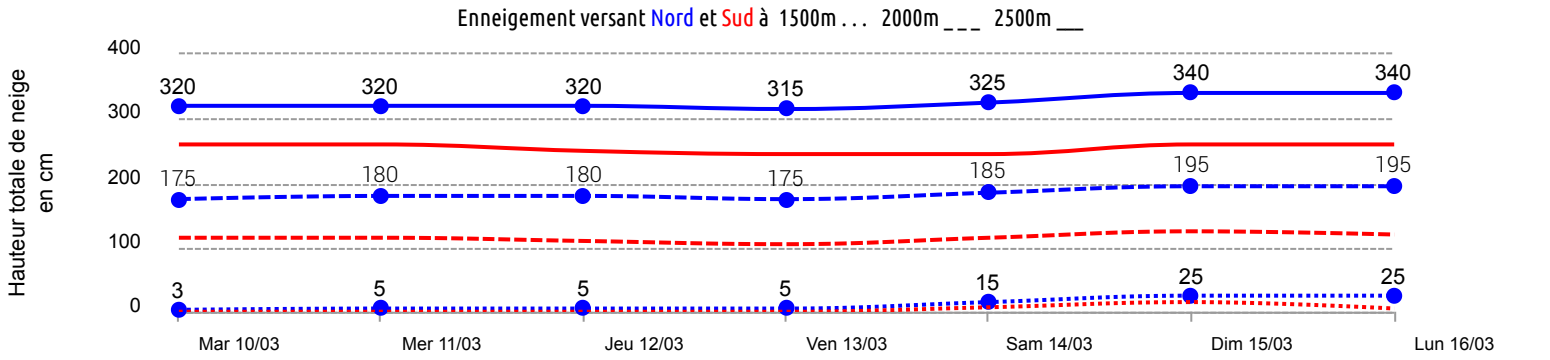

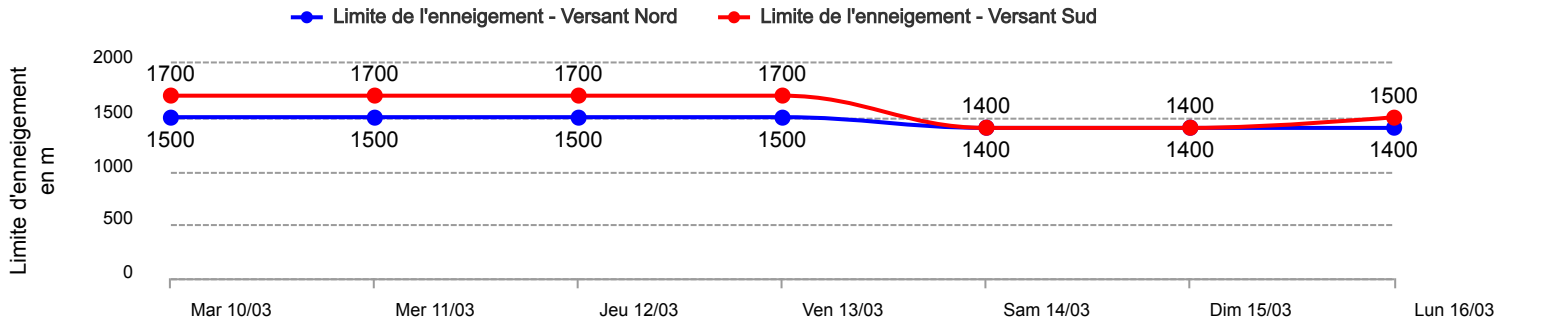

Pour consulter la vigilance en cours, veuillez vous rendre sur le site https://vigilance.meteofrance.fr/fr

Météo-France - 73 avenue de Paris, 94165 Saint-Mandé cedex - Contact : contact@meteo.fr

Bulletin neige & avalanches par téléphone au

0 892 68 10 20 Service 0,35 € / min + prix appel

Rédigé par Météo-France avec la contribution des observateurs du réseau nivo-météorologiques. Partenariat : ANMSM (Maires de Stations de Montagne), DSF (Domaines Skiables de France), ADSP (Directeurs de Pistes et de la Sécurité des Stations de Sports d'Hiver) et autres acteurs de la montagne.