GOBIERNO DE ESPAÑA
VICEPRESIDENCIA TERCERA DEL GOBIERNO
MINISTERIO PARA LA TRANSICIÓN ECOLÓGICA Y EL RETO DEMOGRÁFICO

Boletín de información nivológica y de peligro de aludes

Pirineo Navarro y Aragonés

aemet Agencia Estatal de Meteorología

martes, 17 de marzo de 2026

Pronóstico hasta las 24 horas del miércoles, día 18 de marzo

(Válido fuera de pistas de esquí balizadas y abiertas)

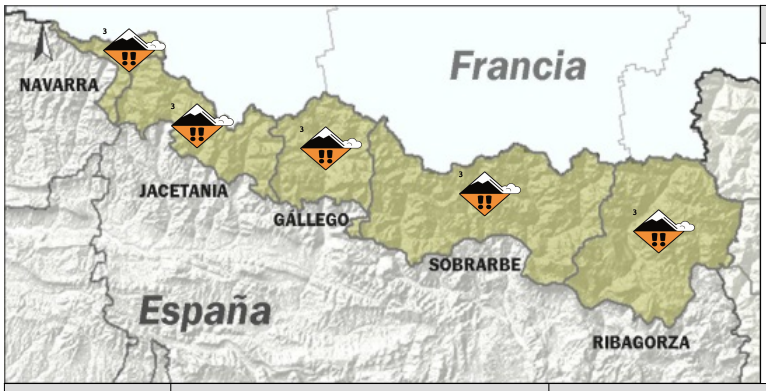

Problemas de aludes

Nieve húmeda

Placas de viento

Macizo	Peligro	Problemas de aludes, cota, orientación, tamaño	Innivación observada (m)
Navarra	3 — 3 / 2 — 2200 — Notable	Nieve húmeda: 2 — N, O, E, S Placas de viento: 3 — 2200 — N, O, E, S	2026-03-17 N / S Cota más baja caras N
Jacetania	3 — 3 / 2 — 2200 — Notable	Nieve húmeda: 2 — N, O, E, S Placas de viento: 3 — 2200 — N, O, E, S	2026-03-17 N / S Cota más baja caras N
Gállego	3 — 3 / 2 — 2200 — Notable	Nieve húmeda: 2 — N, O, E, S Placas de viento: 3 — 2200 — N, O, E, S	2026-03-17 N / S Cota más baja caras N

AEMET. Se autoriza la reproducción de su contenido citando la fuente.

Boletín de información nivológica y de peligro de aludes

Pirineo Navarro y Aragonés

Sobrarbe	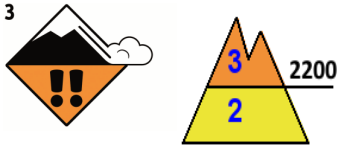 **Notable**	**Nieve húmeda** 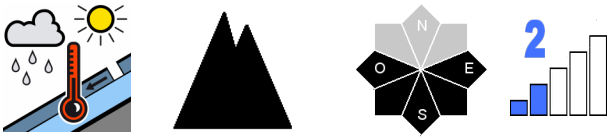 **Placas de viento** 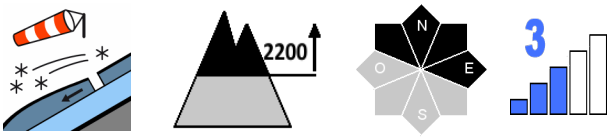	2026-03-17 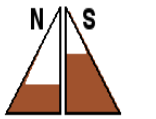 Cota más baja caras N
Ribagorza	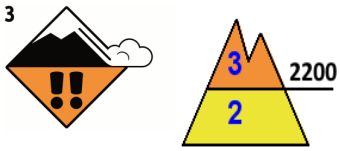 **Notable**	**Nieve húmeda** **Placas de viento** 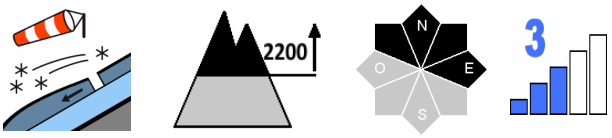	2026-03-17 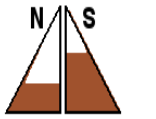 Cota más baja caras N

Estado del manto y observaciones recientes

Las nevadas y el frío del fin de semana han dado paso a días de cielos despejados, mayor insolación y ascenso de las temperaturas. En solanas y en umbrías de cotas medias y bajas el manto se está humidificando, en un ciclo de fusión diurna y rehielo nocturno. Los espesores van menguando algunos centímetros al día, y la cubierta de nieve es más o menos continua a partir de los 1400-1600 metros en umbrías, 1600-1800 metros en solanas. Los espesores son mayores en el sector occidental que en el oriental, aunque ambos estan por encima de lo que cabría esperar a estas alturas de la temporada en medianías y cotas altas. A unos 1800 metros se alcanzan los 80-140 cm y a 2100 metros los 120-210 cm, aún más en ventisqueros, hoyas y otras zonas propensas a la acumulación.

Hoy en superficie el manto ha amanecido bien encostrado pero ha transformado rápido con la insolación. Se aprecia la alternancia de zonas de acumulación venteadas y con sastruguis junto con otras muy erosionadas por el viento donde afloran capas de la antigua costra marrón y nieve vieja. Las capas de nieve reciente han asentado salvo en las umbrías de la alta montaña, incluidas algunas laderas E y W, donde pueden permanecer frágiles y fracturar ante esfuerzos moderados. En umbrías por encima de 2200 metros a resguardo del viento y cerca de crestas y collados, las placas de viento se mantienen reactivas y descansan sobre estratos de granos facetados y escarcha de la semana pasada, así como algunos débiles persistentes a mayor profundidad que permanecen latentes.

En las últimas 24h se ha observado actividad natural y accidental de aludes de tamaños hasta grandes en umbrías de cotas altas y zonas protegidas de los fuertes vientos del domingo. También algunas purgas de nieve húmeda en solanas de cotas medias y altas de dimensión pequeña y mediana.

AEMET. Se autoriza la reproducción de su contenido citando la fuente.

Evolución del manto y peligro de aludes para el miércoles, día 18

Problema de nieve húmeda. Problema de placas de viento y capas débiles persistentes en cotas altas.

Mañana continuará la humidificación del manto, especialmente en solanas y en umbrías de poca inclinación. Serán pues probables las purgas o aludes medianos (capaz de enterrar a una persona) de nieve húmeda tras la fusión del rehielo nocturno. Tampoco se descartan algunos deslizamientos basales en las áreas herbosas o de roca lisa de todas las orientaciones.

En zonas de acumulación de las umbrías y cerca de crestas y collados por encima de 2200 metros, se podrán mantener inestables las placas de viento, que descansan sobre capas débiles de nieve reciente o de facetas y escarcha formadas la semana pasada en umbrías. Ante una sobrecarga débil (paso de un esquiador) u ocasionalmente de manera natural podrán desencadenarse y provocar aludes de tamaño mediano o incluso grande (capaz de enterrar un coche), especialmente si se activan capas débiles persistentes más profundas.

Predicción meteorológica para el miércoles, día 18

Poco nuboso o despejado. A media tarde tenderá a aumentar la nubosidad baja progresivamente por el este. No se descartan algunas precipitaciones débiles y dispersas a últimas horas en la mitad oriental. Cota de nieve en torno a 2100 metros. Temperaturas sin cambios o con algunos cambios ligeros, con las mínimas en ascenso y las máximas en descenso. Heladas débiles en cotas altas. Viento flojo de dirección variable, tendiendo a moderado del sureste al final del día.

Datos en la atmósfera libre:

Altitud de la isoterma de 0 ºC: 3200 m
Altitud de la isoterma de -10 ºC: 4600 m

Viento a 1500 m: VRB 5 km/h
Viento a 3000 m: E 10 km/h

Evolución para el jueves día 19

Problema de nieve húmeda en ligero descenso. Continuación de los problemas de placas de viento y capas débiles persistentes en umbrías de cotas altas.

(Información elaborada a partir de los datos recibidos de los refugios de Linza, Lizara, Panticosa, Bachimaña, Góriz, Pineta, Estós, Angel Orús, La Renclusa y Belagua, de las estaciones de esquí de Astún y Formigal y de Ordesa Pradera)

Escala europea de peligro de aludes

Débil | Limitado | Notable | Fuerte | Muy Fuerte

Problemas de aludes

Nieve reciente | Placas de viento | Capas débiles persistentes | Nieve húmeda | Deslizamientos basales | Sin problema evidente

Nota1: Se recuerda que, siempre que haya nieve, la ausencia total de peligro no existe. Hay que tener presente que en circunstancias desfavorables, con aludes de tamaño 1 (alud pequeño o colada) y tamaño 2 (alud mediano), se pueden sufrir severos daños personales.

Nota2: Los BPA se elaboran en base a información meteorológica así como al estado del manto nivoso a través de sondeos puntuales. Se advierte a los usuarios de la variabilidad de esta información al extrapolarla a zonas extensas de montaña. Por ello, AEMET no se hace responsable de su uso para la toma de decisiones que conciernen a la seguridad personal, ni de los riesgos físicos o materiales de ellas

AEMET. Se autoriza la reproducción de su contenido citando la fuente.

derivadas.

AEMET. Se autoriza la reproducción de su contenido citando la fuente.