ICGC Institut Cartogràfic i Geològic de Catalunya

Servei Meteorològic de Catalunya meteo.cat

Boletín de peligro de aludes para el Pirineo de Catalunya
Del 17/03/2026 al 18/03/2026

(Válido fuera pistas de esquí y zonas no controladas)

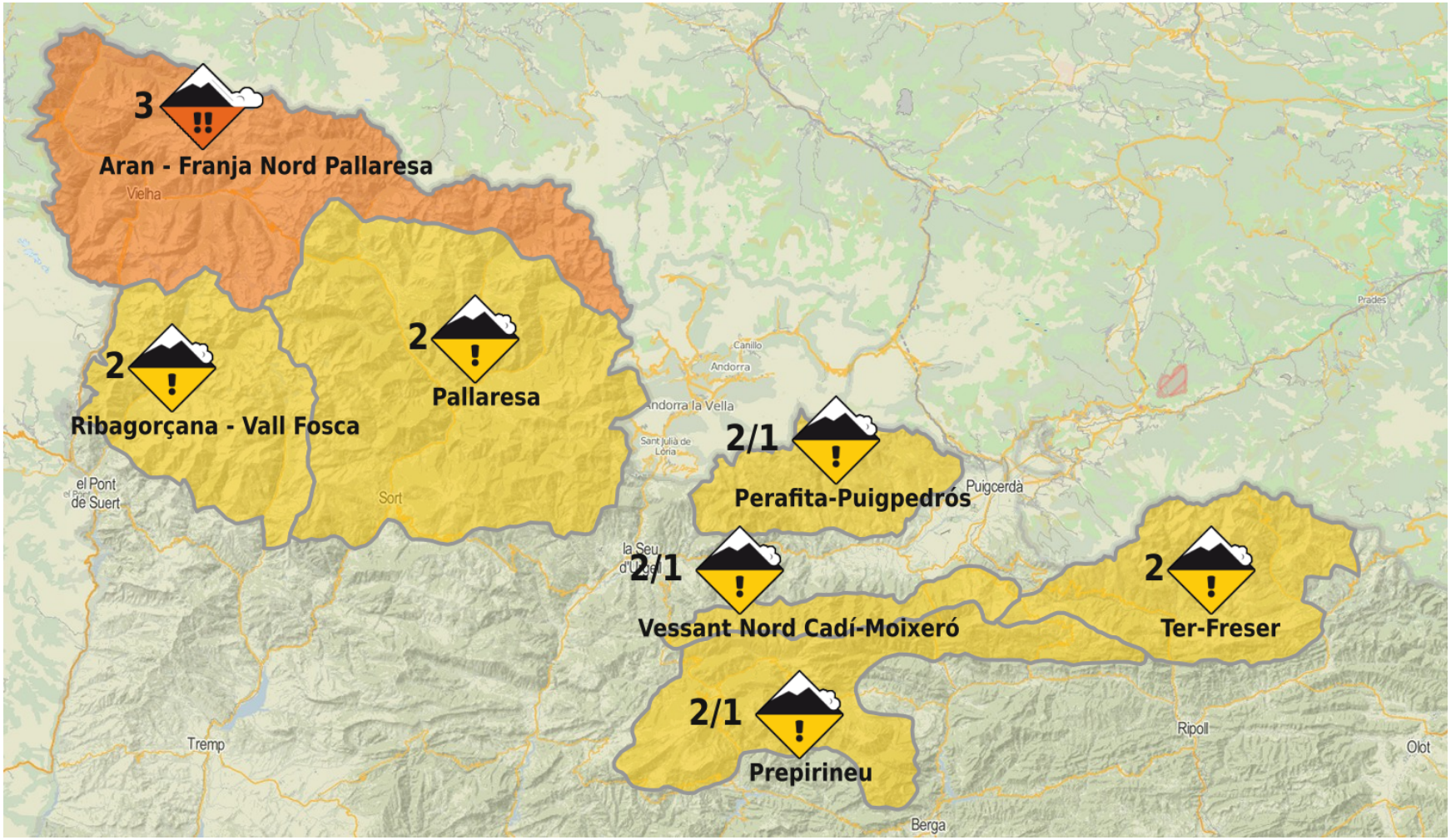

5 MUY FUERTE	4 FUERTE	3 NOTABLE	2 LIMITADO	1 DÉBIL

ICGC Institut Cartogràfic i Geològic de Catalunya

Servei Meteorològic de Catalunya

Boletín de peligro de aludes Aran - Franja Nord Pallaresa Del 17/03/2026 al 18/03/2026

(Válido fuera pistas de esquí y zonas no controladas)

NOTABLE (3)

Situación primaria

Capas débiles persistentes

Distribución

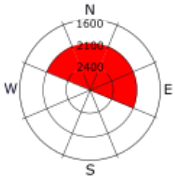

Tamaño

Origen

Tendencia

Situación secundaria

Nieve húmeda

Distribución

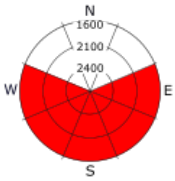

Tamaño

Origen

Tendencia

Estado del manto nivoso

Las placas de viento formadas durante el fin de semana permanecen sobre niveles débiles formados por facetas, escarcha y nieve granulada. Se ha visto actividad natural y también al paso de esquiadores, y al circular por el terreno se escuchan woumfs y aparecen grietas. Los test de estabilidad dan fracturas y propagaciones. Hay que prestar atención ya que podemos desencadenar fácilmente placas, especialmente por encima de los 2.100 m, a orientación NW, N, NE y E. La rotura de las placas y su desencadenamiento pueden dar lugar a aludes de tamaño medio, con capacidad de enterrarnos, o incluso de tamaño 3 (grande), suficiente para enterrar un grupo, en vertientes umbrías protegidas del viento y bajo collados y cordales. Con el aumento de la temperatura y la radiación solar intensa, son probables también aludes de nieve húmeda, a partir de mediodía, incluso de tamaño 2 (medio), sobre todo por debajo de los 2.400 a 2.500 m en las solanas.

Distribución del manto nivoso

Hay nieve por encima de unos 1.400-1-500 m en umbrías y 1.700 m en solanas. Los espesores a unos 2.200 m son superiores a los normales en la Franja Norte de la Pallaresa y en la mitad sur del Aran donde rondan los 180-220 cm. En la mitad norte de Arán hay unos 120-140 cm de grosor total.

Tendencia para las próximas 48-72h

Leve descenso de los problemas por nieve húmeda debido al descenso térmico. Continuaremos con las capas débiles persistentes en umbrías. Peligro: SIN CAMBIOS

El próximo boletín será emitido el día 2026-03-18

5 MUY FUERTE	4 FUERTE	3 NOTABLE	2 LIMITADO	1 DÉBIL

EAWS EUROPEAN AVALANCHE WARNING SERVICES

ICGC Institut Cartogràfic i Geològic de Catalunya

Servei Meteorològic de Catalunya

Boletín de peligro de aludes Ribagorçana - Vall Fosca Del 17/03/2026 al 18/03/2026

(Válido fuera pistas de esquí y zonas no controladas)

LIMITADO (2)

Situación primaria

Nieve húmeda

Distribución

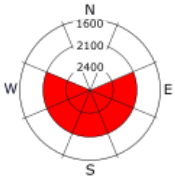

Tamaño

Origen

Tendencia

Situación secundaria

Capas débiles persistentes

Distribución

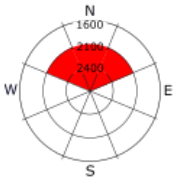

Tamaño

Origen

Tendencia

Estado del manto nivoso

Para el martes esperamos problemas relacionados con la nieve húmeda y la presencia de niveles débiles enterrados. Pese a que de madrugada y primera las costras son portantes y resistentes, con la insolación y el ascenso térmico se transformará el manto más superficial. Pueden caer aludes de fusión de forma natural, en solanas que llegarán a tamaño 1(pequeño), sin capacidad para enterrar a una persona. El terreno más afectado por aludes de fusión son las salidas de puntos oscuros (rocas y árboles) y las orientaciones este, sur y oeste. Las placas de viento formadas durante el fin de semana permanecen sobre niveles débiles (facetas o nieve granulada) y pueden caer a nuestro paso. Los lugares peligrosos están bajo collados y cordales, por encima de 2.500 m y también las orientaciones umbrías resguardadas a N, NE y NW, entre 2200 y 2400 m. Las placas, en caso de romperse, podrán generar aludes de tamaño 2 (medio), con capacidad para enterrar un montañero.

Distribución del manto nivoso

Hay nieve en el suelo a 1.600 m en terreno umbrío, y por encima de unos 1.800 m en laderas soleadas. El manto es esquiable por encima de unos 1.800-1.900 m en umbrías. Los grosores alcanzan los 105-135 cm a unos 2.200 m. Estos valores son superiores a los normales para la época.

Tendencia para las próximas 48-72h

Leve descenso de los problemas por nieve húmeda debido al descenso térmico. Continuaremos con las capas débiles persistentes en umbrías. Peligro: SIN CAMBIOS

El próximo boletín será emitido el día 2026-03-18

5 MUY FUERTE	4 FUERTE	3 NOTABLE	2 LIMITADO	1 DÉBIL

EAWS EUROPEAN AVALANCHE WARNING SERVICES

ICGC Institut Cartogràfic i Geològic de Catalunya

Servei Meteorològic de Catalunya meteo.cat

Boletín de peligro de aludes Pallaresa
Del 17/03/2026 al 18/03/2026

(Válido fuera pistas de esquí y zonas no controladas)

LIMITADO (2)

Situación primaria

Nieve húmeda

Distribución

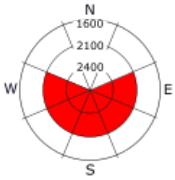

Tamaño

Origen

Tendencia

Situación secundaria

Capas débiles persistentes

Distribución

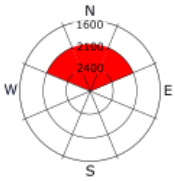

Tamaño

Origen

Tendencia

Estado del manto nivoso

Para el martes esperamos problemas relacionados con la nieve húmeda y la presencia de niveles débiles enterrados. Pese a que de madrugada y primera las costras son portantes y resistentes, con la insolación y el ascenso térmico se transformará el manto más superficial. Pueden caer aludes de fusión de forma natural, en solanas que llegarán a tamaño 1 (pequeño), sin capacidad para enterrar a una persona. El terreno más afectado por aludes de fusión son las salidas de puntos oscuros (rocas y árboles) y las orientaciones este, sur y oeste. Las placas de viento formadas durante el fin de semana permanecen sobre niveles débiles (facetas o nieve granulada) y pueden caer a nuestro paso. Los lugares peligrosos están bajo collados y cordales, por encima de 2.500 m y también las orientaciones umbrías resguardadas a N, NE y NW, entre 2200 y 2400 m. Las placas, en caso de romperse, podrán generar aludes de tamaño 2 (medio), con capacidad para enterrar un montañero.

Distribución del manto nivoso

Hay nieve en el suelo a 1.600 m en N, y a 1.800-1.900 m en S. El manto es esquiable por encima de unos 1.800-1.900 m en umbrías. Los espesores alcanzan los 115-155 cm en cotas medias, variable según los efectos del viento.

Tendencia para las próximas 48-72h

Leve descenso de los problemas por nieve húmeda debido al descenso térmico. Continuaremos con las capas débiles persistentes en umbrías. Peligro: SIN CAMBIOS

El próximo boletín será emitido el día 2026-03-18

5 MUY FUERTE	4 FUERTE	3 NOTABLE	2 LIMITADO	1 DÉBIL

EAWS EUROPEAN AVALANCHE WARNING SERVICES

ICGC Institut Cartogràfic i Geològic de Catalunya

Servei Meteorològic de Catalunya

Boletín de peligro de aludes Perafita-Puigpedrós Del 17/03/2026 al 18/03/2026

(Válido fuera pistas de esquí y zonas no controladas)

LIMITADO (2), a partir de mediodía.
DÉBIL (1), por la mañana.

Situación primaria

Nieve húmeda

Distribución

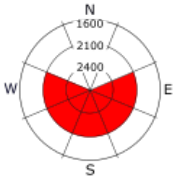

Tamaño

Origen

Tendencia

Situación secundaria

Capas débiles persistentes

Distribución

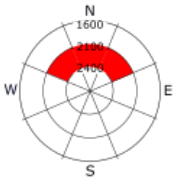

Tamaño

Origen

Tendencia

Estado del manto nivoso

Para el martes esperamos problemas relacionados con la nieve húmeda y la presencia de niveles débiles enterrados. Pese a que de madrugada y primera las costras son portantes y resistentes, con la insolación y el ascenso térmico se transformará el manto más superficial. Pueden caer aludes de fusión de forma natural, en solanas que llegarán a tamaño 1 (pequeño), sin capacidad para enterrar a una persona. El terreno más afectado por aludes de fusión son las salidas de puntos oscuros (rocas y árboles) y las orientaciones este, sur y oeste. Las placas de viento formadas durante el fin de semana permanecen sobre niveles débiles (facetas o nieve granulada) y pueden caer a nuestro paso. Los lugares peligrosos están bajo collados y cordales, por encima de 2.500 m y también las orientaciones umbrías resguardadas a N, NE y NW, entre 2.200 y 2.400 m. Las placas, en caso de romperse, podrán generar aludes de tamaño 2 (medio), con capacidad para enterrar un montañero.

Distribución del manto nivoso

En umbrías hay nieve por encima de 1.400-1.500 m, y en las solanas está presente por encima de 1.700 m. Los espesores, aunque irregulares, rondan los 85-105 cm en cotas medias. Son grosores por encima de los habituales para la época.

Tendencia para las próximas 48-72h

Leve descenso de los problemas por nieve húmeda debido al descenso térmico. Continuaremos con las capas débiles persistentes en umbrías. Peligro: SIN CAMBIOS

El próximo boletín será emitido el día 2026-03-18

5 MUY FUERTE	4 FUERTE	3 NOTABLE	2 LIMITADO	1 DÉBIL

EAWS EUROPEAN AVALANCHE WARNING SERVICES

ICGC Institut Cartogràfic i Geològic de Catalunya

Servei Meteorològic de Catalunya

Boletín de peligro de aludes Vessant Nord Cadí-Moixeró Del 17/03/2026 al 18/03/2026

(Válido fuera pistas de esquí y zonas no controladas)

LIMITADO (2) por encima de 2200 m.
DÉBIL (1) por debajo.

Situación primaria

Nieve húmeda

Distribución

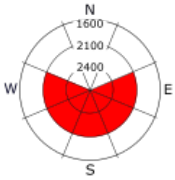

Tamaño

Origen

Tendencia

Situación secundaria

Nieve venteada

Distribución

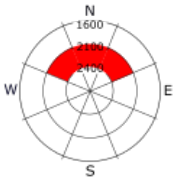

Tamaño

Origen

Tendencia

Estado del manto nivoso

Seguiremos con problemas por nieve húmeda y la presencia de alguna placa antigua, en cota alta. Con el aumento térmico y la insolación intensa, propia de marzo, la nieve más superficial se transformará a mediodía. A primera hora, el manto estará estable, pero a partir del mediodía pueden caer aludes de fusión de forma natural. No tendrán tamaño suficiente para enterrarnos, excepto en terreno trampa donde habrá que evitar pasar a las horas centrales del día y mientras la nieve no rehiele. Las orientaciones más peligrosas son las orientadas a Este, Sur y Oeste. El terreno más afectado por aludes de fusión son las zonas de salida de puntos oscuros como rocas y árboles.

Por otra parte, todavía se mantienen pequeñas placas de viento formadas durante el fin de semana anterior que pueden caer a nuestro paso en las umbrías y bajo collados y crestas más elevadas, en orientaciones que van de E hacia S y aisladamente en N, NE y NW entre 2.200-2.400 m.

Distribución del manto nivoso

En umbrías hay nieve por encima de 1.400-1.500 m, y en las solanas está presente por encima de 1.500 m. El manto nivoso es esquiable por encima de unos 1.800 m. Los grosores están alrededor de 160-180 cm a 2.200 m. Estos valores son muy excedentarios para la época del año.

Tendencia para las próximas 48-72h

Leve descenso de los problemas por nieve húmeda debido a los descenso térmico. Peligro: SIN CAMBIOS.

El próximo boletín será emitido el día 2026-03-18

5 MUY FUERTE	4 FUERTE	3 NOTABLE	2 LIMITADO	1 DÉBIL

EAWS EUROPEAN AVALANCHE WARNING SERVICES

ICGC Institut Cartogràfic i Geològic de Catalunya

Servei Meteorològic de Catalunya

Boletín de peligro de aludes Prepirineu
Del 17/03/2026 al 18/03/2026

(Válido fuera pistas de esquí y zonas no controladas)

LIMITADO (2), a partir de mediodía.
DÉBIL (1), por la mañana.

Situación primaria

Nieve húmeda

Distribución

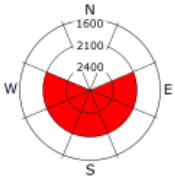

Tamaño

Origen

Tendencia

Estado del manto nivoso
Seguiremos con problemas por nieve húmeda y la presencia de alguna placa antigua, en cota alta. Con el aumento térmico y la insolación intensa, propia de marzo, la nieve más superficial se transformará a mediodía. A primera horael manto estará estable, pero a partir del mediodía pueden caer aludes de fusión de forma natural. No tendrán tamaño suficiente para enterrarnos, excepto en terreno trampa donde habrá que evitar pasar a las horas centrales del día y mientras la nieve no rehiele. Las orientaciones más peligrosas son las orientadas a E, S y O. El terreno más afectado por aludes de fusión son las zonas de salida de puntos oscuros como rocas y árboles.
Aún se mantienen pequeñas placas de viento, menos reactivas, pero que todavía pueden caer a nuestro paso en las umbrías y bajo collados y cordales, en orientaciones que van de E hacia S y aisladamente en N, NE y NW entre 2200-2400 m. Las placas de viento no tendrán capacidad de enterrar a un montañero, excepto en terreno trampa.

Distribución del manto nivoso
En umbrías hay nieve por encima de 1.600-1700 m. En solanas la nieve está presente por encima de 1.800-1.900 m. Los espesores, aunque irregulares, rondan los 65-85 cm en cotas medias.

Tendencia para las próximas 48-72h
Leve descenso de los problemas por nieve húmeda debido al descenso térmico. Peligro: SIN CAMBIOS.

El próximo boletín será emitido el día 2026-03-18

5 MUY FUERTE	4 FUERTE	3 NOTABLE	2 LIMITADO	1 DÉBIL

EAWS EUROPEAN AVALANCHE WARNING SERVICES

ICGC Institut Cartogràfic i Geològic de Catalunya

Servei Meteorològic de Catalunya meteo.cat

Boletín de peligro de aludes Ter-Freser
Del 17/03/2026 al 18/03/2026

(Válido fuera pistas de esquí y zonas no controladas)

LIMITADO (2)

Situación primaria

Nieve húmeda

Distribución

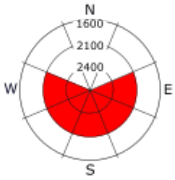

Tamaño

Origen

Tendencia

Situación secundaria

Capas débiles persistentes

Distribución

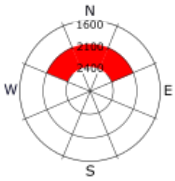

Tamaño

Origen

Tendencia

Estado del manto nivoso

El manto nivoso ha sido erosionado por el episodio de viento, especialmente de las cotas más altas de las umbrías donde aflora la crosta marrón. Para el martes esperamos problemas relacionados con la nieve húmeda y la presencia de niveles débiles enterrados. Pese a que de madrugada y primera las costras son portantes y resistentes, con la insolación y el ascenso térmico se transformará el manto más superficial. Pueden caer aludes de fusión de forma natural, en solanas que llegarán a tamaño 1(pequeñ), sin capacidad para enterrar a una persona. El terreno más afectado por aludes de fusión son las salidas de puntos oscuros (rocas y árboles) y las orientaciones E, S y O. También se mantienen placas de viento, de días atrás, sobre algún nivel débil que pueden caer a nuestro paso, bajo collados y cordales por encima de 2.500 m, en orientaciones que van de E hacia S y en umbrías resguardadas como N, NE y NW entre 2.200-2.400 m. Las placas de viento tendrán capacidad de enterrarnos.

Distribución del manto nivoso

Hay nieve en el suelo por encima de 1.600-1.700 m. Es esquiable a partir de unos 1700 m. El manto nivoso presenta grosores muy excedentarios para la época del año. En lugares no afectados por el viento los grosores oscilan entre 85-105 cm a unos 2.000 my más de 150 cm por encima de 2.400 m.

Tendencia para las próximas 48-72h

Leve descenso de los problemas por nieve húmeda debido al descenso térmico. Continuaremos con las capas débiles persistentes en umbrías elevadas. Peligro: SIN CAMBIOS

El próximo boletín será emitido el día 2026-03-18

5 MUY FUERTE	4 FUERTE	3 NOTABLE	2 LIMITADO	1 DÉBIL

EAWS EUROPEAN AVALANCHE WARNING SERVICES