BUTLLETÍ DEL PERILL D'ALLAUS DEL PRINCIPAT D'ANDORRA

Servei meteorològic nacional
Principat d'Andorra

Elaborat el 17/03/2026 16:00
Propera actualització 18/03/2026 a les 16h

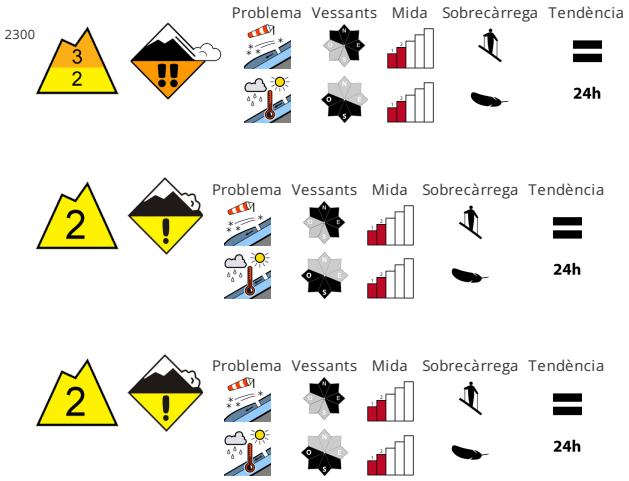

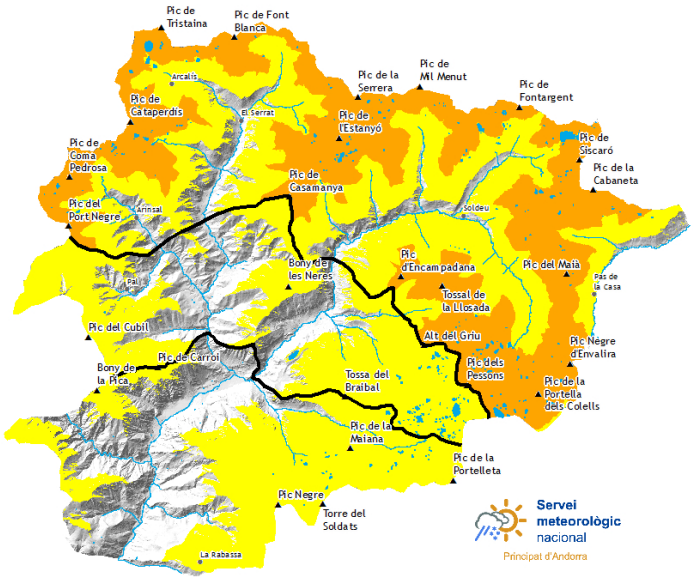

ESTABILITAT DEL MANTELL NIVAL

Les plaques de vent representen la principal font de perill. Sobretot als vessants inclinats orientats a nord-oest, nord i est a la part superior del mantell de neu hi ha capes febles inestables. Les plaques de vent poden ser desencadenades fàcilment i assolir mida mitjana. Els indrets perillosos es troben prop del límit del bosc i també a les transicions de mantell prim a gruixut. Amb l'augment de la temperatura diürna i la radiació solar, són possibles allaus de neu humida de mida petita i mitjana. Això es dona en vessants assolellats inclinats , i també a la base de parets rocoses.

QUALITAT DE LA NEU

Als vessants assolellats i a cotes baixes i mitges : la superfície del mantell de neu es regelarà per formar una crosta portant i s'estovarà ja durant el matí. Prop de les carenes els gruixos de neu varien molt per la influència del vent. Són enganyosos els vessants amb acumulacions de neu ventada. Es recomana mantenir la distància entre els components.

GRUIXOS DEL MANTELL NIVAL FORA DE PISTA

Zona nord		Gruix neu		
Mantell Nival		1500m	2000m	2500m
N	1600 m	0 cm	150 cm	200 cm
S	1900 m	0 cm	100 cm	150 cm

Zona centre		Gruix neu		
Mantell Nival		1500m	2000m	2500m
N	1600 m	0 cm	150 cm	200 cm
S	1900 m	0 cm	100 cm	150 cm

Zona sud		Gruix neu		
Mantell Nival		1500m	2000m	2500m
N	1600 m	0 cm	120 cm	150 cm
S	1900 m	0 cm	60 cm	100 cm

Govern d'Andorra

EAWS EUROPEAN AVALANCHE WARNING SERVICES

Aquest butlletí ha estat elaborat seguint les normes i recomanacions de l'**European Avalanche Warning Services**, del qual el **Servei meteorològic Nacional** n'és membre

BUTLLETÍ DEL PERILL D'ALLAUS DEL PRINCIPAT D'ANDORRA

Servei meteorològic nacional
Principat d'Andorra

Informació detallada per espais naturals protegits

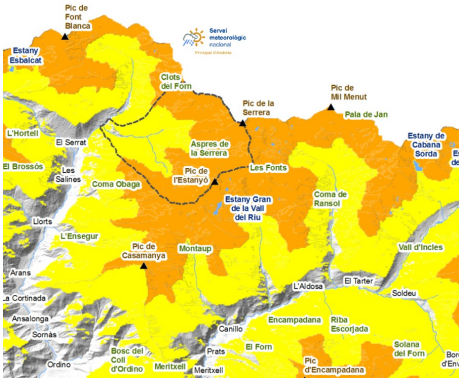

SORTENY

L´ambient hivernal del cap de setmana ha enterrat la neu vella, però el vent la va deixar al descobert en canvis de rasant, crestes i vessants orientats a nord. Sovint, el vent es va emportar la neu nova i també la vella i va deixar les traces en relleu. L´augment de les temperatures diürnes fa que la textura de la neu sigui molt diferent en pocs metres, ja que la neu nova s´humidifica més ràpid i llisca menys. Atenció amb les plaques de vent dels vessants est, sud i oest, on aquests primers dies s´hi haurà de circular amb més prudència.

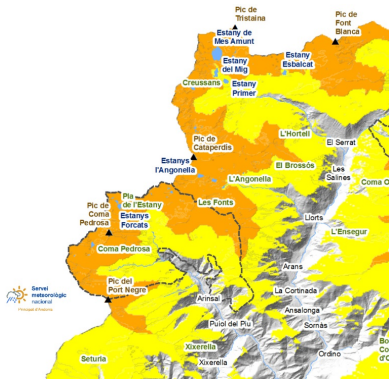

COMAPEDROSA

A cotes altes, la neu vella està ben regelada i està al descobert als indrets ventats. La identificarem pel canvi de color amb la neu nova. Serà més segur i estable circular per la neu vella. La neu nova no ha sigut suficient per tapar les esquerdes de lliscament basal, que encara representen un perill de caiguda.

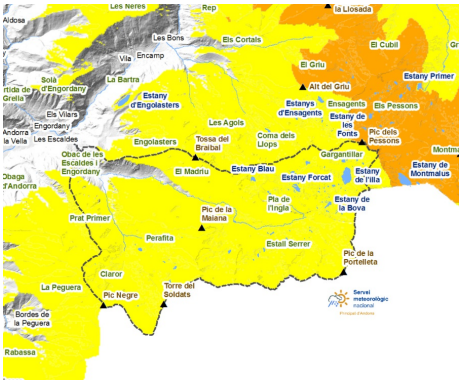

MADRIU-PERAFITA-CLAROR

Els accessos amb esquís des dels Cortals d´Encamp, la Rabassa i Grau Roig continuen ben nevats, però la neu ventada als vessants nord i est ens ha de fer circular amb precaució.

Govern d'Andorra

EAWS
EUROPEAN AVALANCHE WARNING SERVICES

Aquest butlletí ha estat elaborat seguint les normes i recomanacions de l'**European Avalanche Warning Services**, del qual el **Servei meteorològic Nacional** n'és membre

BUTLLETÍ DEL PERILL D'ALLAUS DEL PRINCIPAT D'ANDORRA

Servei meteorològic nacional
Principat d'Andorra

Gruixos de neu nova dels darrers dies (de les últimes 24h mesurat a les 06:00h UTC)

	13/03/2026	14/03/2026	15/03/2026	16/03/2026
FEDA (Central)	0 cm	0 cm	0 cm	0 cm
Engolasters - FEDA	0 cm	6 cm	0 cm	0 cm
Bony de les Neres	3 cm	14 cm	0 cm	0 cm
Sorteny	8 cm	25 cm	3 cm	0 cm
Les Fonts d'Arinsal	9 cm	26 cm	0 cm	0 cm
Perafita	0 cm	4 cm	34 cm	0 cm
Tossa Espiolets	5 cm	0 cm	0 cm	0 cm
Grau Roig - FEDA	4 cm	21 cm	0 cm	0 cm
Fontverd	0 cm	29 cm	0 cm	0 cm
Ransol - FEDA	0 cm	8 cm	0 cm	0 cm
Caborreu	5 cm	11 cm	0 cm	0 cm
La Solana	3 cm	29 cm	0 cm	0 cm
Coll Pa	4 cm	4 cm	0 cm	0 cm
Envalira Antenes	0 cm	37 cm	6 cm	0 cm
Vall del Riu FEDA	9 cm	14 cm	0 cm	0 cm