BUTLLETÍ DEL PERILL D'ALLAUS DEL PRINCIPAT D'ANDORRA

Préparé le 17/03/2026 16:00
Prochaine mise à jour le 18/03/2026 à 16h

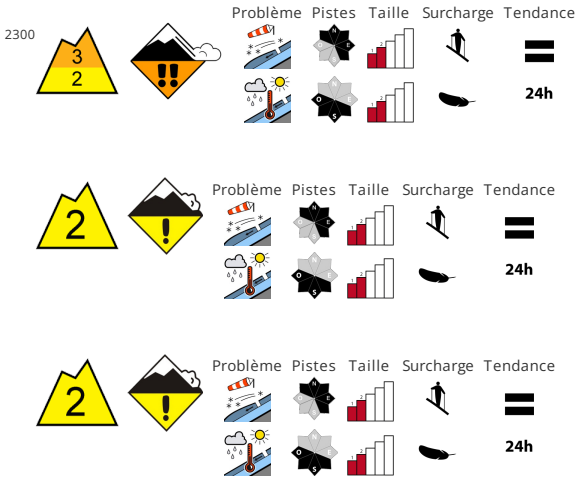

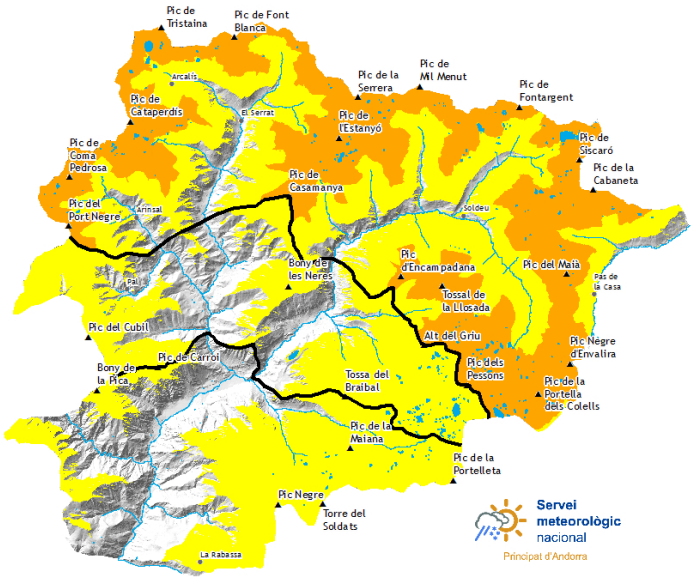

STABILITÉ DU MANTEAU NEIGEUX

Les accumulations de neige soufflée constituent le danger principal. Dans la partie supérieure du manteau neigeux des couches fragiles susceptibles d'être déclenchées sont présentes ils se rencontrent , surtout sur les pentes raides exposées au nord-ouest , au nord et à l'est. Les accumulations de neige soufflée peuvent peut être déchaîné facilement et atteindre une taille moyenne.. Les endroits dangereux se situent dans la zone de la limite de la forêt ainsi qu'aux transitions entre les endroits faiblement et fortement enneigés. Des avalanches petites et moyennes humides sont ils sont possibles avec le réchauffement diurne et le rayonnement solaire. Ceci sur les pentes raides ensoleillées comme au pied des parois rocheuses.

QUALITÈ DE LA NEIGE

Sur les pentes ensoleillées et à basses et moyennes altitudes (-):. La surface de la neige regèle et devient porteuse et se ramollit dès la matinée.. À proximité des crêtes on trouve suivant l'influence du vent des hauteurs de neiges très différentes. Ce sont les pentes où la neige soufflée s'est accumulée qui sont traîtres. Des distances de délestage sont recommandées..

EPAISSEUR DE NEIGE HORS PISTE

Zone nord		Epaisseur de neige		
Nival manteau		1500m	2000m	2500m
N	1600 m	0 cm	150 cm	200 cm
S	1900 m	0 cm	100 cm	150 cm

Zone centre		Epaisseur de neige		
Nival manteau		1500m	2000m	2500m
N	1600 m	0 cm	150 cm	200 cm
S	1900 m	0 cm	100 cm	150 cm

Zone sud		Epaisseur de neige		
Nival manteau		1500m	2000m	2500m
N	1600 m	0 cm	120 cm	150 cm
S	1900 m	0 cm	60 cm	100 cm

Govern d'Andorra

EAWS EUROPEAN AVALANCHE WARNING SERVICES

Aquest butlletí ha estat elaborat seguint les normes i recomanacions de l'**European Avalanche Warning Services**, del qual el **Servei meteorològic Nacional** n'és membre

BUTLLETÍ DEL PERILL D'ALLAUS DEL PRINCIPAT D'ANDORRA

Servei meteorològic nacional
Principat d'Andorra

Des informations détaillées par espace naturel protégé

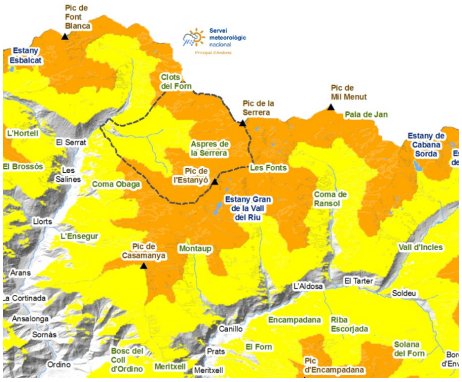

SORTENY

L'atmosphère hivernale du week-end a enfoui la vieille neige, mais le vent l'a laissée exposée sur les dénivelés, les crêtes et les pentes exposées au nord. Souvent, le vent emportait aussi bien la neige nouvelle que l'ancienne et laissait les traces en relief. L'augmentation des températures diurnes rend la texture de la neige très différente en quelques mètres seulement, car la nouvelle neige s'humidifie plus rapidement et glisse moins. Attention aux plaques de vent sur les versants est, sud et ouest, où ces premiers jours il faudra conduire plus prudemment. , , , , , , ,

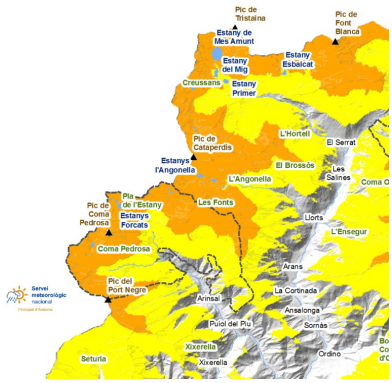

COMAPEDROSA

À haute altitude, la vieille neige est bien gelée et exposée dans les zones venteuses. Nous l'identifierons par le changement de couleur avec la nouvelle neige. Il sera plus sûr et plus stable de rouler sur la vieille neige. La neige fraîche n'a pas suffi à couvrir les fissures de glissement basales, qui représentent toujours un risque de chute. , , , , , , ,

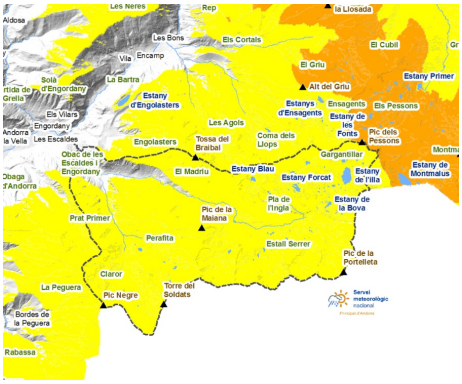

MADRIU-PERAFITA-CLAROR

Les accès à ski depuis les Cortals d´Encamp, la Rabassa et Grau Roig sont encore enneigés, mais la poudrerie sur les versants nord et est doit nous inciter à conduire avec prudence. ,

Govern d'Andorra

EAWS
EUROPEAN AVALANCHE WARNING SERVICES

Aquest butlletí ha estat elaborat seguint les normes i recomanacions de l'**European Avalanche Warning Services**, del qual el **Servei meteorològic Nacional** n'és membre

BUTLLETÍ DEL PERILL D'ALLAUS DEL PRINCIPAT D'ANDORRA

Servei meteorològic nacional
Principat d'Andorra

Couche de neige fraiche des derniers jours (De 24 h mesurée à 06:00 h UTC)

	13/03/2026	14/03/2026	15/03/2026	16/03/2026
FEDA (Central)	0 cm	0 cm	0 cm	0 cm
Engolasters - FEDA	0 cm	6 cm	0 cm	0 cm
Bony de les Neres	3 cm	14 cm	0 cm	0 cm
Sorteny	8 cm	25 cm	3 cm	0 cm
Les Fonts d'Arinsal	9 cm	26 cm	0 cm	0 cm
Perafita	0 cm	4 cm	34 cm	0 cm
Tossa Espiolets	5 cm	0 cm	0 cm	0 cm
Grau Roig - FEDA	4 cm	21 cm	0 cm	0 cm
Fontverd	0 cm	29 cm	0 cm	0 cm
Ransol - FEDA	0 cm	8 cm	0 cm	0 cm
Caborreu	5 cm	11 cm	0 cm	0 cm
La Solana	3 cm	29 cm	0 cm	0 cm
Coll Pa	4 cm	4 cm	0 cm	0 cm
Envalira Antenes	0 cm	37 cm	6 cm	0 cm
Vall del Riu FEDA	9 cm	14 cm	0 cm	0 cm