MINISTERO DELLA DIFESA

meteomont
Servizio Nazionale di previsione neve e valanghe

EAWS EUROPEAN AVALANCHE WARNING SERVICES

CARABINIERI

AERONAUTICA MILITARE SERVIZIO METEOROLOGICO

# PREALPI LOMBARDE

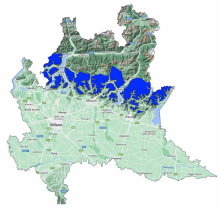

Bollettino Valanghe N. 375/2026 del 17/03/2026 ore 14.00
Validità 48 ore prossima emissione 18/03/2026

**A cura del Servizio METEOMONT dell'ARMA dei CARABINIERI**
**In collaborazione con Servizio Meteorologico dell'Aeronautica militare**

## SITUAZIONE alle 14:00 del 17/03/2026

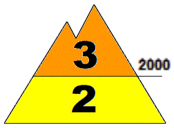


**SITUAZIONE TIPO: neve a debole coesione e vento.**

**SITUAZIONE TIPO: situazione primaverile.**

| Quota neve (mslm) | Nord | Sud |
|---|---|---|
| | 1400 | 1500 |

| Altezza Neve (cm) | Neve al suolo | Neve Fresca | Quota (mslm) |
|---|---|---|---|
| | 109 | 0 | 1713 |
| | 13 | 0 | 1445 |

**VALANGHE OSSERVATE: Alcune valanghe di medie dimensioni, Valanghe di neve a debole coesione di fondo.**

## PREVISIONI 18/03/2026

## GRADO DI PERICOLO: MARCATO 3

### SITUAZIONE TIPO: neve a debole coesione e vento.

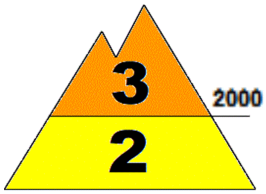


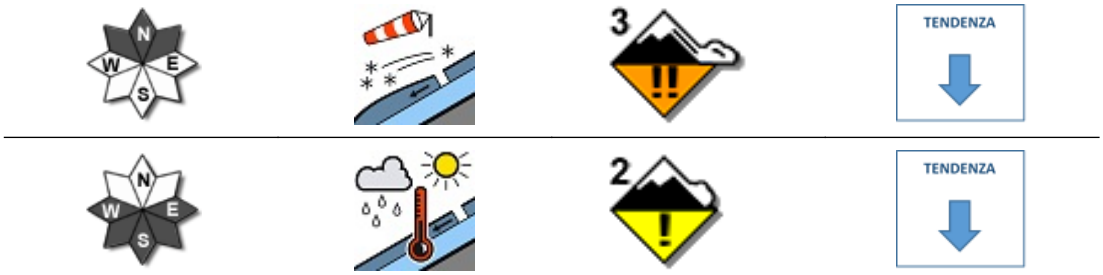


### SITUAZIONE TIPO: situazione primaverile.

**MANTO NEVOSO: La stabilità del manto nevoso è molto scarsa su alcuni punti (aree) per versanti settentrionali al di sopra di 2000 mslm, possibili valanghe di dimensioni medie.**
**La stabilità del manto nevoso è scarsa su pochi punti (aree) per versanti da est a ovest al di sotto di 2000 mslm, possibili valanghe di dimensioni medie.**

## AVVERTENZE

In considerazione degli importanti accumuli di neve ventata, sono da evitare conche, canaloni, cambi di pendenza e pendii sotto vento in genere.

## SCALA EUROPEA DEL GRADO DI PERICOLO VALANGHE

## LEGENDA PROBLEMA

**Bollettino realizzato su scala sinottica-regionale (standard EAWS). La sua valutazione non può escludere in alcun modo la necessità di una seria e capace valutazione locale del pericolo (singolo pendio) che può essere anche sensibilmente diverso. Le previsioni meteorologiche sono relative all'orario UTC (per l'Italia +1 in inverno e +2 in estate).**

# PREALPI LOMBARDE

## PREVISIONE METEO

| Quota | | 18/03/2026 h6:00 | 18/03/2026 h12:00 | 18/03/2026 h18:00 |
|---|---|---|---|---|
| 1000 | Venti | 03 Nodi da N-Est | 01 Nodi da Sud | 02 Nodi da Nord |
| | Temperature | -04 °C | +00 °C | +00 °C |
| | Temp.percepita | -6 °C | 0 °C | 0 °C |
| 2000 | Venti | 04 Nodi da N-Est | 01 Nodi da Sud | 03 Nodi da Nord |
| | Temperature | -04 °C | -02 °C | -02 °C |
| | Temp.percepita | -7 °C | -2 °C | -4 °C |
| 3000 | Venti | 06 Nodi da N-Est | 07 Nodi da Est | 11 Nodi da Est |
| | Temperature | -12 °C | -11 °C | -09 °C |
| | Temp.percepita | -18 °C | -17 °C | -17 °C |
| Zero termico | | 1000-1200 m. | 1600-1800 m. | 1400-1600 m. |
| Fenomeno | | — | — | — |
| Stato del cielo | | | | |

## LEGENDA FENOMENI

— Assenza Fenomeni · Nebbia · Foschia · Pioggia debole · Pioggia moderata · Pioggia forte · Temporali

Nevicata debole · Nevicata moderata · Nevicata forte

## STATO DEL CIELO

Sereno · Poco nuvoloso · Nuvoloso · Molto nuvoloso · Coperto

## Parametri meteonivometrici registrati presso i campi di rilevamento il 17/03/2026.

| Località | Comune | Quota (m.s.l.m.) | Altezza neve (cm) | Neve caduta nelle 24 ore (cm) | Temp. Min (°C) | Temp. Max (°C) | Condizioni del tempo |
|---|---|---|---|---|---|---|---|
| PASSO MANIVA | Collio (BS) | 1751 | 27 | 0 | -2 | +9 | Assenza di precipitazioni |
| PIAN DELLE BETULLE | Margno (LC) | 1445 | 13 | 0 | 0 | +10 | Assenza di precipitazioni |

**(*) Rilievi fuori campo**

**L'INFORMAZIONE E' PREVENZIONE - LEGGI L'ATTUALE GRADO DI PERICOLO VALANGHE!**

**IL CAPO DEL CENTRO NAZIONALE METEOMONT**
**(Ten. Col. RFI Emanuela Gini)**
**FIRMA AUTOGRAFA OMESSA AI SENSI**
**DELL'ART.3 DEL D.LGS N.39/1993**