ALPI LIGURI SUD

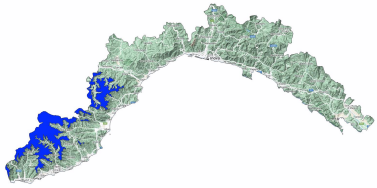

Bollettino Valanghe N. 328/2026 del 17/03/2026 ore 14.00
Validità 48 ore prossima emissione 18/03/2026

A cura del Servizio METEOMONT dell'ARMA dei CARABINIERI
In collaborazione con Servizio Meteorologico dell'Aeronautica militare

SITUAZIONE alle 14:00 del 17/03/2026

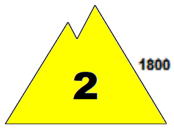

SITUAZIONE TIPO: neve a debole coesione e vento.



SITUAZIONE TIPO: situazione primaverile.

Quota neve (mslm)	Nord	Sud
	1300 - 1600	1300 - 1800

Altezza Neve (cm)	Neve al suolo	Neve Fresca	Quota (mslm)
	235	00	1815
	97	0	1400

VALANGHE OSSERVATE: Alcune valanghe di medie dimensioni, Valanghe di neve a debole coesione di fondo.

PREVISIONI 18/03/2026

GRADO DI PERICOLO: MODERATO 2

SITUAZIONE TIPO: freddo su caldo / caldo su freddo.

MANTO NEVOSO: La stabilità del manto nevoso è scarsa su alcuni punti (aree) per tutte le esposizioni, possibili valanghe di dimensioni medie.

AVVERTENZE

In considerazione dei recenti apporti di neve fresca, è richiesta un'ottima valutazione locale della stabilità ed individuazione dell'itinerario.

SCALA EUROPEA DEL GRADO DI PERICOLO VALANGHE

LEGENDA PROBLEMA

Bollettino realizzato su scala sinottica-regionale (standard EAWS). La sua valutazione non può escludere in alcun modo la necessità di una seria e capace valutazione locale del pericolo (singolo pendio) che può essere anche sensibilmente diverso. Le previsioni meteorologiche sono relative all'orario UTC (per l'Italia +1 in inverno e +2 in estate).

MINISTERO DELLA DIFESA

meteomont
Servizio Nazionale di previsione neve e valanghe

EAWS EUROPEAN AVALANCHE WARNING SERVICES

CARABINIERI

ALPI LIGURI SUD

PREVISIONE METEO

Quota		18/03/2026 h6:00	18/03/2026 h12:00	18/03/2026 h18:00
1000	Venti	01 Nodi da Nord	05 Nodi da Nord	07 Nodi da Nord
	Temperature	-01 °C	-02 °C	-01 °C
	Temp.percepita	-1 °C	-5 °C	-5 °C
2000	Venti	02 Nodi da Nord	10 Nodi da Nord	16 Nodi da Nord
	Temperature	-03 °C	-05 °C	-04 °C
	Temp.percepita	-3 °C	-11 °C	-12 °C
3000	Venti	11 Nodi da Nord	16 Nodi da N-Est	21 Nodi da N-Est
	Temperature	-07 °C	-11 °C	-09 °C
	Temp.percepita	-14 °C	-21 °C	-19 °C
Zero termico		1400-1600 m.	1200-1400 m.	1300-1500 m.
Fenomeno		—		
Stato del cielo				

LEGENDA FENOMENI

— Assenza Fenomeni · Nebbia · Foschia · Pioggia debole · Pioggia moderata · Pioggia forte · Temporali

Nevicata debole · Nevicata moderata · Nevicata forte

STATO DEL CIELO

Sereno · Poco nuvoloso · Nuvoloso · Molto nuvoloso · Coperto

Parametri meteonivometrici registrati presso i campi di rilevamento il 17/03/2026.

Località	Comune	Quota (m.s.l.m.)	Altezza neve (cm)	Neve caduta nelle 24 ore (cm)	Temp. Min (°C)	Temp. Max (°C)	Condizioni del tempo
MONESI *	Triora (IM)	1425	97	0	N.P.	N.P.	Assenza di precipitazioni
MELOSA	Pigna (IM)	1540	10	0	N.P.	N.P.	Assenza di precipitazioni
MARGHERIA VIOLETTO *	Triora (IM)	1815	235	0	N.P.	N.P.	Assenza di precipitazioni

(*) Rilievi fuori campo

L'INFORMAZIONE E' PREVENZIONE - LEGGI L'ATTUALE GRADO DI PERICOLO VALANGHE!

IL CAPO DEL CENTRO NAZIONALE METEOMONT
(Ten. Col. RFI Emanuela Gini)
FIRMA AUTOGRAFA OMESSA AI SENSI
DELL'ART.3 DEL D.LGS N.39/1993

Bollettino realizzato su scala sinottica-regionale (standard EAWS). La sua valutazione non può escludere in alcun modo la necessità di una seria e capace valutazione locale del pericolo (singolo pendio) che può essere anche sensibilmente diverso. Le previsioni meteorologiche sono relative all'orario UTC (per l'Italia +1 in inverno e +2 in estate).