RÉPUBLIQUE FRANÇAISE
*Liberté Égalité Fraternité*

METEO FRANCE
À VOS CÔTÉS, DANS UN CLIMAT QUI CHANGE

# Bulletin d'estimation du risque d'avalanche

(valable en dehors des pistes balisées et ouvertes)

# MASSIF : Cerdagne Canigou

Rédigé le mardi 17 mars 2026 à 15h

## Estimation des risques pour le : MERCREDI 18 MARS

**UN PEU D'INSTABILITÉ EN HAUTE MONTAGNE.**

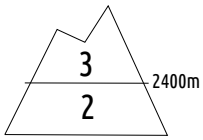


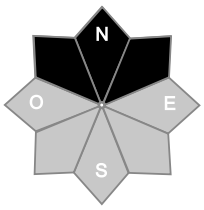


Au-dessus de 2400m indice de risque marqué, plus bas indice limité.

**Départs spontanés :** Quelques plaques de fond en moyenne montagne ou coulées en neige humide au soleil.

**Déclenchements provoqués :** Plaques à vent toujours présentes en haute montagne.

Indices de risque : 5 très fort - 4 fort - 3 marqué - 2 limité - 1 faible -- En noir : les pentes les plus dangereuses

## Stabilité du manteau neigeux

**Situation avalancheuse typique :** neige ventée avalanches de fond

**Déclenchements provoqués :**
Après une journée de mardi très douce et ensoleillée propice à la stabilisation dans de nombreuses pentes, des structures de plaques à vent peuvent demeurer sous les crêtes et pentes sommitales du massif, au-delà de 2400/2500 m. Des accumulations en neige sèche peuvent reposer sur de la neige roulée ou du givre de surface. Cassures de 30/40 cm localement possibles, moins faciles à déclencher que dimanche ou lundi. Pentes restant à l'ombre ou raides de secteur nord.
En deçà de cette altitude, l'humidification a gagné une bonne partie des pentes, et un déclenchement devient nettement moins probable. Les secteurs les plus froids avec configuration particulière (goulet, verrous ) peuvent éventuellement conserver un risque de déclenchement de plaques dans les pentes très raides.
*(Observables : traces d'avalanches récentes, fissures sous les skis, affaissement accompagné de 'whoomf', signes de transport par le vent).*

**Départs spontanés :**
Dans les pentes est, sud puis ouest chauffées par le soleil de mars, avalanches de fond ou de neige humide de taille 1 à 2 attendues. Un départ linéaire causé par l'humidification d'une sous-couche fragile est possible et entrainer très localement une avalanche de plus grande ampleur ( grande, taille 3 ).
*(Observables : neige très humide, gorgée d'eau; enfoncement important)*

**Autres :**
Neige glacée ou très dure dans la majorité des pentes au petit matin.

## Qualité de la neige

**Enneigement :**
L'enneigement reste excellent pour la saison, après plusieurs hivers déficitaires.
Une vingtaine de centimètres sont tombés en altitude ce week-end, avec de fortes accumulations à cause du vent. Fonte conséquente au soleil et en moyenne montagne depuis lundi après-midi et à fortiori mardi.

**Limites skiables :**
On peut encore envisager de chausser les skis dès 1600/1700 dans les forêts en versants froids, 1900/2000m en versants sud.

**État de la neige :**
Neige dure et regelée en surface au petit matin en moyenne montagne et dans les versants sud, est, ouest.
Évolution vers une neige meuble, voire très humide ou pourrie à basse altitude dans l'après-midi. Quelques zones de poudreuse dans les combes d'altitude et en secteur nord au-delà de 2000/2100 m voisinant avec un ancien manteau neigeux découvert par le vent de dimanche.

## Aperçu météo pour le mercredi 18 mars

| | nuit | matin | après-midi | soir |
|---|---|---|---|---|
| | | | | |
| Grand beau temps, douceur marquée. | | | | |
| **Pluie-Neige** | | | 2 200 m | 1 800 m |
| **Iso 0 °C** | 3 300 m | 3 200 m | 2 600 m | 2 100 m |
| **Vent 2000 m** | 10 km/h | 10 km/h | 15 km/h | 20 km/h |
| **Vent 3000 m** | 15 km/h | 15 km/h | 20 km/h | 30 km/h |

Pour consulter la vigilance en cours, veuillez vous rendre sur le site https://vigilance.meteofrance.fr/fr

Météo-France - 73 avenue de Paris, 94165 Saint-Mandé cedex - Contact : contact@meteo.fr

Rédigé par Météo-France avec la contribution des observateurs du réseau nivo-météorologiques. Partenariat : ANMSM (Maires de Stations de Montagne), DSF (Domaines Skiables de France), ADSP (Directeurs de Pistes et de la Sécurité des Stations de Sports d'Hiver) et autres acteurs de la montagne.

Bulletin neige & avalanches par téléphone au
**0 892 68 10 20** Service 0,35 € / min + prix appel

# Bulletin d'estimation du risque d'avalanche

(valable en dehors des pistes balisées et ouvertes)

# MASSIF : Cerdagne Canigou

Rédigé le mardi 17 mars 2026 à 15h

## Épaisseur de neige hors-piste

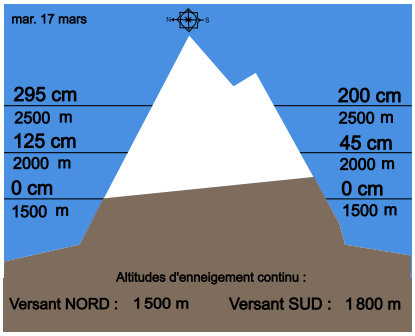


## Précipitations à 1800 m

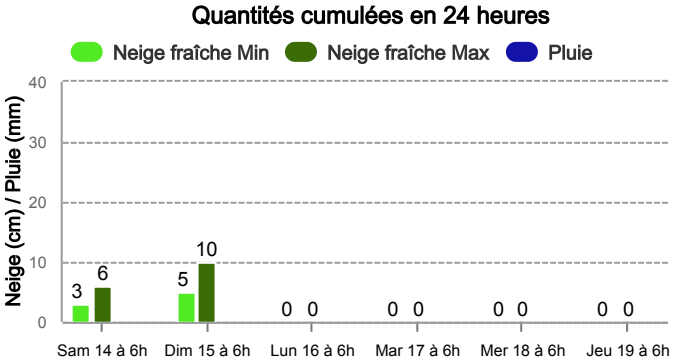


## Tendance du jeudi 19 mars

**Indice de risque limité**

Baisse du risque de déclenchement accidentel en haute montagne.

Pour consulter la vigilance en cours, veuillez vous rendre sur le site https://vigilance.meteofrance.fr/fr

Météo-France - 73 avenue de Paris, 94165 Saint-Mandé cedex - Contact : contact@meteo.fr

Rédigé par Météo-France avec la contribution des observateurs du réseau nivo-météorologiques. Partenariat : ANMSM (Maires de Stations de Montagne), DSF (Domaines Skiables de France), ADSP (Directeurs de Pistes et de la Sécurité des Stations de Sports d'Hiver) et autres acteurs de la montagne.

Bulletin neige & avalanches par téléphone au

0 892 68 10 20 Service 0,35 € / min + prix appel

RÉPUBLIQUE FRANÇAISE
*Liberté Égalité Fraternité*

METEO FRANCE
À VOS CÔTÉS, DANS UN CLIMAT QUI CHANGE

# Bulletin d'estimation du risque d'avalanche

(valable en dehors des pistes balisées et ouvertes)

# MASSIF : Cerdagne Canigou

Rédigé le mardi 17 mars 2026 à 15h

## Conditions nivo-météo des 7 derniers jours

| | mer. 11/03 | | | | jeu. 12/03 | | | | ven. 13/03 | | | | sam. 14/03 | | | | dim. 15/03 | | | | lun. 16/03 | | | | mar. 17/03 | | | |
|---|---|---|---|---|---|---|---|---|---|---|---|---|---|---|---|---|---|---|---|---|---|---|---|---|---|---|---|---|
| | 03h | 09h | 15h | 21h | 03h | 09h | 15h | 21h | 03h | 09h | 15h | 21h | 03h | 09h | 15h | 21h | 03h | 09h | 15h | 21h | 03h | 09h | 15h | 21h | 03h | 09h | 15h | 21h |
| Météo | | | | | | | | | | | | | | | | | | | | | | | | | | | | |
| Vent (km/h) | 20 | 25 | 35 | 45 | 40 | 30 | 25 | 25 | 25 | 25 | 30 | 40 | 50 | 50 | 55 | 70 | 95 | 130 | 95 | 70 | 70 | 60 | 55 | 40 | 45 | 25 | 15 | 15 |
| à 3000m | | | | | | | | | | | | | | | | | | | | | | | | | | | | |
| Vent (km/h) | 10 | 10 | 15 | 25 | 30 | 20 | 15 | 15 | 15 | 15 | 15 | 25 | 30 | 30 | 35 | 45 | 70 | 95 | 75 | 45 | 50 | 45 | 35 | 25 | 25 | 15 | 10 | 10 |
| à 2000m | | | | | | | | | | | | | | | | | | | | | | | | | | | | |

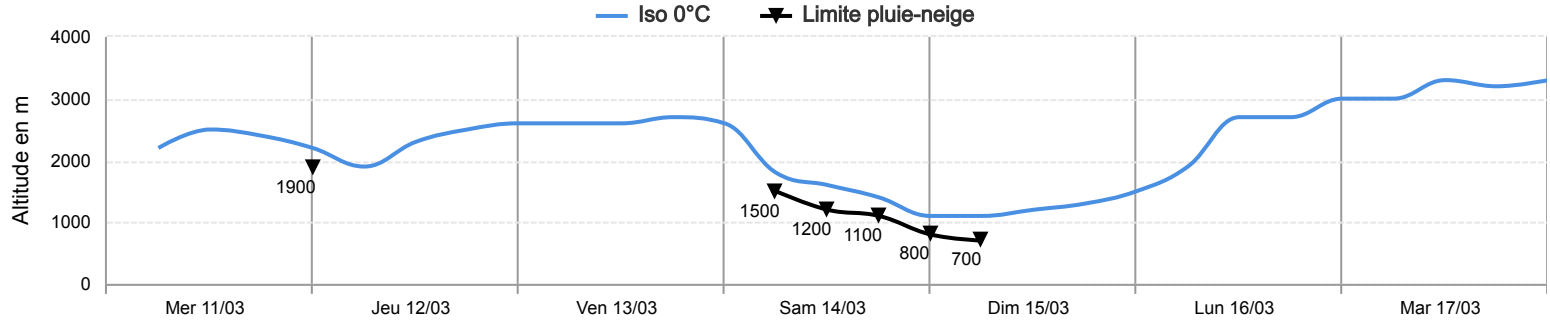


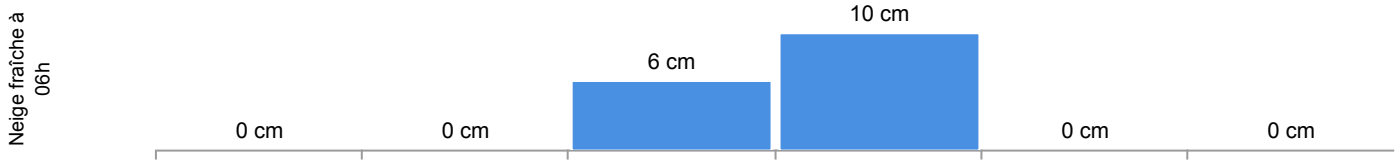


| Risque d'avalanche | mer. 11/03 | jeu. 12/03 | ven. 13/03 | sam. 14/03 | dim. 15/03 | lun. 16/03 | mar. 17/03 |
|---|---|---|---|---|---|---|---|
| | 2 | 2 | 2 | 3 | 3 | 3 | 3 |

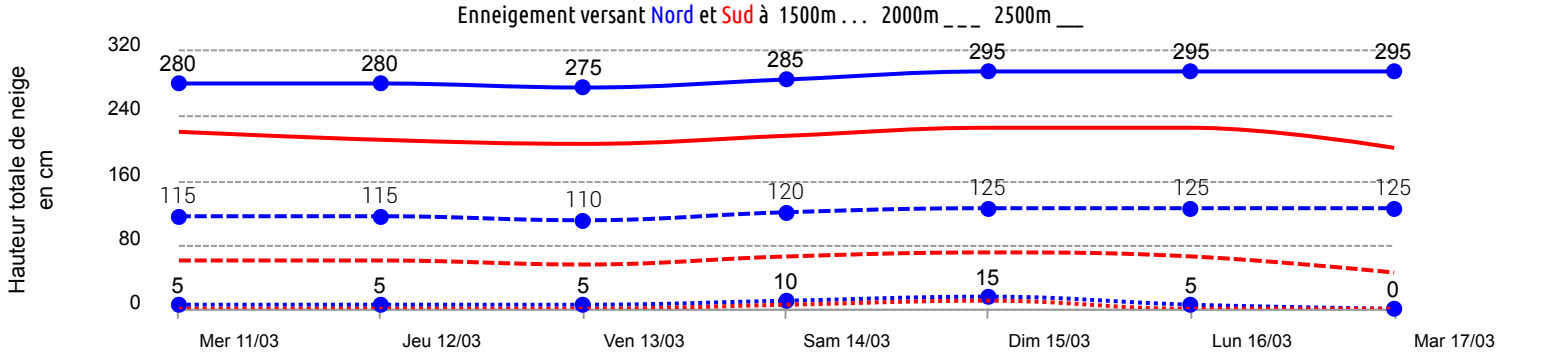


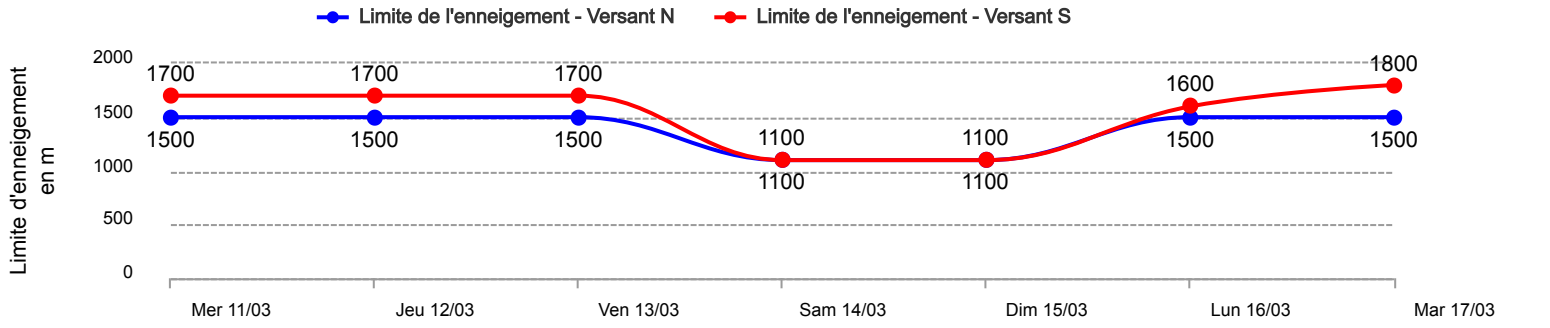


Pour consulter la vigilance en cours, veuillez vous rendre sur le site https://vigilance.meteofrance.fr/fr


Météo-France - 73 avenue de Paris, 94165 Saint-Mandé cedex - Contact : contact@meteo.fr



Rédigé par Météo-France avec la contribution des observateurs du réseau nivo-météorologiques. Partenariat : ANMSM (Maires de Stations de Montagne), DSF (Domaines Skiables de France), ADSP (Directeurs de Pistes et de la Sécurité des Stations de Sports d'Hiver) et autres acteurs de la montagne.



Bulletin neige & avalanches par téléphone au
0 892 68 10 20 Service 0,35 € / min + prix appel