RÉPUBLIQUE FRANÇAISE
Liberté Égalité Fraternité

METEO FRANCE
À VOS CÔTÉS, DANS UN CLIMAT QUI CHANGE

Bulletin d'estimation du risque d'avalanche
(valable en dehors des pistes balisées et ouvertes)
MASSIF : Haute-Ariege

Rédigé le mardi 17 mars 2026 à 15h

Estimation des risques pour le : MERCREDI 18 MARS

UN PEU D'INSTABILITÉ EN HAUTE MONTAGNE.

3

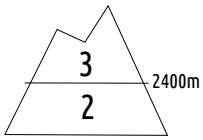

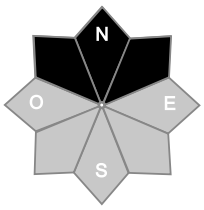

Au-dessus de 2400m indice de risque marqué, plus bas indice limité.

Départs spontanés : Quelques plaques de fond en moyenne montagne ou coulées en neige humide au soleil.

Déclenchements provoqués : Plaques à vent toujours présentes en haute montagne.

Indices de risque : 5 très fort - 4 fort - 3 marqué - 2 limité - 1 faible -- En noir : les pentes les plus dangereuses

Stabilité du manteau neigeux

Situation avalancheuse typique : neige ventée avalanches de fond

Déclenchements provoqués :
Après une journée de mardi très douce et ensoleillée propice à la stabilisation dans de nombreuses pentes, des structures de plaques à vent peuvent demeurer sous les crêtes et pentes sommitales du massif, au-delà de 2400/2500 m. Des accumulations en neige sèche peuvent reposer sur de la neige roulée ou du givre de surface.
Cassures de 30/40 cm localement possibles, moins faciles à déclencher que dimanche ou lundi. Pentes restant à l'ombre ou raides de secteur nord.
En deçà de cette altitude, l'humidification a gagné une bonne partie des pentes, et un déclenchement devient nettement moins probable. Les secteurs les plus froids avec configuration particulière (goulet, verrous) peuvent éventuellement conserver un risque de déclenchement de plaques dans les pentes très raides.
(Observables : traces d'avalanches récentes, fissures sous les skis, affaissement accompagné de 'whoomf', signes de transport par le vent).

Départs spontanés :
Dans les pentes est, sud puis ouest chauffées par le soleil de mars, avalanches de fond ou de neige humide de taille 1 à 2 attendues. Un départ linéaire causé par l'humidification d'une sous-couche fragile est possible et entrainer très localement une avalanche de plus grande ampleur (grande, taille 3).
(Observables : neige très humide, gorgée d'eau; enfoncement important)

Autres :
Neige glacée ou très dure dans la majorité des pentes au petit matin.

Qualité de la neige

Enneigement :
L'enneigement reste excellent pour la saison, après plusieurs hivers déficitaires.
Une trentaine de centimètres sont tombés en altitude ce week-end, très hétérogènes à cause du vent. Fonte conséquente au soleil et en moyenne montagne depuis lundi après-midi et à fortiori mardi.

Limites skiables :
On peut encore envisager de chausser les skis vers 1200/1300m en terrain herbeux en nord, mais sans véritable sous-couche en dessous de 1500m en versants froids, 1800/1900m en versants sud.

État de la neige :
Neige dure et regelée en surface au petit matin en moyenne montagne et dans les versants sud, est, ouest.
Évolution vers une neige meuble, voire très humide ou pourrie à basse altitude dans l'après-midi.
Encore un peu de poudreuse dans les combes d'altitude et en secteur nord au-delà de 2000/2100 m voisinant avec un ancien manteau neigeux découvert par le vent de dimanche.

Aperçu météo pour le mercredi 18 mars

	nuit	matin	après-midi	soir
Grand beau temps, douceur marquée.				
Pluie-Neige				
Iso 0 °C	3 400 m	3 300 m	3 200 m	3 100 m
Vent 2000 m	10 km/h	5 km/h	5 km/h	15 km/h
Vent 3000 m	15 km/h	15 km/h	15 km/h	25 km/h

Pour consulter la vigilance en cours, veuillez vous rendre sur le site https://vigilance.meteofrance.fr/fr

Météo-France - 73 avenue de Paris, 94165 Saint-Mandé cedex - Contact : contact@meteo.fr

Rédigé par Météo-France avec la contribution des observateurs du réseau nivo-météorologiques. Partenariat : ANMSM (Maires de Stations de Montagne), DSF (Domaines Skiables de France), ADSP (Directeurs de Pistes et de la Sécurité des Stations de Sports d'Hiver) et autres acteurs de la montagne.

Bulletin neige & avalanches par téléphone au
0 892 68 10 20 Service 0,35 € / min + prix appel

Bulletin d'estimation du risque d'avalanche

(valable en dehors des pistes balisées et ouvertes)

MASSIF : Haute-Ariege

Rédigé le mardi 17 mars 2026 à 15h

Épaisseur de neige hors-piste

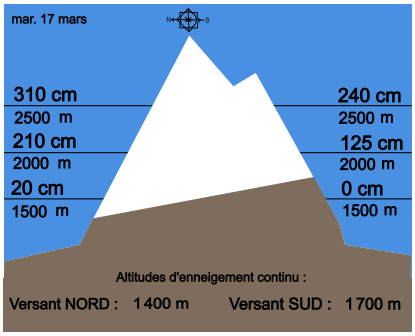

Précipitations à 1800 m

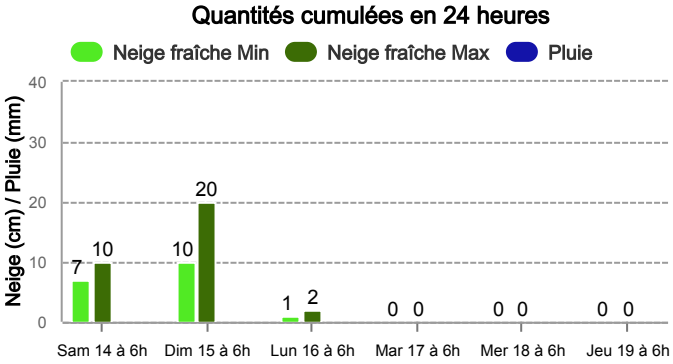

Tendance du jeudi 19 mars

Indice de risque limité

Baisse du risque de déclenchement accidentel en haute montagne.

Pour consulter la vigilance en cours, veuillez vous rendre sur le site https://vigilance.meteofrance.fr/fr

Météo-France - 73 avenue de Paris, 94165 Saint-Mandé cedex - Contact : contact@meteo.fr

Rédigé par Météo-France avec la contribution des observateurs du réseau nivo-météorologiques. Partenariat : ANMSM (Maires de Stations de Montagne), DSF (Domaines Skiables de France), ADSP (Directeurs de Pistes et de la Sécurité des Stations de Sports d'Hiver) et autres acteurs de la montagne.

Bulletin neige & avalanches par téléphone au

0 892 68 10 20 Service 0,35 € / min + prix appel

RÉPUBLIQUE FRANÇAISE
Liberté Égalité Fraternité

METEO FRANCE
À VOS CÔTÉS, DANS UN CLIMAT QUI CHANGE

Bulletin d'estimation du risque d'avalanche
(valable en dehors des pistes balisées et ouvertes)
MASSIF : Haute-Ariege

Rédigé le mardi 17 mars 2026 à 15h

Conditions nivo-météo des 7 derniers jours

	mer. 11/03				jeu. 12/03				ven. 13/03				sam. 14/03				dim. 15/03				lun. 16/03				mar. 17/03			
	03h	09h	15h	21h	03h	09h	15h	21h	03h	09h	15h	21h	03h	09h	15h	21h	03h	09h	15h	21h	03h	09h	15h	21h	03h	09h	15h	21h
Météo																												
Vent (km/h)	15	20	35	45	40	30	25	25	25	25	30	40	50	50	55	70	95	95	75	50	40	30	30	20	25	15	15	15
à 3000m																												
Vent (km/h)	10	10	15	30	30	20	15	15	15	15	15	25	30	30	35	45	60	60	50	30	25	20	20	10	15	10	10	10
à 2000m																												

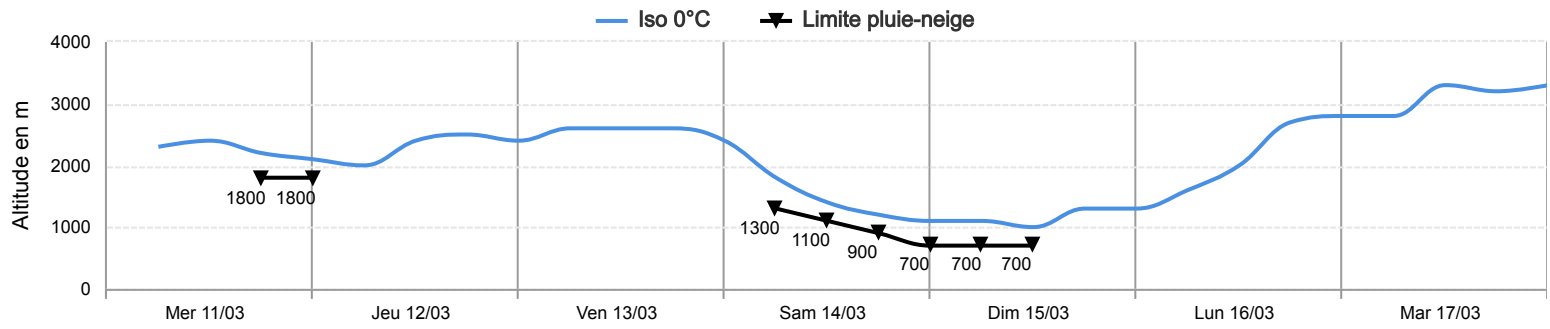

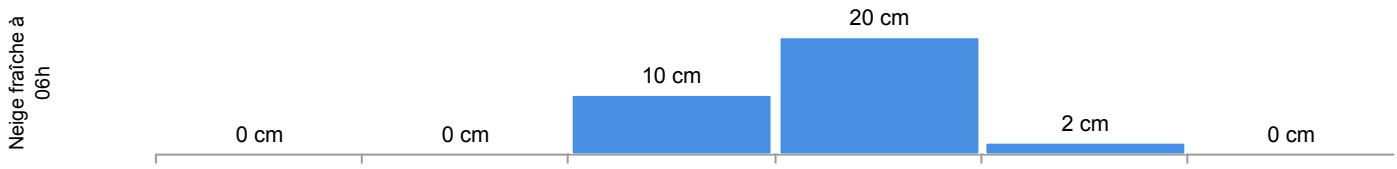

Risque d'avalanche	mer. 11/03	jeu. 12/03	ven. 13/03	sam. 14/03	dim. 15/03	lun. 16/03	mar. 17/03
	2	2	2	3	3	3	3

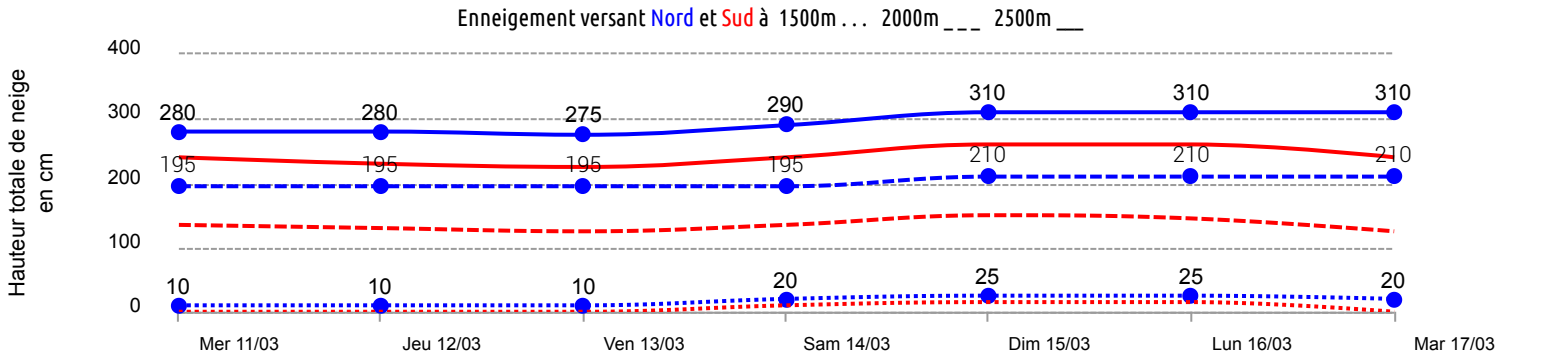

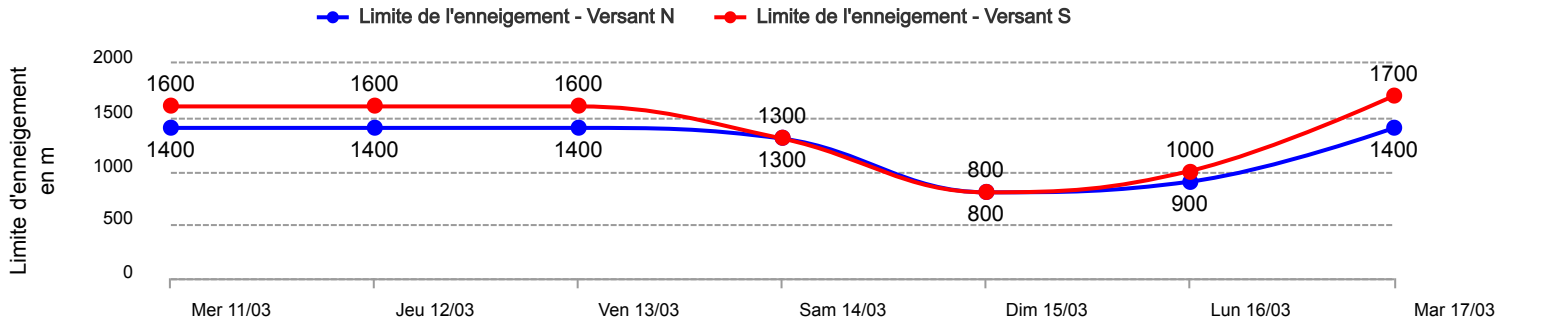

Pour consulter la vigilance en cours, veuillez vous rendre sur le site https://vigilance.meteofrance.fr/fr

Météo-France - 73 avenue de Paris, 94165 Saint-Mandé cedex - Contact : contact@meteo.fr

Rédigé par Météo-France avec la contribution des observateurs du réseau nivo-météorologiques. Partenariat : ANMSM (Maires de Stations de Montagne), DSF (Domaines Skiables de France), ADSP (Directeurs de Pistes et de la Sécurité des Stations de Sports d'Hiver) et autres acteurs de la montagne.

Bulletin neige & avalanches par téléphone au

0 892 68 10 20 Service 0,35 € / min + prix appel