Bulletin d'estimation du risque d'avalanche

(valable en dehors des pistes balisées et ouvertes)

MASSIF : Aravis

Rédigé le mardi 17 mars 2026 à 16h

Estimation des risques pour le : MERCREDI 18 MARS

INSTABILITÉS DANS LA NEIGE VENTÉE EN UBACS ET EN ALTITUDE.

3

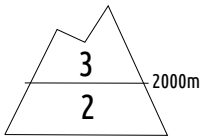

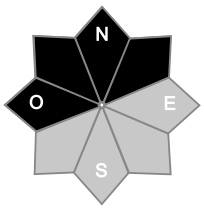

Au-dessus de 2000m indice de risque marqué, plus bas indice limité.

Départs spontanés : rares plaques de fond.

Déclenchements provoqués : Plaques à vent

Indices de risque : 5 très fort - 4 fort - 3 marqué - 2 limité - 1 faible -- En noir : les pentes les plus dangereuses

Stabilité du manteau neigeux

Situation avalancheuse typique : neige ventée avalanches de fond

Déclenchements provoqués :

* Au-dessus de 2000 m : **Nombreuses plaques à vent**. **Formés par le vent de N/NW/NE** puis **en cours de formation en journée par le vent de SE**. Elles se situent dans les ubacs au-dessus de 2000 m. Elles sont **plus nombreuses en altitude**. **Assez facile à déclencher**. Taille 1 à 2 (petite à moyenne).

Observables : vaguelettes, fissures devant les skis, zones d'accumulations…

* Au-dessus de 1800m en NW/N/NE et 2500m ailleurs, une couche fragile est encore présente sous environ 1m de neige, mais très difficilement sollicitable. Dans le cas d'une avalanche en cascade, elle pourrait être sollicitée et engendrer des avalanches de taille 3 (grandes).

Départs spontanés :

* En dessous de 2200/2400 m : rares avalanches de fond, dans les zones herbeuses ou les dalles rocheuses. Taille 1 à 2.
* En dessous de 2000 m : petites avalanches de neige humide dans les adrets. De plus en plus nombreuses au fil de l'ensoleillement. Taille 1.

Qualité de la neige

Enneigement :

Il est correct pour la saison. En matinée, on retrouve de la neige dès 1000/1200 m. On retrouve un manteau réellement skiable à partir de 1200/1300 m en Nord et 1500/1600m en Sud.

Qualité de la neige mercredi :

* En dessous de 1800 m : neige regelée le matin sur un fond humide. La croute s'humidifie au fil des heures.
* Entre 1800 et 2300/2400 m:
- versant Nord : Soufflé près des crêtes, plus poudreux dense loin des secteurs exposés au vent de N
- versant E/SE : la neige décaille légèrement en début de matinée avant de durcir sous l'effet du vent de SE.
- W/SW : La neige reste légèrement croutée en journée et a du mal à décailler sous l'effet du vent.
* Au-dessus de 2300/2400 m :

En versant W/S/E : La neige reste légèrement croutée en journée et a du mal à décailler sous l'effet du vent.

En versant N : Soufflé près des crêtes, plus poudreux dense loin des secteurs exposés au vent de Nord.

Aperçu météo pour le mercredi 18 mars

nuit	matin	après-midi	soir

Grand soleil. Bise puis vent de SE à partir du milieu de journée. Températures en baisse : à 2000 m : -2 à 3°C.

Pluie-Neige				
Iso 0 °C	2 500 m	2 200 m	2 000 m	2 000 m
Vent 2000 m	15 km/h	15 km/h	20 km/h	15 km/h
Vent 2500 m	45 km/h	40 km/h	30 km/h	30 km/h

Épaisseur de neige hors-piste

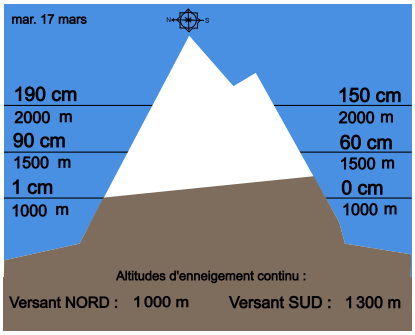

Précipitations à 1800 m

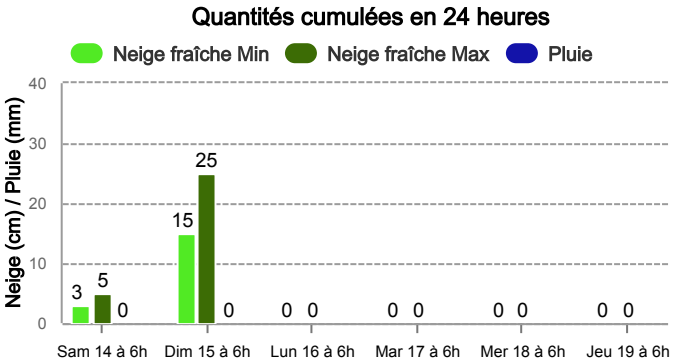

Tendance du jeudi 19 mars

3 **Indice de risque marqué**

Risque en baisse. Temps anticyclonique.

Pour consulter la vigilance en cours, veuillez vous rendre sur le site https://vigilance.meteofrance.fr/fr

Météo-France - 73 avenue de Paris, 94165 Saint-Mandé cedex - Contact : contact@meteo.fr

Rédigé par Météo-France avec la contribution des observateurs du réseau nivo-météorologiques. Partenariat : ANMSM (Maires de Stations de Montagne), DSF (Domaines Skiables de France), ADSP (Directeurs de Pistes et de la Sécurité des Stations de Sports d'Hiver) et autres acteurs de la montagne.

Bulletin neige & avalanches par téléphone au

0 892 68 10 20 Service 0,35 € / min + prix appel

Bulletin d'estimation du risque d'avalanche

(valable en dehors des pistes balisées et ouvertes)

MASSIF : Aravis

Rédigé le mardi 17 mars 2026 à 16h

Conditions nivo-météo des 7 derniers jours

	mer. 11/03				jeu. 12/03				ven. 13/03				sam. 14/03				dim. 15/03				lun. 16/03				mar. 17/03			
	03h	09h	15h	21h	03h	09h	15h	21h	03h	09h	15h	21h	03h	09h	15h	21h	03h	09h	15h	21h	03h	09h	15h	21h	03h	09h	15h	21h
Météo																												
Vent (km/h)	40	50	60	45	30	20	5	10	30	45	50	70	55	30	20	45	45	20	15	15	15	20	20	20	25	30	30	35
à 2500m																												
Vent (km/h)	30	40	50	30	20	10	5	5	20	40	40	55	45	20	15	40	35	10	5	5	5	10	10	10	10	15	15	15
à 2000m																												

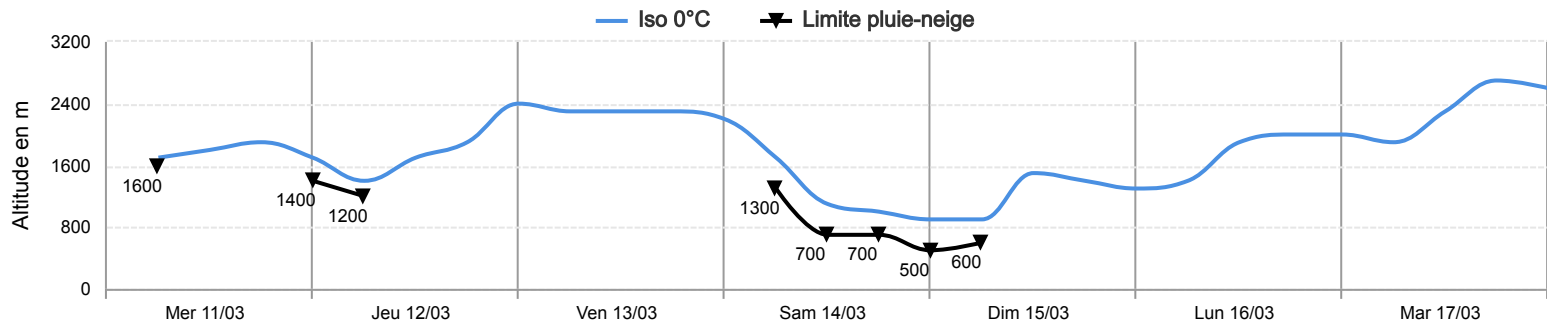

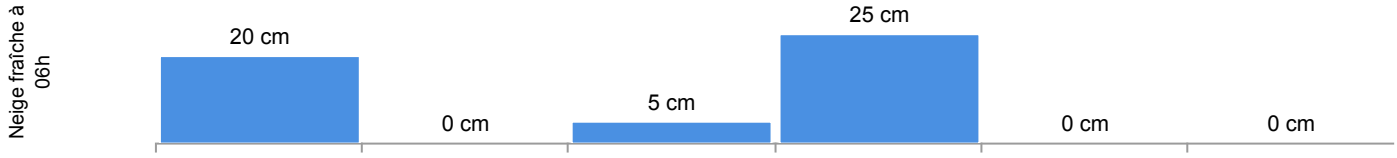

Risque d'avalanche	mer. 11/03	jeu. 12/03	ven. 13/03	sam. 14/03	dim. 15/03	lun. 16/03	mar. 17/03
	1	2	2	3	3	3	2

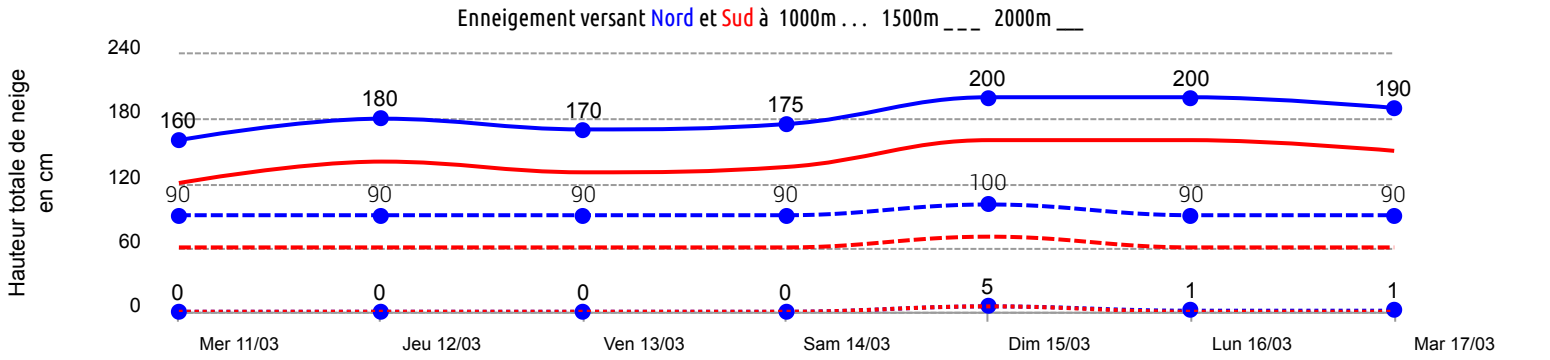

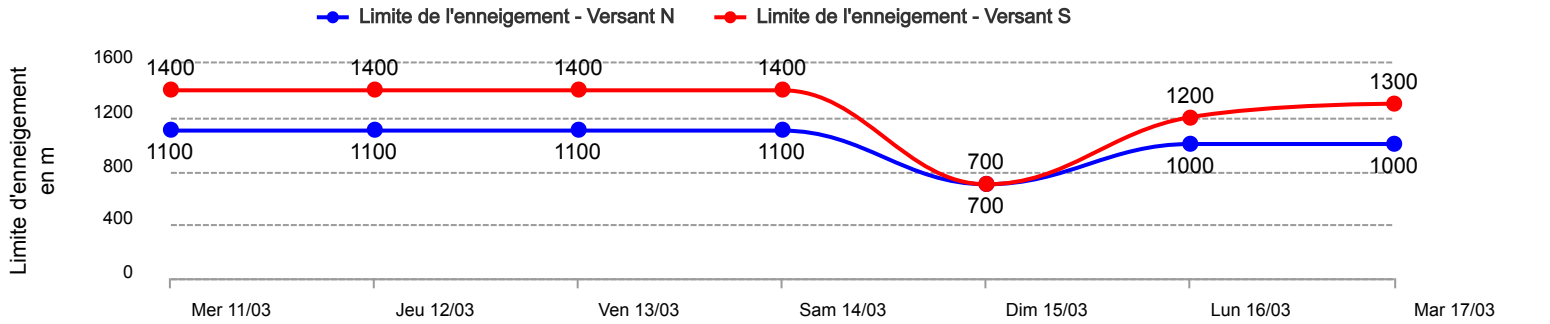

Pour consulter la vigilance en cours, veuillez vous rendre sur le site https://vigilance.meteofrance.fr/fr

Météo-France - 73 avenue de Paris, 94165 Saint-Mandé cedex - Contact : contact@meteo.fr

Bulletin neige & avalanches par téléphone au

0 892 68 10 20 Service 0,35 € / min + prix appel

Rédigé par Météo-France avec la contribution des observateurs du réseau nivo-météorologiques. Partenariat : ANMSM (Maires de Stations de Montagne), DSF (Domaines Skiables de France), ADSP (Directeurs de Pistes et de la Sécurité des Stations de Sports d'Hiver) et autres acteurs de la montagne.