RÉPUBLIQUE FRANÇAISE
Liberté Égalité Fraternité

METEO FRANCE
À VOS CÔTÉS, DANS UN CLIMAT QUI CHANGE

Bulletin d'estimation du risque d'avalanche

(valable en dehors des pistes balisées et ouvertes)

MASSIF : Aspe Ossau

Rédigé le mardi 17 mars 2026 à 16h

Estimation des risques pour le : MERCREDI 18 MARS

HUMIDIFICATION EN COURS, PLAQUES INSTABLES EN NORD AU-DESSUS DE 2300M.

3

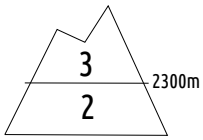

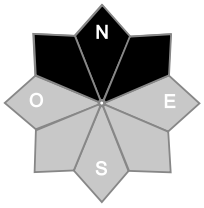

Au-dessus de 2300m indice de risque marqué, plus bas indice limité.

Départs spontanés : en neige humide au soleil.

Déclenchements provoqués : plaques instables au-dessus de 2300m.

Indices de risque : 5 très fort - 4 fort - 3 marqué - 2 limité - 1 faible -- En noir : les pentes les plus dangereuses

Stabilité du manteau neigeux

Situation avalancheuse typique : neige ventée neige humide

Déclenchements provoqués : **risque marqué** dans **quelques pentes Nord raides** d'altitude.
- **structures de plaques instables** encore présentes en **Nord-Ouest, Nord et Nord-Est**, **facilement déclenchables par faible sollicitation au-dessus de 2300m**. Avalanches **souvent de taille 1 à 2 attendues, localement taille 3 possibles** en skiant une **accumulation ou une combe encore chargée par ses abords** : la **couche fragile peu enfouie**, constituée depuis le week-end dernier de neige roulée, de neige récente peu transformée ou de grains anguleux en cours de formation sous les nuits claires des derniers jours, y **reste sensible à la moindre surcharge**.
- dans tous **les autres secteurs**, **peu de risque** de déclenchement **au petit matin grâce au regel efficace** du un manteau neigeux, puis **déclenchement par forte sollicitation de la neige s'humidifiant au soleil**.

Observables : au-dessus de 2200 à 2300m, signes de transport par le vent très visibles, fissures possibles sous les skis ou les raquettes, quelques affaissements dans les combes.

Départs spontanés :
- regel nocturne efficace, donc **pas ou très peu d'activité au petit matin**. Pour la journée, **départs ponctuels de petite taille dans les secteurs raides** en fonction de la course du **soleil**.
- **cassure linaire** avec le déclenchement d'une **avalanche de fond de taille moyenne à grande** toujours possible au **niveau d'une fissure ou d'une rupture de pente** par humidification de la couche fragile décrite ci-dessus (en secteurs **Est en matinée, Sud à Sud-Ouest l'après-midi** avec quelques accumulations).

Observables : "gueules de baleines" en Est, Sud et Ouest.

Autres : neige dure et regelée au petit matin, devenant très humide et très molle au soleil, pont de neige et corniches encore en place fragilisés.

Qualité de la neige

Enneigement : correct pour la saison, surtout au-dessus de 1800 m, mais reste assez maigre en versants exposés au vent d'ouest. Il débute assez bas, mais n'est skiable qu'à partir de 1600m en nord, plutôt 1800 en sud, faute de sous-couche.
État de la neige : qualité très variable au petit matin : en expositions ombragées au-dessus de 2300m, la neige est encore sèche, finement regelée entre 1900 et 2300m, regelée et dure en dessous. Zones pelées en neige très dure ou en glace près des cols et des sommets. En journée, conditions de printemps : la neige ramollit et s'alourdit au soleil, la neige restée sèche s'humidifie un peu plus en profondeur en secteurs Nord jusque 2400/2500m, reste sèche et frittée à cartonnée dans les pentes raides au-dessus.

Aperçu météo pour le mercredi 18 mars

	nuit	matin	après-midi	soir
Beau temps sec et doux, quelques nuages l'après-midi.				
Pluie-Neige				
Iso 0 °C	3 300 m	3 300 m	3 300 m	3 000 m
Vent 1500 m	10 km/h	0 km/h	5 km/h	10 km/h
Vent 3000 m	15 km/h	10 km/h	15 km/h	20 km/h

Pour consulter la vigilance en cours, veuillez vous rendre sur le site https://vigilance.meteofrance.fr/fr

Météo-France - 73 avenue de Paris, 94165 Saint-Mandé cedex - Contact : contact@meteo.fr

Rédigé par Météo-France avec la contribution des observateurs du réseau nivo-météorologiques. Partenariat : ANMSM (Maires de Stations de Montagne), DSF (Domaines Skiables de France), ADSP (Directeurs de Pistes et de la Sécurité des Stations de Sports d'Hiver) et autres acteurs de la montagne.

Bulletin neige & avalanches par téléphone au
0 892 68 10 20 Service 0,35 € / min + prix appel

Bulletin d'estimation du risque d'avalanche

(valable en dehors des pistes balisées et ouvertes)

MASSIF : Aspe Ossau

Rédigé le mardi 17 mars 2026 à 16h

Épaisseur de neige hors-piste

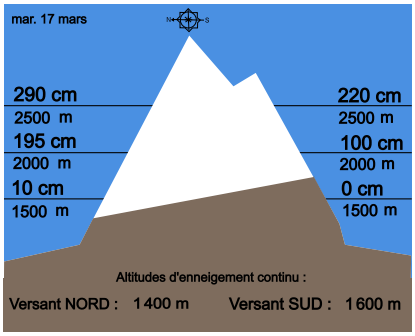

Précipitations à 1800 m

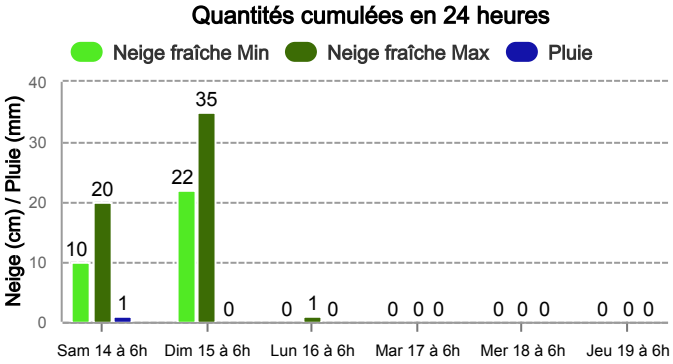

Tendance du jeudi 19 mars

Indice de risque limité

Le tassement des plaques continue, l'humidification progresse, le risque est en baisse.

Pour consulter la vigilance en cours, veuillez vous rendre sur le site https://vigilance.meteofrance.fr/fr

Météo-France - 73 avenue de Paris, 94165 Saint-Mandé cedex - Contact : contact@meteo.fr

Rédigé par Météo-France avec la contribution des observateurs du réseau nivo-météorologiques. Partenariat : ANMSM (Maires de Stations de Montagne), DSF (Domaines Skiables de France), ADSP (Directeurs de Pistes et de la Sécurité des Stations de Sports d'Hiver) et autres acteurs de la montagne.

Bulletin neige & avalanches par téléphone au

0 892 68 10 20 Service 0,35 € / min + prix appel

RÉPUBLIQUE FRANÇAISE
Liberté Égalité Fraternité

METEO FRANCE
À VOS CÔTÉS, DANS UN CLIMAT QUI CHANGE

Bulletin d'estimation du risque d'avalanche

(valable en dehors des pistes balisées et ouvertes)

MASSIF : Aspe Ossau

Rédigé le mardi 17 mars 2026 à 16h

Conditions nivo-météo des 7 derniers jours

	mer. 11/03				jeu. 12/03				ven. 13/03				sam. 14/03				dim. 15/03				lun. 16/03				mar. 17/03			
	03h	09h	15h	21h	03h	09h	15h	21h	03h	09h	15h	21h	03h	09h	15h	21h	03h	09h	15h	21h	03h	09h	15h	21h	03h	09h	15h	21h
Météo																												
Vent (km/h)	40	60	60	55	40	30	55	60	35	60	60	50	55	60	80	95	100	95	85	60	35	35	40	30	25	20	15	15
à 3000m																												
Vent (km/h)	20	15	15	5	10	5	15	10	10	20	20	25	25	30	45	50	60	55	40	20	20	20	10	5	10	10	10	10
à 1500m																												

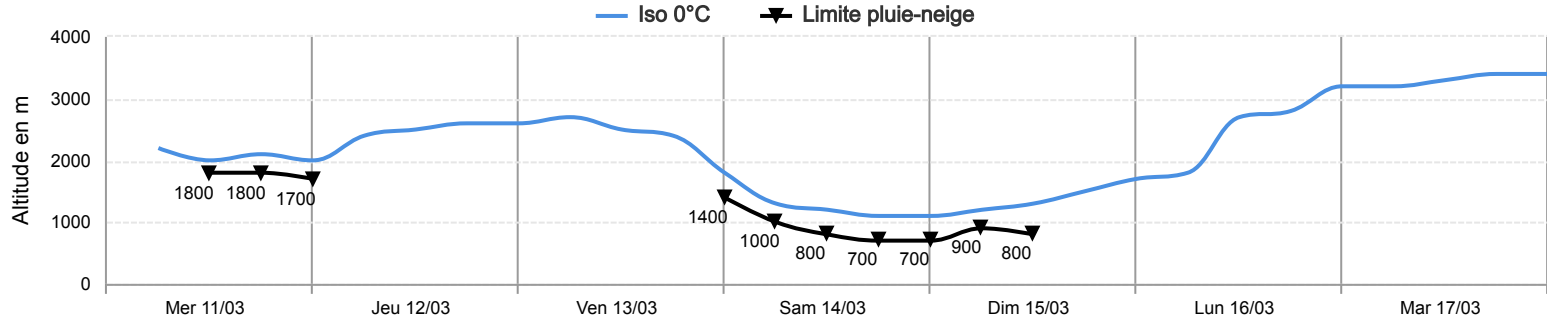

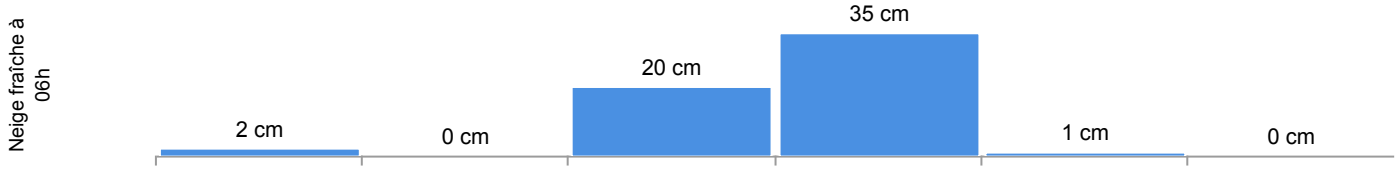

Risque d'avalanche	mer. 11/03	jeu. 12/03	ven. 13/03	sam. 14/03	dim. 15/03	lun. 16/03	mar. 17/03
	2	2	2	3	3	3	3

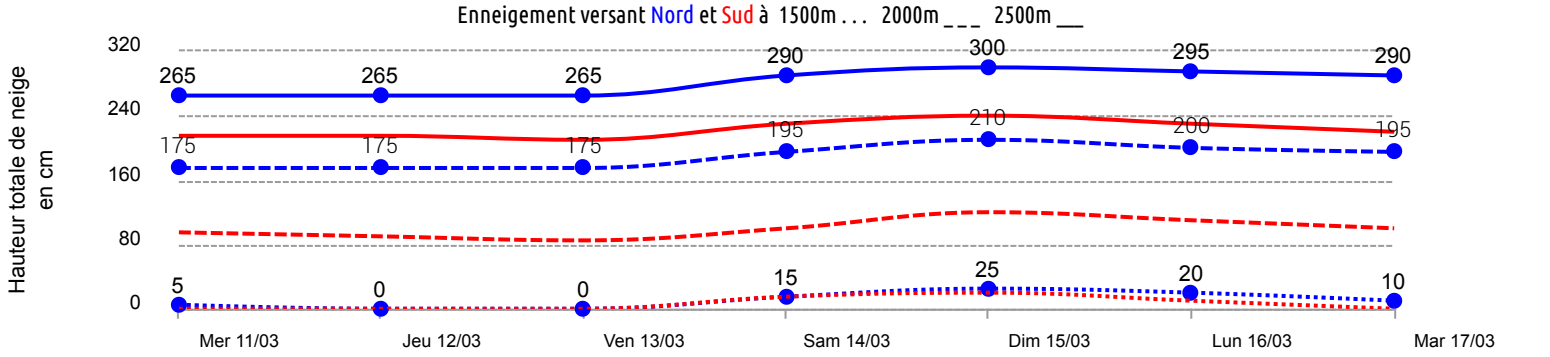

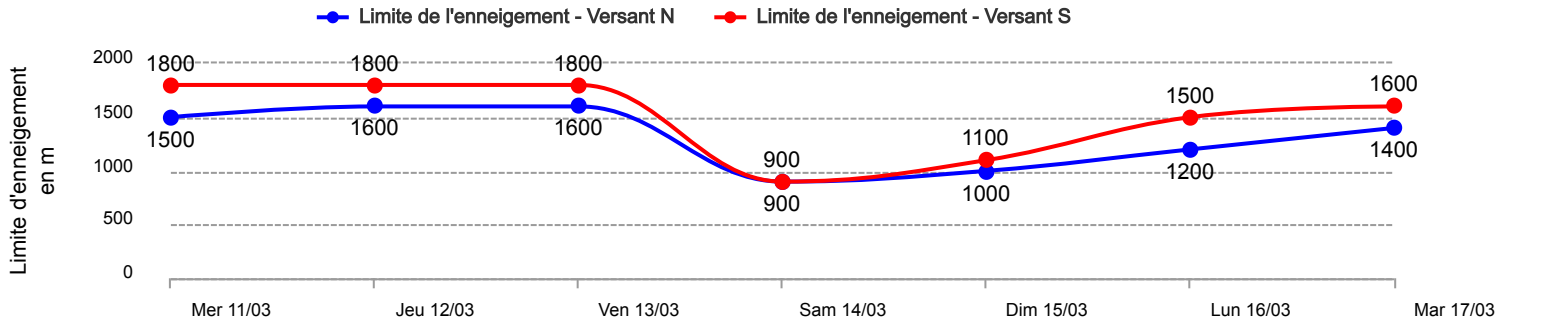

Pour consulter la vigilance en cours, veuillez vous rendre sur le site https://vigilance.meteofrance.fr/fr

Météo-France - 73 avenue de Paris, 94165 Saint-Mandé cedex - Contact : contact@meteo.fr

Rédigé par Météo-France avec la contribution des observateurs du réseau nivo-météorologiques. Partenariat : ANMSM (Maires de Stations de Montagne), DSF (Domaines Skiables de France), ADSP (Directeurs de Pistes et de la Sécurité des Stations de Sports d'Hiver) et autres acteurs de la montagne.

Bulletin neige & avalanches par téléphone au

0 892 68 10 20 Service 0,35 € / min + prix appel