Bulletin d'estimation du risque d'avalanche
(valable en dehors des pistes balisées et ouvertes)

MASSIF : Bauges

Rédigé le mardi 17 mars 2026 à 16h

Estimation des risques pour le : MERCREDI 18 MARS

ENCORE DE RARES INSTABILITÉS EN UBACS D'ALTITUDE.

2

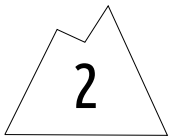

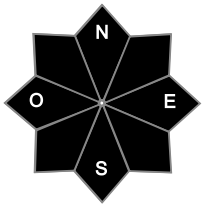

Indice de risque limité.

Départs spontanés : Rares plaques de fond

Déclenchements provoqués : Plaques à vent en ubacs d'altitude.

Indices de risque : 5 très fort - 4 fort - 3 marqué - 2 limité - 1 faible -- En noir : les pentes les plus dangereuses

Stabilité du manteau neigeux

Situation avalancheuse typique : neige ventée avalanches de fond

Départs spontanés :
* Rares avalanches de fond, dans les zones herbeuses ou les dalles rocheuses. Taille 1 à 2 (petite à moyenne).
* Avalanches de neige humide dans les adrets. De plus en plus nombreuses au fil de l'ensoleillement. Taille 1 à 2 dans les adrets les plus raides.

Déclenchements provoqués :
* **Au-dessus de 1800 m** : **quelques plaques à vent.** Formés par le vent de N/NW/NE des derniers jours et en cours de formation en journée par le vent de S/SE. Elles sont situées **surtout près des crêtes en ubacs. Assez facile à déclencher**. Taille 1 à 2 (petite à moyenne).

Observables : vaguelettes, fissures devant les skis, zones d'accumulations…

Qualité de la neige

Enneigement :
Il est correct pour la saison. En matinée, on retrouve de la neige dès 1000/1200 m. On retrouve un manteau réellement skiable à partir de 1200/1300 m en Nord et 1500/1600m en Sud.

Qualité de la neige mercredi :
* En dessous de 1600/1800 m : neige regelée le matin sur un fond humide. La croute s'humidifie au fil des heures.
* Au-dessus de 1600/1800 m :
- versant nord : Soufflé près des crêtes, plus poudreux dense loin des secteurs exposés au vent de N
- versant E/SE : la neige décaille légèrement en début de matinée avant de durcir de nouveau sous l'effet du vent de SE.
- W/SW : La neige reste légèrement croutée en journée et a du mal à décailler sous l'effet du vent.

Aperçu météo pour le mercredi 18 mars

nuit	matin	après-midi	soir

Ensoleillé, quelques nuages l'après-midi. Bise puis vent de SE à partir du milieu de journée. Températures en baisse : à 1500 m : -2 à 7°C.

Pluie-Neige				
Iso 0 °C	2 500 m	2 200 m	2 000 m	2 000 m
Vent 1500 m	↙ 15 km/h	↖ 15 km/h	↖ 20 km/h	↖ 15 km/h
Vent 2000 m	↙ 25 km/h	↓ 25 km/h	↖ 30 km/h	↖ 25 km/h

Épaisseur de neige hors-piste

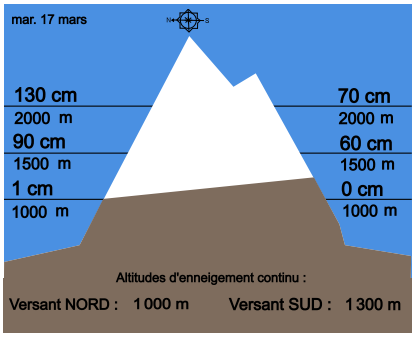

Précipitations à 1800 m

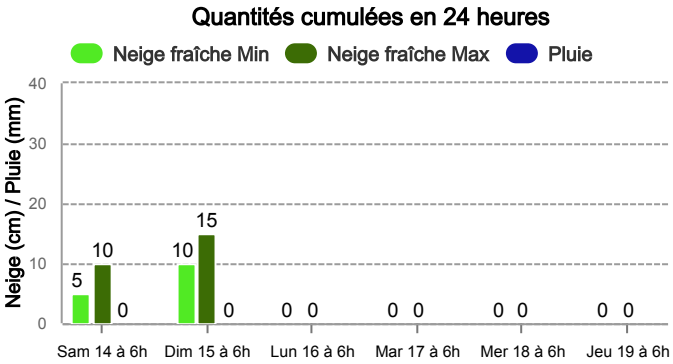

Tendance du jeudi 19 mars

2

Indice de risque limité

Risque en baisse. Vent en baisse, grand soleil.

Pour consulter la vigilance en cours, veuillez vous rendre sur le site https://vigilance.meteofrance.fr/fr

Météo-France - 73 avenue de Paris, 94165 Saint-Mandé cedex - Contact : contact@meteo.fr

Rédigé par Météo-France avec la contribution des observateurs du réseau nivo-météorologiques. Partenariat : ANMSM (Maires de Stations de Montagne), DSF (Domaines Skiables de France), ADSP (Directeurs de Pistes et de la Sécurité des Stations de Sports d'Hiver) et autres acteurs de la montagne.

Bulletin neige & avalanches par téléphone au 0 892 68 10 20 Service 0,35 € / min + prix appel

RÉPUBLIQUE FRANÇAISE
Liberté Égalité Fraternité

METEO FRANCE
À VOS CÔTÉS, DANS UN CLIMAT QUI CHANGE

Bulletin d'estimation du risque d'avalanche

(valable en dehors des pistes balisées et ouvertes)

MASSIF : Bauges

Rédigé le mardi 17 mars 2026 à 16h

Conditions nivo-météo des 7 derniers jours

	mer. 11/03				jeu. 12/03				ven. 13/03				sam. 14/03				dim. 15/03				lun. 16/03				mar. 17/03			
	03h	09h	15h	21h	03h	09h	15h	21h	03h	09h	15h	21h	03h	09h	15h	21h	03h	09h	15h	21h	03h	09h	15h	21h	03h	09h	15h	21h
Météo																												
Vent (km/h)	30	40	40	40	20	10	5	5	20	30	40	60	45	35	25	25	35	25	30	15	15	20	20	15	25	25	30	30
à 2000m																												
Vent (km/h)	20	20	30	30	15	5	0	0	10	20	25	50	35	25	20	20	30	20	25	10	10	15	15	10	15	15	20	20
à 1500m																												

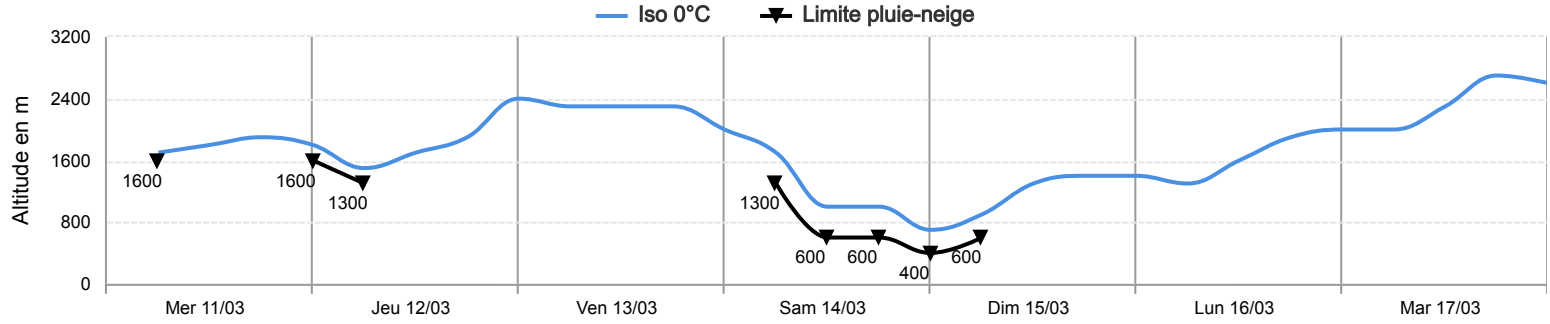

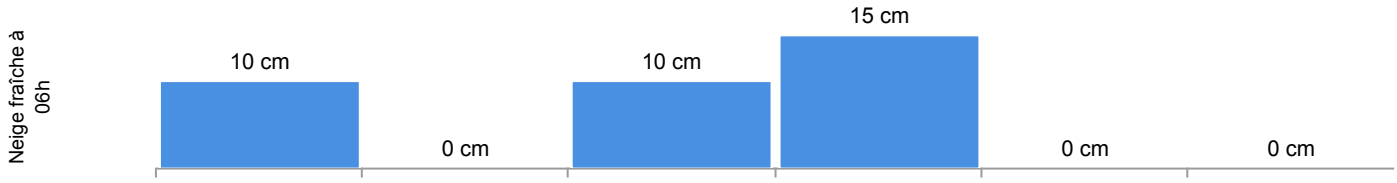

Risque d'avalanche	mer. 11/03	jeu. 12/03	ven. 13/03	sam. 14/03	dim. 15/03	lun. 16/03	mar. 17/03
	1	2	2	3	3	2	2

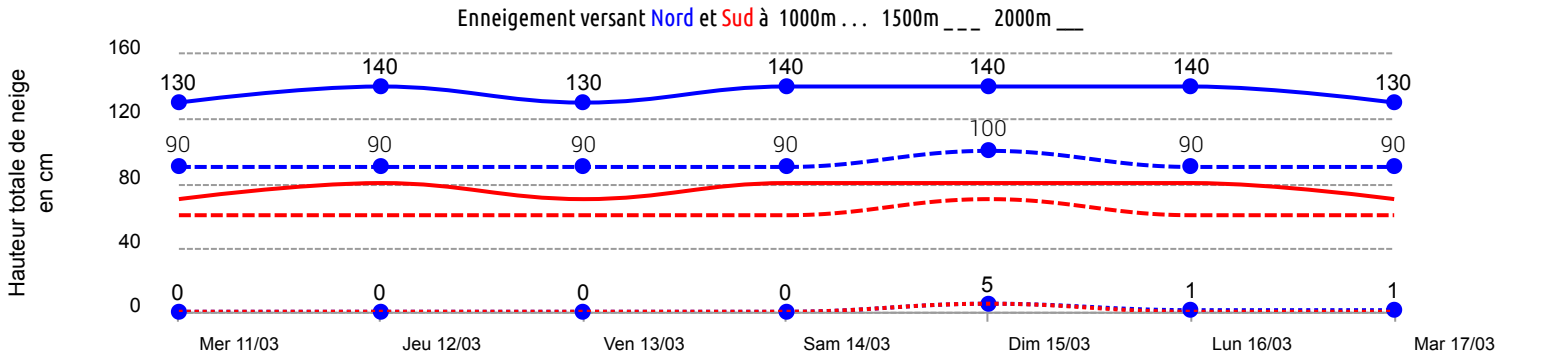

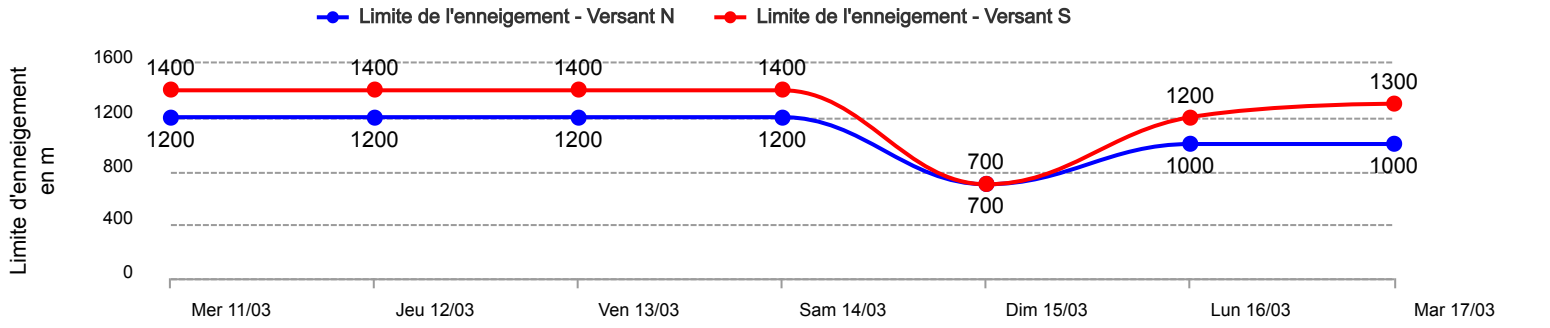

Pour consulter la vigilance en cours, veuillez vous rendre sur le site https://vigilance.meteofrance.fr/fr

Météo-France - 73 avenue de Paris, 94165 Saint-Mandé cedex - Contact : contact@meteo.fr

Rédigé par Météo-France avec la contribution des observateurs du réseau nivo-météorologiques. Partenariat : ANMSM (Maires de Stations de Montagne), DSF (Domaines Skiables de France), ADSP (Directeurs de Pistes et de la Sécurité des Stations de Sports d'Hiver) et autres acteurs de la montagne.

Bulletin neige & avalanches par téléphone au

0 892 68 10 20 Service 0,35 € / min + prix appel