RÉPUBLIQUE FRANÇAISE
Liberté Égalité Fraternité

METEO FRANCE
À VOS CÔTÉS, DANS UN CLIMAT QUI CHANGE

Bulletin d'estimation du risque d'avalanche
(valable en dehors des pistes balisées et ouvertes)
MASSIF : Beaufortain

Rédigé le mardi 17 mars 2026 à 16h

Estimation des risques pour le : MERCREDI 18 MARS

COUP DE VENT ET NOUVELLES PLAQUES DES LA MI-JOURNEE.

3

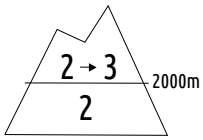

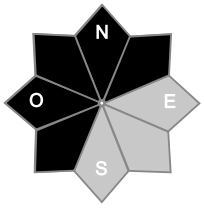

Au-dessus de 2000m indice de risque limité évoluant en marqué, plus bas indice limité.

Départs spontanés : quelques départs de plaques dans le très raide.

Déclenchements provoqués : formation de nouvelles plaques dès la mi-journée.

Indices de risque : 5 très fort - 4 fort - 3 marqué - 2 limité - 1 faible -- En noir : les pentes les plus dangereuses

Stabilité du manteau neigeux

Situation avalancheuse typique : neige ventée

Déclenchements provoqués : à partir de la mi-journée, le franc coup de vent d'Est va former des plaques là où la neige récente est transportée. On les trouve autant aux abords des crêtes qu'en pied de pente. Etant en cours de formation, elles sont très réactives au passage d'un skieur, surtout dans les versants NO, N et NE qui conservent un manteau hivernal. Elles gagnent en épaisseur au fil des heures. Avalanches moyennes (taille 2) possibles en fin de journée. **Observable :** le transport de neige en cours.
Facteur aggravant : la dernière chute de neige s'est localement déposée sur une fine couche de grains anguleux, en versant NO, N et NE au-delà de 2400 m, ce qui tend à augmenter le volume de neige mobilisable, et donc la taille des avalanches.

Départs spontanés : à partir de la mi-journée, le transport de la neige par le vent d'Est engendre des départs de petites plaques dans les pentes raides, aux abords des crêtes, derrière les bosses... là où la neige se dépose. Petites à moyennes avalanches.

Qualité de la neige

Enneigement : généralement très bon, sauf aux basses altitudes où les hauteurs de neige sont tout juste correctes pour la saison.

Limite skiable : encore skiable dès 1100/1200 m dans les prairies orientées nord, plutôt 1400/1500 m en sud pas trop raide.

Qualité de la neige :
- en versants ombragés, crouté sous 1700/1900 m puis couche de neige récente meuble de plus en plus conséquente avec l'altitude (20/40 cm passé 2000 m), parfois redistribuée ou densifiée par le vent (neige dure sur les crêtes).
- en versants ensoleillés, neige croutée le matin qui décaille en Est et Sud, tant que le vent ne souffle pas trop fort. L'après-midi, les versants SO et O d'altitude soumis au vent ne décaillent pas.

Aperçu météo pour le mercredi 18 mars

nuit	matin	après-midi	soir

Belle entame de journée. Coup de vent d'Est à partir de la fin de matinée.

Pluie-Neige				
Iso 0 °C	2 600 m	2 300 m	1 900 m	1 900 m
Vent 2000 m	↖ 10 km/h	↙ 20 km/h	← 40 km/h	← 35 km/h
Vent 3000 m	↙ 20 km/h	↙ 35 km/h	← 60 km/h	← 50 km/h

Épaisseur de neige hors-piste

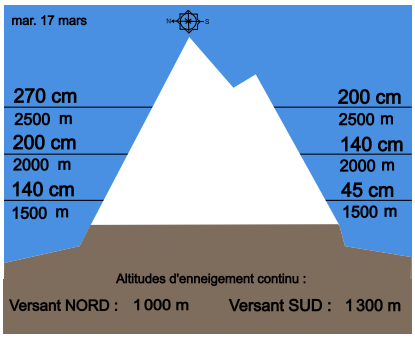

Précipitations à 1800 m

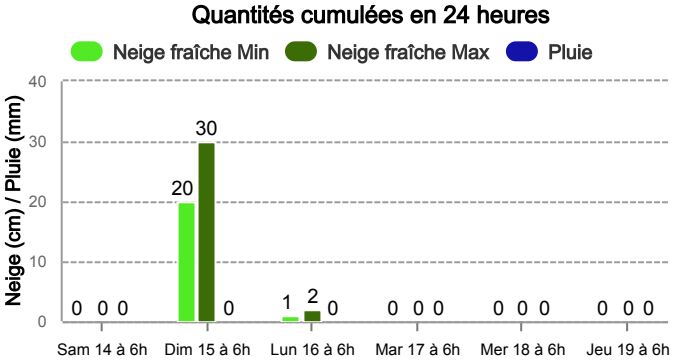

Tendance du jeudi 19 mars

3

Indice de risque marqué

Les structures de plaque récemment formées entament leur stabilisation. En fonction de la sévérité de l'épisode de vent de ce mercredi, le risque marqué s'envisage un jour de plus.

Pour consulter la vigilance en cours, veuillez vous rendre sur le site https://vigilance.meteofrance.fr/fr

Météo-France - 73 avenue de Paris, 94165 Saint-Mandé cedex - Contact : contact@meteo.fr

Rédigé par Météo-France avec la contribution des observateurs du réseau nivo-météorologiques. Partenariat : ANMSM (Maires de Stations de Montagne), DSF (Domaines Skiables de France), ADSP (Directeurs de Pistes et de la Sécurité des Stations de Sports d'Hiver) et autres acteurs de la montagne.

Bulletin neige & avalanches par téléphone au
0 892 68 10 20 Service 0,35 € / min + prix appel

RÉPUBLIQUE FRANÇAISE
Liberté Égalité Fraternité

METEO FRANCE
À VOS CÔTÉS, DANS UN CLIMAT QUI CHANGE

Bulletin d'estimation du risque d'avalanche

(valable en dehors des pistes balisées et ouvertes)

MASSIF : Beaufortain

Rédigé le mardi 17 mars 2026 à 16h

Conditions nivo-météo des 7 derniers jours

	mer. 11/03				jeu. 12/03				ven. 13/03				sam. 14/03				dim. 15/03				lun. 16/03				mar. 17/03			
	03h	09h	15h	21h	03h	09h	15h	21h	03h	09h	15h	21h	03h	09h	15h	21h	03h	09h	15h	21h	03h	09h	15h	21h	03h	09h	15h	21h
Météo																												
Vent (km/h)	25	25	30	40	30	25	20	20	20	25	30	65	50	25	30	40	35	40	15	10	20	30	30	20	20	20	20	20
à 3000m																												
Vent (km/h)	15	15	20	30	20	15	10	10	10	10	15	40	35	15	20	30	30	30	10	5	10	15	20	10	10	10	10	10
à 2000m																												

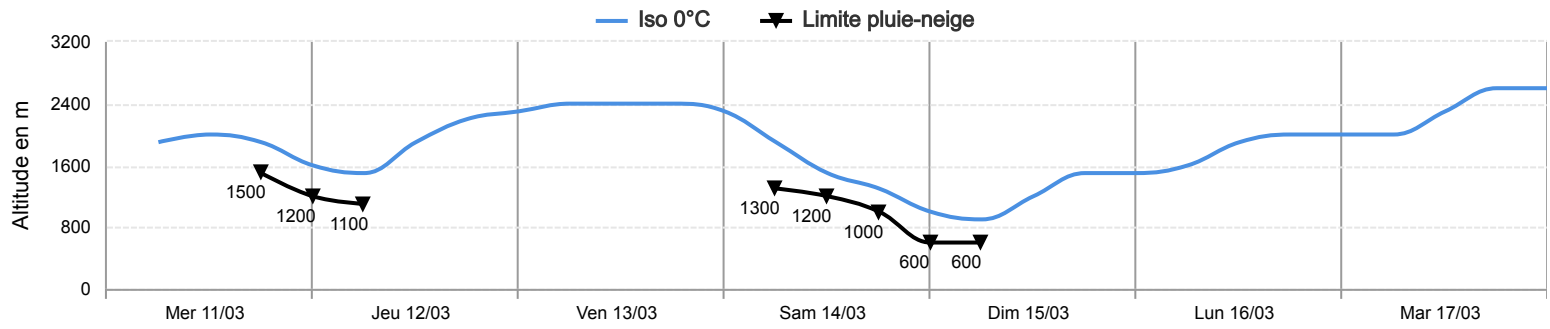

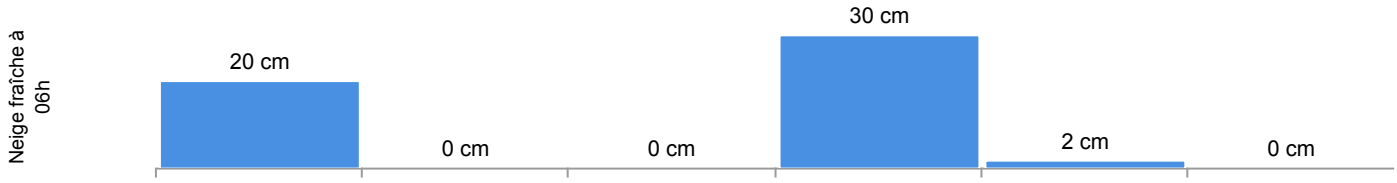

Risque d'avalanche	mer. 11/03	jeu. 12/03	ven. 13/03	sam. 14/03	dim. 15/03	lun. 16/03	mar. 17/03
	1	2	2	3	3	3	2

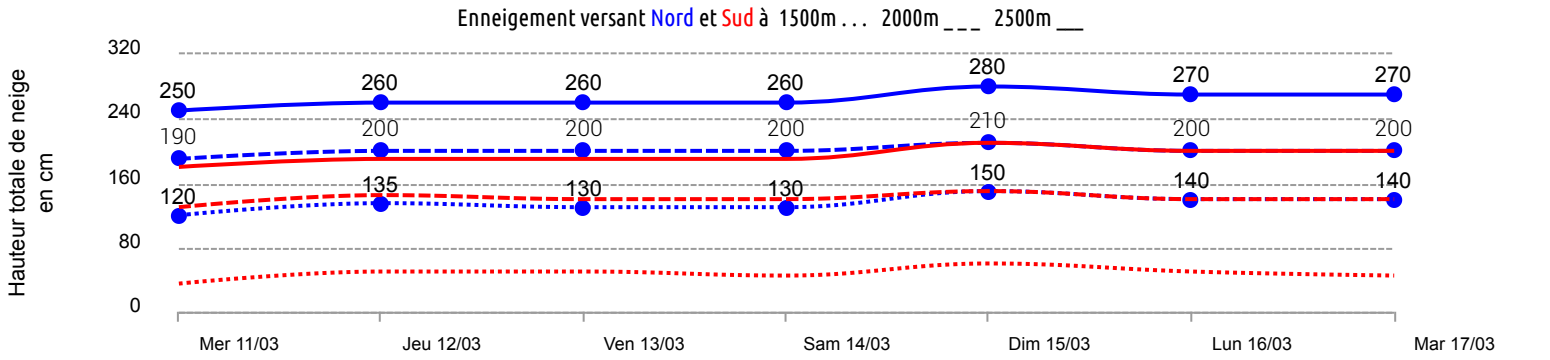

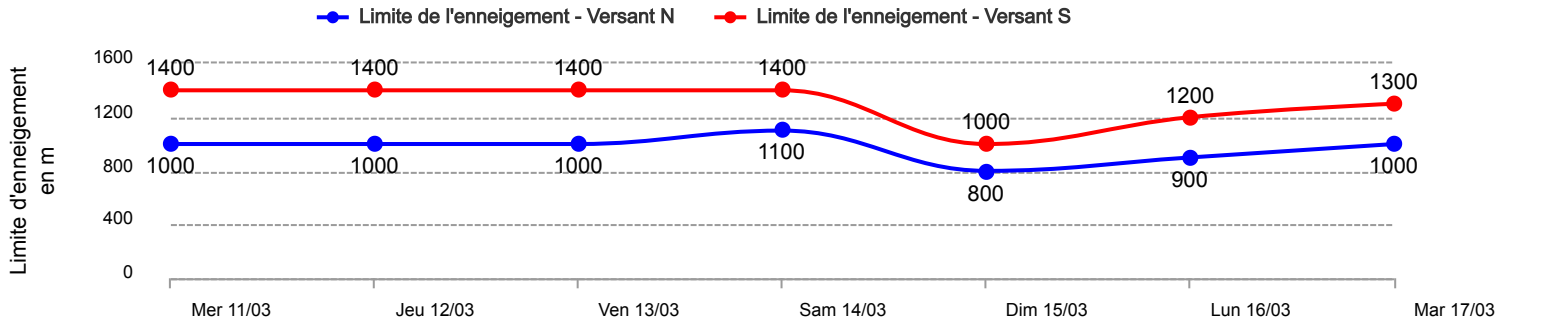

Pour consulter la vigilance en cours, veuillez vous rendre sur le site https://vigilance.meteofrance.fr/fr

Météo-France - 73 avenue de Paris, 94165 Saint-Mandé cedex - Contact : contact@meteo.fr

Bulletin neige & avalanches par téléphone au

0 892 68 10 20 Service 0,35 € / min + prix appel

Rédigé par Météo-France avec la contribution des observateurs du réseau nivo-météorologiques. Partenariat : ANMSM (Maires de Stations de Montagne), DSF (Domaines Skiables de France), ADSP (Directeurs de Pistes et de la Sécurité des Stations de Sports d'Hiver) et autres acteurs de la montagne.