Bulletin d'estimation du risque d'avalanche

(valable en dehors des pistes balisées et ouvertes)

MASSIF : Chartreuse

Rédigé le mardi 17 mars 2026 à 16h

Estimation des risques pour le : MERCREDI 18 MARS

QUELQUES INSTABILITÉS EN VERSANT FROID.

2

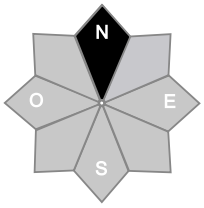

Indice de risque limité.

Départs spontanés : Peu probables.

Déclenchements provoqués : Rares plaques de neige soufflée dans les versants ombragés.

Indices de risque : 5 très fort - 4 fort - 3 marqué - 2 limité - 1 faible -- En noir : les pentes les plus dangereuses

Stabilité du manteau neigeux

Situation avalancheuse typique : neige ventée

Déclenchements provoqués : Le manteau neigeux s'est bien consolidé depuis les dernières chutes de neige. Le risque de déclenchement se limite à quelques avalanches de plaque formées par le vent de nord, peu épaisses et situées surtout près des crêtes des versants ombragés.

Départs spontanés : Après un bon regel nocturne, l'humidification du manteau neigeux sera assez faible mercredi. Très peu d'activité avalancheuse naturelle à redouter.

Qualité de la neige

Qualification de l'enneigement : L'enneigement est bon pour la saison en versants ombragés au dessus de 1300 m. Il est correct en Sud mais les sous-couches sont rares sous 1700/1800 m.
Limites skiables : Vers 1200/1700 m selon les versants.

Qualité de la neige mercredi : Neige croûtée, s'humidifiant superficiellement en journée de mercredi dans les versants au soleil. Neige froide souvent travaillée par le vent dans les ubacs.

Aperçu météo pour le mercredi 18 mars

	nuit	matin	après-midi	soir
Pluie-Neige				
Iso 0 °C	2 900 m	2 600 m	2 100 m	2 000 m
Vent 1500 m	10 km/h	15 km/h	15 km/h	10 km/h
Vent 2000 m	25 km/h	25 km/h	35 km/h	40 km/h

Épaisseur de neige hors-piste

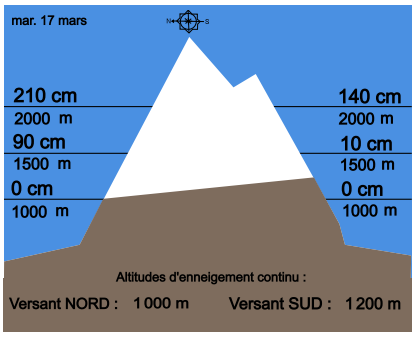

Précipitations à 1800 m

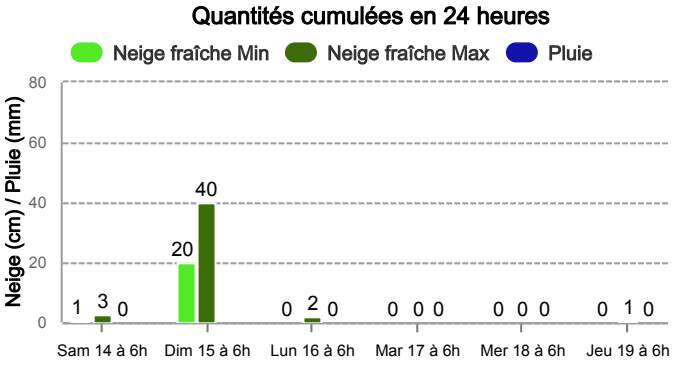

Tendance du jeudi 19 mars

2

Indice de risque limité

Poursuite de la stabilisation du manteau neigeux jeudi. Risques probablement en baisse.

Pour consulter la vigilance en cours, veuillez vous rendre sur le site https://vigilance.meteofrance.fr/fr

Météo-France - 73 avenue de Paris, 94165 Saint-Mandé cedex - Contact : contact@meteo.fr

Rédigé par Météo-France avec la contribution des observateurs du réseau nivo-météorologiques. Partenariat : ANMSM (Maires de Stations de Montagne), DSF (Domaines Skiables de France), ADSP (Directeurs de Pistes et de la Sécurité des Stations de Sports d'Hiver) et autres acteurs de la montagne.

Bulletin neige & avalanches par téléphone au 0 892 68 10 20 Service 0,35 € / min + prix appel

RÉPUBLIQUE FRANÇAISE
Liberté Égalité Fraternité

METEO FRANCE
À VOS CÔTÉS, DANS UN CLIMAT QUI CHANGE

Bulletin d'estimation du risque d'avalanche

(valable en dehors des pistes balisées et ouvertes)

MASSIF : Chartreuse

Rédigé le mardi 17 mars 2026 à 16h

Conditions nivo-météo des 7 derniers jours

	mer. 11/03				jeu. 12/03				ven. 13/03				sam. 14/03				dim. 15/03				lun. 16/03				mar. 17/03			
	03h	09h	15h	21h	03h	09h	15h	21h	03h	09h	15h	21h	03h	09h	15h	21h	03h	09h	15h	21h	03h	09h	15h	21h	03h	09h	15h	21h
Météo																												
Vent (km/h)	30	30	35	45	45	30	20	10	20	25	40	55	70	40	40	65	80	65	50	45	50	45	40	35	35	35	35	25
à 2000m																												
Vent (km/h)	20	25	30	20	25	20	15	5	10	15	30	40	45	20	25	50	70	45	40	25	35	30	25	20	15	15	10	10
à 1500m																												

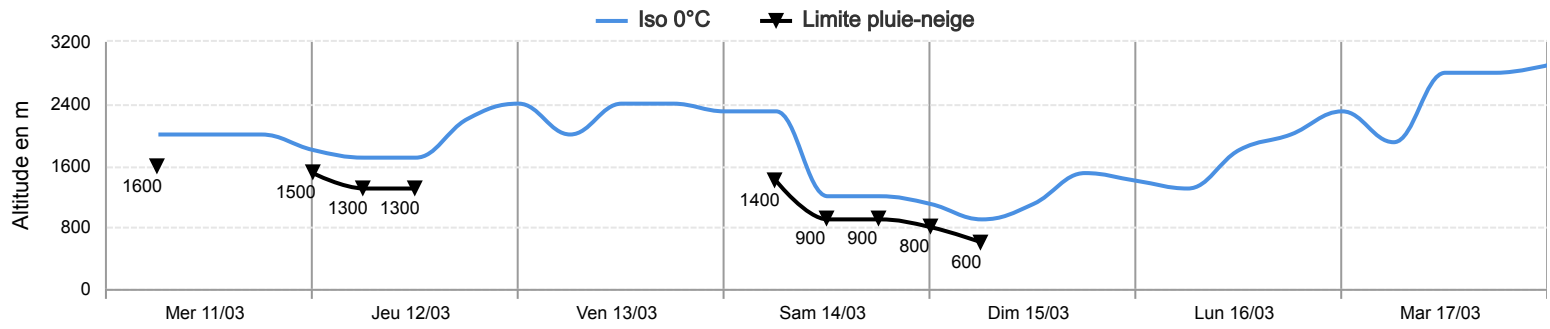

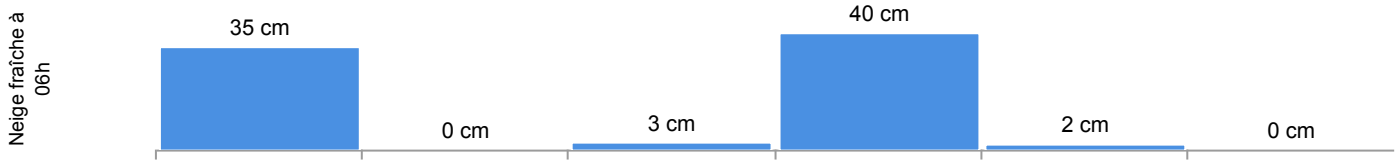

Risque d'avalanche	mer. 11/03	jeu. 12/03	ven. 13/03	sam. 14/03	dim. 15/03	lun. 16/03	mar. 17/03
	1	2	2	3	3	3	2

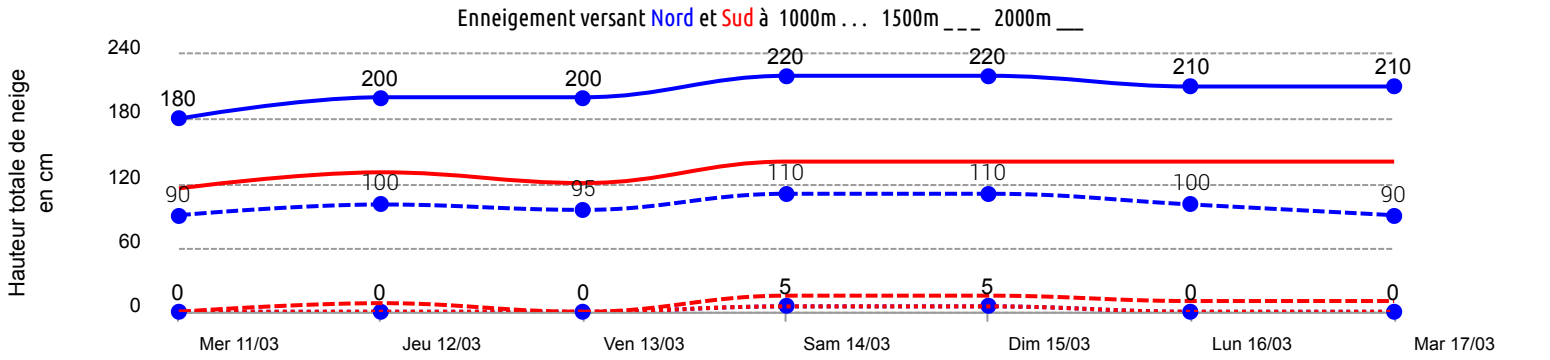

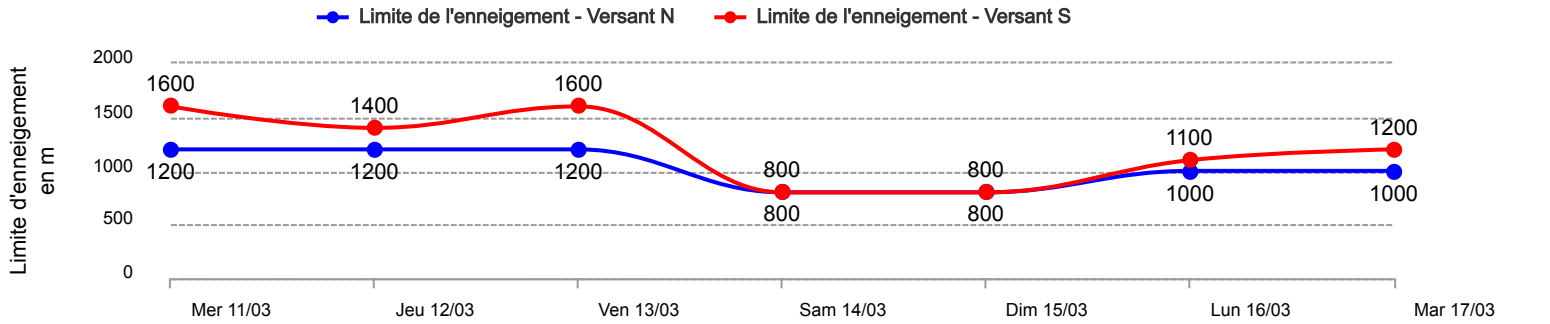

Pour consulter la vigilance en cours, veuillez vous rendre sur le site https://vigilance.meteofrance.fr/fr

Météo-France - 73 avenue de Paris, 94165 Saint-Mandé cedex - Contact : contact@meteo.fr

Rédigé par Météo-France avec la contribution des observateurs du réseau nivo-météorologiques. Partenariat : ANMSM (Maires de Stations de Montagne), DSF (Domaines Skiables de France), ADSP (Directeurs de Pistes et de la Sécurité des Stations de Sports d'Hiver) et autres acteurs de la montagne.

Bulletin neige & avalanches par téléphone au

0 892 68 10 20 Service 0,35 € / min + prix appel