# Bulletin d'estimation du risque d'avalanche
(valable en dehors des pistes balisées et ouvertes)

# MASSIF : Grandes-Rousses

Rédigé le mardi 17 mars 2026 à 16h

## Estimation des risques pour le : MERCREDI 18 MARS

**MANTEAU NEIGEUX MODÉRÉMENT STABILISÉ EN VERSANTS OMBRAGÉS.**

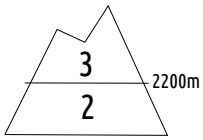


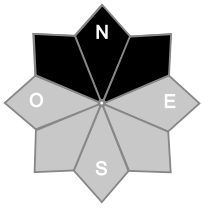


Au-dessus de 2200m indice de risque marqué, plus bas indice limité.

**Départs spontanés :** Peu probables.

**Déclenchements provoqués :** Quelques plaques en altitude.

Indices de risque : 5 très fort - 4 fort - 3 marqué - 2 limité - 1 faible -- En noir : les pentes les plus dangereuses

## Stabilité du manteau neigeux

**Situation avalancheuse typique :** neige ventée

Déclenchements provoqués : sous l'effet du soleil, le manteau neigeux s'est déjà bien consolidé dans les adrets. Cependant, il reste des plaques formées récemment par le vent de nord, essentiellement dans les versants froids à plus de 2200 m. Ces plaques sont constituées de neige plus ou moins compacte suivant l'action du vent, et les cassures ne dépassent généralement pas 20/40 cm. De nouvelles plaques, plus fines, pourraient se former en fin de journée sous l'effet du vent d'est.

Départs spontanés : Après un bon regel nocturne, l'humidification du manteau neigeux sera assez faible mercredi. Très peu d'activité avalancheuse naturelle à redouter.

## Qualité de la neige

**Qualification de l'enneigement :** L'enneigement est bon pour la saison en versants ombragés au dessus de 1300 m. Il est correct en Sud mais les sous-couches sont rares sous 1700/1800 m.
**Limites skiables :** Vers 1200/1600 m selon les versants.

**Qualité de la neige mercredi :** Neige croûtée, s'humidifiant superficiellement en journée de mercredi dans les versants au soleil. Neige froide souvent travaillée par le vent dans les ubacs. Très léger saupoudrage possible l'après-midi.

## Aperçu météo pour le mercredi 18 mars

| | nuit | matin | après-midi | soir |
|---|---|---|---|---|
| Pluie-Neige | | | | |
| Iso 0 °C | 2 900 m | 2 600 m | 2 200 m | 1 800 m |
| Vent 2000 m | 15 km/h | 15 km/h | 40 km/h | 40 km/h |
| Vent 3000 m | 30 km/h | 30 km/h | 45 km/h | 55 km/h |

## Épaisseur de neige hors-piste

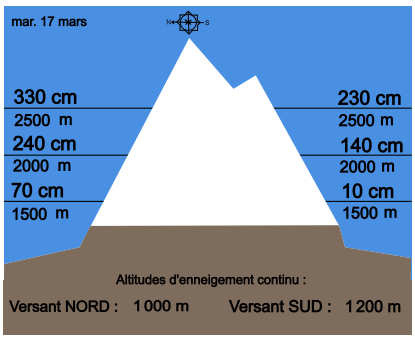


## Précipitations à 1800 m

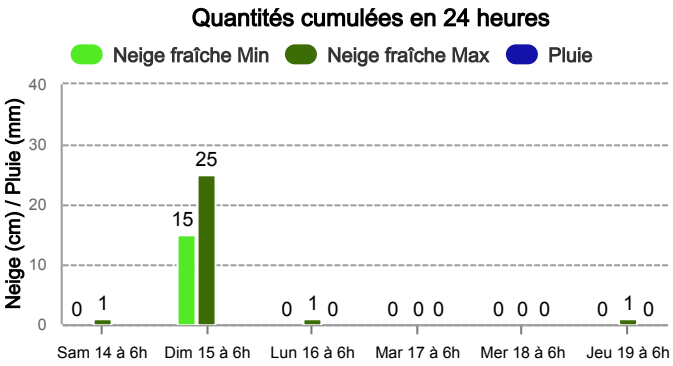


## Tendance du jeudi 19 mars

**Indice de risque limité**

Poursuite de la stabilisation du manteau neigeux jeudi. Risques probablement en baisse.

Pour consulter la vigilance en cours, veuillez vous rendre sur le site https://vigilance.meteofrance.fr/fr

Météo-France - 73 avenue de Paris, 94165 Saint-Mandé cedex - Contact : contact@meteo.fr

Rédigé par Météo-France avec la contribution des observateurs du réseau nivo-météorologiques. Partenariat : ANMSM (Maires de Stations de Montagne), DSF (Domaines Skiables de France), ADSP (Directeurs de Pistes et de la Sécurité des Stations de Sports d'Hiver) et autres acteurs de la montagne.

Bulletin neige & avalanches par téléphone au
0 892 68 10 20 Service 0,35 € / min + prix appel

RÉPUBLIQUE FRANÇAISE
*Liberté Égalité Fraternité*

METEO FRANCE
À VOS CÔTÉS, DANS UN CLIMAT QUI CHANGE

# Bulletin d'estimation du risque d'avalanche

## (valable en dehors des pistes balisées et ouvertes)

# MASSIF : Grandes-Rousses

Rédigé le mardi 17 mars 2026 à 16h

## Conditions nivo-météo des 7 derniers jours

| | mer. 11/03 | | | | jeu. 12/03 | | | | ven. 13/03 | | | | sam. 14/03 | | | | dim. 15/03 | | | | lun. 16/03 | | | | mar. 17/03 | | | |
|---|---|---|---|---|---|---|---|---|---|---|---|---|---|---|---|---|---|---|---|---|---|---|---|---|---|---|---|---|
| | 03h | 09h | 15h | 21h | 03h | 09h | 15h | 21h | 03h | 09h | 15h | 21h | 03h | 09h | 15h | 21h | 03h | 09h | 15h | 21h | 03h | 09h | 15h | 21h | 03h | 09h | 15h | 21h |
| Météo | | | | | | | | | | | | | | | | | | | | | | | | | | | | |
| Vent (km/h) | 20 | 30 | 35 | 25 | 40 | 50 | 20 | 10 | 15 | 20 | 35 | 45 | 60 | 40 | 25 | 65 | 70 | 40 | 45 | 35 | 45 | 35 | 45 | 35 | 25 | 15 | 20 | 20 |
| à 3000m | | | | | | | | | | | | | | | | | | | | | | | | | | | | |
| Vent (km/h) | 10 | 10 | 25 | 15 | 25 | 25 | 10 | 10 | 10 | 10 | 25 | 35 | 40 | 15 | 20 | 40 | 40 | 30 | 30 | 25 | 35 | 25 | 30 | 25 | 15 | 10 | 10 | 10 |
| à 2000m | | | | | | | | | | | | | | | | | | | | | | | | | | | | |

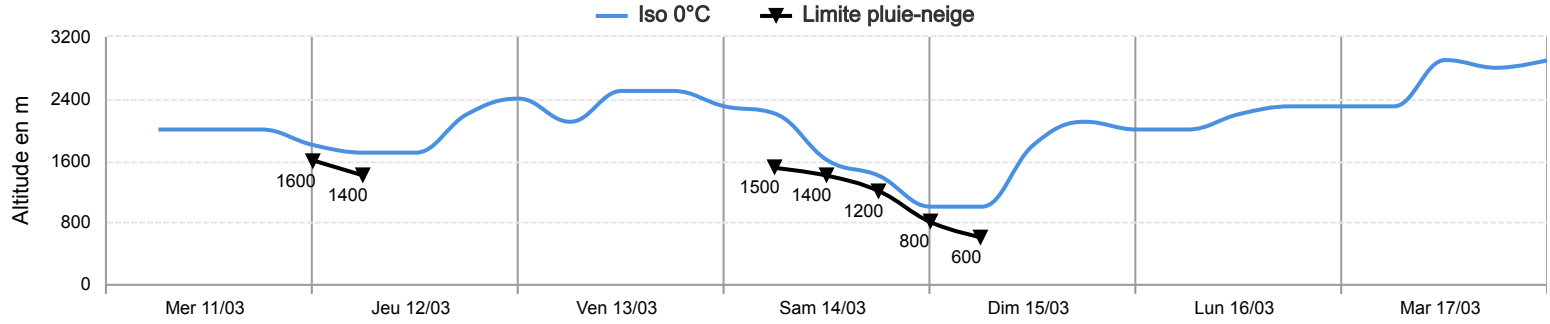


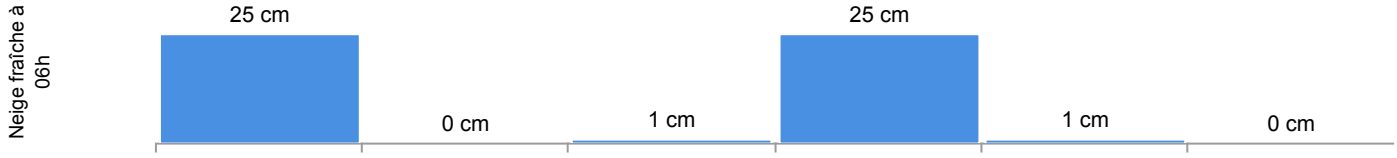


| Risque d'avalanche | mer. 11/03 | jeu. 12/03 | ven. 13/03 | sam. 14/03 | dim. 15/03 | lun. 16/03 | mar. 17/03 |
|---|---|---|---|---|---|---|---|
| | 2 | 2 | 3 | 3 | 3 | 3 | 3 |

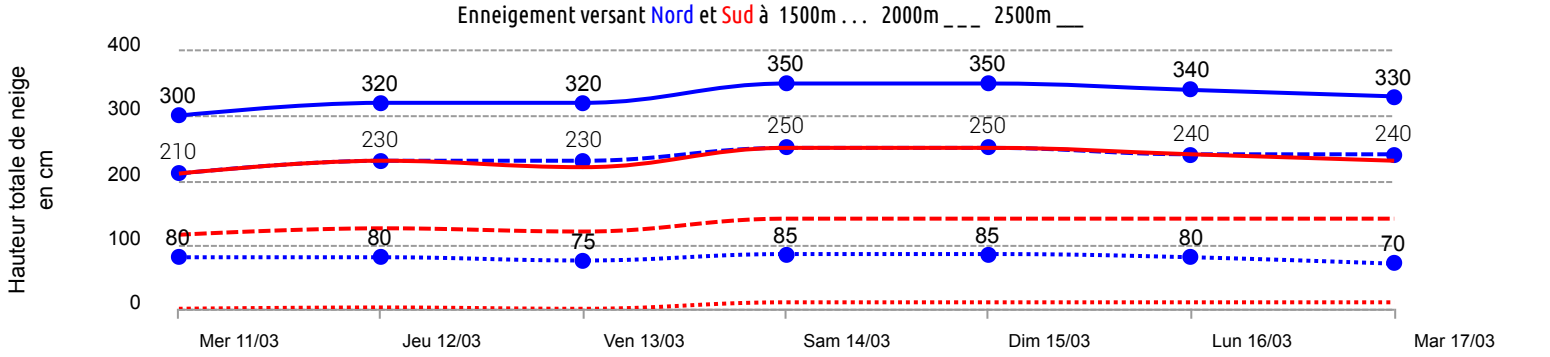


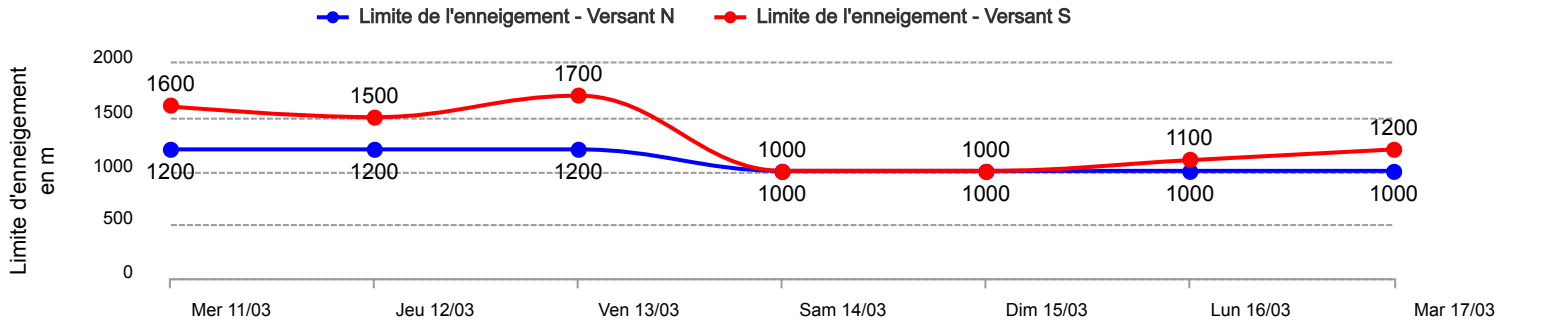


Pour consulter la vigilance en cours, veuillez vous rendre sur le site https://vigilance.meteofrance.fr/fr


Météo-France - 73 avenue de Paris, 94165 Saint-Mandé cedex - Contact : contact@meteo.fr


Bulletin neige & avalanches par téléphone au

0 892 68 10 20 Service 0,35 € / min + prix appel


Rédigé par Météo-France avec la contribution des observateurs du réseau nivo-météorologiques. Partenariat : ANMSM (Maires de Stations de Montagne), DSF (Domaines Skiables de France), ADSP (Directeurs de Pistes et de la Sécurité des Stations de Sports d'Hiver) et autres acteurs de la montagne.