Bulletin d'estimation du risque d'avalanche

(valable en dehors des pistes balisées et ouvertes)

MASSIF : Mercantour

Rédigé le mardi 17 mars 2026 à 16h

Estimation des risques pour le : MERCREDI 18 MARS

DES INSTABILITÉS DANS LA NEIGE VENTÉE

3

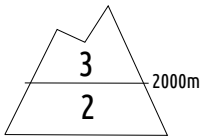

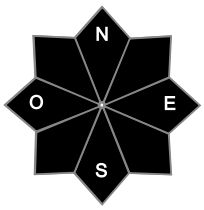

Au-dessus de 2000m indice de risque marqué, plus bas indice limité.

Départs spontanés : quelques départs de plaques suite au transport de neige par le vent.

Déclenchements provoqués : plaques faciles à déclencher dans la neige transportée par le vent.

Indices de risque : 5 très fort - 4 fort - 3 marqué - 2 limité - 1 faible -- En noir : les pentes les plus dangereuses

Stabilité du manteau neigeux

Situation avalancheuse typique : neige ventée

Déclenchements provoqués : de nouvelles plaques se forment tout au long de la journée, même loin des crêtes, avec le fort vent de nord à nord-est attendu. Au-dessus de 2000 m, ces plaques sont faciles à déclencher et assez fréquentes en contrebas des crêtes, derrière les ruptures de pente ou les bosses. Ces instabilités se trouvent plus fréquemment dans les ubacs où le manteau neigeux n'est pas printanier, mais des plaques se forment aussi derrière les crêtes en adrets, avec la neige rapportée depuis les versants ombragés. Avalanches souvent moyennes (taille 2), une rare grande (taille 3) non exclue en cas de sollicitation de la couche fragile persistante enfouie (suite au départ d'une plaque de surface par exemple).
Sous 2000 m, la probabilité de déclencher une plaque est plus limitée.

Départs spontanés : quelques plaques cèdent spontanément suite au transport de neige par le vent. Avalanches souvent moyennes (taille 2), rarement grandes (taille 3).

Qualité de la neige

Enneigement excédentaire dans la Roya, proche des normales sur le reste du massif.
Données observées : 160 cm à la Nivôse de Millefonts à 2430 m, 118 cm à Isola 2000 à 1912 m.

Enneigement skiable : vers 1400 m en ubacs, 1700/1800 m en adrets peu pentus.

État de la neige en surface : dans les adrets, neige souvent croûtée, parfois recouverte par un peu de neige fraîche ou par des accumulations de neige rapportée par le vent. Dans les ubacs, la neige reste froide au-dessus de 2000/2100 m environ, encore assez légère à l'abri du vent, mais de plus en plus travaillée ou durcie par le vent dans les secteurs exposés.

Aperçu météo pour le mercredi 18 mars

nuit	matin	après-midi	soir

Un peu de neige le matin et jusqu'en début d'après-midi (2 à 5 cm, jusqu'à 10/15 cm sur les crêtes frontalières de Vésubie/Roya). Net refroidissement. Neige soufflée par le vent de nord à nord-est qui devient très fort l'après-midi. Faible blocage neigeux frontalier la nuit suivante.

Pluie-Neige		1 200 m		1 100 m
Iso 0 °C	2 000 m	1 500 m	1 400 m	1 400 m
Vent 2000 m	↓ 15 km/h	↓ 45 km/h	↓ 65 km/h	↓ 70 km/h
Vent 3000 m	↘ 20 km/h	↙ 65 km/h	↙ 90 km/h	↙ 95 km/h

Épaisseur de neige hors-piste

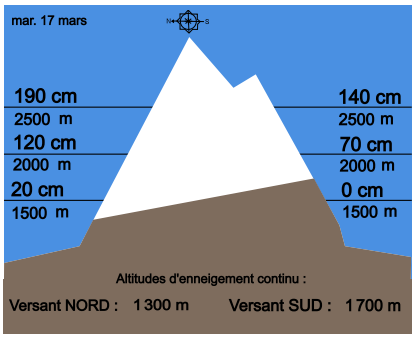

Précipitations à 1800 m

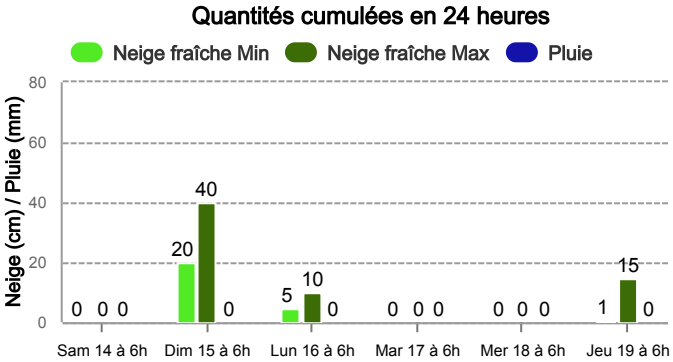

Tendance du jeudi 19 mars

3

Indice de risque marqué

Persistance de la problématique de neige ventée, avec le vent de nord à nord-est qui reste fort en altitude le matin.
Risque marqué probable.

Pour consulter la vigilance en cours, veuillez vous rendre sur le site https://vigilance.meteofrance.fr/fr

Météo-France - 73 avenue de Paris, 94165 Saint-Mandé cedex - Contact : contact@meteo.fr

Rédigé par Météo-France avec la contribution des observateurs du réseau nivo-météorologiques. Partenariat : ANMSM (Maires de Stations de Montagne), DSF (Domaines Skiables de France), ADSP (Directeurs de Pistes et de la Sécurité des Stations de Sports d'Hiver) et autres acteurs de la montagne.

Bulletin neige & avalanches par téléphone au
0 892 68 10 20 Service 0,35 € / min + prix appel

RÉPUBLIQUE FRANÇAISE
Liberté Égalité Fraternité

METEO FRANCE
À VOS CÔTÉS, DANS UN CLIMAT QUI CHANGE

Bulletin d'estimation du risque d'avalanche

(valable en dehors des pistes balisées et ouvertes)

MASSIF : Mercantour

Rédigé le mardi 17 mars 2026 à 16h

Conditions nivo-météo des 7 derniers jours

	mer. 11/03				jeu. 12/03				ven. 13/03				sam. 14/03				dim. 15/03				lun. 16/03				mar. 17/03			
	03h	09h	15h	21h	03h	09h	15h	21h	03h	09h	15h	21h	03h	09h	15h	21h	03h	09h	15h	21h	03h	09h	15h	21h	03h	09h	15h	21h
Météo																												
Vent (km/h)	25	35	45	40	40	40	40	30	25	20	30	25	60	55	40	25	60	80	50	35	45	40	35	30	20	15	20	20
à 3000m																												
Vent (km/h)	10	15	20	15	20	40	35	25	30	10	15	10	15	35	25	15	30	55	40	25	35	30	25	15	15	15	15	15
à 2000m																												

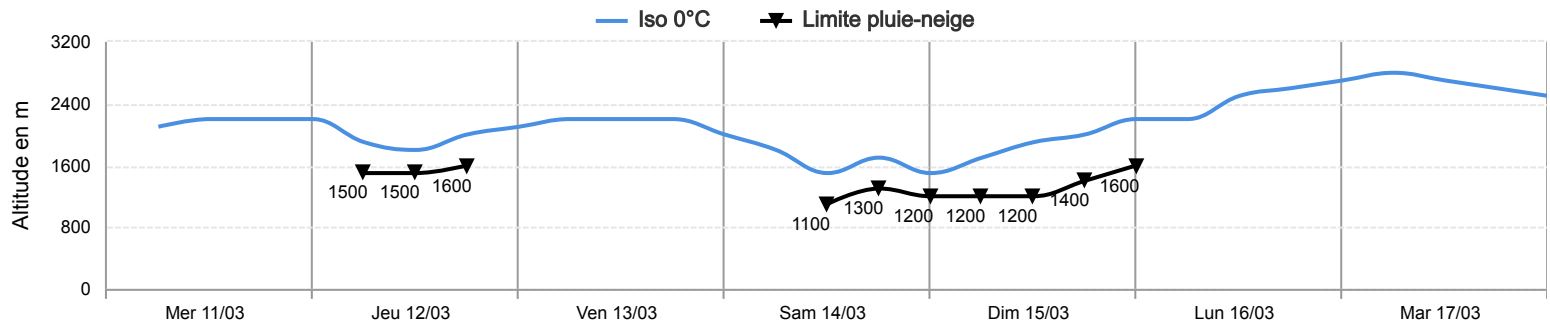

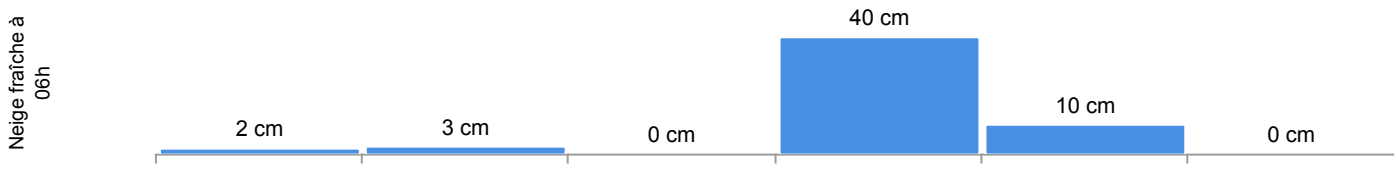

Risque d'avalanche	mer. 11/03	jeu. 12/03	ven. 13/03	sam. 14/03	dim. 15/03	lun. 16/03	mar. 17/03
	2	2	2	3	3	3	3

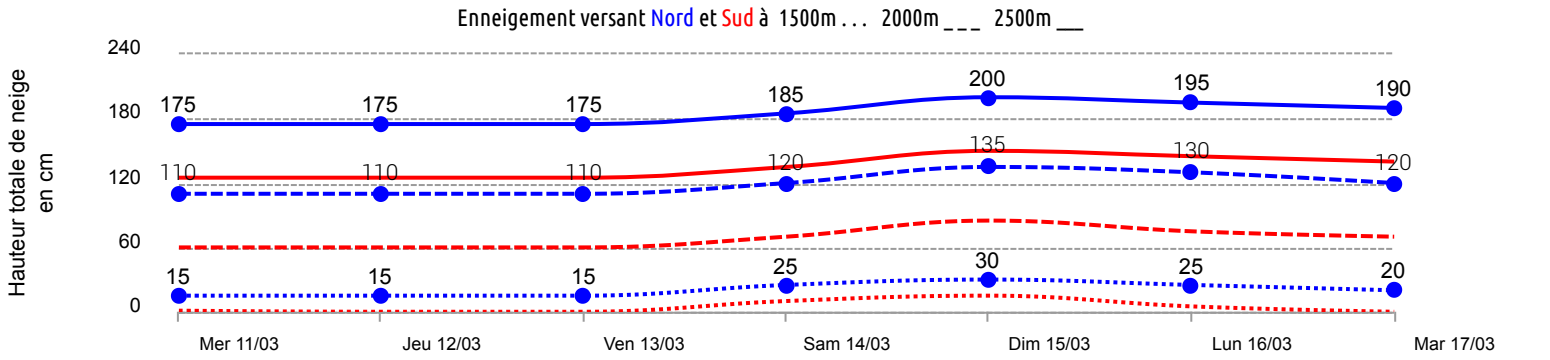

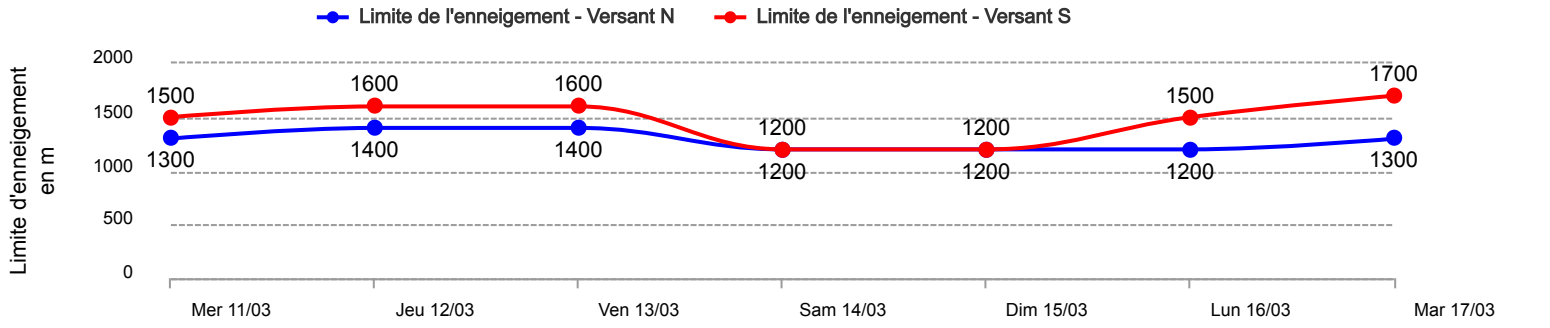

Pour consulter la vigilance en cours, veuillez vous rendre sur le site https://vigilance.meteofrance.fr/fr

Météo-France - 73 avenue de Paris, 94165 Saint-Mandé cedex - Contact : contact@meteo.fr

Bulletin neige & avalanches par téléphone au

0 892 68 10 20 Service 0,35 € / min + prix appel

Rédigé par Météo-France avec la contribution des observateurs du réseau nivo-météorologiques. Partenariat : ANMSM (Maires de Stations de Montagne), DSF (Domaines Skiables de France), ADSP (Directeurs de Pistes et de la Sécurité des Stations de Sports d'Hiver) et autres acteurs de la montagne.