Bulletin d'estimation du risque d'avalanche

(valable en dehors des pistes balisées et ouvertes)

MASSIF : Pays-Basque

Rédigé le mardi 17 mars 2026 à 16h

Estimation des risques pour le : MERCREDI 18 MARS

HUMIDIFICATION EN COURS, RARES STRUCTURES DE PLAQUES.

2

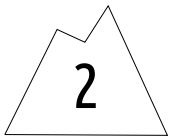

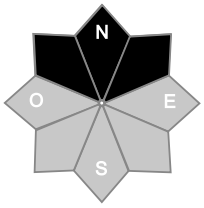

Indice de risque limité.

Départs spontanés : en neige humide au soleil.

Déclenchements provoqués : rares structures de plaques instables sur le haut du massif.

Indices de risque : 5 très fort - 4 fort - 3 marqué - 2 limité - 1 faible -- En noir : les pentes les plus dangereuses

Stabilité du manteau neigeux

Situation avalancheuse typique : neige humide neige ventée

Déclenchements provoqués :
Quelques structures de plaques peu épaisses résistent en altitude, surtout a**u-dessus de 1900/2000m dans le secteur du Pic d'Anie**, déclenchables surtout par s**ollicitation moyenne à forte**. Elles sont s**ouvent regelées en surface et sur une faible épaisseur au petit matin**, **plus sensibles après le dégel**, mais **se stabilisant peu à peu au cours de la journée** l'humidification se faisant plus en profondeur.

Observables : au-dessus de 2000m dans les secteurs nord du Pic d'Anie, signes de transport par le vent très visibles, fissures possibles sous les skis ou les raquettes, quelques affaissements dans les combes étroites.

Départs spontanés :
Regel nocturne efficace, donc **pas ou très peu d'activité au petit matin**. Pour la journée, **départs ponctuels de petite taille dans les secteurs raides** en fonction de la course du **soleil**.
Une **rare avalanche de fond de taille moyenne** reste possible se déclenchant au **niveau d'une fissure ou d'une rupture de pente** au plus fort d' l'humidification (en secteurs **Est en matinée, Sud à Sud-Ouest l'après-midi** où l'on trouve encore quelques accumulations).

Observables : "gueules de baleines" en Est, Sud et Ouest.

Autres : neige dure et regelée au petit matin, devenant très humide et très molle au soleil, pont de neige et corniches encore en place fragilisés.

Qualité de la neige

Enneigement : correct pour la saison, surtout au-dessus de 1800 m, mais reste assez maigre en versants exposés au vent d'ouest. Il débute assez bas, mais n'est skiable qu'à partir de 1600m en nord, plutôt 1800 en sud, faute de sous-couche.
État de la neige : qualité très variable au petit matin : en expositions ombragées, dans quelques secteurs raides du Pic d'Anie au-dessus de 2000m la neige est encore sèche, finement regelée entre 1900 et 2000m, regelée et dure en dessous. Zones pelées en neige très dure ou en glace près des cols et des sommets. En journée, conditions de printemps : la neige ramollit et s'alourdit au soleil, la neige restée sèche s'humidifie un peu plus en profondeur.

Aperçu météo pour le mercredi 18 mars

	nuit	matin	après-midi	soir
Pluie-Neige				
Iso 0 °C	3 300 m	3 300 m	3 300 m	3 000 m
Vent 1000 m	↑ 15 km/h	↑ 5 km/h	↑ 5 km/h	↑ 15 km/h
Vent 2000 m	↑ 25 km/h	↑ 20 km/h	↑ 25 km/h	↑ 50 km/h

Beau temps sec et doux, quelques nuages l'après-midi, renforcement du vent de Sud mercredi soir.

Épaisseur de neige hors-piste

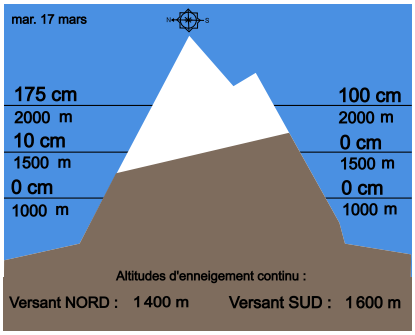

Précipitations à 1800 m

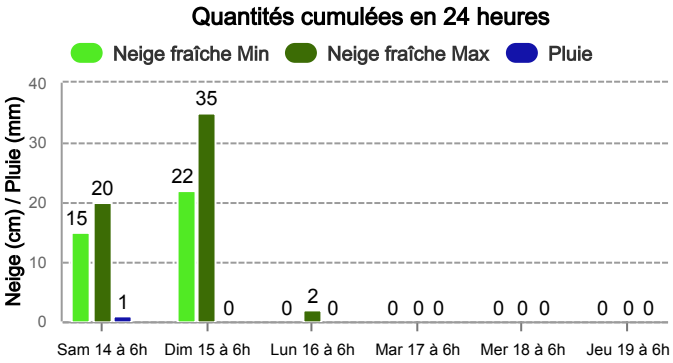

Tendance du jeudi 19 mars

1

Indice de risque faible

Risque en baisse avec la poursuite de l'humidification des rares structures de plaques encore présentes.

Pour consulter la vigilance en cours, veuillez vous rendre sur le site https://vigilance.meteofrance.fr/fr

Météo-France - 73 avenue de Paris, 94165 Saint-Mandé cedex - Contact : contact@meteo.fr

Rédigé par Météo-France avec la contribution des observateurs du réseau nivo-météorologiques. Partenariat : ANMSM (Maires de Stations de Montagne), DSF (Domaines Skiables de France), ADSP (Directeurs de Pistes et de la Sécurité des Stations de Sports d'Hiver) et autres acteurs de la montagne.

Bulletin neige & avalanches par téléphone au
0 892 68 10 20 Service 0,35 € / min + prix appel

RÉPUBLIQUE FRANÇAISE
Liberté Égalité Fraternité

METEO FRANCE
À VOS CÔTÉS, DANS UN CLIMAT QUI CHANGE

Bulletin d'estimation du risque d'avalanche
(valable en dehors des pistes balisées et ouvertes)
MASSIF : Pays-Basque

Rédigé le mardi 17 mars 2026 à 16h

Conditions nivo-météo des 7 derniers jours

	mer. 11/03				jeu. 12/03				ven. 13/03				sam. 14/03				dim. 15/03				lun. 16/03				mar. 17/03			
	03h	09h	15h	21h	03h	09h	15h	21h	03h	09h	15h	21h	03h	09h	15h	21h	03h	09h	15h	21h	03h	09h	15h	21h	03h	09h	15h	21h
Météo																												
Vent (km/h)	50	45	60	50	30	35	20	20	30	60	55	55	65	60	55	70	70	75	65	50	50	35	30	20	15	15	15	25
à 2000m																												
Vent (km/h)	15	10	20	15	10	15	5	5	15	20	20	15	25	20	20	35	40	50	35	20	20	20	15	5	10	5	10	15
à 1000m																												

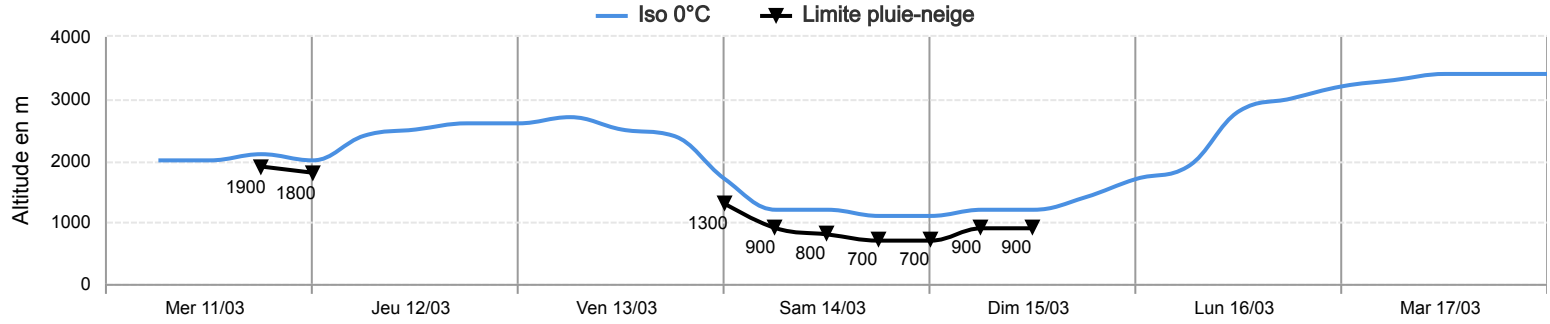

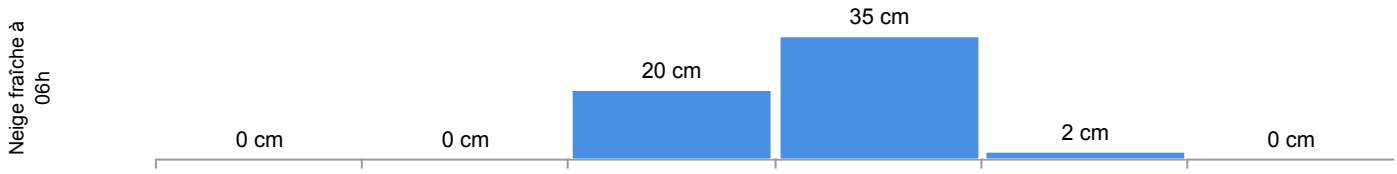

Risque d'avalanche	mer. 11/03	jeu. 12/03	ven. 13/03	sam. 14/03	dim. 15/03	lun. 16/03	mar. 17/03
	2	2	1	3	3	3	2

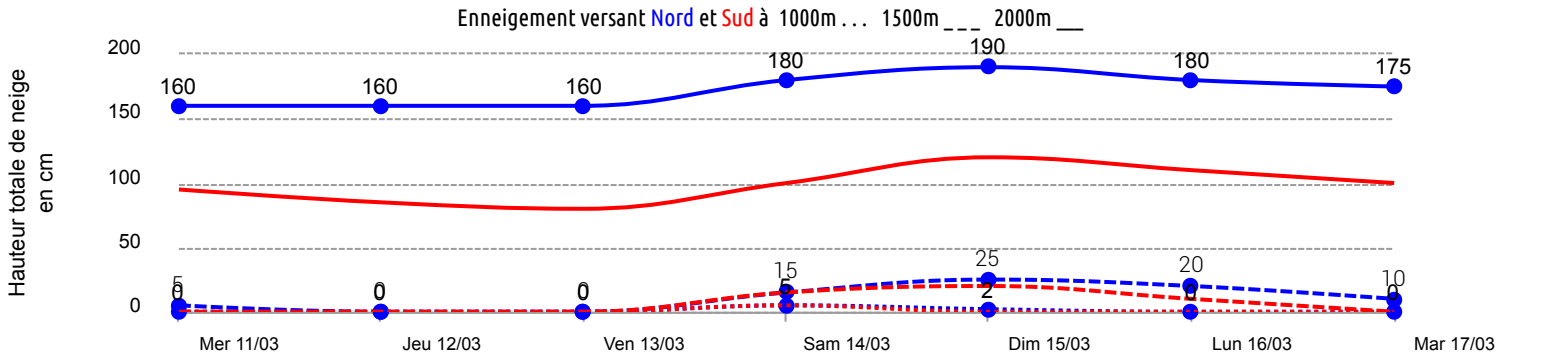

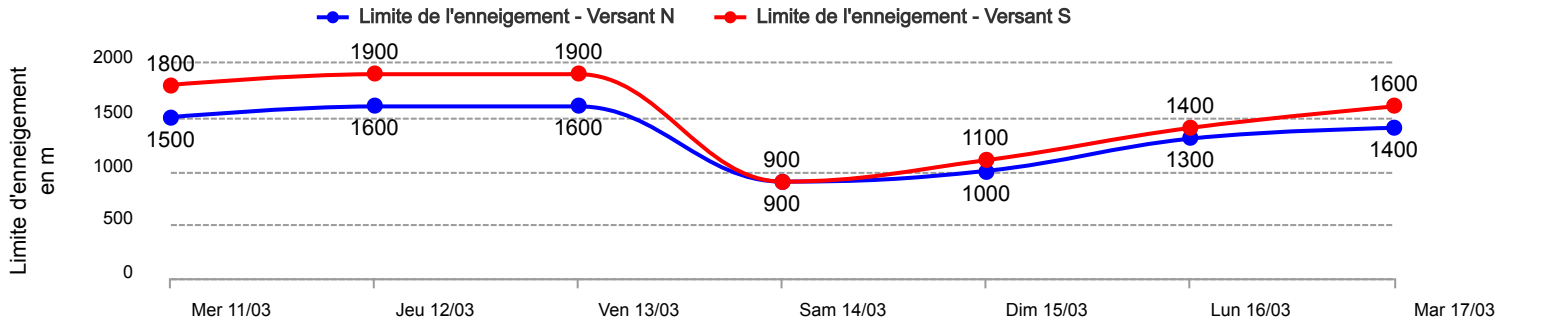

Pour consulter la vigilance en cours, veuillez vous rendre sur le site https://vigilance.meteofrance.fr/fr

Météo-France - 73 avenue de Paris, 94165 Saint-Mandé cedex - Contact : contact@meteo.fr

Bulletin neige & avalanches par téléphone au
0 892 68 10 20 Service 0,35 € / min + prix appel

Rédigé par Météo-France avec la contribution des observateurs du réseau nivo-météorologiques. Partenariat : ANMSM (Maires de Stations de Montagne), DSF (Domaines Skiables de France), ADSP (Directeurs de Pistes et de la Sécurité des Stations de Sports d'Hiver) et autres acteurs de la montagne.