Bulletin d'estimation du risque d'avalanche
(valable en dehors des pistes balisées et ouvertes)

MASSIF : Queyras

Rédigé le mardi 17 mars 2026 à 16h

Estimation des risques pour le : MERCREDI 18 MARS

INSTABILITÉ ENCORE MARQUÉE DANS NEIGE RÉCENTE SÈCHE VENTÉE, PLUS ÉPAISSES DANS LE HAUT GUIL

3

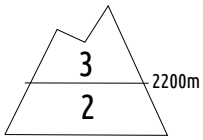

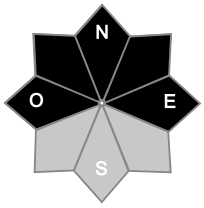

Au-dessus de 2200m indice de risque marqué, plus bas indice limité.

Départs spontanés : rare avalanche de plaque

Déclenchements provoqués : avalanches de plaque, faciles à déclencher

Indices de risque : 5 très fort - 4 fort - 3 marqué - 2 limité - 1 faible -- En noir : les pentes les plus dangereuses

Stabilité du manteau neigeux

Situation avalancheuse typique : neige ventée couche fragile persistante

Déclenchements provoqués : plaques à vent récentes, quelques autres en formation (transport par le vent de la neige restée sèche / mobilisable). Instabilités surtout présentes au-dessus de 2200/2400 m dans les orientations ouest / nord / est ou au-dessus de 2700 m environ dans les adrets. Ces instabilités restent facilement déclenchables par un skieur. Avalanche mobilisant la neige récente de taille petite à moyenne. Dans le Haut Guil, vers Abries-Ristolas, taille moyenne, voire grande. Par ailleurs, on ne peut pas exclure dans ces mêmes orientations, le déclenchement en cascade d'une instabilité plus enfouie (couche fragile persistante), possiblement de grande taille, large cassure, emportant la quasi-totalité du manteau en place.
- À plus basses altitudes ou en adrets d'altitude, les instabilités se stabilisent. Un déclenchement semble plus difficile.

Départs spontanés : peu probables ou rares départs sous forme de plaque par la surcharge liée au transport de la neige par le vent. Plutôt haute altitude, taille petite à moyenne, rarement grande.

Qualité de la neige

L'enneigement est proche des normales pour une mi-mars, et il s'est bien amélioré dans le Haut Guil suite au petit retour d'est.
Hauteurs de neige observées : 166 cm en versant nord du col Izoard à 2300 m, 101 cm à la Nivôse du Col Agnel à 2630 m, 79 cm à Ristolas à 1670 m.

Limite d'enneigement skiable : vers 1600/1800 m selon les secteurs et orientations.

État de la neige de surface : après un bon regel, neige croutée en adrets. Peu ou pas d'humidification en journée. En ubacs au-dessus de 2000/2400 m, neige récente souvent densifiée / travaillée par le vent. À très haute altitude, toute orientation, neige sèche travaillée par le vent. Quelques giboulées en journée donnant localement quelques cm de neige.

Aperçu météo pour le mercredi 18 mars

nuit	matin	après-midi	soir

Passagèrement très nuageux entre la matinée/début d'après-midi accompagné de faibles giboulées.
Vent d'est devenant sensible.

Pluie-Neige			1 000 m	1 000 m
Iso 0 °C	2 400 m	1 500 m	1 300 m	1 300 m
Vent 2000 m	10 km/h	30 km/h	40 km/h	30 km/h
Vent 3000 m	20 km/h	40 km/h	50 km/h	40 km/h

Épaisseur de neige hors-piste

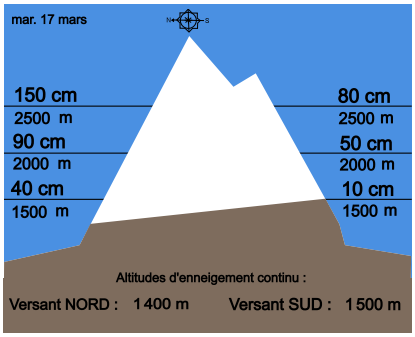

Précipitations à 1800 m

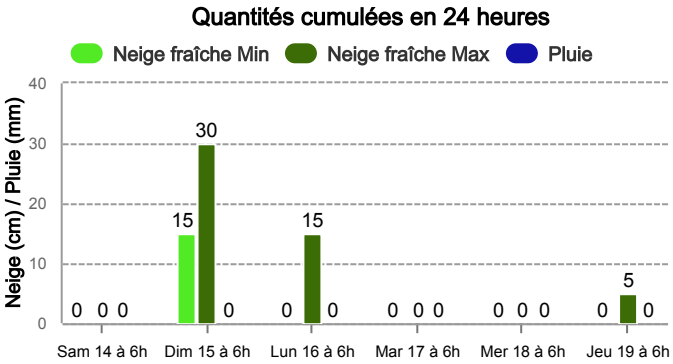

Tendance du jeudi 19 mars

3 **Indice de risque marqué**

Risque stable ou en baisse. Plaques encore localement réactives, notamment sur le Haut Guil.

Pour consulter la vigilance en cours, veuillez vous rendre sur le site https://vigilance.meteofrance.fr/fr

Météo-France - 73 avenue de Paris, 94165 Saint-Mandé cedex - Contact : contact@meteo.fr

Rédigé par Météo-France avec la contribution des observateurs du réseau nivo-météorologiques. Partenariat : ANMSM (Maires de Stations de Montagne), DSF (Domaines Skiables de France), ADSP (Directeurs de Pistes et de la Sécurité des Stations de Sports d'Hiver) et autres acteurs de la montagne.

Bulletin neige & avalanches par téléphone au 0 892 68 10 20 Service 0,35 € / min + prix appel

RÉPUBLIQUE FRANÇAISE
Liberté Égalité Fraternité

METEO FRANCE
À VOS CÔTÉS, DANS UN CLIMAT QUI CHANGE

Bulletin d'estimation du risque d'avalanche

(valable en dehors des pistes balisées et ouvertes)

MASSIF : Queyras

Rédigé le mardi 17 mars 2026 à 16h

Conditions nivo-météo des 7 derniers jours

	mer. 11/03				jeu. 12/03				ven. 13/03				sam. 14/03				dim. 15/03				lun. 16/03				mar. 17/03			
	03h	09h	15h	21h	03h	09h	15h	21h	03h	09h	15h	21h	03h	09h	15h	21h	03h	09h	15h	21h	03h	09h	15h	21h	03h	09h	15h	21h
Météo																												
Vent (km/h)	20	25	40	40	35	20	20	15	15	15	20	25	45	25	5	15	40	50	30	10	20	30	30	25	25	15	20	15
à 3000m																												
Vent (km/h)	10	15	25	15	15	15	15	10	10	10	15	15	15	10	0	5	15	30	25	10	10	20	30	15	10	10	15	10
à 2000m																												

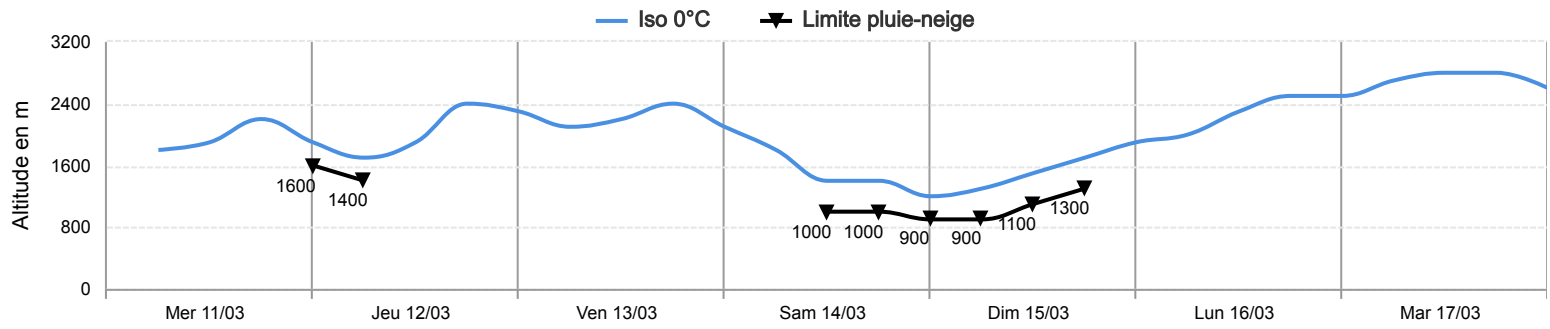

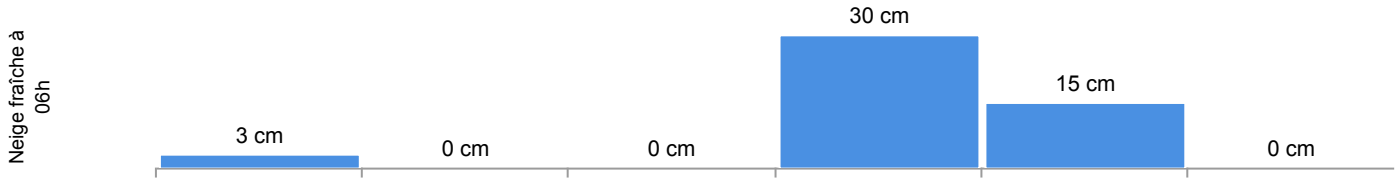

Risque d'avalanche	mer. 11/03	jeu. 12/03	ven. 13/03	sam. 14/03	dim. 15/03	lun. 16/03	mar. 17/03
	2	2	2	3	3	3	3

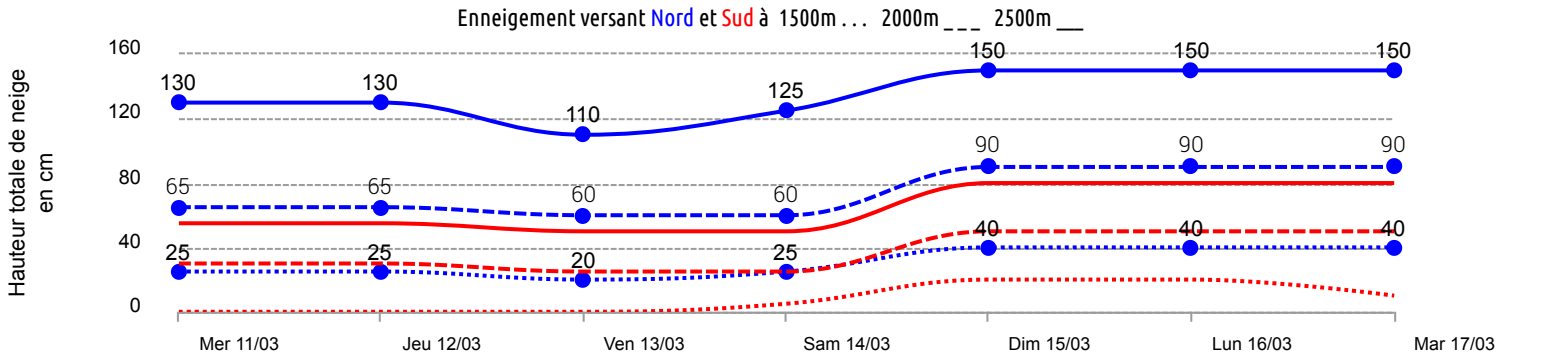

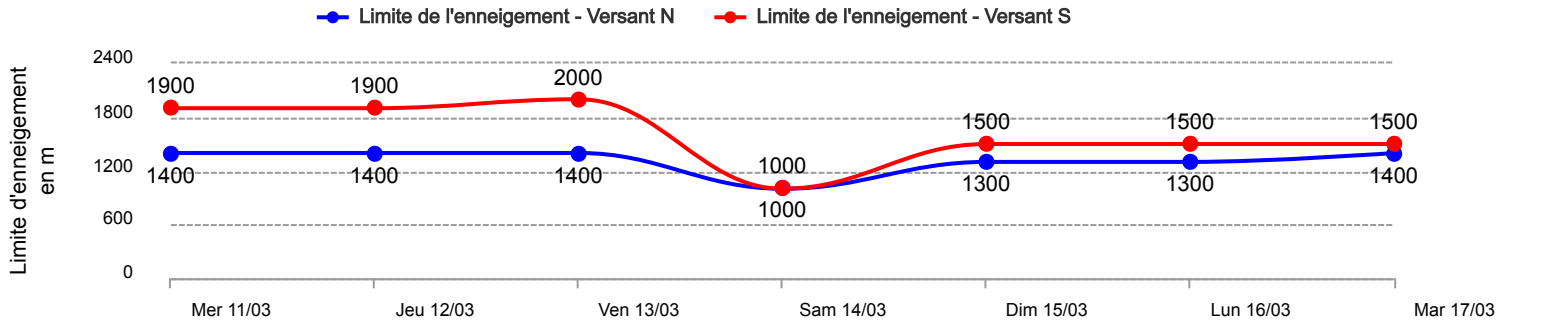

Pour consulter la vigilance en cours, veuillez vous rendre sur le site https://vigilance.meteofrance.fr/fr

Météo-France - 73 avenue de Paris, 94165 Saint-Mandé cedex - Contact : contact@meteo.fr

Bulletin neige & avalanches par téléphone au

0 892 68 10 20 Service 0,35 € / min + prix appel

Rédigé par Météo-France avec la contribution des observateurs du réseau nivo-météorologiques. Partenariat : ANMSM (Maires de Stations de Montagne), DSF (Domaines Skiables de France), ADSP (Directeurs de Pistes et de la Sécurité des Stations de Sports d'Hiver) et autres acteurs de la montagne.