Bulletin d'estimation du risque d'avalanche

(valable en dehors des pistes balisées et ouvertes)

MASSIF : Renoso Incudine

Rédigé le mardi 17 mars 2026 à 16h

Estimation des risques pour le : MERCREDI 18 MARS

INSTABILITÉS EN ALTITUDE DANS LA NEIGE FRAICHE VENTÉE.

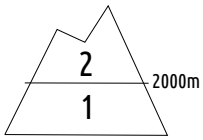

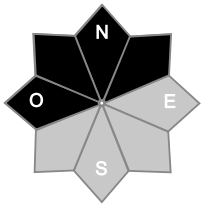

Au-dessus de 2000m indice de risque limité, plus bas indice faible.

Départs spontanés : Rares départs superficiels en neige fraîches dans les pentes raides

Déclenchements provoqués : Nombreuses plaques à vent difficilement sollicitables en altitude au-dessus de 2000 m.

Indices de risque : 5 très fort - 4 fort - 3 marqué - 2 limité - 1 faible -- En noir : les pentes les plus dangereuses

Stabilité du manteau neigeux

Situation avalancheuse typique : neige ventée

Déclenchements provoqués : Vent de Nord-est accompagnant les nouvelles chutes de neige, formant ainsi de nouvelles structures de plaques au-dessus de 2000 m environ, où la neige récente est restée plus légère. Elles s'ajoutent aux plaques formées par les précédentes chutes de neige et reposent parfois sur des couches fragiles composées de neige roulée. Ces plaques peuvent exister en tous versants ; elles sont par endroits dures à cause du vent fort, parfois friables plus à l'abri du vent. Elles engendrent des avalanches de taille moyenne (taille 1 à 2). Toutefois, en pentes ombragées où la neige est restée froide, une plaque peut encore être sensible au simple passage d'un randonneur ou skieur.

En dessous de 2000 m, la neige fraîche repose sur une sous-couche regelée et stable.

Départs spontanés : peu probable, ou rares coulées de surface avec la neige rapportée par le vent fort, dans les couloirs et pentes raides.

Autres : Nombreuses des surfaces dures et glacées.

Qualité de la neige

Qualification de l'enneigement : L'enneigement est excellent pour la saison au-dessus de 1600 m. Au Val d'Ese, on relève 2m00 de neige à 1800 m. À Ghisoni Capanelle, on mesure environ 3m00 dans les combes abritées.

Limite d'enneigement skiable : 1500 m.

État de la neige : La neige fraîche de ces derniers jours (20-30 cm à 2000 m) s'humidifie en surface dans les pentes SE à SW bien exposées au soleil actuel, surtout en-dessous de 2000/2200 m. Plus haut, et en pentes plus froides NE à NW, elle reste plus froide, légère et profonde, ou bien densifiée ou durcie par le Grécale qui a soufflé fort surtout en haute montagne. Le net refroidissement va permettre une consolidation par regel des couches de neige humide. Des croûtes épaisses vont se former et des surfaces dures et glacées se généraliser. Mercredi matin un peu de neige fraîche va se déposer.

À noter également la présence de corniches parfois volumineuses.

Aperçu météo pour le mercredi 18 mars

	nuit	matin	après-midi	soir
Pluie-Neige		800 m		
Iso 0 °C	1 400 m	1 000 m	1 300 m	1 300 m
Vent 1500 m	10 km/h	25 km/h	35 km/h	40 km/h
Vent 2000 m	20 km/h	40 km/h	45 km/h	70 km/h

Épaisseur de neige hors-piste

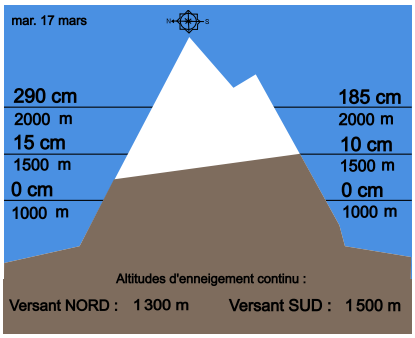

Précipitations à 1800 m

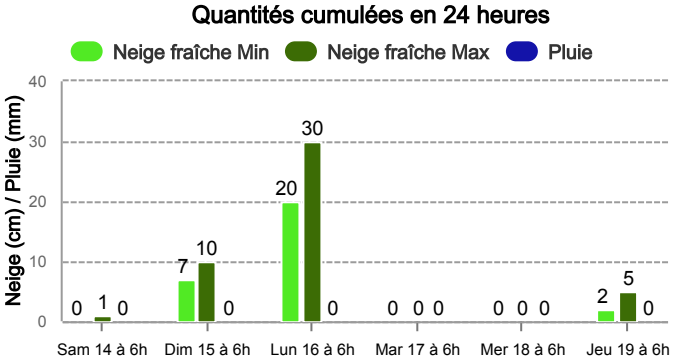

Tendance du jeudi 19 mars

Indice de risque limité

Plaques encore localement sensibles en versants ombragés.

Pour consulter la vigilance en cours, veuillez vous rendre sur le site https://vigilance.meteofrance.fr/fr

Météo-France - 73 avenue de Paris, 94165 Saint-Mandé cedex - Contact : contact@meteo.fr

Rédigé par Météo-France avec la contribution des observateurs du réseau nivo-météorologiques. Partenariat : ANMSM (Maires de Stations de Montagne), DSF (Domaines Skiables de France), ADSP (Directeurs de Pistes et de la Sécurité des Stations de Sports d'Hiver) et autres acteurs de la montagne.

Bulletin neige & avalanches par téléphone au 0 892 68 10 20 Service 0,35 € / min + prix appel

RÉPUBLIQUE FRANÇAISE
Liberté Égalité Fraternité

METEO FRANCE
À VOS CÔTÉS, DANS UN CLIMAT QUI CHANGE

Bulletin d'estimation du risque d'avalanche

(valable en dehors des pistes balisées et ouvertes)

MASSIF : Renoso Incudine

Rédigé le mardi 17 mars 2026 à 16h

Conditions nivo-météo des 7 derniers jours

	mer. 11/03				jeu. 12/03				ven. 13/03				sam. 14/03				dim. 15/03				lun. 16/03				mar. 17/03			
	03h	09h	15h	21h	03h	09h	15h	21h	03h	09h	15h	21h	03h	09h	15h	21h	03h	09h	15h	21h	03h	09h	15h	21h	03h	09h	15h	21h
Météo																												
Vent (km/h)	20	30	40	40	30	30	30	30	25	15	5	5	10	30	50	35	25	40	70	60	60	45	15	35	30	45	15	10
à 2000m																												
Vent (km/h)	15	20	30	20	30	20	25	15	20	20	15	10	10	20	50	45	45	40	65	45	50	40	10	15	10	15	10	5
à 1500m																												

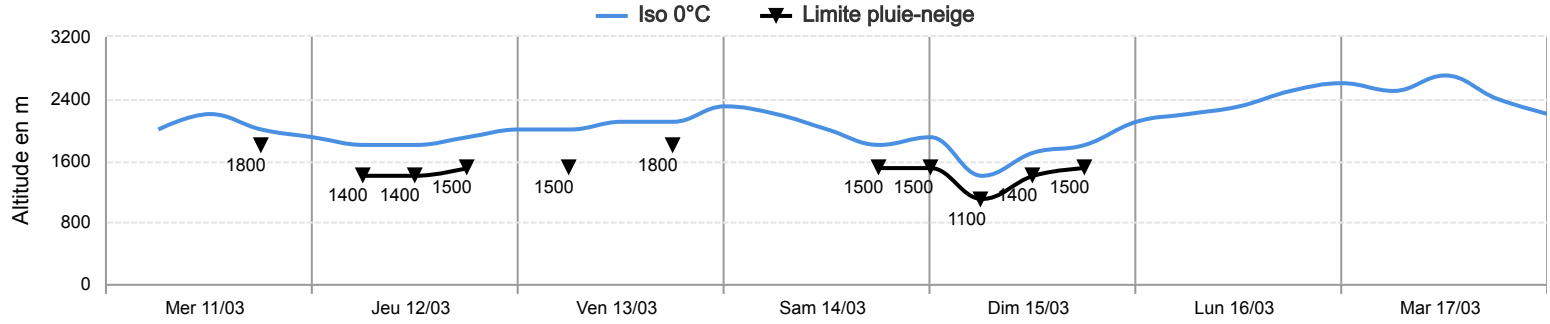

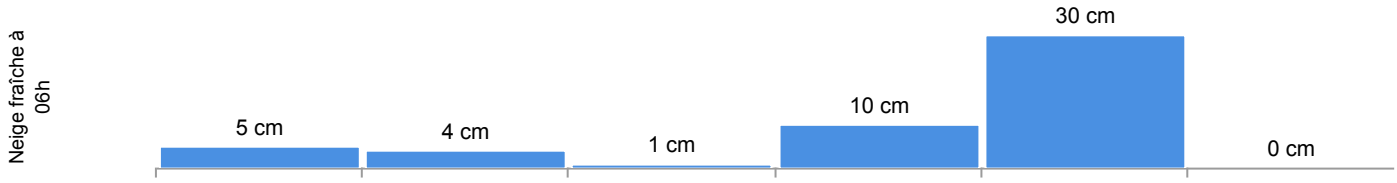

Risque d'avalanche	mer. 11/03	jeu. 12/03	ven. 13/03	sam. 14/03	dim. 15/03	lun. 16/03	mar. 17/03
	1	1	1	2	2	3	2

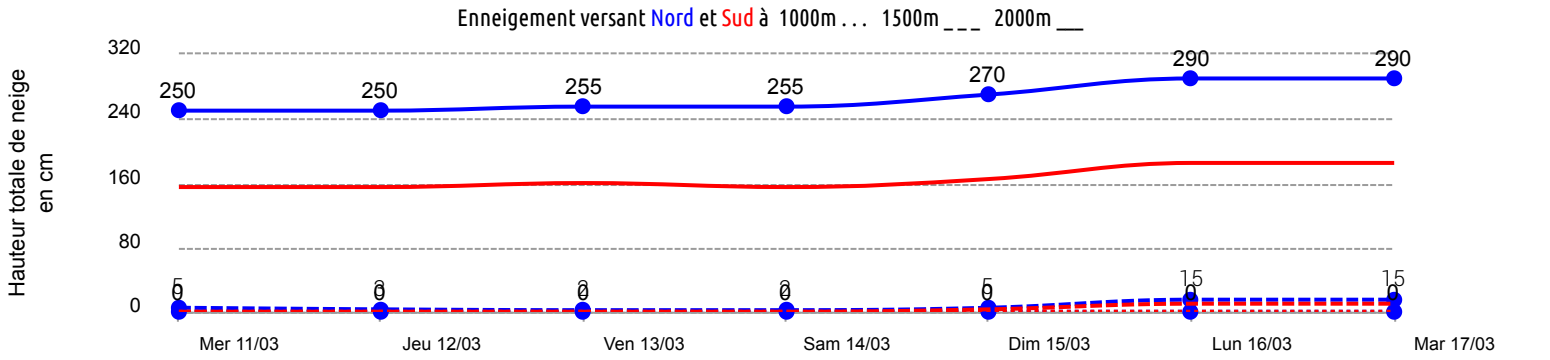

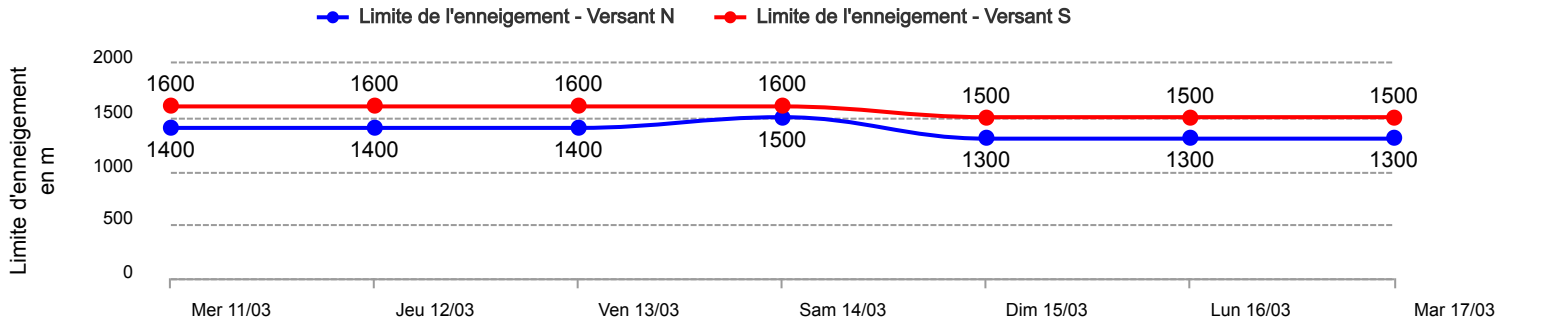

Pour consulter la vigilance en cours, veuillez vous rendre sur le site https://vigilance.meteofrance.fr/fr

Météo-France - 73 avenue de Paris, 94165 Saint-Mandé cedex - Contact : contact@meteo.fr

Rédigé par Météo-France avec la contribution des observateurs du réseau nivo-météorologiques. Partenariat : ANMSM (Maires de Stations de Montagne), DSF (Domaines Skiables de France), ADSP (Directeurs de Pistes et de la Sécurité des Stations de Sports d'Hiver) et autres acteurs de la montagne.

Bulletin neige & avalanches par téléphone au

0 892 68 10 20 Service 0,35 € / min + prix appel