# Bulletin d'estimation du risque d'avalanche

(valable en dehors des pistes balisées et ouvertes)

# MASSIF : Thabor

Rédigé le mardi 17 mars 2026 à 16h

## Estimation des risques pour le : MERCREDI 18 MARS

**INSTABILITÉ ENCORE MARQUÉE DANS NEIGE RÉCENTE SÈCHE VENTÉE**

3

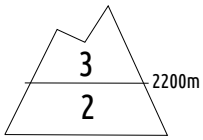


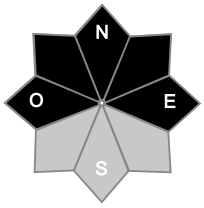


Au-dessus de 2200m indice de risque marqué, plus bas indice limité.

**Départs spontanés :** rare avalanche de plaque

**Déclenchements provoqués :** avalanches de plaque, faciles à déclencher

Indices de risque : 5 très fort - 4 fort - 3 marqué - 2 limité - 1 faible -- En noir : les pentes les plus dangereuses

## Stabilité du manteau neigeux

**Situation avalancheuse typique :** neige ventée couche fragile persistante

**Déclenchements provoqués** : plaques à vent récentes, quelques autres en formation (transport par le vent de la neige restée sèche / mobilisable). Instabilités surtout présentes au-dessus de 2200/2400 m dans les orientations ouest / nord / est ou vers les plus hauts sommets dans les adrets. Ces instabilités restent facilement déclenchables par un skieur. Avalanches de taille petite à moyenne, mobilisant la neige récente. Par ailleurs, on ne peut pas exclure dans ces mêmes orientations, le déclenchement en cascade d'une instabilité plus enfouie (couche fragile persistante), possiblement de grande taille, large cassure, emportant la quasi-totalité du manteau en place.
- À plus basses altitudes ou en adrets d'altitude, les instabilités se stabilisent. Un déclenchement semble plus difficile.

**Départs spontanés** : peu probables ou rares départs sous forme de plaque par la surcharge liée au transport de la neige par le vent. Plutôt haute altitude, taille petite à moyenne.

## Qualité de la neige

**L'enneigement** est proche des normales pour une mi-mars.
Hauteurs de neige observées vers 2500 m : 174 cm dans le vallon du Chardonnet, 127 cm à la nivôse des Rochilles, 83 cm à la Nivôse du Galibier.

**Limite d'enneigement skiable** : vers 1400/1500 m en ubacs, 1700/1900 m en adrets pas trop raides.

**État de la neige de surface** : après un bon regel, neige croutée en adrets. Peu ou pas d'humidification en journée. En ubacs au-dessus de 2000/2400 m, neige récente souvent densifiée / travaillée par le vent. Quelques giboulées en journée donnant localement quelques cm de neige.

## Aperçu météo pour le mercredi 18 mars

| nuit | matin | après-midi | soir |
|---|---|---|---|
| | | | |

Passagèrement très nuageux entre la matinée / milieu d'après-midi accompagné de faibles giboulées.
Vent d'est devenant sensible.

| Pluie-Neige | | | 1 000 m | |
|---|---|---|---|---|
| Iso 0 °C | 2 200 m | 1 500 m | 1 300 m | 1 300 m |
| Vent 2000 m | ↘ 20 km/h | ↙ 30 km/h | ↖ 40 km/h | ↖ 20 km/h |
| Vent 3000 m | ↘ 40 km/h | ↖ 50 km/h | ↖ 50 km/h | ↖ 45 km/h |

## Épaisseur de neige hors-piste

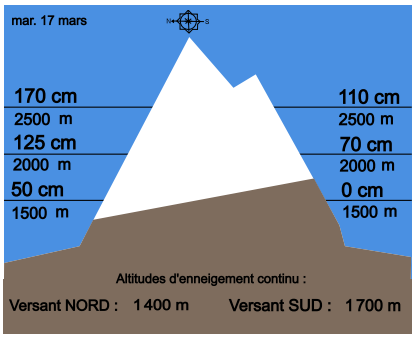


## Précipitations à 1800 m

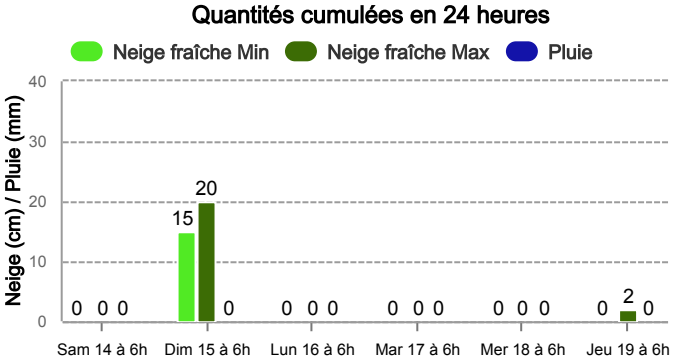


## Tendance du jeudi 19 mars

3

**Indice de risque marqué**

Risque stable ou en baisse. Plaques encore localement réactives.

Pour consulter la vigilance en cours, veuillez vous rendre sur le site https://vigilance.meteofrance.fr/fr

Météo-France - 73 avenue de Paris, 94165 Saint-Mandé cedex - Contact : contact@meteo.fr

Rédigé par Météo-France avec la contribution des observateurs du réseau nivo-météorologiques. Partenariat : ANMSM (Maires de Stations de Montagne), DSF (Domaines Skiables de France), ADSP (Directeurs de Pistes et de la Sécurité des Stations de Sports d'Hiver) et autres acteurs de la montagne.

Bulletin neige & avalanches par téléphone au **0 892 68 10 20** Service 0,35 € / min + prix appel

RÉPUBLIQUE FRANÇAISE
*Liberté Égalité Fraternité*

METEO FRANCE
À VOS CÔTÉS, DANS UN CLIMAT QUI CHANGE

# Bulletin d'estimation du risque d'avalanche

## (valable en dehors des pistes balisées et ouvertes)

# MASSIF : Thabor

Rédigé le mardi 17 mars 2026 à 16h

## Conditions nivo-météo des 7 derniers jours

| | mer. 11/03 | | | | jeu. 12/03 | | | | ven. 13/03 | | | | sam. 14/03 | | | | dim. 15/03 | | | | lun. 16/03 | | | | mar. 17/03 | | | |
|---|---|---|---|---|---|---|---|---|---|---|---|---|---|---|---|---|---|---|---|---|---|---|---|---|---|---|---|---|
| | 03h | 09h | 15h | 21h | 03h | 09h | 15h | 21h | 03h | 09h | 15h | 21h | 03h | 09h | 15h | 21h | 03h | 09h | 15h | 21h | 03h | 09h | 15h | 21h | 03h | 09h | 15h | 21h |
| Météo | | | | | | | | | | | | | | | | | | | | | | | | | | | | |
| Vent (km/h) | 15 | 20 | 35 | 40 | 40 | 30 | 20 | 10 | 10 | 10 | 15 | 20 | 50 | 30 | 5 | 15 | 20 | 45 | 40 | 10 | 30 | 40 | 50 | 40 | 35 | 20 | 25 | 25 |
| à 3000m | | | | | | | | | | | | | | | | | | | | | | | | | | | | |
| Vent (km/h) | 10 | 10 | 20 | 15 | 20 | 20 | 15 | 10 | 10 | 10 | 15 | 10 | 5 | 5 | 10 | 20 | 10 | 20 | 15 | 5 | 10 | 30 | 40 | 25 | 20 | 15 | 20 | 15 |
| à 2000m | | | | | | | | | | | | | | | | | | | | | | | | | | | | |

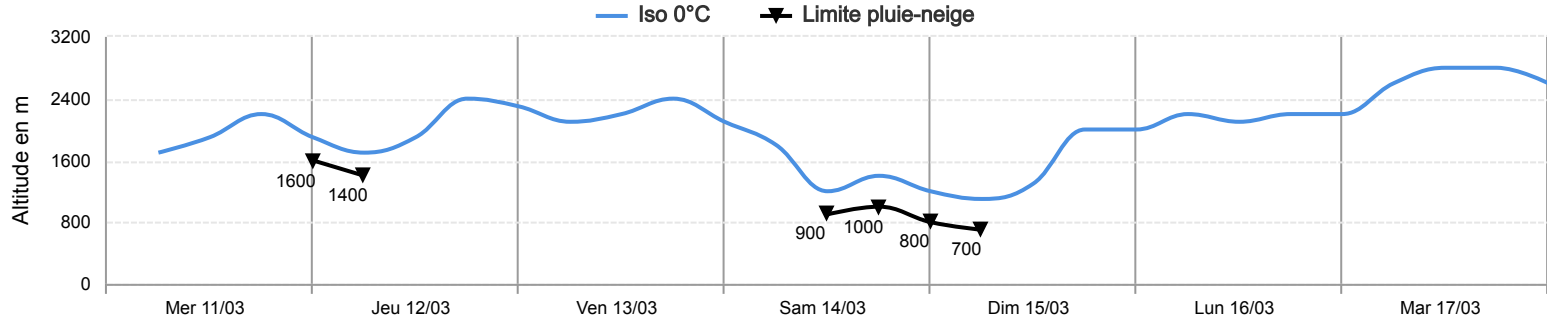


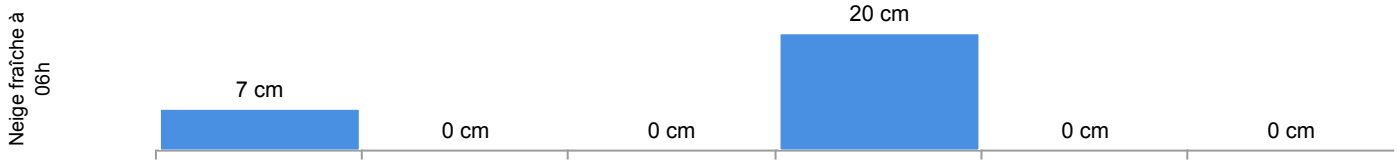


| Risque d'avalanche | mer. 11/03 | jeu. 12/03 | ven. 13/03 | sam. 14/03 | dim. 15/03 | lun. 16/03 | mar. 17/03 |
|---|---|---|---|---|---|---|---|
| | 2 | 2 | 2 | 3 | 3 | 3 | 3 |

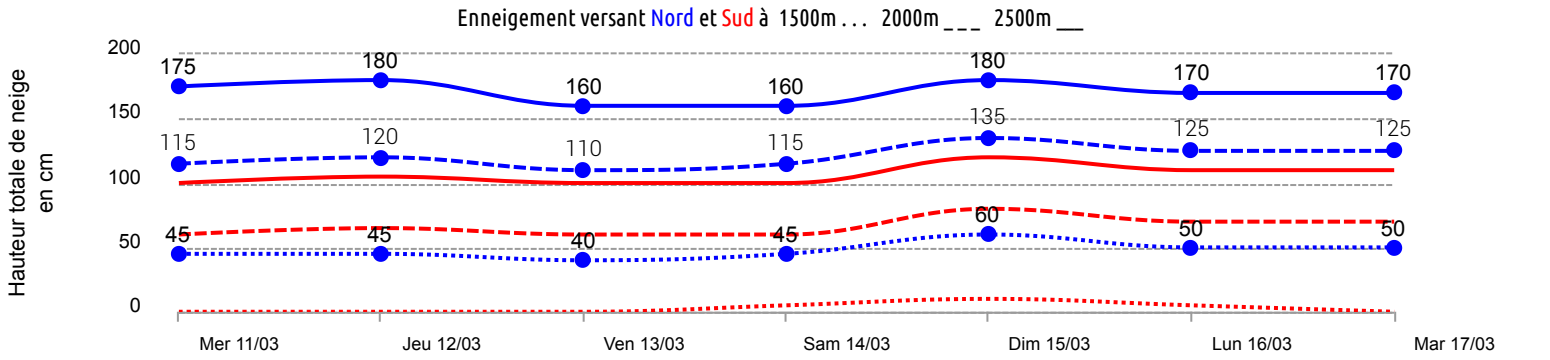


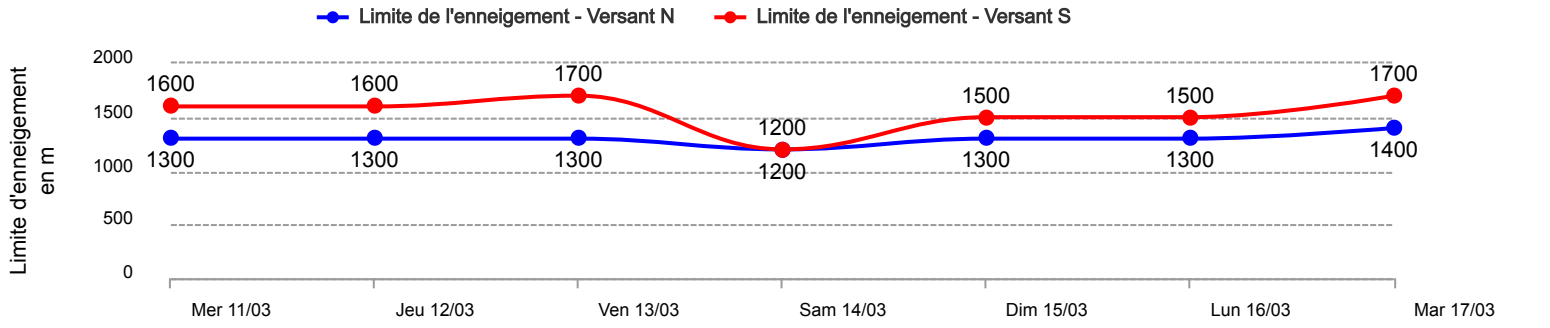


Pour consulter la vigilance en cours, veuillez vous rendre sur le site https://vigilance.meteofrance.fr/fr


**Météo-France - 73 avenue de Paris, 94165 Saint-Mandé cedex - Contact : contact@meteo.fr**


Rédigé par Météo-France avec la contribution des observateurs du réseau nivo-météorologiques. Partenariat : ANMSM (Maires de Stations de Montagne), DSF (Domaines Skiables de France), ADSP (Directeurs de Pistes et de la Sécurité des Stations de Sports d'Hiver) et autres acteurs de la montagne.

**Bulletin neige & avalanches par téléphone au**

**0 892 68 10 20** Service 0,35 € / min + prix appel