# Bulletin d'estimation du risque d'avalanche

(valable en dehors des pistes balisées et ouvertes)

# MASSIF : Ubaye

Rédigé le mardi 17 mars 2026 à 16h

## Estimation des risques pour le : MERCREDI 18 MARS

**DES INSTABILITÉS DANS LA NEIGE VENTÉE**

3

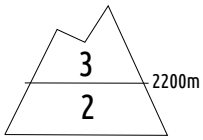


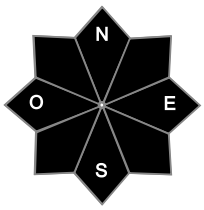


Au-dessus de 2200m indice de risque marqué, plus bas indice limité.

**Départs spontanés :** quelques départs de plaques suite au transport de neige par le vent.

**Déclenchements provoqués :** plaques faciles à déclencher dans la neige transportée par le vent.

Indices de risque : 5 très fort - 4 fort - 3 marqué - 2 limité - 1 faible -- En noir : les pentes les plus dangereuses

## Stabilité du manteau neigeux

**Situation avalancheuse typique :** neige ventée

**Déclenchements provoqués :** de nouvelles plaques se forment progressivement en journée de mercredi, même loin des crêtes, avec le renforcement du vent d'est attendu. Au-dessus de 2200 m, ces plaques sont faciles à déclencher et assez fréquentes en contrebas des crêtes, derrière les ruptures de pente ou les bosses. Ces instabilités se trouvent plus fréquemment dans les ubacs où le manteau neigeux n'est pas printanier, mais des plaques se forment aussi derrière les crêtes en adrets, avec la neige rapportée depuis les versants ombragés. Avalanches souvent moyennes (taille 2), une rare grande (taille 3) non exclue en cas de sollicitation de la couche fragile persistante enfouie (suite au départ d'une première plaque de surface par exemple).
Sous 2200 m, la probabilité de déclencher une plaque est plus limitée.

**Départs spontanés :** quelques plaques cèdent spontanément suite au transport de neige par le vent. Avalanches souvent moyennes (taille 2), rarement grandes (taille 3).

## Qualité de la neige

**Enneigement** proche des normales.
Hauteurs de neige observées : 80 cm à la Nivôse de Restefond à 2550 m (secteur venté), 90 cm au-dessus de Larche à 2270 m en adret.

**Enneigement skiable** : vers 1500 m en ubacs, 1800/1900 m en adrets peu pentus.

**État de la neige en surface** : dans les adrets, neige souvent croûtée, parfois recouverte par un peu de neige fraîche ou par des accumulations de neige rapportée par le vent. Dans les ubacs, la neige reste froide au-dessus de 2000/2100 m environ, encore assez légère à l'abri du vent, mais de plus en plus travaillée ou durcie par le vent dans les secteurs exposés.

## Aperçu météo pour le mercredi 18 mars

| | nuit | matin | après-midi | soir |
|---|---|---|---|---|
| | | | | |
| Un peu de neige le matin et jusqu'en début d'après-midi (1 à 5 cm), soufflée par le vent d'est qui devient fort en seconde partie de journée. Net refroidissement. | | | | |
| **Pluie-Neige** | | 1 200 m | | |
| **Iso 0 °C** | 2 200 m | 1 600 m | 1 500 m | 1 600 m |
| **Vent 2000 m** | 10 km/h | 30 km/h | 50 km/h | 50 km/h |
| **Vent 3000 m** | 25 km/h | 50 km/h | 70 km/h | 80 km/h |

## Épaisseur de neige hors-piste

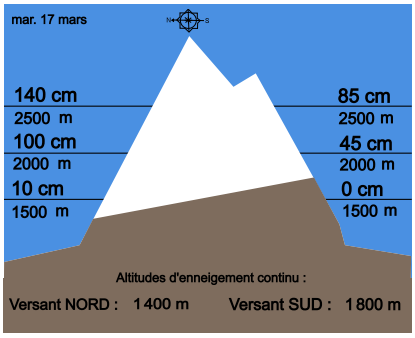


## Précipitations à 1800 m

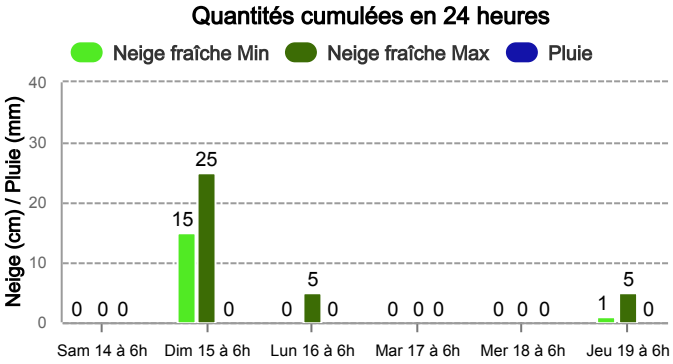


## Tendance du jeudi 19 mars

3

**Indice de risque marqué**

Persistance de la problématique de neige ventée, avec le vent d'est qui reste encore assez fort en altitude le matin.
Risque marqué probable.

Pour consulter la vigilance en cours, veuillez vous rendre sur le site https://vigilance.meteofrance.fr/fr

Météo-France - 73 avenue de Paris, 94165 Saint-Mandé cedex - Contact : contact@meteo.fr

Rédigé par Météo-France avec la contribution des observateurs du réseau nivo-météorologiques. Partenariat : ANMSM (Maires de Stations de Montagne), DSF (Domaines Skiables de France), ADSP (Directeurs de Pistes et de la Sécurité des Stations de Sports d'Hiver) et autres acteurs de la montagne.

Bulletin neige & avalanches par téléphone au
0 892 68 10 20 Service 0,35 € / min + prix appel

RÉPUBLIQUE FRANÇAISE
*Liberté Égalité Fraternité*

METEO FRANCE
À VOS CÔTÉS, DANS UN CLIMAT QUI CHANGE

# Bulletin d'estimation du risque d'avalanche

## (valable en dehors des pistes balisées et ouvertes)

# MASSIF : Ubaye

Rédigé le mardi 17 mars 2026 à 16h

## Conditions nivo-météo des 7 derniers jours

| | mer. 11/03 | | | | jeu. 12/03 | | | | ven. 13/03 | | | | sam. 14/03 | | | | dim. 15/03 | | | | lun. 16/03 | | | | mar. 17/03 | | | |
|---|---|---|---|---|---|---|---|---|---|---|---|---|---|---|---|---|---|---|---|---|---|---|---|---|---|---|---|---|
| | 03h | 09h | 15h | 21h | 03h | 09h | 15h | 21h | 03h | 09h | 15h | 21h | 03h | 09h | 15h | 21h | 03h | 09h | 15h | 21h | 03h | 09h | 15h | 21h | 03h | 09h | 15h | 21h |
| Météo | | | | | | | | | | | | | | | | | | | | | | | | | | | | |
| Vent (km/h) | 20 | 30 | 45 | 40 | 35 | 25 | 20 | 15 | 15 | 15 | 20 | 20 | 40 | 60 | 30 | 25 | 65 | 75 | 45 | 35 | 50 | 40 | 35 | 35 | 25 | 30 | 25 | 20 |
| à 3000m | | | | | | | | | | | | | | | | | | | | | | | | | | | | |
| Vent (km/h) | 5 | 10 | 20 | 15 | 15 | 15 | 15 | 10 | 10 | 10 | 20 | 10 | 15 | 30 | 20 | 15 | 20 | 40 | 20 | 10 | 15 | 20 | 25 | 15 | 10 | 10 | 15 | 10 |
| à 2000m | | | | | | | | | | | | | | | | | | | | | | | | | | | | |

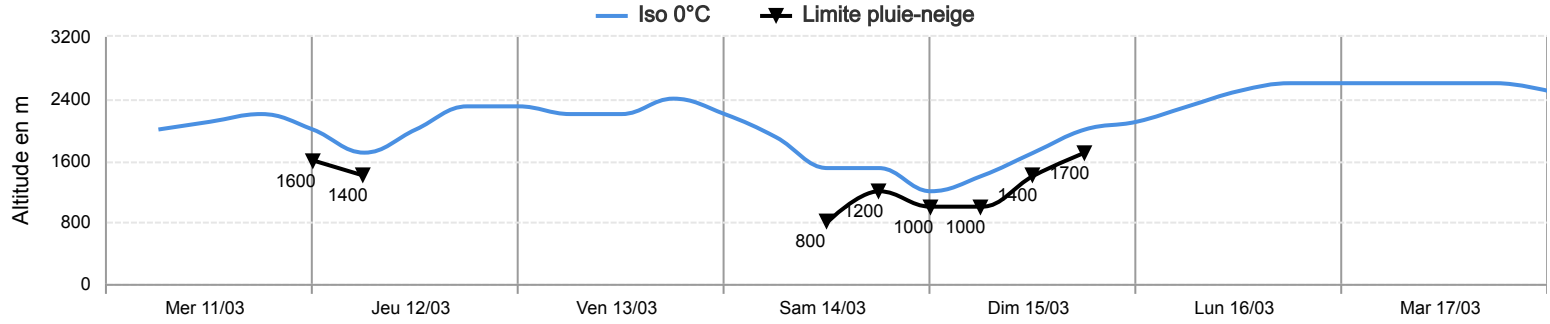


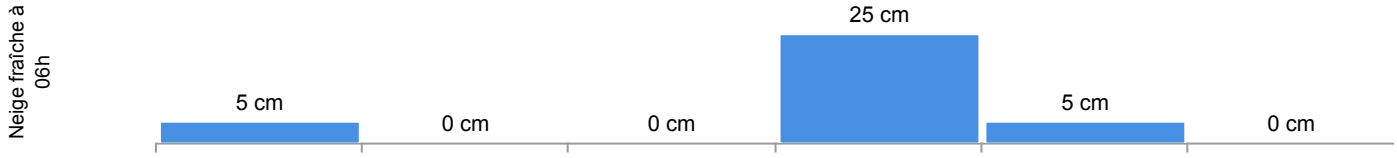


| Risque d'avalanche | mer. 11/03 | jeu. 12/03 | ven. 13/03 | sam. 14/03 | dim. 15/03 | lun. 16/03 | mar. 17/03 |
|---|---|---|---|---|---|---|---|
| | 2 | 2 | 2 | 3 | 3 | 3 | 2 |

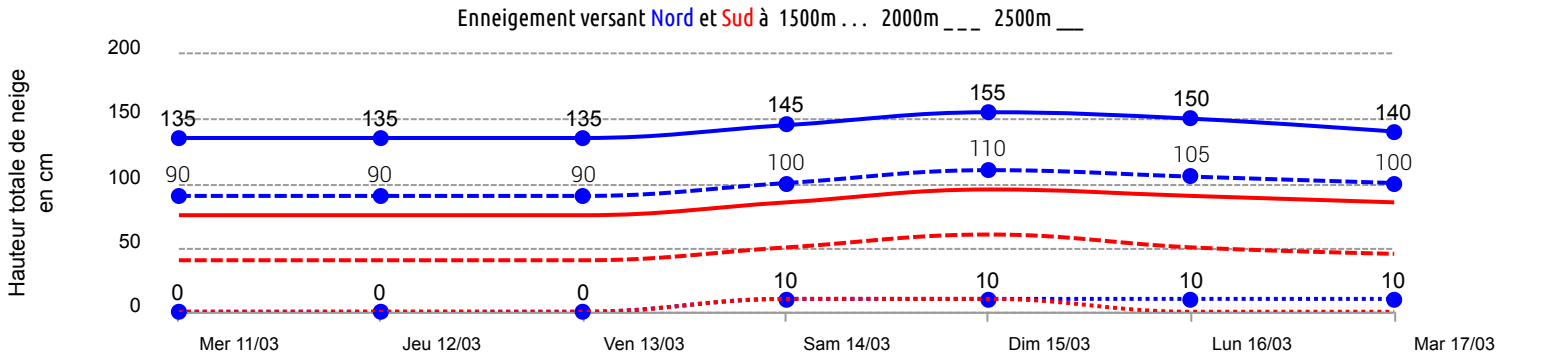


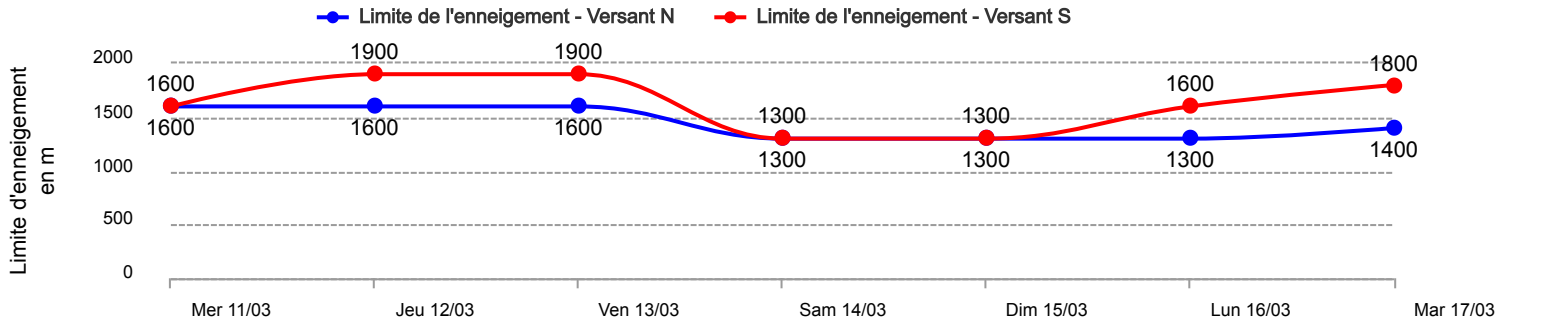


Pour consulter la vigilance en cours, veuillez vous rendre sur le site https://vigilance.meteofrance.fr/fr


**Météo-France - 73 avenue de Paris, 94165 Saint-Mandé cedex - Contact : contact@meteo.fr**


Rédigé par Météo-France avec la contribution des observateurs du réseau nivo-météorologiques. Partenariat : ANMSM (Maires de Stations de Montagne), DSF (Domaines Skiables de France), ADSP (Directeurs de Pistes et de la Sécurité des Stations de Sports d'Hiver) et autres acteurs de la montagne.

**Bulletin neige & avalanches par téléphone au**

**0 892 68 10 20** Service 0,35 € / min + prix appel