GOBIERNO DE ESPAÑA
VICEPRESIDENCIA TERCERA DEL GOBIERNO
MINISTERIO PARA LA TRANSICIÓN ECOLÓGICA Y EL RETO DEMOGRÁFICO

Boletín de información nivológica y de peligro de aludes

Pirineo Catalán

aemet Agencia Estatal de Meteorología

miércoles, 18 de marzo de 2026

Pronóstico hasta las 24 horas del jueves, día 19 de marzo

(Válido fuera de pistas de esquí balizadas y abiertas)

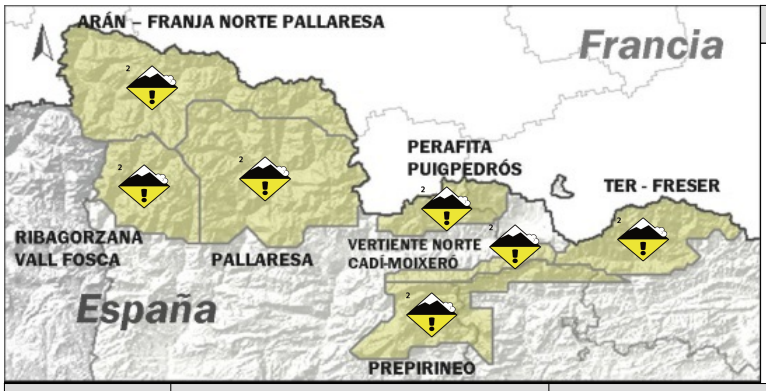

Problemas de aludes

Nieve húmeda

Placas de viento

Macizo	Peligro	Problemas de aludes, cota, orientación, tamaño	Innivación observada (m)
Arán - Franja norte Pallaresa	2 Limitado	Nieve húmeda: 2 / Placas de viento: 2, 2100	2026-03-18 Cota más baja caras N
Ribagorzana - Vall Fosca	2 Limitado	Nieve húmeda: 2 / Placas de viento: 2, 2200	2026-03-18 Cota más baja caras N
Pallaresa	2 Limitado	Nieve húmeda: 2 / Placas de viento: 2, 2200	2026-03-18 Cota más baja caras N

AEMET. Se autoriza la reproducción de su contenido citando la fuente.

Boletín de información nivológica y de peligro de aludes

Pirineo Catalán

Perafita - Puigpedrós	**Limitado**	**Nieve húmeda** 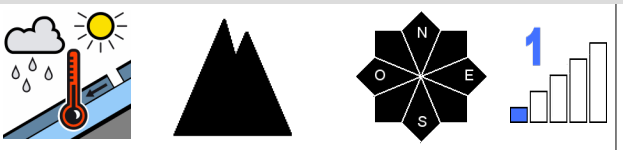 **Placas de viento** 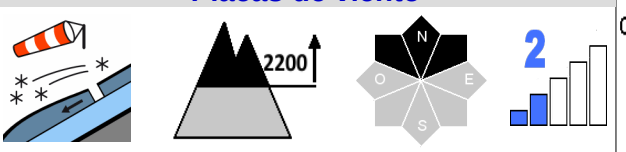	2026-03-18 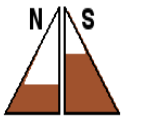 Cota más baja caras N
Ter - Freser	**Limitado**	**Nieve húmeda** 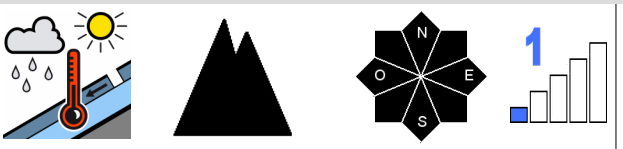 **Placas de viento** 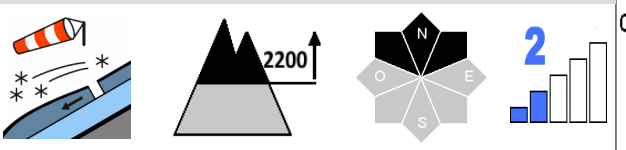	2026-03-18 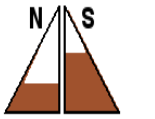 Cota más baja caras N
Vertiente norte Cadí - Moixeró	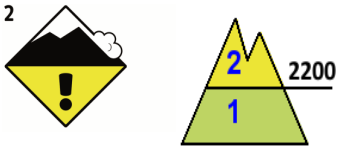 **Limitado**	**Nieve húmeda** 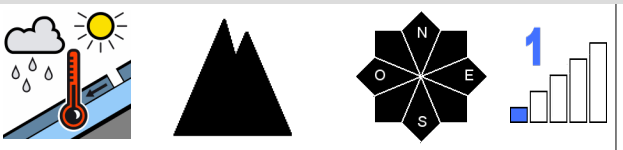 **Placas de viento** 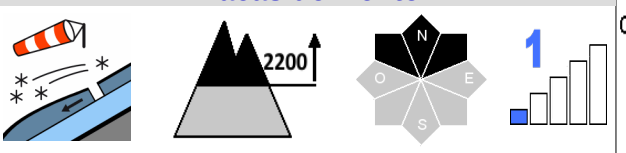	2026-03-18 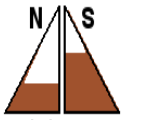 Cota más baja caras N
Prepirineo	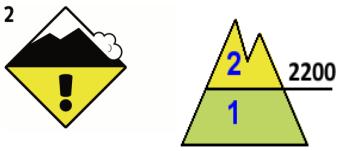 **Limitado**	**Nieve húmeda** 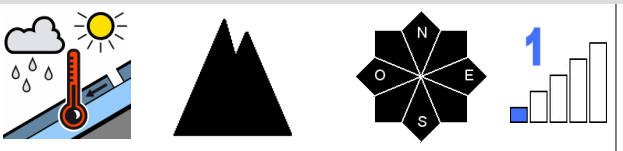 **Placas de viento** 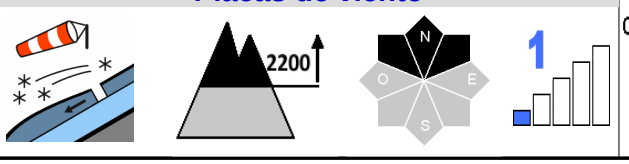	2026-03-18 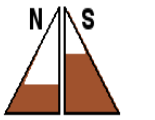 Cota más baja caras N

Estado del manto y observaciones recientes

Los cielos poco nubosos y la entrada de una masa de aire más cálida están siendo los fenómenos meteorológicos más relevantes para la nieve en los últimos dos días. La humidificación ha afectado a la mayoría de zonas, excepto a las umbrías de cotas altas, purgando de manera importante las laderas inclinadas. Esto deja unas cotas bajas y medias con nieve húmeda hasta la base. En cotas altas, tenemos nieve húmeda superficial en las solanas y nieve seca, venteada o encostrada, en las umbrías, la cual se aposenta sobre capas débiles persistentes activas no especialmente profundas. Además, toda la nieve húmeda

AEMET. Se autoriza la reproducción de su contenido citando la fuente.

superficial se encuentra bajo ciclo diario de fusión-rehielo, dando lugar a gruesas costras que estabilizan el manto a primeras horas.

La cubierta de nieve se muestra continua desde cotas bajas-medias y presenta una notable asimetría norte-sur. Los espesores van menguando algunos centímetros al día y son mayores en el aréa occidental que en la oriental, aunque ambas están en valores máximos para la época. Por encima de 2200 metros y de manera general, se superan los dos metros en los macizos occidentales y el metro en los orientales.

Evolución del manto y peligro de aludes para el jueves, día 19

Problema de placas de viento y capas débiles persistentes en cotas altas. Problema de nieve húmeda.

La entrada de abundante nubosidad baja, ya durante la madrugada, inhibirá notablemente la formación de costra de rehielo para mañana. Las purgas de nieve húmeda seguirán siendo posibles en laderas lo suficientemente inclinadas, en las zonas en contacto con esta nubosidad baja. La disminución de la radiación solar y la purga de días previos harán estos aludes menos frecuentes, aunque localmente sigan pudiendo alcanzar el tamaño mediano. Este tipo de aludes también se podrán producir de manera accidental. No se descarta algún deslizamiento basal que pueda alcanzar un tamaño superior.

En umbrías de cotas altas, se alternan zonas con estructura de placa sobre capa débil que podrían colapsar ante el peso de una sola persona. Estas son, en general, distinguibles al contraste con la nieve marrón antigua. Su desencadenamiento podrá dar lugar a aludes de tamaño mediano, raramente grande.

Predicción meteorológica para el jueves, día 19

Nuboso o muy nuboso, con nubes bajas y algunas de evolución diurna, tendiendo a disminuir la nubosidad hacia el final del día. Precipitaciones débiles y dispersas durante la primera mitad del día, más probables en los macizos orientales. No se descartan algunos chubascos vespertinos en el norte del Arán, que podrían ser ocasionalmente tormentosos. Cota de nieve entre 1300 y 1900 metros aproximadamente, generalmente más baja hacia el este. Temperaturas en descenso, notable de las máximas. Heladas débiles en cotas altas, localmente moderadas. Viento flojo o moderado de componentes sur y este. En cotas altas, soplará flojo de dirección variable.

Datos en la atmósfera libre:

Altitud de la isoterma de 0 ºC: 2000 m
Altitud de la isoterma de -10 ºC: 3800 m

Viento a 1500 m: S 10 km/h
Viento a 3000 m: VRB 10 km/h

Evolución para el viernes día 20

Nivel de peligro con pocos cambios, con probable formación de costra de rehielo que estabilice el manto primeras horas.

AEMET. Se autoriza la reproducción de su contenido citando la fuente.

Boletín de información nivológica y de peligro de aludes

Pirineo Catalán

Escala europea de peligro de aludes

Débil | Limitado | Notable | Fuerte | Muy Fuerte

Problemas de aludes

Nieve reciente | Placas de viento | Capas débiles persistentes | Nieve húmeda | Deslizamientos basales | Sin problema evidente

Nota1: Se recuerda que, siempre que haya nieve, la ausencia total de peligro no existe. Hay que tener presente que en circunstancias desfavorables, con aludes de tamaño 1 (alud pequeño o colada) y tamaño 2 (alud mediano), se pueden sufrir severos daños personales.

Nota2: Los BPA se elaboran en base a información meteorológica así como al estado del manto nivoso a través de sondeos puntuales. Se advierte a los usuarios de la variabilidad de esta información al extrapolarla a zonas extensas de montaña. Por ello, AEMET no se hace responsable de su uso para la toma de decisiones que conciernen a la seguridad personal, ni de los riesgos físicos o materiales de ellas derivadas.

AEMET. Se autoriza la reproducción de su contenido citando la fuente.