ICGC Institut Cartogràfic i Geològic de Catalunya

Servei Meteorològic de Catalunya meteo.cat

Boletín de peligro de aludes para el Pirineo de Catalunya
Del 18/03/2026 al 19/03/2026

(Válido fuera pistas de esquí y zonas no controladas)

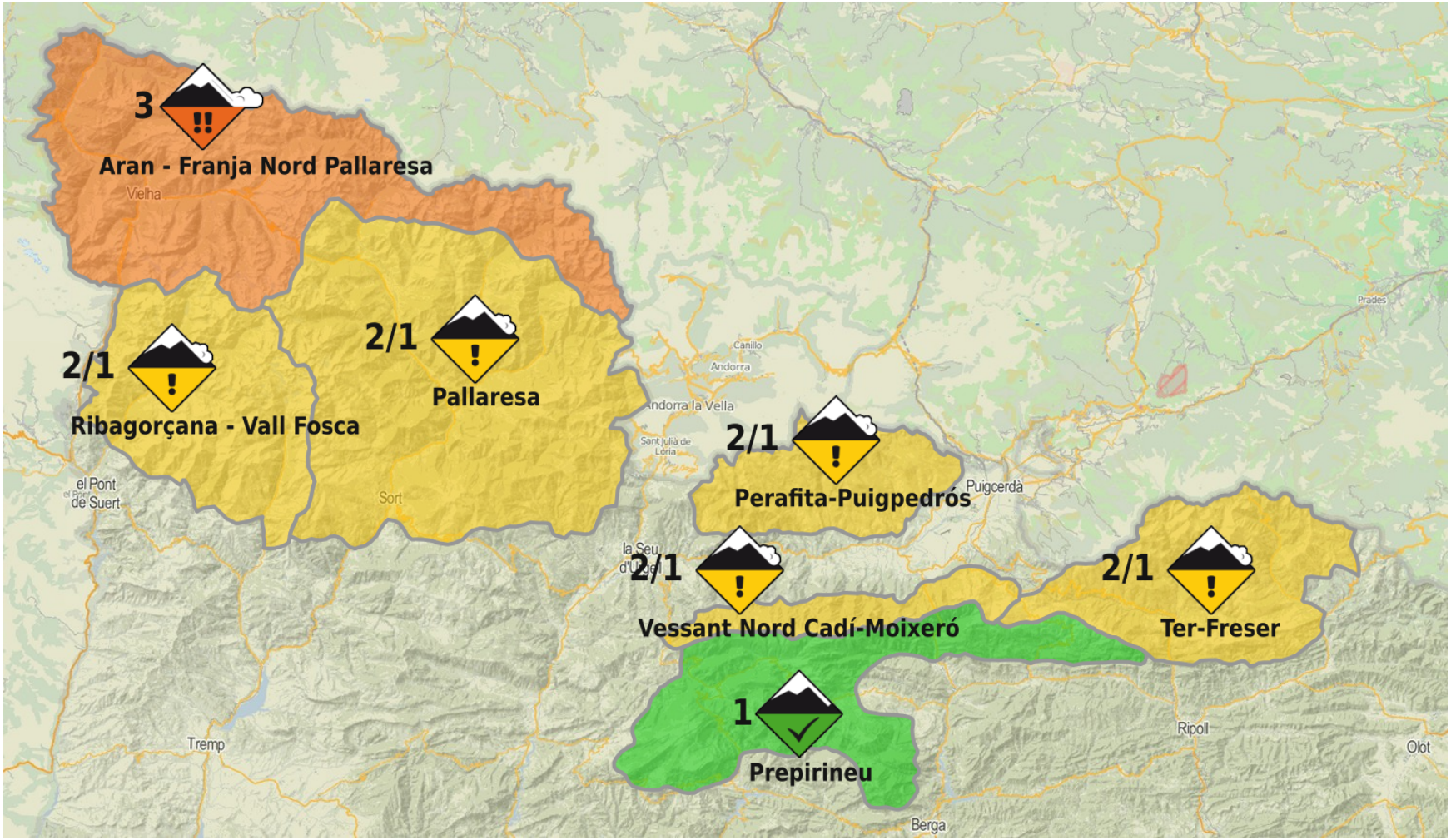

5 MUY FUERTE	4 FUERTE	3 NOTABLE	2 LIMITADO	1 DÉBIL

ICGC Institut Cartogràfic i Geològic de Catalunya

Servei Meteorològic de Catalunya

Boletín de peligro de aludes Aran - Franja Nord Pallaresa Del 18/03/2026 al 19/03/2026

(Válido fuera pistas de esquí y zonas no controladas)

NOTABLE (3)

Situación primaria

Capas débiles persistentes

Distribución

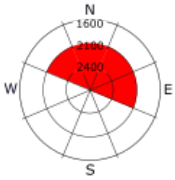

Tamaño

Origen

Tendencia

Situación secundaria

Nieve húmeda

Distribución

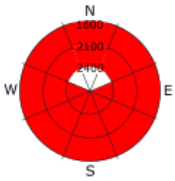

Tamaño

Origen

Tendencia

Estado del manto nivoso

El problema de las capas débiles persistentes sigue presente, con un manto que presenta una estabilidad pobre, especialmente en las placas formadas durante el pasado fin de semana y que permanecen sobre facetas o escarcha. Estos días se ha observado actividad natural y también al paso de esquiadores, y al desplazarse por el terreno se escuchan woumfs y los tests de estabilidad dan fracturas y propagaciones.

Es necesario prestar atención, ya que podemos desencadenar fácilmente placas, especialmente por encima de los 2.000 m, en orientaciones NW, N, NE y E. La rotura de las placas y su desencadenamiento pueden dar lugar a aludes de tamaño medio, con capacidad de enterrar a una persona e incluso de tamaño 3 (grande), suficiente para enterrar a un grupo de montañeros, sobre todo en laderas umbrías protegidas del viento y bajo collados y crestas. También son probables aludes de nieve húmeda a partir del mediodía, de hasta tamaño 2 (medio), en las solanas y hasta cota media en las umbrías.

Distribución del manto nivoso

Hay nieve por encima de unos 1.400-1-500 m en umbrías y 1.700 m en solanas. Los espesores a unos 2.200 m son superiores a los normales en la Franja Norte de la Pallaresa y en la mitad sur del Aran donde rondan los 180-220 cm. En la mitad norte de Arán hay unos 120-140 cm de grosor total.

Tendencia para las próximas 48-72h

Continuaremos con las capas débiles persistentes en umbrías. Peligro: SIN CAMBIOS

El próximo boletín será emitido el día 2026-03-19

5 MUY FUERTE	4 FUERTE	3 NOTABLE	2 LIMITADO	1 DÉBIL

EAWS EUROPEAN AVALANCHE WARNING SERVICES

ICGC Institut Cartogràfic i Geològic de Catalunya

Servei Meteorològic de Catalunya meteo.cat

Boletín de peligro de aludes Ribagorçana - Vall Fosca Del 18/03/2026 al 19/03/2026

(Válido fuera pistas de esquí y zonas no controladas)

LIMITADO (2), por encima de 2.300 m.
DÉBIL (1), en el resto.

Situación primaria

Nieve húmeda

Distribución

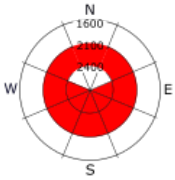

Tamaño

Origen

Tendencia

Situación secundaria

Capas débiles persistentes

Distribución

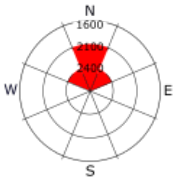

Tamaño

Origen

Tendencia

Estado del manto nivoso

Para el jueves esperamos problemas relacionados con la nieve húmeda y la presencia de niveles débiles enterrados. Se espera poco rehielo por la presencia de nubes bajas. Con el humedecimiento del manto pueden caer aludes de fusión de forma natural que llegarán a tamaño 1(pequeño), sin capacidad para enterrar a una persona. El terreno más afectado por aludes de fusión son las salidas de puntos oscuros (rocas y árboles) y las orientaciones este, sur y oeste. No se descartan tampoco a umbrías de cota media. Las placas de viento formadas durante el fin de semana permanecen sobre niveles débiles (facetas o nieve granulada) y pueden caer a nuestro paso. Los lugares peligrosos están bajo collados y cordales, por encima de 2.300-2.400 m y también en las orientaciones umbrías resguardadas en N, NE y NW, entre 2200 y 2400 m. Las placas, en caso de romperse, podrán generar aludes de tamaño 2 (medio), con capacidad de enterrar a un montañero.

Distribución del manto nivoso

Hay nieve en el suelo a 1.600 m en terreno umbrío, y por encima de unos 1.800 m en laderas soleadas. El manto es esquiable por encima de unos 1.800-1.900 m en umbrías. Los grosores alcanzan los 105-135 cm a unos 2.200 m. Estos valores son superiores a los normales para la época.

Tendencia para las próximas 48-72h

Continuaremos con las capas débiles persistentes en umbrías. Peligro: SIN CAMBIOS

El próximo boletín será emitido el día 2026-03-19

5 MUY FUERTE	4 FUERTE	3 NOTABLE	2 LIMITADO	1 DÉBIL

EAWS EUROPEAN AVALANCHE WARNING SERVICES

ICGC Institut Cartogràfic i Geològic de Catalunya

Servei Meteorològic de Catalunya

Boletín de peligro de aludes Pallaresa
Del 18/03/2026 al 19/03/2026

(Válido fuera pistas de esquí y zonas no controladas)

LIMITADO (2), por encima de 2.300 m.
DÉBIL (1), en el resto.

Situación primaria

Nieve húmeda

Distribución

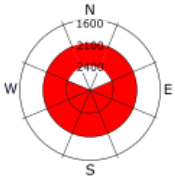

Tamaño

Origen

Tendencia

Situación secundaria

Capas débiles persistentes

Distribución

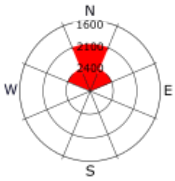

Tamaño

Origen

Tendencia

Estado del manto nivoso

Para el jueves esperamos problemas relacionados con la nieve húmeda y la presencia de niveles débiles enterrados. Se espera poco rehielo por la presencia de nubes bajas. Con el humedecimiento del manto pueden caer aludes de fusión de forma natural que llegarán a tamaño 1 (pequeño), sin capacidad para enterrar a una persona. El terreno más afectado por aludes de fusión son las salidas de puntos oscuros (rocas y árboles) y las orientaciones este, sur y oeste. No se descartan tampoco en umbrías de cota media. Las placas de viento formadas durante el fin de semana permanecen sobre niveles débiles (facetas o nieve granulada) y pueden caer a nuestro paso. Los lugares peligrosos están bajo collados y cordales, por encima de 2.300-2.400 m y también en las orientaciones umbrías resguardadas en N, NE y NW, entre 2200 y 2400 m. Las placas, en caso de romperse, podrán generar aludes de tamaño 2 (medio), con capacidad de enterrar a un montañero.

Distribución del manto nivoso

Hay nieve en el suelo a 1.600 m en N, y a 1.800-1.900 m en S. El manto es esquiable por encima de unos 1.800-1.900 m en umbrías. Los espesores alcanzan los 115-155 cm en cotas medias, variable según los efectos del viento.

Tendencia para las próximas 48-72h

Continuaremos con las capas débiles persistentes en umbrías. Peligro: SIN CAMBIOS

El próximo boletín será emitido el día 2026-03-19

5 MUY FUERTE	4 FUERTE	3 NOTABLE	2 LIMITADO	1 DÉBIL

EAWS EUROPEAN AVALANCHE WARNING SERVICES

ICGC Institut Cartogràfic i Geològic de Catalunya

meteo.cat Servei Meteorològic de Catalunya

Boletín de peligro de aludes Perafita-Puigpedrós Del 18/03/2026 al 19/03/2026

(Válido fuera pistas de esquí y zonas no controladas)

LIMITADO (2), por encima de 2.300 m.
DÉBIL (1), en el resto.

Situación primaria

Nieve húmeda

Distribución

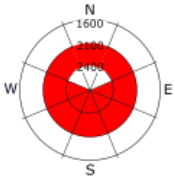

Tamaño

Origen

Tendencia

Situación secundaria

Capas débiles persistentes

Distribución

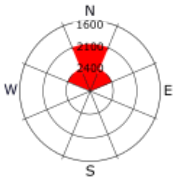

Tamaño

Origen

Tendencia

Estado del manto nivoso

El jueves se espera poco rehielo por la presencia de nubes bajas. Con el humedecimiento del manto pueden caer aludes de fusión de forma natural que llegarán a tamaño 1(pequeño), sin capacidad para enterrar a una persona. El terreno más afectado por aludes de fusión son las salidas de puntos oscuros (rocas y árboles) y las orientaciones este, sur y oeste. No se descartan tampoco en umbrías de cota media. Las placas de viento formadas durante el fin de semana permanecen sobre niveles débiles (facetas o nieve granulada) y pueden caer a nuestro paso. Los lugares peligrosos están bajo collados y cordales, por encima de 2.300-2.400 my también en las orientaciones umbrías resguardadas en N, NE y NW, entre 2200 y 2400 m. Las placas, en caso de romperse, podrán generar aludes de tamaño 2 (medio), con capacidad de enterrar a un montañero.

Distribución del manto nivoso

En umbrías hay nieve por encima de 1.400-1.500 m, y en las solanas está presente por encima de 1.700 m. Los espesores, aunque irregulares, rondan los 85-105 cm en cotas medias. Son grosores por encima de los habituales para la época.

Tendencia para las próximas 48-72h

Continuaremos con las capas débiles persistentes en umbrías. Peligro: SIN CAMBIOS

El próximo boletín será emitido el día 2026-03-19

5 MUY FUERTE	4 FUERTE	3 NOTABLE	2 LIMITADO	1 DÉBIL

EAWS EUROPEAN AVALANCHE WARNING SERVICES

ICGC Institut Cartogràfic i Geològic de Catalunya

Servei Meteorològic de Catalunya meteo.cat

Boletín de peligro de aludes
Vessant Nord Cadí-Moixeró
Del 18/03/2026 al 19/03/2026

(Válido fuera pistas de esquí y zonas no controladas)

LIMITADO (2) por encima de 2200 m.
DÉBIL (1) por debajo.

Situación primaria

Nieve húmeda

Distribución

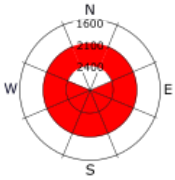

Tamaño

Origen

Tendencia

Estado del manto nivoso
Seguiremos con problemas por nieve húmeda y la presencia de alguna placa antigua, en cota alta. El jueves se espera poco rehielo por la presencia de nubes bajas y algún chubasco. Con el humedecimiento del manto pueden caer aludes de fusión de forma natural que llegarán a tamaño 1 (pequeño), sin capacidad para enterrar a una persona, excepto en terreno trampa donde habrá que evitar pasar mientras la nieve no rehiele. Las orientaciones más peligrosas son las orientadas a Este, Sur, Oeste y umbrías de cota media. El terreno más afectado por aludes de fusión son las zonas de salida de puntos oscuros como rocas y árboles. Por otra parte, todavía podemos encontrar alguna placa antigua formada durante el pasado fin de semana que podría caer a nuestro paso, por ejemplo, en una caída, esquiando. Las encontraremos en lo alto de las Canals y bajo collados y crestas más elevadas, entre 2200-2400 m.

Distribución del manto nivoso
En umbrías hay nieve por encima de 1.400-1.500 m, y en las solanas está presente por encima de 1.500 m. El manto nivoso es esquiable por encima de unos 1.800 m. Los grosores están alrededor de 160-180 cm a 2.200 m. Estos valores son muy excedentarios para la época del año.

Tendencia para las próximas 48-72h
Leve descenso de los problemas por nieve húmeda. Peligro: SIN CAMBIOS.

El próximo boletín será emitido el día 2026-03-19

5 MUY FUERTE	4 FUERTE	3 NOTABLE	2 LIMITADO	1 DÉBIL

EAWS EUROPEAN AVALANCHE WARNING SERVICES

ICGC Institut Cartogràfic i Geològic de Catalunya

Servei Meteorològic de Catalunya

Boletín de peligro de aludes Prepirineu
Del 18/03/2026 al 19/03/2026

(Válido fuera pistas de esquí y zonas no controladas)

DÉBIL (1).

Situación primaria

Nieve húmeda

Distribución

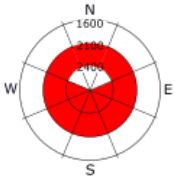

Tamaño

Origen

Tendencia

Estado del manto nivoso

El manto se muestra bastante asentado y endurecido internamente y en superficie se ha humedecido con el ascenso térmico. Para el jueves, aumenta la nubosidad y la nieve se podrá volver a humedecer, sin esperar mucho rehielo. No se descarta la caída de algún alud húmedo, pequeño, que no tendrá capacidad para enterrar a una persona, excepto en terreno trampa donde habrá que evitar pasar mientras la nieve no rehiele. Las orientaciones más sensibles a la caída de aludes de nieve húmeda son las orientadas a Este, Sur y Oeste, así como las umbrías de cota media.

Distribución del manto nivoso

En umbrías hay nieve por encima de 1.600-1700 m. En solanas la nieve está presente por encima de 1.800-1.900 m. Los espesores, aunque irregulares, rondan los 65-85 cm en cotas medias.

Tendencia para las próximas 48-72h

Leve descenso de los problemas por nieve húmeda. Peligro: SIN CAMBIOS.

El próximo boletín será emitido el día 2026-03-19

5 MUY FUERTE	4 FUERTE	3 NOTABLE	2 LIMITADO	1 DÉBIL

EAWS EUROPEAN AVALANCHE WARNING SERVICES

ICGC Institut Cartogràfic i Geològic de Catalunya

Servei Meteorològic de Catalunya

Boletín de peligro de aludes Ter-Freser
Del 18/03/2026 al 19/03/2026

(Válido fuera pistas de esquí y zonas no controladas)

LIMITADO (2), a partir de 2.300 m.
DÉBIL (1), en el resto.

Situación primaria

Nieve húmeda

Distribución

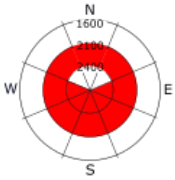

Tamaño

Origen

Tendencia

Situación secundaria

Capas débiles persistentes

Distribución

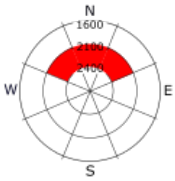

Tamaño

Origen

Tendencia

Estado del manto nivoso

Para el jueves esperamos problemas relacionados con la nieve húmeda y la presencia de niveles débiles enterrados. Se espera poco rehielo por la presencia de nubes bajas. Con el humedecimiento del manto pueden caer aludes de fusión de forma natural que llegarán a tamaño 1(pequeño), sin capacidad para enterrar a una persona. También es posible encontrar alguna placa antigua, formada durante el fin de semana, donde el viento no haya deflactado las laderas y encima de algún nivel débil que podría caer a nuestro paso. Las encontraremos bajo collados y cordales por encima de 2.300 m, en orientaciones que van de E hacia S y, aisladamente, en umbrías resguardadas como N, NE y NW entre 2.200-2.400 m. En caso de romperse alguna placa se generarán aludes de hasta tamaño medio (con capacidad de enterrar a una persona).

Distribución del manto nivoso

Hay nieve en el suelo por encima de 1.600-1.700 m. Es esquiable a partir de unos 1700 m. El manto nivoso presenta grosores muy excedentarios para la época del año. En lugares no afectados por el viento los grosores oscilan entre 85-105 cm a unos 2.000 m y más de 150 cm por encima de 2.400 m.

Tendencia para las próximas 48-72h

Leve descenso de los problemas por nieve húmeda. Peligro: SIN CAMBIOS

El próximo boletín será emitido el día 2026-03-19

5 MUY FUERTE	4 FUERTE	3 NOTABLE	2 LIMITADO	1 DÉBIL

EAWS EUROPEAN AVALANCHE WARNING SERVICES