BUTLLETÍ DEL PERILL D'ALLAUS DEL PRINCIPAT D'ANDORRA

Servei meteorològic nacional
Principat d'Andorra

Elaborat el 18/03/2026 16:00
Propera actualització 19/03/2026 a les 16h

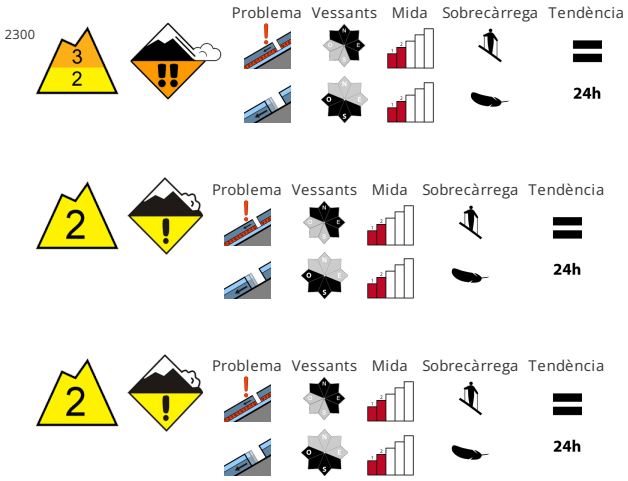

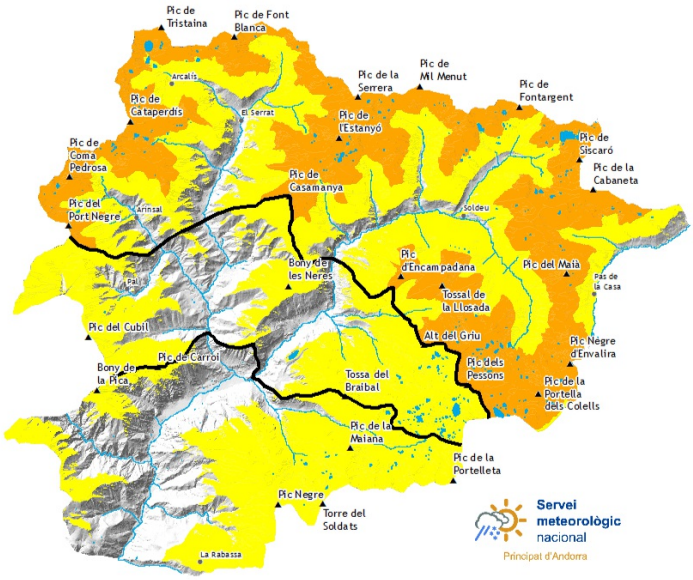

ESTABILITAT DEL MANTELL NIVAL

Sobretot als vessants inclinats orientats a nord-oest, nord i est a la part superior del mantell de neu hi ha capes febles inestables. Aquestes poden ser desencadenades fàcilment i assolir mida mitjana. Els indrets perillosos es troben prop del límit del bosc i també a les transicions de mantell prim a gruixut. Amb la penetració de la humitat són possibles allaus de lliscament basal. Els indrets perillosos són difícils de reconèixer amb mala visibilitat. El perill d'allaus romandrà invariable.

QUALITAT DE LA NEU

Durant la nit caurà neu per sobre dels 2000 m aproximadament. La superfície del mantell de neu es refredarà tot just durant la nit ennuvolada i s'estovarà ja durant el matí. Prop de les carenes els gruixos de neu varien molt per la influència del vent. Són enganyosos els vessants amb acumulacions de neu ventada. Es recomana mantenir la distància entre els components.

GRUIXOS DEL MANTELL NIVAL FORA DE PISTA

Zona nord		Gruix neu		
Mantell Nival		1500m	2000m	2500m
N	1600 m	0 cm	150 cm	200 cm
S	1900 m	0 cm	100 cm	150 cm

Zona centre		Gruix neu		
Mantell Nival		1500m	2000m	2500m
N	1600 m	0 cm	150 cm	200 cm
S	1900 m	0 cm	100 cm	150 cm

Zona sud		Gruix neu		
Mantell Nival		1500m	2000m	2500m
N	1600 m	0 cm	120 cm	150 cm
S	1900 m	0 cm	60 cm	100 cm

Govern d'Andorra

EAWS EUROPEAN AVALANCHE WARNING SERVICES

Aquest butlletí ha estat elaborat seguint les normes i recomanacions de l'**European Avalanche Warning Services**, del qual el **Servei meteorològic Nacional** n'és membre

BUTLLETÍ DEL PERILL D'ALLAUS DEL PRINCIPAT D'ANDORRA

Servei meteorològic nacional
Principat d'Andorra

Informació detallada per espais naturals protegits

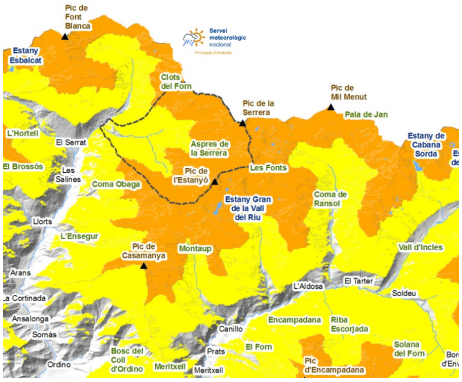

SORTENY

L´ambient hivernal del cap de setmana va enterrar la neu vella, però el vent la va deixar al descobert en canvis de rasant, crestes i vessants orientats a nord. Atenció amb les plaques de vent dels vessants est, sud i oest, on s´hi haurà de circular amb més prudència. L´augment de les temperatures diürnes ha fet que la textura de la neu sigui molt diferent en pocs metres, ja que la neu nova s´humidifica més ràpid i llisca menys. Els pocs centímetres que cauran fins dijous no modificaran les condicions actuals.

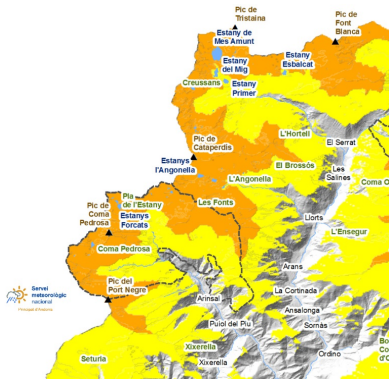

COMAPEDROSA

A cotes altes, la neu vella està ben regelada i al descobert als indrets ventats. La identificarem pel canvi de color amb la neu nova. Serà més segur i estable circular per la neu vella. La neu nova no ha sigut suficient per tapar les esquerdes de lliscament basal, que encara representen un perill de caiguda.

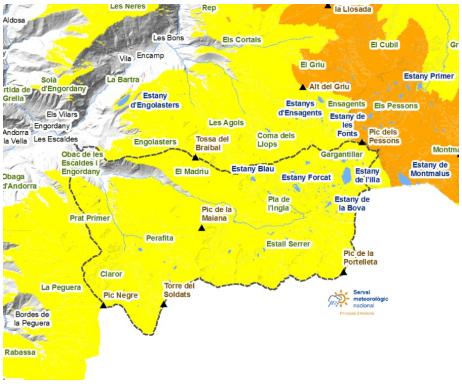

MADRIU-PERAFITA-CLAROR

Els accessos amb esquís des dels Cortals d´Encamp, la Rabassa i Grau Roig continuen ben nevats, però la neu ventada als vessants nord i est ens ha de fer circular amb precaució.

Govern d'Andorra

EAWS
EUROPEAN AVALANCHE WARNING SERVICES

Aquest butlletí ha estat elaborat seguint les normes i recomanacions de l'**European Avalanche Warning Services**, del qual el **Servei meteorològic Nacional** n'és membre

BUTLLETÍ DEL PERILL D'ALLAUS DEL PRINCIPAT D'ANDORRA

Servei meteorològic nacional
Principat d'Andorra

Gruixos de neu nova dels darrers dies (de les últimes 24h mesurat a les 06:00h UTC)

	14/03/2026	15/03/2026	16/03/2026	17/03/2026
FEDA (Central)	0 cm	0 cm	0 cm	0 cm
Engolasters - FEDA	6 cm	0 cm	0 cm	0 cm
Bony de les Neres	14 cm	0 cm	0 cm	0 cm
Sorteny	25 cm	3 cm	0 cm	0 cm
Les Fonts d'Arinsal	26 cm	0 cm	0 cm	0 cm
Perafita	4 cm	34 cm	0 cm	0 cm
Tossa Espiolets	0 cm	0 cm	0 cm	0 cm
Grau Roig - FEDA	21 cm	0 cm	0 cm	0 cm
Fontverd	29 cm	0 cm	0 cm	0 cm
Ransol - FEDA	8 cm	0 cm	0 cm	0 cm
Caborreu	11 cm	0 cm	0 cm	0 cm
La Solana	29 cm	0 cm	0 cm	0 cm
Coll Pa	4 cm	0 cm	0 cm	4 cm
Envalira Antenes	37 cm	6 cm	0 cm	0 cm
Vall del Riu FEDA	14 cm	0 cm	0 cm	0 cm