BUTLLETÍ DEL PERILL D'ALLAUS DEL PRINCIPAT D'ANDORRA

Elaborado el 18/03/2026 16:00
Proxima actualización 19/03/2026 a las 16h

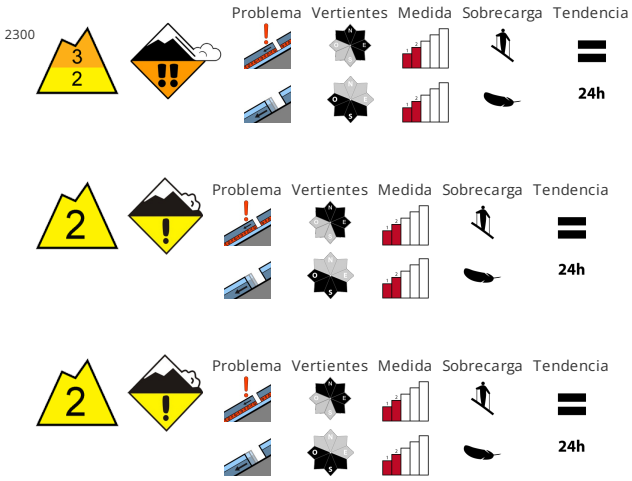

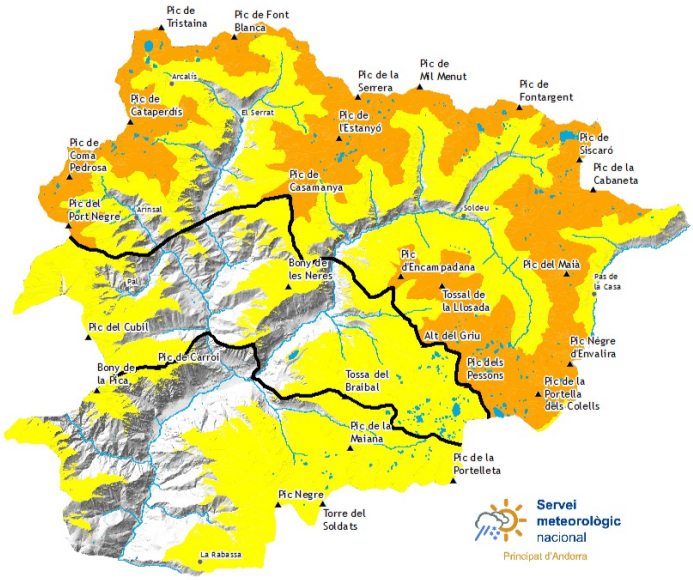

CALIDAD DE LA NIEVE

Sobre todo en las laderas inclinadas orientadas a noroeste, norte y este en la parte superior del manto de nieve hay capas débiles inestables. Estas pueden ser desencadenadas fácilmente y alcanzar un tamaño mediano. Los lugares peligrosos se encuentran cerca del límite del bosque y en las transiciones de manto delgado a grueso. Con la penetración de la humedad son posibles avalanchas de deslizamiento basal. Los lugares peligrosos son resultan difíciles de reconocer con poca visibilidad. El peligro de aludes permanecerá invariable.

ESTABILIDAD DEL MANTO NIVOSO

Durante la noche caerá nieve por encima de los 2000 m aproximadamente. La superficie del manto de nieve se enfriará apenas durante la noche nublada y se ablandará ya durante la mañana. Cerca de los cordales los espesores de nieve varían mucho por la influencia del viento. Son engañosas las laderas con acumulaciones de nieve venteada. Se recomienda mantener la distancia de seguridad entre los miembros del grupo.

ESPESORES DEL MANTO NIVOSO FUERA DE PISTA

Zona norte		Espesor nieve		
Manto Nival		1500m	2000m	2500m
N	1600 m	0 cm	150 cm	200 cm
S	1900 m	0 cm	100 cm	150 cm

zona centro		Espesor nieve		
Manto Nival		1500m	2000m	2500m
N	1600 m	0 cm	150 cm	200 cm
S	1900 m	0 cm	100 cm	150 cm

Zona sur		Espesor nieve		
Manto Nival		1500m	2000m	2500m
N	1600 m	0 cm	120 cm	150 cm
S	1900 m	0 cm	60 cm	100 cm

Govern d'Andorra

EAWS EUROPEAN AVALANCHE WARNING SERVICES

Aquest butlletí ha estat elaborat seguint les normes i recomanacions de l'**European Avalanche Warning Services**, del qual el **Servei meteorològic Nacional** n'és membre

BUTLLETÍ DEL PERILL D'ALLAUS DEL PRINCIPAT D'ANDORRA

Servei meteorològic nacional
Principat d'Andorra

Información detallada por espacios naturales protegidos

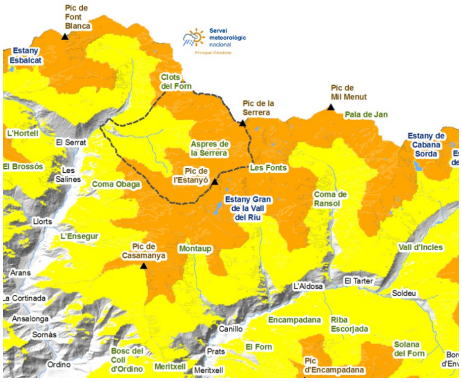

SORTENY

El ambiente invernal del fin de semana enterró a la nieve vieja, pero el viento la dejó al descubierto en cambios de rasante, crestas y vertientes orientadas a norte. Atención con las placas de viento de las vertientes este, sur y oeste, donde se deberá circular con mayor prudencia. El aumento de las temperaturas diurnas ha hecho que la textura de la nieve sea muy diferente en pocos metros, ya que la nieve nueva se humidifica más rápido y se desliza menos. Los pocos centímetros que caerán hasta el jueves no modificarán las condiciones actuales.

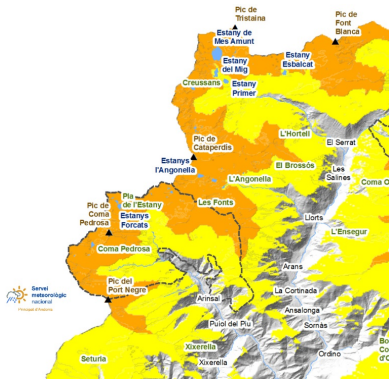

COMAPEDROSA

En cotas altas, la nieve vieja está bien rehilada y al descubierto en los lugares vientos. La identificaremos por el cambio de color con la nieve nueva. Será más seguro y estable circular por la nieve vieja. La nieve nueva no ha sido suficiente para tapar las grietas de deslizamiento basal, que todavía representan un peligro de caída.

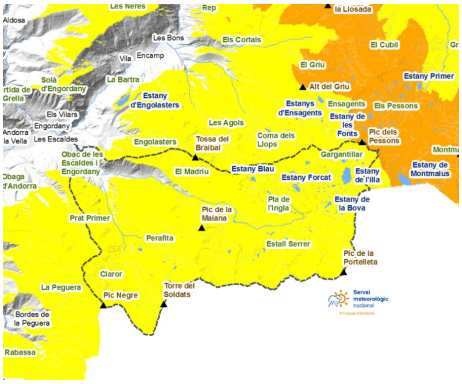

MADRIU-PERAFITA-CLAROR

Los accesos con esquís desde los Cortals d´Encamp, la Rabassa y Grau Roig siguen bien nevados, pero la nieve venteada en las vertientes norte y este nos debe hacer circular con precaución.

Govern d'Andorra

EAWS
EUROPEAN AVALANCHE WARNING SERVICES

Aquest butlletí ha estat elaborat seguint les normes i recomanacions de l'**European Avalanche Warning Services**, del qual el **Servei meteorològic Nacional** n'és membre

BUTLLETÍ DEL PERILL D'ALLAUS DEL PRINCIPAT D'ANDORRA

Servei meteorològic nacional
Principat d'Andorra

Espesores de nieve nueva de los últimos días (de las ultimas 24h mesurado a las 06:00h UTC)

	14/03/2026	15/03/2026	16/03/2026	17/03/2026
FEDA (Central)	0 cm	0 cm	0 cm	0 cm
Engolasters - FEDA	6 cm	0 cm	0 cm	0 cm
Bony de les Neres	14 cm	0 cm	0 cm	0 cm
Sorteny	25 cm	3 cm	0 cm	0 cm
Les Fonts d'Arinsal	26 cm	0 cm	0 cm	0 cm
Perafita	4 cm	34 cm	0 cm	0 cm
Tossa Espiolets	0 cm	0 cm	0 cm	0 cm
Grau Roig - FEDA	21 cm	0 cm	0 cm	0 cm
Fontverd	29 cm	0 cm	0 cm	0 cm
Ransol - FEDA	8 cm	0 cm	0 cm	0 cm
Caborreu	11 cm	0 cm	0 cm	0 cm
La Solana	29 cm	0 cm	0 cm	0 cm
Coll Pa	4 cm	0 cm	0 cm	4 cm
Envalira Antenes	37 cm	6 cm	0 cm	0 cm
Vall del Riu FEDA	14 cm	0 cm	0 cm	0 cm