MINISTERO DELLA DIFESA

meteomont Servizio Nazionale di previsione neve e valanghe

EAWS EUROPEAN AVALANCHE WARNING SERVICES

CARABINIERI

In collaborazione con: arpav

# DOLOMITI MERIDIONALI

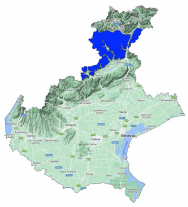

Bollettino Valanghe N. 379/2026 del 18/03/2026 ore 14.00
Validità 48 ore prossima emissione 19/03/2026
**A cura del Servizio METEOMONT dell'ARMA dei CARABINIERI**
**In collaborazione con Servizio Meteorologico dell'Aeronautica militare**

## SITUAZIONE alle 14:00 del 18/03/2026

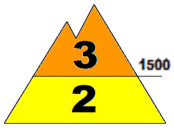


**SITUAZIONE TIPO: neve a debole coesione e vento.**

**SITUAZIONE TIPO: situazione primaverile.**

| Quota neve (mslm) | Nord | Sud |
|---|---|---|
| | 900 - 1700 | 1700 |

| Altezza Neve (cm) | Neve al suolo | Neve Fresca | Quota (mslm) |
|---|---|---|---|
| | 74 | 000 | 1820 |
| | 83 | 00 | 1757 |

**VALANGHE OSSERVATE: -.**

## PREVISIONI 19/03/2026

# GRADO DI PERICOLO: MARCATO 3

## SITUAZIONE TIPO: neve a debole coesione e vento.

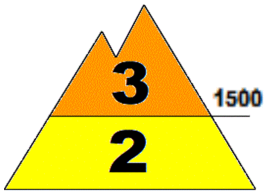


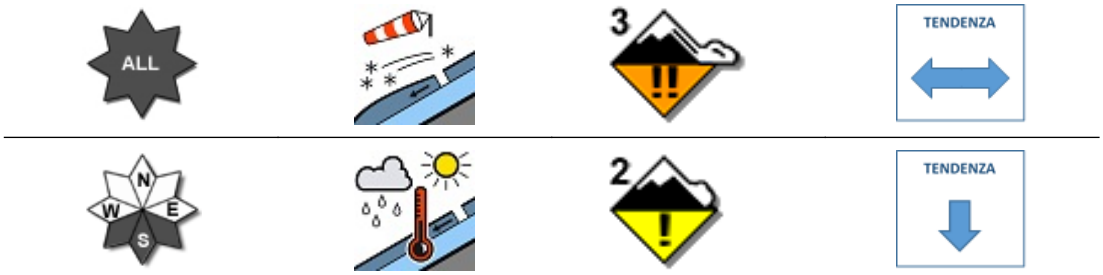


## SITUAZIONE TIPO: situazione primaverile.

**MANTO NEVOSO: La stabilità del manto nevoso è scarsa su molti punti (aree) per tutte le esposizioni al di sopra di 1500 mslm, possibili valanghe di dimensioni medie.**
**La stabilità del manto nevoso è scarsa su alcuni punti (aree) per versanti meridionali al di sotto di 1500 mslm, possibili valanghe di dimensioni medie.**

## AVVERTENZE

A seguito dell'attività eolica registrata sono da evitare le zone di accumulo, conche, canaloni, cambi di pendenza e pendii sotto vento in genere.

## SCALA EUROPEA DEL GRADO DI PERICOLO VALANGHE

5 - MOLTO FORTE | 4 - FORTE | 3 - MARCATO | 2 - MODERATO | 1 - DEBOLE | NO NEVE | NO INFO

## LEGENDA PROBLEMA

NEVE FRESCA | LASTRONI DA VENTO | STRATI DEBOLI PERSISTENTI | NEVE BAGNATA | SLITTAMENTO | CORNICI | NESSUN PROBLEMA VALANGHIVO EVIDENTE | NO_INFO

**Bollettino realizzato su scala sinottica-regionale (standard EAWS). La sua valutazione non può escludere in alcun modo la necessità di una seria e capace valutazione locale del pericolo (singolo pendio) che può essere anche sensibilmente diverso. Le previsioni meteorologiche sono relative all'orario UTC (per l'Italia +1 in inverno e +2 in estate).**

MINISTERO DELLA DIFESA

meteomont
Servizio Nazionale di previsione neve e valanghe

EAWS EUROPEAN AVALANCHE WARNING SERVICES

CARABINIERI

In collaborazione con: arpav

# DOLOMITI MERIDIONALI

## PREVISIONE METEO

| Quota | | 19/03/2026 h6:00 | 19/03/2026 h12:00 | 19/03/2026 h18:00 |
|---|---|---|---|---|
| 1000 | Venti | 03 Nodi da Nord | 02 Nodi da N-Est | 01 Nodi da Est |
| | Temperature | +02 °C | +04 °C | +04 °C |
| | Temp.percepita | 0 °C | 4 °C | 4 °C |
| 2000 | Venti | 12 Nodi da N-Est | 08 Nodi da N-Est | 05 Nodi da N-Est |
| | Temperature | -02 °C | -02 °C | -02 °C |
| | Temp.percepita | -8 °C | -7 °C | -5 °C |
| 3000 | Venti | 12 Nodi da N-Est | 15 Nodi da N-Est | 13 Nodi da N-Est |
| | Temperature | -09 °C | -09 °C | -10 °C |
| | Temp.percepita | -17 °C | -18 °C | -19 °C |
| Zero termico | | 1700-1900 m. | 1700-1900 m. | 1600-1800 m. |
| Fenomeno | | — | — | — |
| Stato del cielo | | | | |

## LEGENDA FENOMENI

— Assenza Fenomeni · Nebbia · Foschia · Pioggia debole · Pioggia moderata · Pioggia forte · Temporali

Nevicata debole · Nevicata moderata · Nevicata forte

## STATO DEL CIELO

Sereno · Poco nuvoloso · Nuvoloso · Molto nuvoloso · Coperto

## Parametri meteonivometrici registrati presso i campi di rilevamento il 18/03/2026.

| Località | Comune | Quota (m.s.l.m.) | Altezza neve (cm) | Neve caduta nelle 24 ore (cm) | Temp. Min (°C) | Temp. Max (°C) | Condizioni del tempo |
|---|---|---|---|---|---|---|---|
| LE BUSE | Falcade (BL) | 1820 | 74 | 0 | -8 | +7 | Precipitazioni all'orizzonte (pioggia, neve, grandine, temporali) ma non sulla stazione |
| COL DEI BALDI * | Selva di Cadore (BL) | 1920 | 108 | 1 | -7 | +7 | Nevicata forte |
| P.SO PADON | Livinallongo del Col di Lana (BL) | 2369 | 88 | 0 | N.P. | N.P. | Nevicata debole continua |

(*) Rilievi fuori campo

**L'INFORMAZIONE E' PREVENZIONE - LEGGI L'ATTUALE GRADO DI PERICOLO VALANGHE!**

IL CAPO DEL CENTRO NAZIONALE METEOMONT
(Ten. Col. RFI Emanuela Gini)
FIRMA AUTOGRAFA OMESSA AI SENSI
DELL'ART.3 DEL D.LGS N.39/1993

Bollettino realizzato su scala sinottica-regionale (standard EAWS). La sua valutazione non può escludere in alcun modo la necessità di una seria e capace valutazione locale del pericolo (singolo pendio) che può essere anche sensibilmente diverso. Le previsioni meteorologiche sono relative all'orario UTC (per l'Italia +1 in inverno e +2 in estate).