MINISTERO DELLA DIFESA

meteomont
Servizio Nazionale di previsione neve e valanghe

EAWS EUROPEAN AVALANCHE WARNING SERVICES

CARABINIERI

APPENNINO EMILIANO CENTRALE

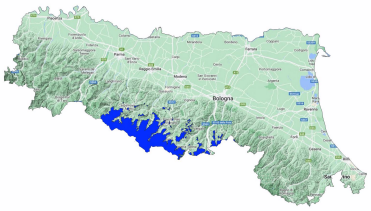

Bollettino Valanghe N. 350/2026 del 18/03/2026 ore 14.00
Validità 48 ore prossima emissione 19/03/2026
A cura del Servizio METEOMONT dell'ARMA dei CARABINIERI
In collaborazione con Servizio Meteorologico dell'Aeronautica militare

SITUAZIONE alle 14:00 del 18/03/2026

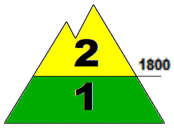

SITUAZIONE TIPO: neve a debole coesione e vento.

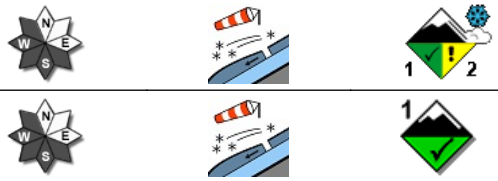

SITUAZIONE TIPO: neve a debole coesione e vento.

	Nord	Sud
Quota neve (mslm)	*1200 - 1300*	*1200 - 1300*

	Neve al suolo	Neve Fresca	Quota (mslm)
Altezza Neve (cm)	*109*	*005*	*1840*
	041	*002*	*1550*

VALANGHE OSSERVATE: Nessuna valanga.

PREVISIONI 19/03/2026

GRADO DI PERICOLO: MODERATO 2

SITUAZIONE TIPO: neve a debole coesione e vento.

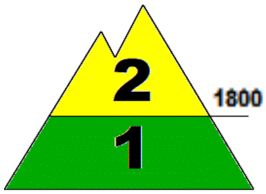

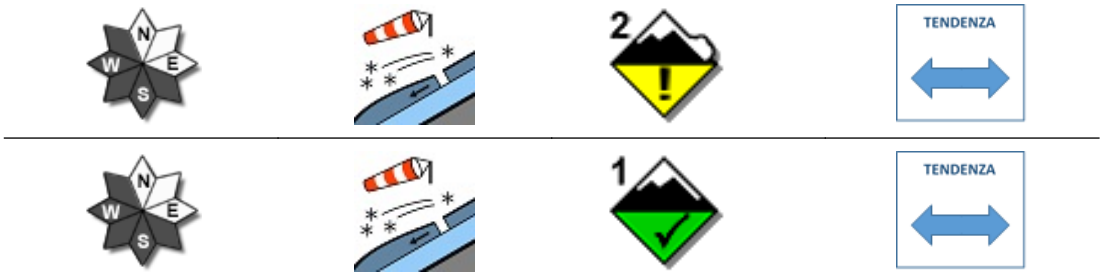

SITUAZIONE TIPO: freddo su caldo / caldo su freddo.

MANTO NEVOSO: La stabilità del manto nevoso è scarsa su alcuni punti (aree) per versanti da sud est a nord ovest al di sopra di 1800 mslm, possibili valanghe di dimensioni medie.
La stabilità del manto nevoso è discreta su pochi punti (aree) per versanti da sud est a nord ovest al di sotto di 1800 mslm, possibili valanghe di dimensioni piccole.

AVVERTENZE

A seguito dell'attività eolica prevista sono da evitare le zone di accumulo, conche, canaloni, cambi di pendenza e pendii sotto vento in genere.

SCALA EUROPEA DEL GRADO DI PERICOLO VALANGHE

5 - MOLTO FORTE | *4 - FORTE* | *3 - MARCATO* | *2 - MODERATO* | *1 - DEBOLE* | NO NEVE *NO NEVE* | *NO INFO*

LEGENDA PROBLEMA

NEVE FRESCA | *LASTRONI DA VENTO* | *STRATI DEBOLI PERSISTENTI* | *NEVE BAGNATA* | *SLITTAMENTO* | *CORNICI* | *NESSUN PROBLEMA VALANGHIVO EVIDENTE* | *NO_INFO*

Bollettino realizzato su scala sinottica-regionale (standard EAWS). La sua valutazione non può escludere in alcun modo la necessità di una seria e capace valutazione locale del pericolo (singolo pendio) che può essere anche sensibilmente diverso. Le previsioni meteorologiche sono relative all'orario UTC (per l'Italia +1 in inverno e +2 in estate).

MINISTERO DELLA DIFESA

meteomont
Servizio Nazionale di previsione neve e valanghe

EAWS EUROPEAN AVALANCHE WARNING SERVICES

CARABINIERI

APPENNINO EMILIANO CENTRALE

PREVISIONE METEO

Quota		19/03/2026 h6:00	19/03/2026 h12:00	19/03/2026 h18:00
1000	Venti	08 Nodi da N-Est	07 Nodi da N-Est	06 Nodi da N-Est
	Temperature	-02 °C	+01 °C	+00 °C
	Temp.percepita	-7 °C	-3 °C	-4 °C
2000	Venti	25 Nodi da N-Est	20 Nodi da N-Est	22 Nodi da N-Est
	Temperature	-05 °C	-05 °C	-04 °C
	Temp.percepita	-15 °C	-14 °C	-13 °C
3000	Venti	22 Nodi da N-Est	19 Nodi da N-Est	21 Nodi da N-Est
	Temperature	-06 °C	-08 °C	-08 °C
	Temp.percepita	-15 °C	-18 °C	-18 °C
Zero termico		0900-1100 m.	1300-1500 m.	1100-1300 m.
Fenomeno		—	—	—
Stato del cielo				

LEGENDA FENOMENI

— Assenza Fenomeni · Nebbia · Foschia · Pioggia debole · Pioggia moderata · Pioggia forte · Temporali

Nevicata debole · Nevicata moderata · Nevicata forte

STATO DEL CIELO

Sereno · Poco nuvoloso · Nuvoloso · Molto nuvoloso · Coperto

Parametri meteonivometrici registrati presso i campi di rilevamento il 18/03/2026.

Località	Comune	Quota (m.s.l.m.)	Altezza neve (cm)	Neve caduta nelle 24 ore (cm)	Temp. Min (°C)	Temp. Max (°C)	Condizioni del tempo
PASSO PRADARENA	Ventasso (RE)	1585	2	0	-4	0	Assenza di precipitazioni
MONTE CUSNA	Villa Minozzo (RE)	1164	0	N.P.	N.P.	N.P.	Assenza di precipitazioni
RIFUGIO CAVONE	Lizzano in Belvedere (BO)	1416	19	1	-3	+2	Assenza di precipitazioni
LAGO DELLA NINFA	Sestola (MO)	1550	41	2	-2	+5	Assenza di precipitazioni
PIANCAVALLARO	Riolunato (MO)	1840	109	5	N.P.	N.P.	Nevicata debole intermittente
PIAN CAVALLARO *	Riolunato (MO)	1897	109	5	N.P.	N.P.	Nevicata moderata

(*) Rilievi fuori campo

L'INFORMAZIONE E' PREVENZIONE - LEGGI L'ATTUALE GRADO DI PERICOLO VALANGHE!

IL CAPO DEL CENTRO NAZIONALE METEOMONT
(Ten. Col. RFI Emanuela Gini)
FIRMA AUTOGRAFA OMESSA AI SENSI
DELL'ART.3 DEL D.LGS N.39/1993

Bollettino realizzato su scala sinottica-regionale (standard EAWS). La sua valutazione non può escludere in alcun modo la necessità di una seria e capace valutazione locale del pericolo (singolo pendio) che può essere anche sensibilmente diverso. Le previsioni meteorologiche sono relative all'orario UTC (per l'Italia +1 in inverno e +2 in estate).