RÉPUBLIQUE FRANÇAISE
Liberté Égalité Fraternité

METEO FRANCE
À VOS CÔTÉS, DANS UN CLIMAT QUI CHANGE

Bulletin d'estimation du risque d'avalanche
(valable en dehors des pistes balisées et ouvertes)
MASSIF : Orlu St-Barthelemy

Rédigé le mercredi 18 mars 2026 à 15h

Estimation des risques pour le : JEUDI 19 MARS

UN PEU D'INSTABILITÉ EN HAUTE MONTAGNE.

2

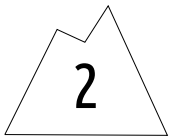

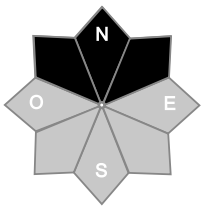

Indice de risque limité.

Départs spontanés : Plaques de fond en moyenne montagne ou coulées en neige humide, y compris en versants nord.

Déclenchements provoqués : Quelques plaques à vent en haute montagne.

Indices de risque : 5 très fort - 4 fort - 3 marqué - 2 limité - 1 faible -- En noir : les pentes les plus dangereuses

Stabilité du manteau neigeux

Situation avalancheuse typique : neige humide avalanches de fond

Déclenchements provoqués :
Quelques structures de plaques potentiellement encore en place dans quelques pentes sommitales raides orientées nord, dans les secteurs ayant résisté à l'humidification (au-delà de 2400/2500 m secteur Orlu/Est, Beys/Bésines). Des accumulations en neige sèche sont encore susceptibles de reposer sur du givre de surface ou de la neige roulée. Cassures de 30/40 cm localement possibles, mais avalanches difficiles à déclencher. En deçà de cette altitude, l'humidification a gagné une bonne partie des pentes, le risque de départ diminue significativement.
Les secteurs les plus froids avec configuration particulière (goulet, verrous) peuvent éventuellement conserver un risque de déclenchement de plaques dans les pentes très raides.
(Observables : traces d'avalanches récentes, fissures sous les skis, affaissement accompagné de 'whoomf', signes de transport par le vent).

Départs spontanés :
Avalanches de fond de taille petite ou moyenne possible dès la matinée, y compris en versant nord. Quelques coulées ponctuelles en neige humide dans les pentes ou couloirs raides en dessous de 2100/2200 m.
En effet, le regel s'annonce incertain en dessous de cette altitude en raison de la couche nuageuse de la fin de nuit.
Une humidification un peu plus prononcée et profonde que les journées précédentes est attendue en journée dans les versants nord de moyenne montagne.
(Observables : neige très humide, gorgée d'eau; enfoncement important)

Qualité de la neige

Enneigement :
Malgré le redoux de ces derniers jours, l'enneigement reste excellent pour la saison, après plusieurs hivers déficitaires.
Fonte conséquente au soleil et en moyenne montagne depuis lundi après-midi et à fortiori mardi.

Limites skiables :
On peut encore envisager de chausser les skis vers 1300/1400 m dans les meilleures configurations en versants nord, plus surement au-dessus de 1500m en versants froids, 1800/1900m en versants sud.

État de la neige :
Neige souvent dure et regelée en matinée au-delà de 2100/2200 m. Regel incertain en dessous de cette altitude avec les nuages plus nombreux.
Dans l'après-midi, humidification moins prononcée que les jours précédents en versants ensoleillés, neige de printemps meuble dans tous les versants en dessous de 2300/2400 m. Quelques combes de poudreuses résistent au-delà de 2500 m.

Aperçu météo pour le jeudi 19 mars

	nuit	matin	après-midi	soir
	Nuageux à couvent en matinée, rares ondées.			
Pluie-Neige				
Iso 0 °C	2 900 m	2 400 m	2 300 m	2 400 m
Vent 2000 m	↑ 25 km/h	↑ 20 km/h	↖ 15 km/h	↗ 10 km/h
Vent 3000 m	↘ 40 km/h	↘ 20 km/h	← 10 km/h	↙ 15 km/h

Pour consulter la vigilance en cours, veuillez vous rendre sur le site https://vigilance.meteofrance.fr/fr

Météo-France - 73 avenue de Paris, 94165 Saint-Mandé cedex - Contact : contact@meteo.fr

Rédigé par Météo-France avec la contribution des observateurs du réseau nivo-météorologiques. Partenariat : ANMSM (Maires de Stations de Montagne), DSF (Domaines Skiables de France), ADSP (Directeurs de Pistes et de la Sécurité des Stations de Sports d'Hiver) et autres acteurs de la montagne.

Bulletin neige & avalanches par téléphone au
0 892 68 10 20 Service 0,35 € / min + prix appel

Bulletin d'estimation du risque d'avalanche

(valable en dehors des pistes balisées et ouvertes)

MASSIF : Orlu St-Barthelemy

Rédigé le mercredi 18 mars 2026 à 15h

Épaisseur de neige hors-piste

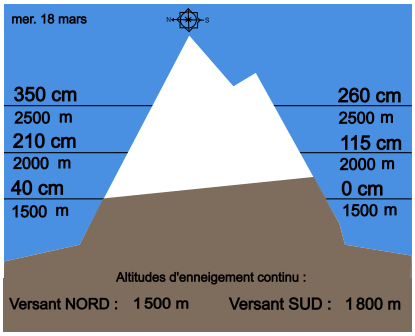

Précipitations à 1800 m

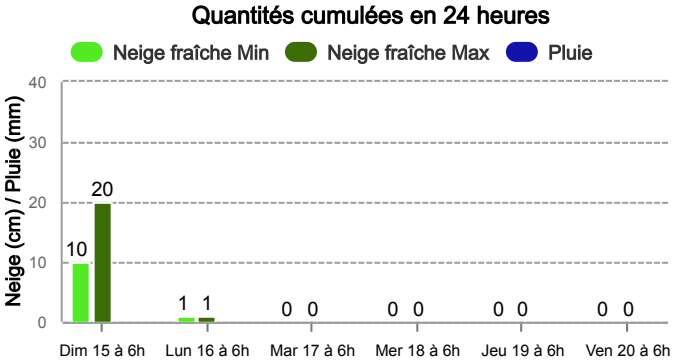

Tendance du vendredi 20 mars

Indice de risque limité

Stationnaires, voire en légère baisse le matin.

Pour consulter la vigilance en cours, veuillez vous rendre sur le site https://vigilance.meteofrance.fr/fr

Météo-France - 73 avenue de Paris, 94165 Saint-Mandé cedex - Contact : contact@meteo.fr

Rédigé par Météo-France avec la contribution des observateurs du réseau nivo-météorologiques. Partenariat : ANMSM (Maires de Stations de Montagne), DSF (Domaines Skiables de France), ADSP (Directeurs de Pistes et de la Sécurité des Stations de Sports d'Hiver) et autres acteurs de la montagne.

Bulletin neige & avalanches par téléphone au

0 892 68 10 20 Service 0,35 € / min + prix appel

RÉPUBLIQUE FRANÇAISE
Liberté Égalité Fraternité

METEO FRANCE
À VOS CÔTÉS, DANS UN CLIMAT QUI CHANGE

Bulletin d'estimation du risque d'avalanche

(valable en dehors des pistes balisées et ouvertes)

MASSIF : Orlu St-Barthelemy

Rédigé le mercredi 18 mars 2026 à 15h

Conditions nivo-météo des 7 derniers jours

	jeu. 12/03				ven. 13/03				sam. 14/03				dim. 15/03				lun. 16/03				mar. 17/03				mer. 18/03			
	03h	09h	15h	21h	03h	09h	15h	21h	03h	09h	15h	21h	03h	09h	15h	21h	03h	09h	15h	21h	03h	09h	15h	21h	03h	09h	15h	21h
Météo																												
Vent (km/h)	40	30	25	25	25	25	30	40	50	50	55	70	95	95	75	50	40	30	30	20	25	15	15	15	15	15	20	30
à 3000m																												
Vent (km/h)	30	20	15	15	15	15	15	25	30	30	35	45	60	60	50	30	25	20	20	10	15	10	10	10	10	10	10	15
à 2000m																												

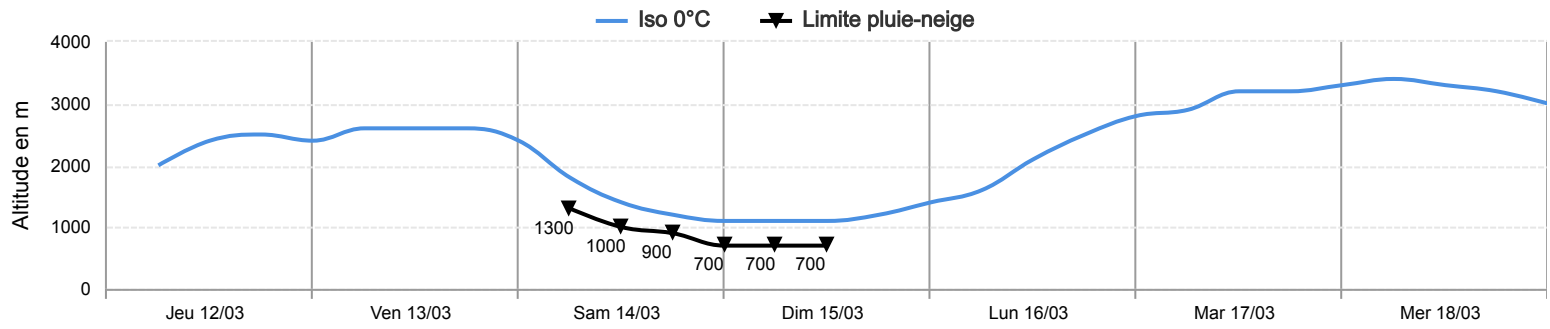

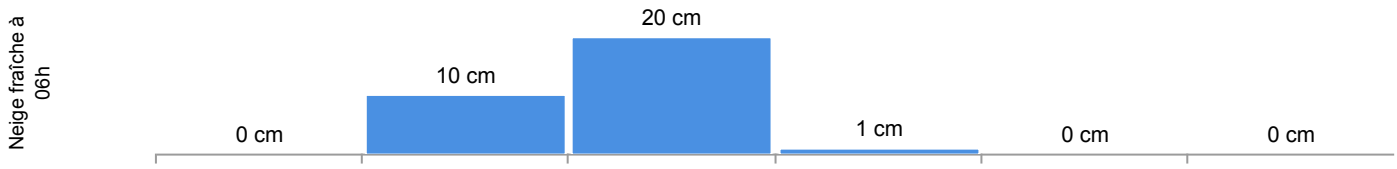

Risque d'avalanche	jeu. 12/03	ven. 13/03	sam. 14/03	dim. 15/03	lun. 16/03	mar. 17/03	mer. 18/03
	2	2	3	3	3	3	3

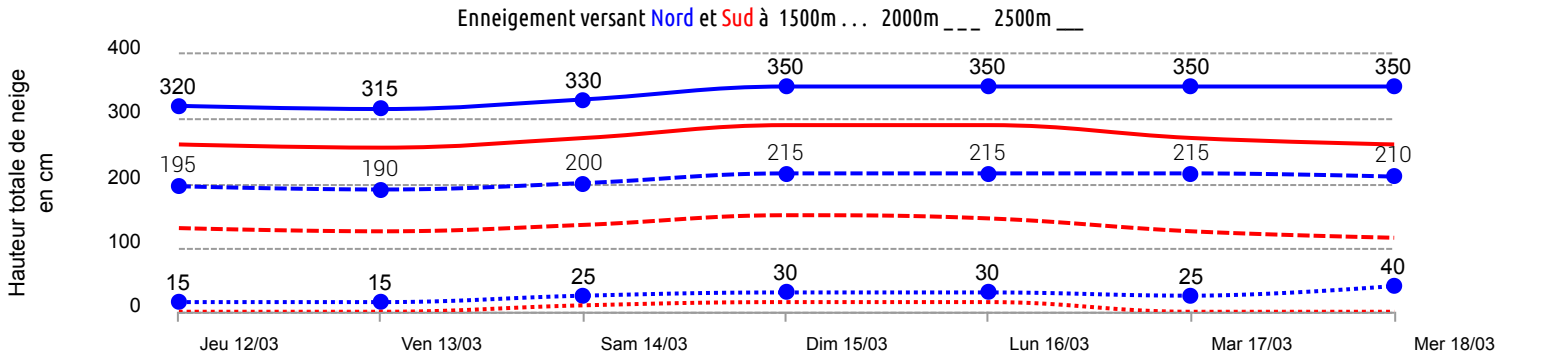

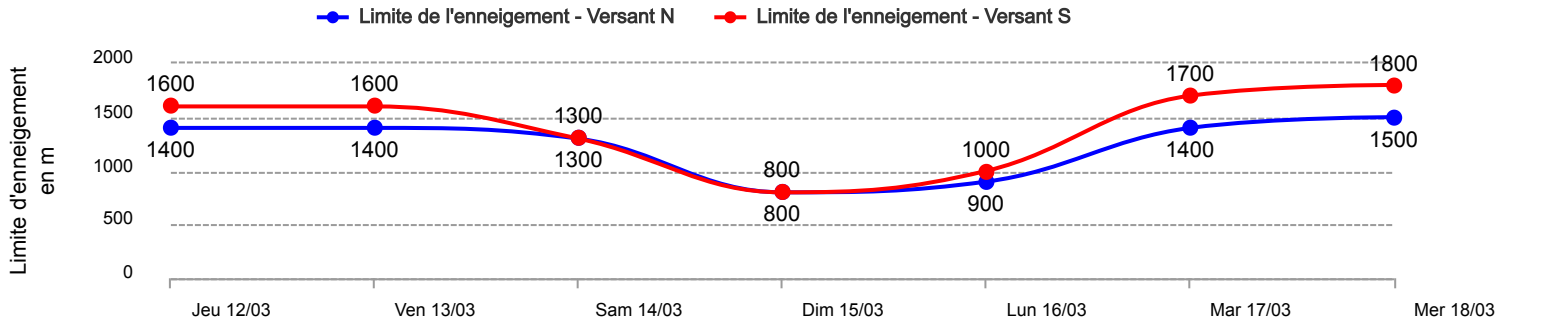

Pour consulter la vigilance en cours, veuillez vous rendre sur le site https://vigilance.meteofrance.fr/fr

Météo-France - 73 avenue de Paris, 94165 Saint-Mandé cedex - Contact : contact@meteo.fr

Rédigé par Météo-France avec la contribution des observateurs du réseau nivo-météorologiques. Partenariat : ANMSM (Maires de Stations de Montagne), DSF (Domaines Skiables de France), ADSP (Directeurs de Pistes et de la Sécurité des Stations de Sports d'Hiver) et autres acteurs de la montagne.

Bulletin neige & avalanches par téléphone au

0 892 68 10 20 Service 0,35 € / min + prix appel