Bulletin d'estimation du risque d'avalanche
(valable en dehors des pistes balisées et ouvertes)

MASSIF : Chartreuse

Rédigé le mercredi 18 mars 2026 à 16h

Estimation des risques pour le : JEUDI 19 MARS

RARES INSTABILITÉS EN VERSANT FROID.

2

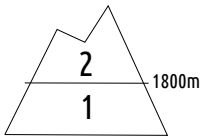

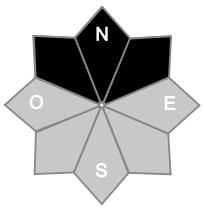

Au-dessus de 1800m indice de risque limité, plus bas indice faible.

Départs spontanés : Rares coulées au soleil.

Déclenchements provoqués : Rares plaques de neige soufflée dans les versants ombragés.

Indices de risque : 5 très fort - 4 fort - 3 marqué - 2 limité - 1 faible -- En noir : les pentes les plus dangereuses

Stabilité du manteau neigeux

Situation avalancheuse typique : neige ventée

Déclenchements provoqués : Le manteau neigeux s'est bien consolidé depuis les dernières chutes de neige. Le risque de déclenchement se limite à de rares avalanches de plaque formées par le vent de nord, peu épaisses et situées surtout près des crêtes des versants ombragés.

Départs spontanés : Après un bon regel nocturne, l'humidification du manteau neigeux reprend grâce au soleil. Ponctuellement, une avalanche de neige lourde (taille 1 à 2) reste possible jeudi dans une pente surchauffée qui n'aurait pas déjà purgé depuis les dernières chutes de neige.

Qualité de la neige

Qualification de l'enneigement : L'enneigement est bon pour la saison en versants ombragés au dessus de 1300 m. Il est correct en Sud mais les sous-couches sont rares sous 1700/1800 m.
Limites skiables : Vers 1200/1700 m selon les versants.
Qualité de la neige jeudi : Neige croûtée, s'humidifiant en journée dans les versants au soleil. Neige dense, parfois travaillée par le vent dans les ubacs.

Aperçu météo pour le jeudi 19 mars

	nuit	matin	après-midi	soir
Pluie-Neige				
Iso 0 °C	2 000 m	2 100 m	2 100 m	2 100 m
Vent 1500 m	10 km/h	15 km/h	15 km/h	10 km/h
Vent 2000 m	35 km/h	25 km/h	20 km/h	20 km/h

Épaisseur de neige hors-piste

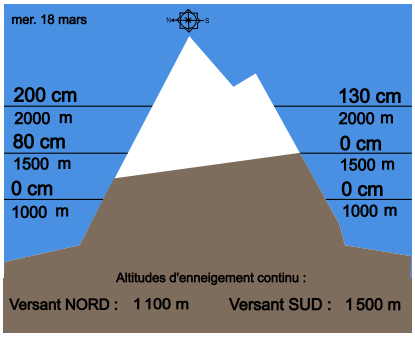

Précipitations à 1800 m

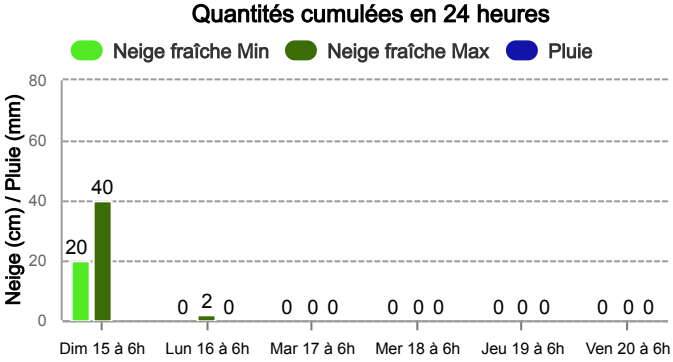

Tendance du vendredi 20 mars

2

Indice de risque limité

Reprise de l'humidification en journée de vendredi. Risques stationnaires.

Pour consulter la vigilance en cours, veuillez vous rendre sur le site https://vigilance.meteofrance.fr/fr

Météo-France - 73 avenue de Paris, 94165 Saint-Mandé cedex - Contact : contact@meteo.fr

Rédigé par Météo-France avec la contribution des observateurs du réseau nivo-météorologiques. Partenariat : ANMSM (Maires de Stations de Montagne), DSF (Domaines Skiables de France), ADSP (Directeurs de Pistes et de la Sécurité des Stations de Sports d'Hiver) et autres acteurs de la montagne.

Bulletin neige & avalanches par téléphone au
0 892 68 10 20 Service 0,35 € / min + prix appel

RÉPUBLIQUE FRANÇAISE
Liberté Égalité Fraternité

METEO FRANCE
À VOS CÔTÉS, DANS UN CLIMAT QUI CHANGE

Bulletin d'estimation du risque d'avalanche
(valable en dehors des pistes balisées et ouvertes)
MASSIF : Chartreuse

Rédigé le mercredi 18 mars 2026 à 16h

Conditions nivo-météo des 7 derniers jours

	jeu. 12/03				ven. 13/03				sam. 14/03				dim. 15/03				lun. 16/03				mar. 17/03				mer. 18/03			
	03h	09h	15h	21h	03h	09h	15h	21h	03h	09h	15h	21h	03h	09h	15h	21h	03h	09h	15h	21h	03h	09h	15h	21h	03h	09h	15h	21h
Météo																												
Vent (km/h)	45	30	20	10	20	25	40	55	70	40	40	65	80	65	50	45	50	45	40	35	35	35	35	25	25	25	35	40
à 2000m																												
Vent (km/h)	25	20	15	5	10	15	30	40	45	20	25	50	70	45	40	25	35	30	25	20	15	15	10	10	10	15	15	10
à 1500m																												

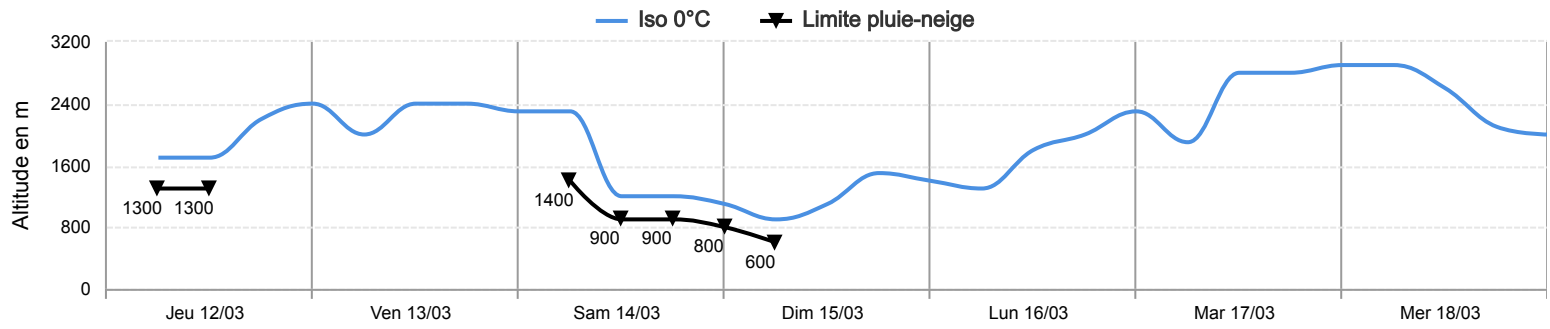

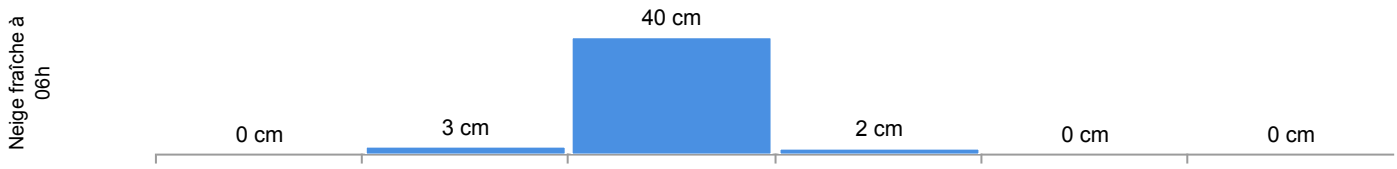

Risque d'avalanche	jeu. 12/03	ven. 13/03	sam. 14/03	dim. 15/03	lun. 16/03	mar. 17/03	mer. 18/03
	2	2	3	3	3	2	2

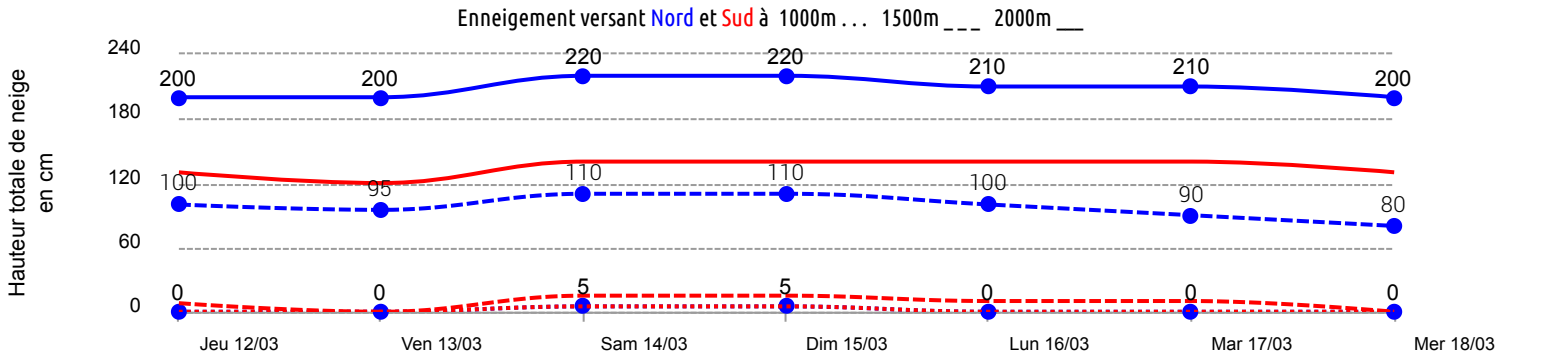

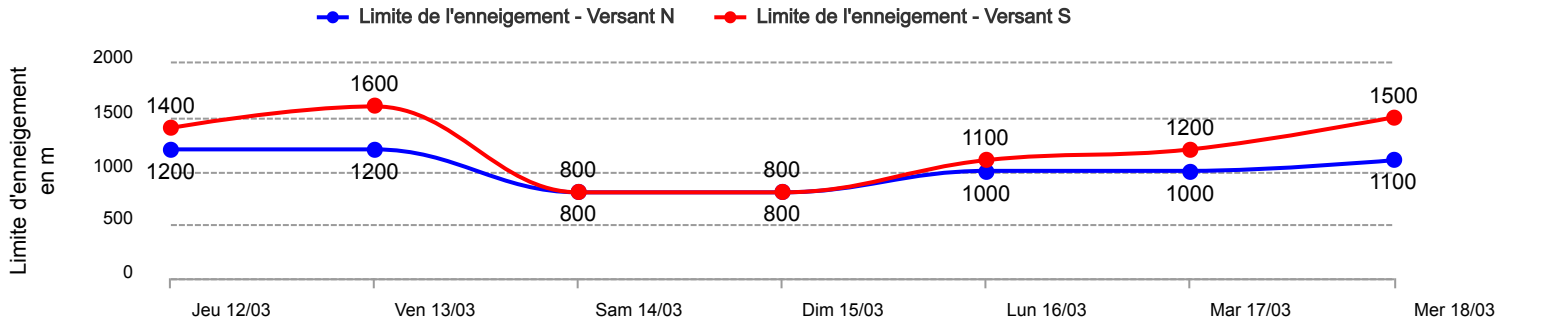

Pour consulter la vigilance en cours, veuillez vous rendre sur le site https://vigilance.meteofrance.fr/fr

Météo-France - 73 avenue de Paris, 94165 Saint-Mandé cedex - Contact : contact@meteo.fr

Bulletin neige & avalanches par téléphone au **0 892 68 10 20** Service 0,35 € / min + prix appel

Rédigé par Météo-France avec la contribution des observateurs du réseau nivo-météorologiques. Partenariat : ANMSM (Maires de Stations de Montagne), DSF (Domaines Skiables de France), ADSP (Directeurs de Pistes et de la Sécurité des Stations de Sports d'Hiver) et autres acteurs de la montagne.