Bulletin d'estimation du risque d'avalanche
(valable en dehors des pistes balisées et ouvertes)

MASSIF : Haut-Var Haut-Verdon

Rédigé le mercredi 18 mars 2026 à 16h

Estimation des risques pour le : JEUDI 19 MARS

DES INSTABILITÉS DANS LES ACCUMULATIONS DE NEIGE VENTÉE

3

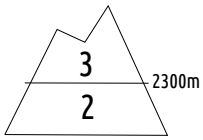

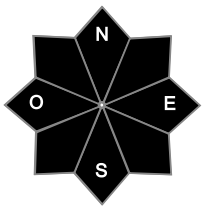

Au-dessus de 2300m indice de risque marqué, plus bas indice limité.

Départs spontanés : quelques départs de neige humide, de faible ampleur.

Déclenchements provoqués : plaques faciles à déclencher dans la neige ventée.

Indices de risque : 5 très fort - 4 fort - 3 marqué - 2 limité - 1 faible -- En noir : les pentes les plus dangereuses

Stabilité du manteau neigeux

Situation avalancheuse typique : neige ventée

Déclenchements provoqués : des plaques sont en place en altitude, plus fréquentes au-dessus de 2300 m, suite au transport de neige par le vent observé ce mercredi. Ces plaques peuvent céder au passage d'un skieur et sont présentes dans les zones d'accumulations, en contrebas ou derrière des crêtes, les ruptures de pente ou les bosses. Ces instabilités se trouvent plus fréquemment dans les ubacs où le manteau neigeux n'est pas printanier, mais quelques plaques se sont aussi formées derrière les crêtes en adrets, avec la neige rapportée depuis les versants ombragés.
Avalanches souvent moyennes (taille 2), une rare grande (taille 3) non exclue en cas de rupture sur la couche fragile persistante enfouie (suite au départ d'une première plaque de surface par exemple).

Départs spontanés : l'activité en neige humide reste limitée, mais quelques départs sont attendus dans les pentes raides bien ensoleillées. Avalanches petites en général, plus rarement moyennes (taille 1 voire 2).

Qualité de la neige

Enneigement plutôt excédentaire dans le Haut-Verdon, proche des normales dans le Haut Var.
Hauteurs de neige observées : vers 2000 m, 180 cm dans un fond de vallon du Haut-Verdon, 120 cm dans le Haut Var.

Enneigement skiable : vers 1400/1500 m en ubacs, 1700/1800 m en adrets peu pentus.

État de la neige en surface : manteau neigeux printanier dans les adrets, croûté en début de matinée, s'humidifiant au soleil en cours de journée. Des accumulations de neige rapportée par le vent en altitude.
Dans les ubacs, la neige reste froide au-dessus de 2000 m environ, encore assez légère dans les combes ou forêts d'altitude abritées, mais souvent très travaillée ou durcie par le vent dans les secteurs exposés.

Aperçu météo pour le jeudi 19 mars

nuit	matin	après-midi	soir

Temps bien ensoleillé. Rares cumulus l'après-midi. Le vent de nord-est faiblit progressivement.

Pluie-Neige				
Iso 0 °C	1 500 m	1 800 m	2 200 m	2 000 m
Vent 2000 m	45 km/h	30 km/h	20 km/h	15 km/h
Vent 3000 m	65 km/h	50 km/h	30 km/h	30 km/h

Épaisseur de neige hors-piste

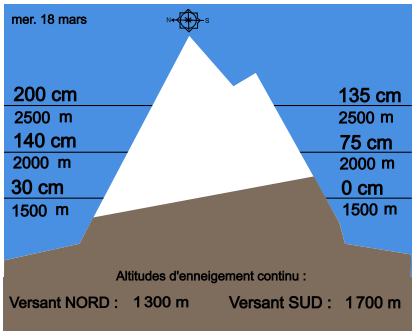

Précipitations à 1800 m

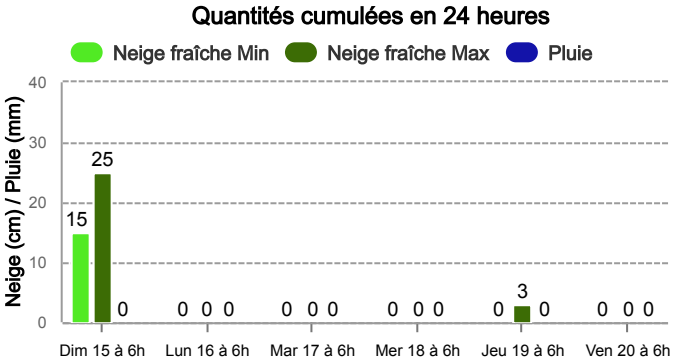

Tendance du vendredi 20 mars

2

Indice de risque limité

Stabilisation progressive du manteau neigeux. Encore quelques plaques résiduelles, mais plus difficiles à déclencher. L'activité en neige humide au soleil reste limitée.

Pour consulter la vigilance en cours, veuillez vous rendre sur le site https://vigilance.meteofrance.fr/fr

Météo-France - 73 avenue de Paris, 94165 Saint-Mandé cedex - Contact : contact@meteo.fr

Rédigé par Météo-France avec la contribution des observateurs du réseau nivo-météorologiques. Partenariat : ANMSM (Maires de Stations de Montagne), DSF (Domaines Skiables de France), ADSP (Directeurs de Pistes et de la Sécurité des Stations de Sports d'Hiver) et autres acteurs de la montagne.

Bulletin neige & avalanches par téléphone au 0 892 68 10 20 Service 0,35 € / min + prix appel

Bulletin d'estimation du risque d'avalanche

(valable en dehors des pistes balisées et ouvertes)

MASSIF : Haut-Var Haut-Verdon

Rédigé le mercredi 18 mars 2026 à 16h

Conditions nivo-météo des 7 derniers jours

	jeu. 12/03				ven. 13/03				sam. 14/03				dim. 15/03				lun. 16/03				mar. 17/03				mer. 18/03			
	03h	09h	15h	21h	03h	09h	15h	21h	03h	09h	15h	21h	03h	09h	15h	21h	03h	09h	15h	21h	03h	09h	15h	21h	03h	09h	15h	21h
Météo																												
Vent (km/h)	40	30	20	20	20	10	15	15	40	50	30	20	60	75	45	35	55	40	35	30	20	15	20	25	20	50	80	80
à 3000m																												
Vent (km/h)	25	25	20	10	10	5	15	10	15	25	20	15	20	55	25	15	20	20	25	15	10	10	15	10	10	25	50	50
à 2000m																												

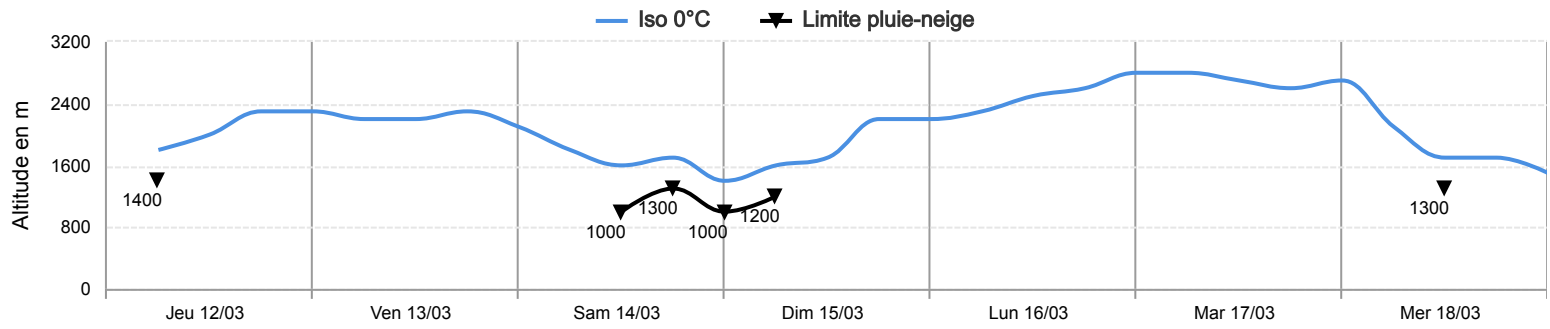

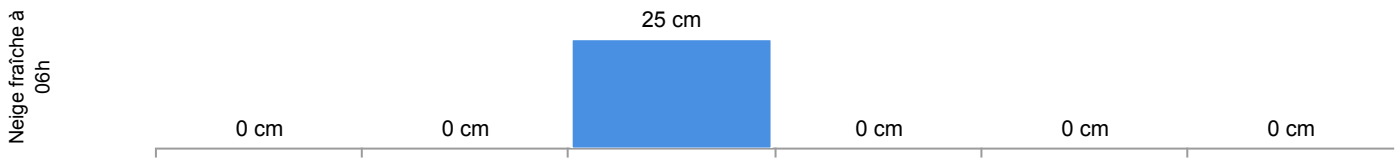

Risque d'avalanche	jeu. 12/03	ven. 13/03	sam. 14/03	dim. 15/03	lun. 16/03	mar. 17/03	mer. 18/03
	2	2	3	3	3	2	3

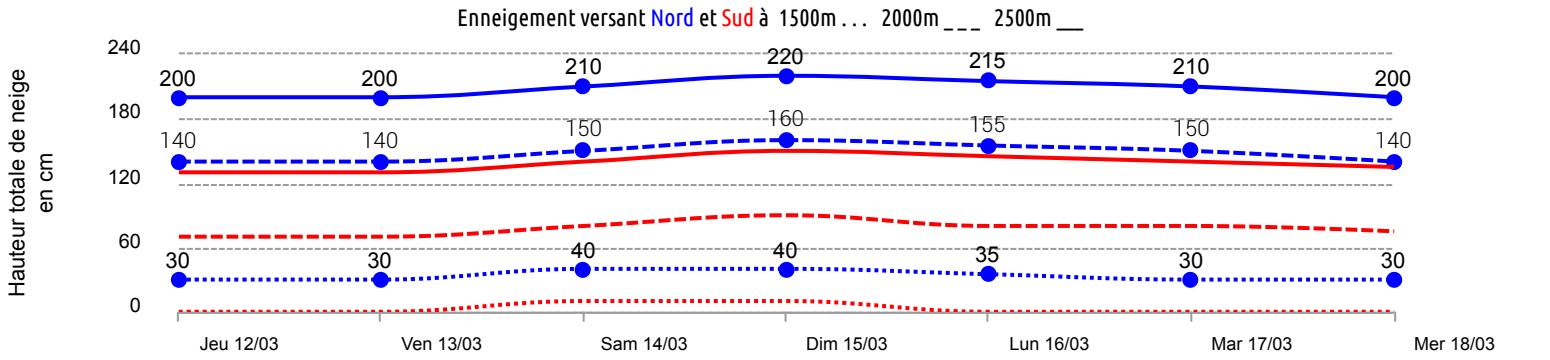

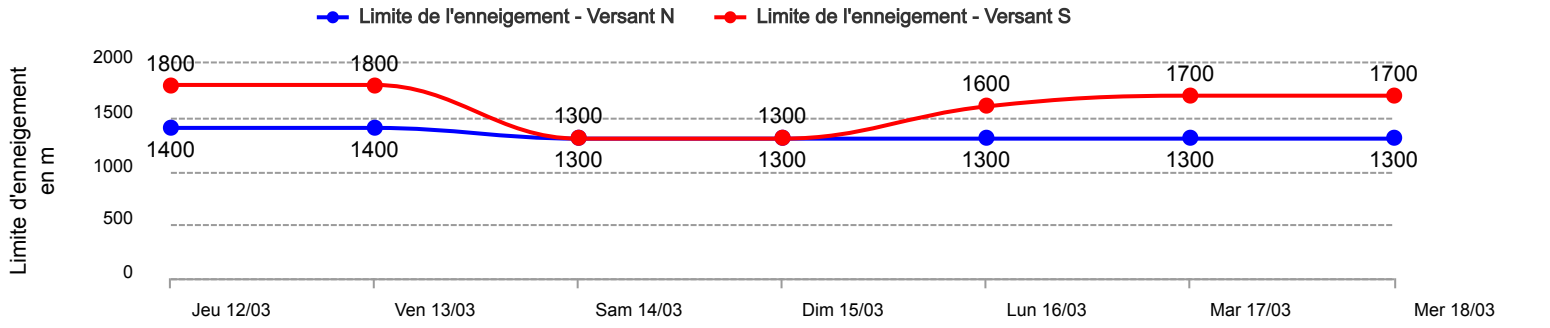

Pour consulter la vigilance en cours, veuillez vous rendre sur le site https://vigilance.meteofrance.fr/fr

Météo-France - 73 avenue de Paris, 94165 Saint-Mandé cedex - Contact : contact@meteo.fr

Bulletin neige & avalanches par téléphone au

0 892 68 10 20 Service 0,35 € / min + prix appel

Rédigé par Météo-France avec la contribution des observateurs du réseau nivo-météorologiques. Partenariat : ANMSM (Maires de Stations de Montagne), DSF (Domaines Skiables de France), ADSP (Directeurs de Pistes et de la Sécurité des Stations de Sports d'Hiver) et autres acteurs de la montagne.