Bulletin d'estimation du risque d'avalanche

(valable en dehors des pistes balisées et ouvertes)

MASSIF : Haute-Bigorre

Rédigé le mercredi 18 mars 2026 à 16h

Estimation des risques pour le : JEUDI 19 MARS

QUELQUES PLAQUES EN ALTITUDE AU-DESSUS DE 2300M, HUMIDIFICATION AILLEURS.

2

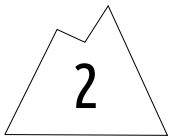

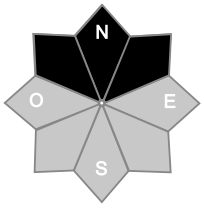

Plaques en altitude.

Indices de risque : 5 très fort - 4 fort - 3 marqué - 2 limité - 1 faible -- En noir : les pentes les plus dangereuses

Indice de risque limité.

Départs spontanés : En neige humide, avalanches de fond possibles.

Déclenchements provoqués : Quelques plaques au-dessus de 2300m.

Stabilité du manteau neigeux

Situation avalancheuse typique : neige ventée neige humide

Déclenchements provoqués :
- **Au-dessus de 2300m**, dans les pentes raides allant du Nord-Ouest vers le Nord-Est, quelques plaques à vent sont encore présentes. Elles restent facilement déclenchables par un simple skieur et peuvent être parfois difficiles à identifier avec les faibles chutes de neige de ce jeudi. Leur sollicitation peut engendrer des cassures linéaires petites à moyennes (taille 1 à 2), parfois encore des grandes (taille 3) surtout dans les zones d'accumulation les plus importantes. Ces plaques peuvent reposer sur des couches fragiles peu enfouies, sensibles à la moindre surcharge.
- **Ailleurs**, un regel efficace devrait réduire le risque avalancheux au petit matin. Puis, un skieur peut déclencher par forte sollicitation des avalanches dans la neige s'humidifiant en toutes orientations au fil de la journée. Des avalanches petites à moyennes sont possibles (taille 1 à 2), rarement grandes (taille 3).

Départs spontanés :
- **Au-dessus de 2300m**, des départs ponctuels de plaques décrites ci-dessus restent possibles, par surcharge par le vent, engendrant généralement des avalanches petites à moyennes (taille 1 à 2), plus rarement des grandes (taille 3) dans les zones d'accumulations plus importantes.
- **Ailleurs**, des départs ponctuels dans la neige humide sont attendus dans les pentes raides en toutes orientations et au fil de la journée. Un regel efficace devrait limiter cette activité avalancheuse tôt le matin. Les avalanches sont généralement petites à moyennes (taille 1 à 2), rarement grandes (taille 3) surtout dans les combes ou zones d'accumulation plus conséquentes. Des avalanches de fond restent aussi possibles dans les pentes raides des versants au fil de la journée, engendrant des avalanches moyennes à parfois grandes (taille 2 à 3).

Autres : Pont de neige et corniches encore en place fragilisés.

Qualité de la neige

Enneigement : Correct pour la saison, surtout au-dessus de 1800 m, mais reste assez maigre en versants exposés au vent d'ouest. Il débute assez bas, mais n'est skiable qu'à partir de 1600m en nord, plutôt 1800 en sud, faute de sous-couche.
État de la neige : Au petit matin, la neige reste encore sèche au-dessus de 2300m dans les pentes Nord-Ouest à Nord-Est. Elle est regelée plus bas et partout ailleurs. En journée, une fine couche de neige peut venir se déposer sur le manteau neigeux au-dessus de 1800m. Sinon, la neige reste bien ramollie et lourde sous 2300m, elle poursuit son humidification. Elle reste sèche en secteurs Nord au-dessus de 2300m environ, bien travaillée par le vent dans les pentes raides.

Aperçu météo pour le jeudi 19 mars

	nuit	matin	après-midi	soir

Belles éclaircies le matin. Ciel un peu plus couvert ensuite, faibles averses attendues. Ciel dégagé la nuit suivante. Vent faible à parfois modéré.

	nuit	matin	après-midi	soir
Pluie-Neige	1 900 m		1 800 m	
Iso 0 °C	2 800 m	2 500 m	2 300 m	2 500 m
Vent 2000 m	15 km/h	15 km/h	15 km/h	10 km/h
Vent 3000 m	25 km/h	25 km/h	20 km/h	15 km/h

Épaisseur de neige hors-piste

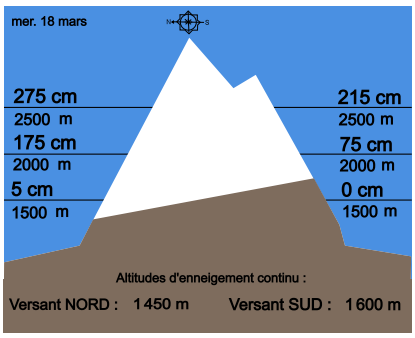

Précipitations à 1800 m

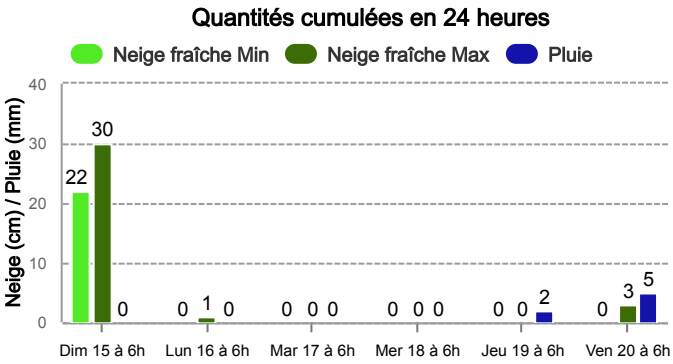

Tendance du vendredi 20 mars

2

Indice de risque limité

Risque stationnaire. Poursuite de l'humidification du manteau neigeux avec de belles éclaircies, rares averses possibles l'après-midi. Plaques en altitude.

Pour consulter la vigilance en cours, veuillez vous rendre sur le site https://vigilance.meteofrance.fr/fr

Météo-France - 73 avenue de Paris, 94165 Saint-Mandé cedex - Contact : contact@meteo.fr

Rédigé par Météo-France avec la contribution des observateurs du réseau nivo-météorologiques. Partenariat : ANMSM (Maires de Stations de Montagne), DSF (Domaines Skiables de France), ADSP (Directeurs de Pistes et de la Sécurité des Stations de Sports d'Hiver) et autres acteurs de la montagne.

Bulletin neige & avalanches par téléphone au 0 892 68 10 20 Service 0,35 € / min + prix appel

RÉPUBLIQUE FRANÇAISE
Liberté Égalité Fraternité

METEO FRANCE
À VOS CÔTÉS, DANS UN CLIMAT QUI CHANGE

Bulletin d'estimation du risque d'avalanche

(valable en dehors des pistes balisées et ouvertes)

MASSIF : Haute-Bigorre

Rédigé le mercredi 18 mars 2026 à 16h

Conditions nivo-météo des 7 derniers jours

	jeu. 12/03				ven. 13/03				sam. 14/03				dim. 15/03				lun. 16/03				mar. 17/03				mer. 18/03			
	03h	09h	15h	21h	03h	09h	15h	21h	03h	09h	15h	21h	03h	09h	15h	21h	03h	09h	15h	21h	03h	09h	15h	21h	03h	09h	15h	21h
Météo																												
Vent (km/h)	40	30	55	60	35	60	60	50	55	60	80	95	95	90	85	60	60	45	40	30	25	20	15	15	15	10	15	25
à 3000m																												
Vent (km/h)	5	10	10	5	15	20	20	25	15	30	35	65	70	65	40	20	20	15	5	10	10	10	10	10	5	2	5	10
à 2000m																												

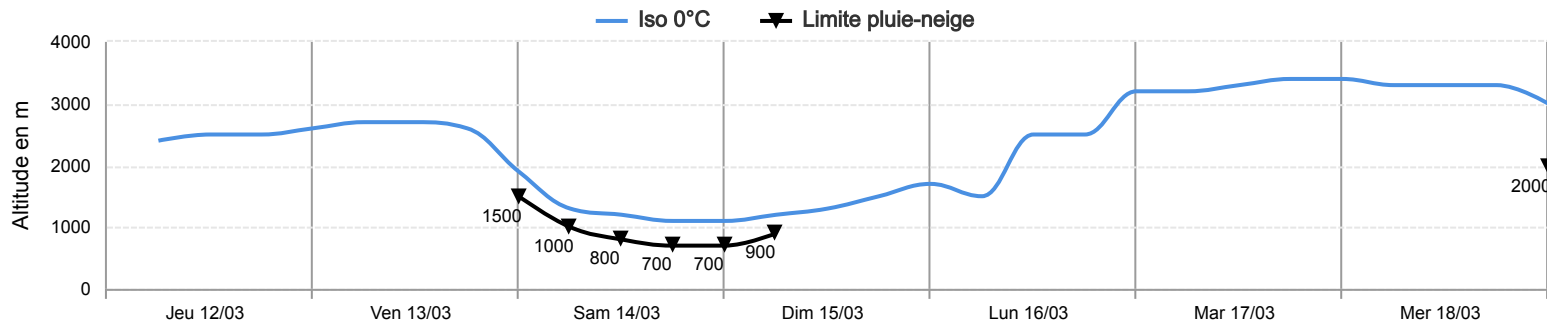

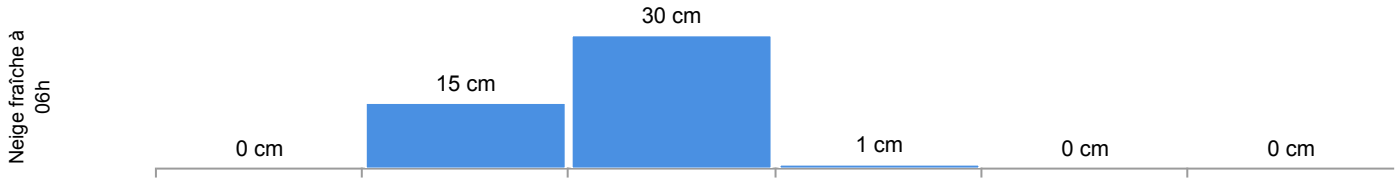

Risque d'avalanche	jeu. 12/03	ven. 13/03	sam. 14/03	dim. 15/03	lun. 16/03	mar. 17/03	mer. 18/03
	2	2	3	3	3	3	3

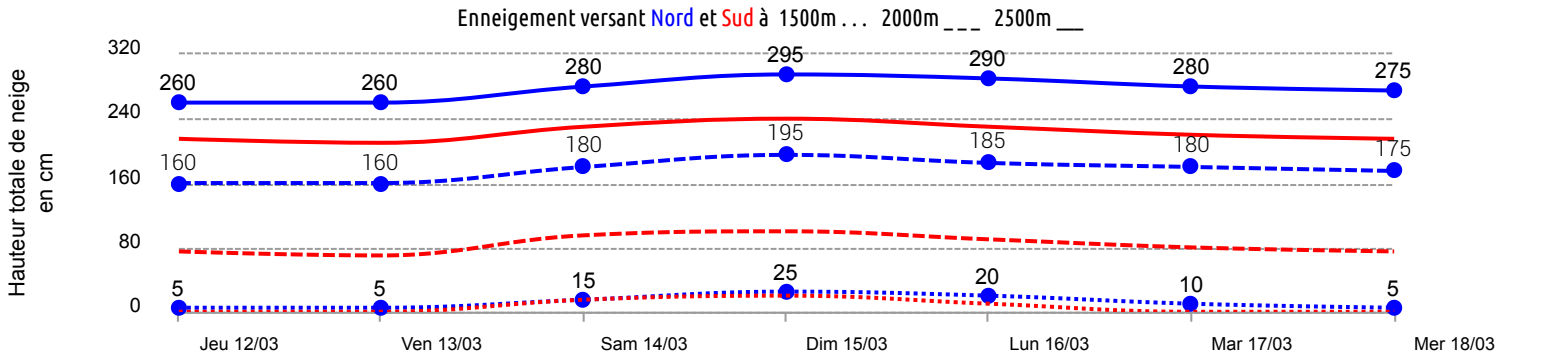

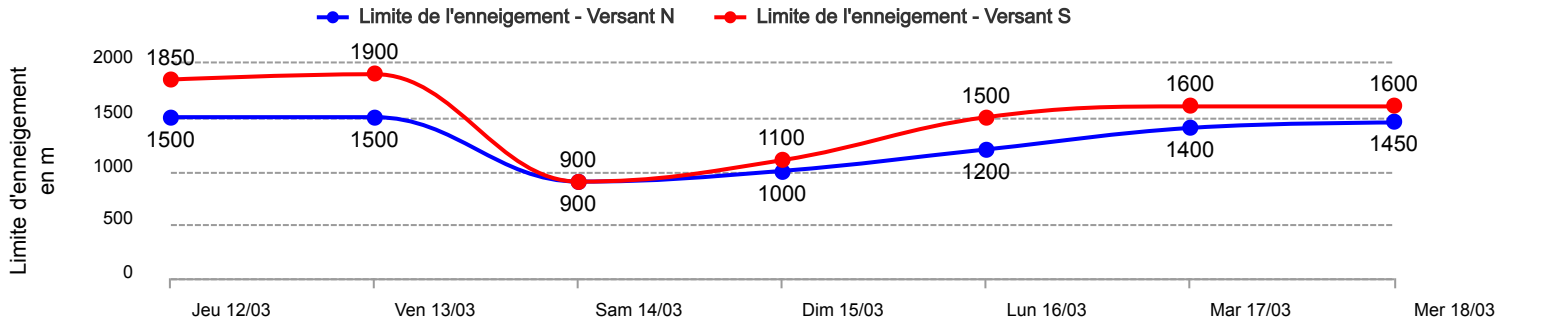

Pour consulter la vigilance en cours, veuillez vous rendre sur le site https://vigilance.meteofrance.fr/fr

Météo-France - 73 avenue de Paris, 94165 Saint-Mandé cedex - Contact : contact@meteo.fr

Bulletin neige & avalanches par téléphone au

0 892 68 10 20 Service 0,35 € / min + prix appel

Rédigé par Météo-France avec la contribution des observateurs du réseau nivo-météorologiques. Partenariat : ANMSM (Maires de Stations de Montagne), DSF (Domaines Skiables de France), ADSP (Directeurs de Pistes et de la Sécurité des Stations de Sports d'Hiver) et autres acteurs de la montagne.