Bulletin d'estimation du risque d'avalanche

(valable en dehors des pistes balisées et ouvertes)

MASSIF : Mercantour

Rédigé le mercredi 18 mars 2026 à 16h

Estimation des risques pour le : JEUDI 19 MARS

DES INSTABILITÉS DANS LES ACCUMULATIONS DE NEIGE RÉCENTE / VENTÉE

3

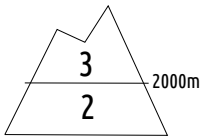

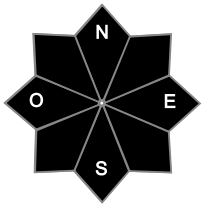

Au-dessus de 2000m indice de risque marqué, plus bas indice limité.

Départs spontanés : quelques avalanches de neige récente / humide au soleil, petites à moyennes --- Plaques suite au transport de neige par le vent.

Déclenchements provoqués : plaques faciles à déclencher dans la neige récente et/ou ventée.

Indices de risque : 5 très fort - 4 fort - 3 marqué - 2 limité - 1 faible -- En noir : les pentes les plus dangereuses

Stabilité du manteau neigeux

Situation avalancheuse typique : neige ventée neige humide

Déclenchements provoqués : des plaques sont en place, en particulier au-dessus de 2000 m, suite aux récentes petites chutes de neige et/ou au fort transport engendré par le vent de nord à nord-est. Ces plaques sont faciles à déclencher et assez fréquentes en contrebas ou derrière les crêtes, les ruptures de pente ou les bosses. Elles se trouvent dans les zones d'accumulations, et plus fréquemment dans les ubacs où le manteau neigeux n'est pas printanier, mais aussi derrière les crêtes en adrets, avec la neige rapportée depuis les versants ombragés.
Sur le chaînon frontalier, et notamment en Vésubie/Roya (là où il neige le plus), pas d'orientation privilégiée.
Avalanches souvent moyennes (taille 2), une rare grande (taille 3) non exclue en cas de sollicitation de la couche fragile persistante enfouie (suite au départ d'une plaque de surface par exemple).

Départs spontanés : * Sur le chaînon frontalier (surtout Vésubie/Roya), avalanches de neige récente humidifiée au soleil, petites à moyennes (taille 1 à 2). Sur le reste du massif, l'activité en neige humide reste limitée, mais quelques départs sont attendus dans les pentes raides bien ensoleillées. Avalanches petites en général, plus rarement moyennes (taille 1 voire 2).
* Quelques départs de plaques, suite au transport de neige par le vent qui se poursuit notamment le matin.

Qualité de la neige

Enneigement excédentaire dans la Roya, proche des normales sur le reste du massif.
Données observées : 160 cm à la Nivôse de Millefonts à 2430 m, 115 cm à Isola 2000 à 1912 m.

Enneigement skiable : vers 1400 m en ubacs, 1700/1800 m en adrets peu pentus.

État de la neige en surface : * Chaînon frontalier : manteau hétérogène avec un peu de neige fraîche souvent très travaillée par le vent qui côtoie des surfaces durcies/croutées ou décapées. En cours de journée, humidification au soleil.
*Reste du massif : manteau neigeux printanier dans les adrets, croûté en début de matinée, s'humidifiant au soleil en cours de journée. Dans les ubacs, la neige reste froide au-dessus de 2000 m environ, encore assez légère dans les combes ou forêts d'altitude abritées, mais souvent très travaillée ou durcie par le vent dans les secteurs exposés.

Aperçu météo pour le jeudi 19 mars

	nuit	matin	après-midi	soir

Retour d'un temps sec et ensoleillé en cours de matinée, après les petites chutes de neige de la nuit en secteur frontalier (3 à 5 cm, jusqu'à 10/15 cm en Vésubie/Roya) . Le vent de nord à nord-est reste bien établi, mais faiblit progressivement.

Pluie-Neige	1 000 m			
Iso 0 °C	1 300 m	1 400 m	1 800 m	1 900 m
Vent 2000 m	↓ 70 km/h	↓ 50 km/h	↓ 35 km/h	↙ 30 km/h
Vent 3000 m	↙ 80 km/h	↙ 60 km/h	↙ 50 km/h	↓ 35 km/h

Épaisseur de neige hors-piste

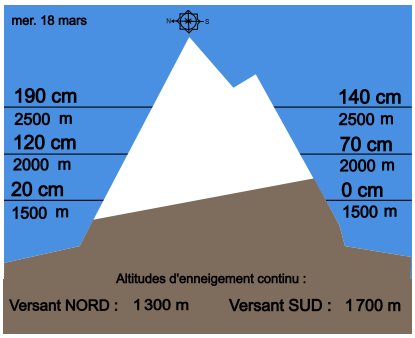

Précipitations à 1800 m

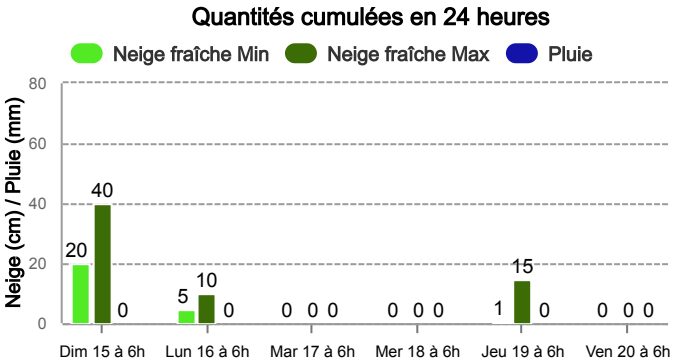

Tendance du vendredi 20 mars

Indice de risque limité

Stabilisation progressive du manteau neigeux. Encore quelques plaques, notamment sur le chaînon frontalier. L'activité en neige humide au soleil reste limitée.

Pour consulter la vigilance en cours, veuillez vous rendre sur le site https://vigilance.meteofrance.fr/fr

Météo-France - 73 avenue de Paris, 94165 Saint-Mandé cedex - Contact : contact@meteo.fr

Rédigé par Météo-France avec la contribution des observateurs du réseau nivo-météorologiques. Partenariat : ANMSM (Maires de Stations de Montagne), DSF (Domaines Skiables de France), ADSP (Directeurs de Pistes et de la Sécurité des Stations de Sports d'Hiver) et autres acteurs de la montagne.

Bulletin neige & avalanches par téléphone au

0 892 68 10 20 Service 0,35 € / min + prix appel

RÉPUBLIQUE FRANÇAISE
Liberté Égalité Fraternité

METEO FRANCE
À VOS CÔTÉS, DANS UN CLIMAT QUI CHANGE

Bulletin d'estimation du risque d'avalanche
(valable en dehors des pistes balisées et ouvertes)

MASSIF : Mercantour

Rédigé le mercredi 18 mars 2026 à 16h

Conditions nivo-météo des 7 derniers jours

	jeu. 12/03				ven. 13/03				sam. 14/03				dim. 15/03				lun. 16/03				mar. 17/03				mer. 18/03			
	03h	09h	15h	21h	03h	09h	15h	21h	03h	09h	15h	21h	03h	09h	15h	21h	03h	09h	15h	21h	03h	09h	15h	21h	03h	09h	15h	21h
Météo																												
Vent (km/h)	40	40	40	30	25	20	30	25	60	55	40	25	60	80	50	35	45	40	35	30	20	15	20	20	20	65	90	95
à 3000m																												
Vent (km/h)	20	40	35	25	30	10	15	10	15	35	25	15	30	55	40	25	35	30	25	15	15	15	15	15	15	45	65	70
à 2000m																												

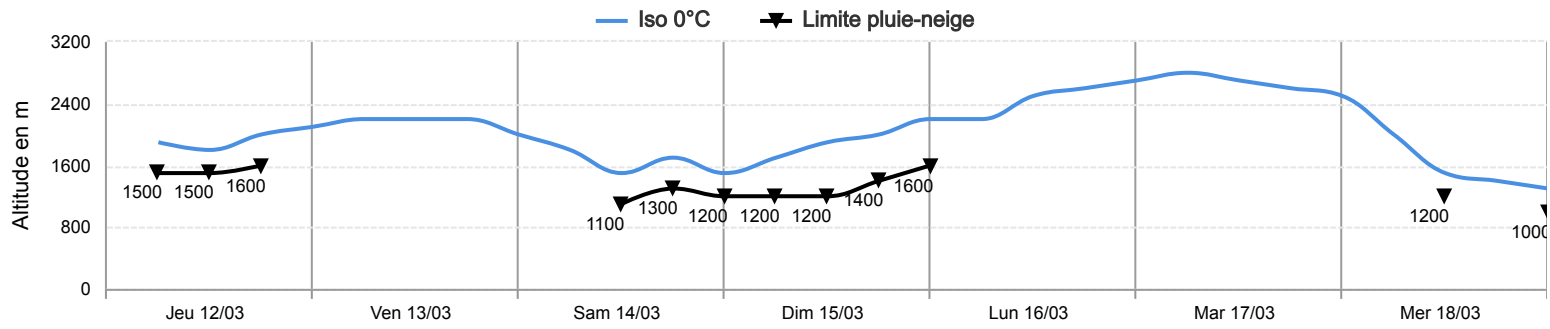

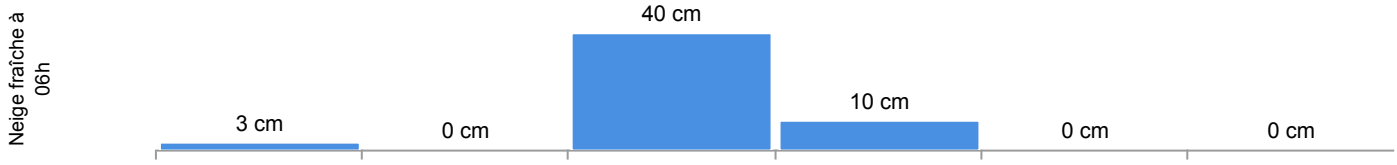

Risque d'avalanche	jeu. 12/03	ven. 13/03	sam. 14/03	dim. 15/03	lun. 16/03	mar. 17/03	mer. 18/03
	2	2	3	3	3	3	3

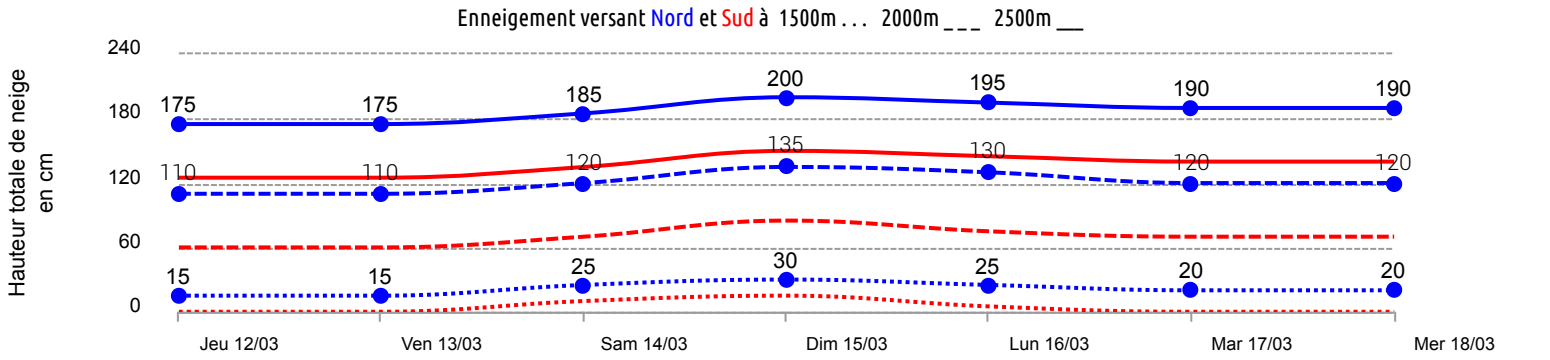

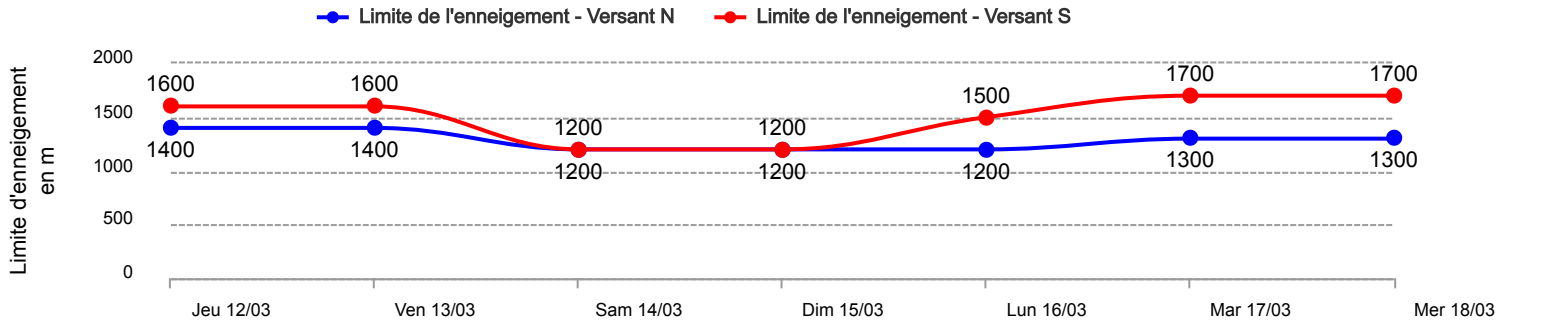

Pour consulter la vigilance en cours, veuillez vous rendre sur le site https://vigilance.meteofrance.fr/fr

Météo-France - 73 avenue de Paris, 94165 Saint-Mandé cedex - Contact : contact@meteo.fr

Rédigé par Météo-France avec la contribution des observateurs du réseau nivo-météorologiques. Partenariat : ANMSM (Maires de Stations de Montagne), DSF (Domaines Skiables de France), ADSP (Directeurs de Pistes et de la Sécurité des Stations de Sports d'Hiver) et autres acteurs de la montagne.

Bulletin neige & avalanches par téléphone au
0 892 68 10 20 Service 0,35 € / min + prix appel