Bulletin d'estimation du risque d'avalanche
(valable en dehors des pistes balisées et ouvertes)

MASSIF : Mont-Blanc

Rédigé le mercredi 18 mars 2026 à 16h

Estimation des risques pour le : JEUDI 19 MARS

3

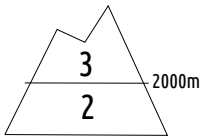

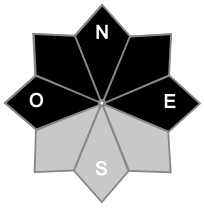

Au-dessus de 2000m indice de risque marqué, plus bas indice limité.

Départs spontanés : rares en neige humide

Déclenchements provoqués : plaques à vent dans les secteurs soumis au Foehn

Indices de risque : 5 très fort - 4 fort - 3 marqué - 2 limité - 1 faible -- En noir : les pentes les plus dangereuses

Stabilité du manteau neigeux

Situation avalancheuse typique : neige ventée

Déclenchements provoqués :
* **nombreuses plaques à vent**, principalement dans les versants **est, nord et ouest au-dessus de 2000 m** et **sud au-dessus de 3000 m**, rares en dessous. Elles sont dures. **Facile à déclencher**. Elles ont été formées par le fort Foehn mercredi après-midi. Taille 2 (moyenne).
Observables : accumulation de neige, vaguelettes, fissures sous les skis.
* rares plaques dures sur sous-couche fragile persistante enfouies, au-dessus de 2200 m. Difficile à déclencher. Départ possible par chutes de corniches, séracs ou avalanches en cascade. Taille 2 (moyenne) et rarement 3 (grande) avec d'épaisses cassures.
* un peu de neige humide peut couler sous les skis dans les versants ensoleillés aux heures les plus chaudes. Taille 1 (petite)

Départs spontanés :
* rares plaques de fond, de jour comme de nuit, dans les pentes lisses et raides (zones herbeuses, dalles rocheuses). Présentes dans les versants sud sous 2200 m et dans les versants nord sous 2000 m. Taille 2 (moyenne).
* rares avalanches de neige humide, dans les versants ensoleillés sous 2500 m, très rares en début de matinée et un peu plus nombreuses au fil de la course du soleil. Taille 1 rarement 2.
Observables : enfoncement piéton important, escargots.

Qualité de la neige

Enneigement : Pour la saison, l'enneigement est correct.
On peut chausser les skis vers 1200/1300 m en nord et 1400/1500 m en sud.
Grosses corniches présentes.

Qualité de la neige ce jeudi matin :
* en versant sud sous 2800 m et nord sous 1600/1800 m, fine croûte de regel non portante, s'humidifiant en journée.
* en versant nord au-dessus de 1600/1800 m et sud au-dessus de 2800 m, neige froide fortement travaillée par le vent.

Aperçu météo pour le jeudi 19 mars

	nuit	matin	après-midi	soir

ensoleillé, au maximum 5°C à 2000 m et 7°C à 1500 m.

Pluie-Neige				
Iso 0 °C	2 000 m	2 100 m	2 200 m	2 100 m
Vent 2000 m	↙ 20 km/h	↙ 25 km/h	↙ 10 km/h	↙ 10 km/h
Vent 4000 m	← 60 km/h	← 60 km/h	↙ 60 km/h	↙ 60 km/h

Épaisseur de neige hors-piste

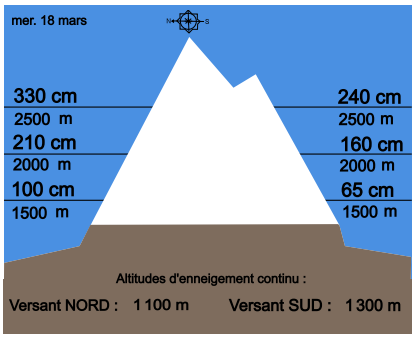

Précipitations à 1800 m

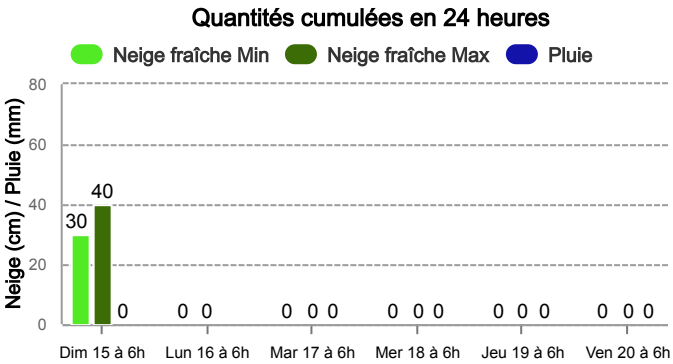

Tendance du vendredi 20 mars

2

Indice de risque limité

Vendredi, ensoleillé avec peu de vent et un isotherme 0°C vers 2000 m.
⇒ stabilisation progressive des plaques à vent, quelques petites avalanches de neige humide au soleil.

Pour consulter la vigilance en cours, veuillez vous rendre sur le site https://vigilance.meteofrance.fr/fr

Météo-France - 73 avenue de Paris, 94165 Saint-Mandé cedex - Contact : contact@meteo.fr

Rédigé par Météo-France avec la contribution des observateurs du réseau nivo-météorologiques. Partenariat : ANMSM (Maires de Stations de Montagne), DSF (Domaines Skiables de France), ADSP (Directeurs de Pistes et de la Sécurité des Stations de Sports d'Hiver) et autres acteurs de la montagne.

Bulletin neige & avalanches par téléphone au
0 892 68 10 20 Service 0,35 € / min + prix appel

RÉPUBLIQUE FRANÇAISE
Liberté Égalité Fraternité

METEO FRANCE
À VOS CÔTÉS, DANS UN CLIMAT QUI CHANGE

Bulletin d'estimation du risque d'avalanche

(valable en dehors des pistes balisées et ouvertes)

MASSIF : Mont-Blanc

Rédigé le mercredi 18 mars 2026 à 16h

Conditions nivo-météo des 7 derniers jours

	jeu. 12/03				ven. 13/03				sam. 14/03				dim. 15/03				lun. 16/03				mar. 17/03				mer. 18/03			
	03h	09h	15h	21h	03h	09h	15h	21h	03h	09h	15h	21h	03h	09h	15h	21h	03h	09h	15h	21h	03h	09h	15h	21h	03h	09h	15h	21h
Météo																												
Vent (km/h)	40	40	30	25	25	35	45	60	45	40	25	30	30	35	40	60	70	80	60	70	65	65	70	70	80	100	100	80
à 4000m																												
Vent (km/h)	10	5	5	5	20	30	40	50	30	25	20	25	25	10	10	10	10	20	15	20	20	20	25	20	15	40	80	40
à 2000m																												

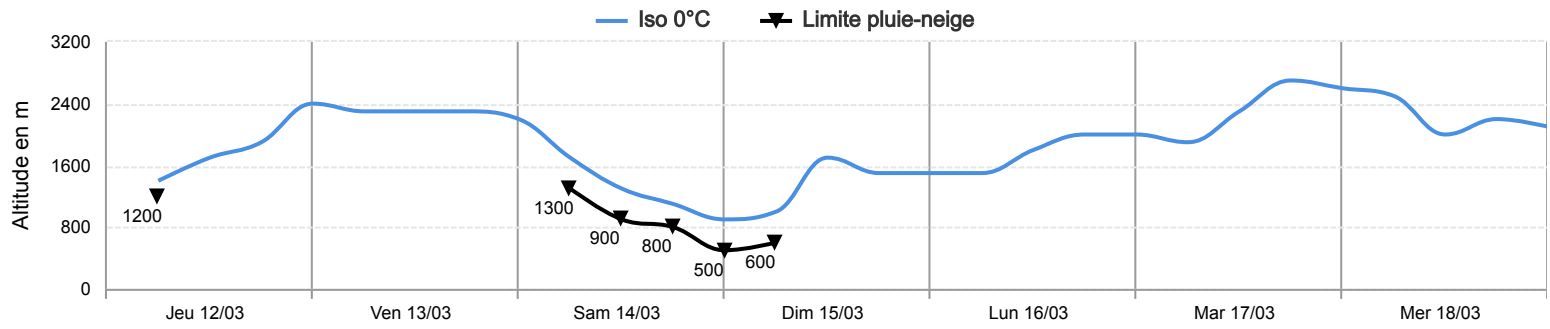

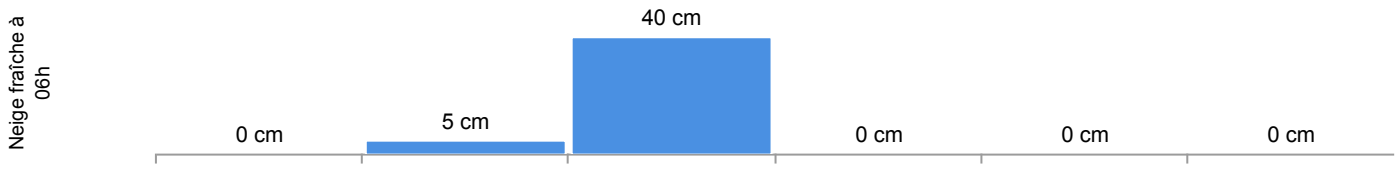

Risque d'avalanche	jeu. 12/03	ven. 13/03	sam. 14/03	dim. 15/03	lun. 16/03	mar. 17/03	mer. 18/03
	2	3	3	3	3	3	3

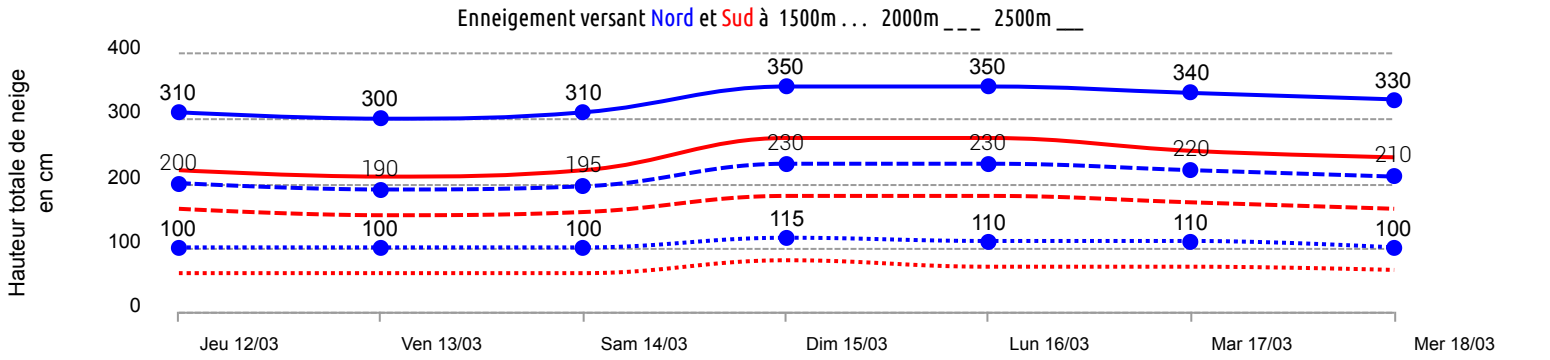

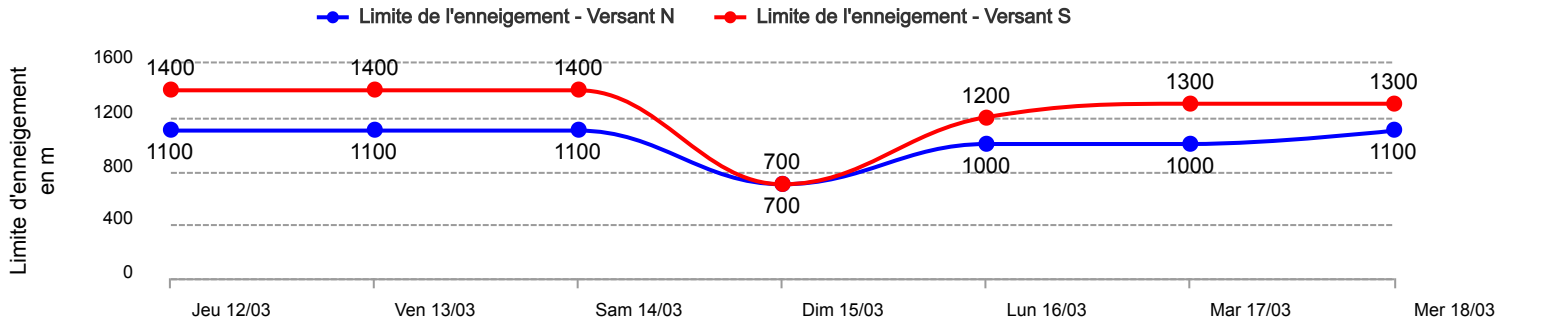

Pour consulter la vigilance en cours, veuillez vous rendre sur le site https://vigilance.meteofrance.fr/fr

Météo-France - 73 avenue de Paris, 94165 Saint-Mandé cedex - Contact : contact@meteo.fr

Rédigé par Météo-France avec la contribution des observateurs du réseau nivo-météorologiques. Partenariat : ANMSM (Maires de Stations de Montagne), DSF (Domaines Skiables de France), ADSP (Directeurs de Pistes et de la Sécurité des Stations de Sports d'Hiver) et autres acteurs de la montagne.

Bulletin neige & avalanches par téléphone au
0 892 68 10 20 Service 0,35 € / min + prix appel