Bulletin d'estimation du risque d'avalanche
(valable en dehors des pistes balisées et ouvertes)

MASSIF : Pays-Basque

Rédigé le mercredi 18 mars 2026 à 16h

Estimation des risques pour le : JEUDI 19 MARS

RARES PLAQUES AU PLUS HAUT DU MASSIF, POURSUITE DE L'HUMIDIFICATION AILLEURS.

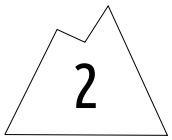

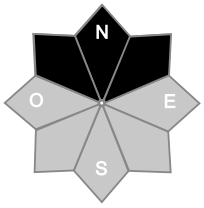

Rares plaques.

Indice de risque limité.

Départs spontanés : En neige humide, avalanches de fond possibles.

Déclenchements provoqués : rares plaques au plus haut du massif.

Indices de risque : 5 très fort - 4 fort - 3 marqué - 2 limité - 1 faible -- En noir : les pentes les plus dangereuses

Stabilité du manteau neigeux

Situation avalancheuse typique : neige humide neige ventée

Déclenchements provoqués :
- **Au plus haut du massif**, dans les pentes raides allant du Nord-Ouest au Nord-Est, de rares plaques peuvent encore persister. Elles sont maintenant difficilement déclenchables par un simple skieur mais leur sollicitation peut encore engendrer des cassures linéaires petites à moyennes (taille 1 à 2).
- **Ailleurs**, un regel efficace devrait réduire le risque avalancheux au petit matin. Puis, un skieur peut déclencher par forte sollicitation des avalanches dans la neige s'humidifiant en toutes orientations au fil de la journée. Des avalanches petites à moyennes sont possibles (taille 1 à 2).

Départs spontanés :
- **Au plus haut du massif**, des départs ponctuels de plaques décrites ci-dessus restent possibles, par surcharge par le vent, engendrant généralement des avalanches petites à moyennes (taille 1 à 2).
- **Ailleurs**, des départs ponctuels dans la neige humide sont attendus dans les pentes raides en toutes orientations et au fil de la journée. Un regel efficace devrait limiter cette activité avalancheuse tôt le matin. Les avalanches sont généralement petites à moyennes (taille 1 à 2). Des avalanches de fond restent aussi possibles dans les pentes raides des versants au fil de la journée, engendrant des avalanches généralement moyennes (taille 2).

Autres : Pont de neige et corniches encore en place fragilisés.

Qualité de la neige

Enneigement : Correct pour la saison, surtout au-dessus de 1800 m, mais reste assez maigre en versants exposés au vent d'ouest. Il débute assez bas, mais n'est skiable qu'à partir de 1600m en nord, plutôt 1800 en sud, faute de sous-couche.
État de la neige : Au petit matin, la neige reste encore sèche au plus haut du massif dans les pentes Nord-Ouest à Nord-Est. Elle est regelée plus bas et partout ailleurs. En journée, une fine couche de neige peut venir se déposer sur le manteau neigeux au-dessus de 1800m. Sinon, la neige reste bien ramollie, lourde et poursuit son humidification. La neige restée sèche au plus haut du massif et dans les versants Nord s'humidifie un peu plus en profondeur.

Aperçu météo pour le jeudi 19 mars

	nuit	matin	après-midi	soir

Belles éclaircies le matin. Ciel un peu plus couvert ensuite, faibles averses attendues. Ciel dégagé la nuit suivante. Vent faible à modéré.

Pluie-Neige		1 800 m		
Iso 0 °C	3 100 m	2 500 m	2 300 m	2 500 m
Vent 1000 m	↑ 30 km/h	↑ 20 km/h	↖ 20 km/h	↑ 15 km/h
Vent 2000 m	→ 55 km/h	↑ 35 km/h	↑ 35 km/h	↑ 25 km/h

Épaisseur de neige hors-piste

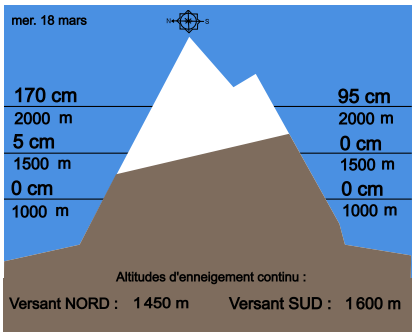

Précipitations à 1800 m

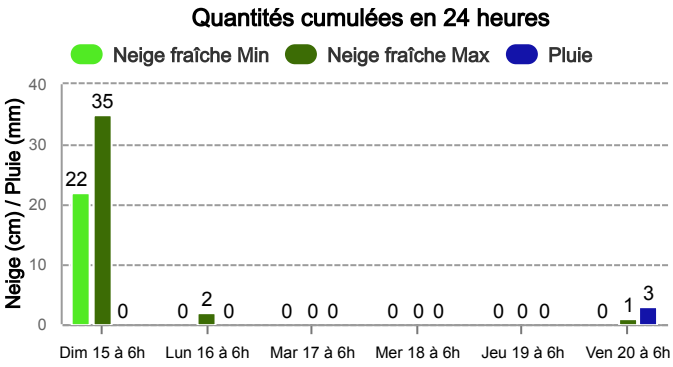

Tendance du vendredi 20 mars

Indice de risque limité

Risque potentiellement en baisse, les rares plaques en altitude s'humidifient. L'humidification du manteau neigeux se poursuit ailleurs avec les éclaircies.

Pour consulter la vigilance en cours, veuillez vous rendre sur le site https://vigilance.meteofrance.fr/fr

Météo-France - 73 avenue de Paris, 94165 Saint-Mandé cedex - Contact : contact@meteo.fr

Rédigé par Météo-France avec la contribution des observateurs du réseau nivo-météorologiques. Partenariat : ANMSM (Maires de Stations de Montagne), DSF (Domaines Skiables de France), ADSP (Directeurs de Pistes et de la Sécurité des Stations de Sports d'Hiver) et autres acteurs de la montagne.

Bulletin neige & avalanches par téléphone au 0 892 68 10 20 Service 0,35 € / min + prix appel

RÉPUBLIQUE FRANÇAISE
Liberté Égalité Fraternité

METEO FRANCE
À VOS CÔTÉS, DANS UN CLIMAT QUI CHANGE

Bulletin d'estimation du risque d'avalanche

(valable en dehors des pistes balisées et ouvertes)

MASSIF : Pays-Basque

Rédigé le mercredi 18 mars 2026 à 16h

Conditions nivo-météo des 7 derniers jours

	jeu. 12/03				ven. 13/03				sam. 14/03				dim. 15/03				lun. 16/03				mar. 17/03				mer. 18/03			
	03h	09h	15h	21h	03h	09h	15h	21h	03h	09h	15h	21h	03h	09h	15h	21h	03h	09h	15h	21h	03h	09h	15h	21h	03h	09h	15h	21h
Météo																												
Vent (km/h)	30	35	20	20	30	60	55	55	65	60	55	70	70	75	65	50	50	35	30	20	15	15	15	25	25	20	30	55
à 2000m																												
Vent (km/h)	10	15	5	5	15	20	20	15	25	20	20	35	40	50	35	20	20	20	15	5	10	5	10	15	15	5	10	35
à 1000m																												

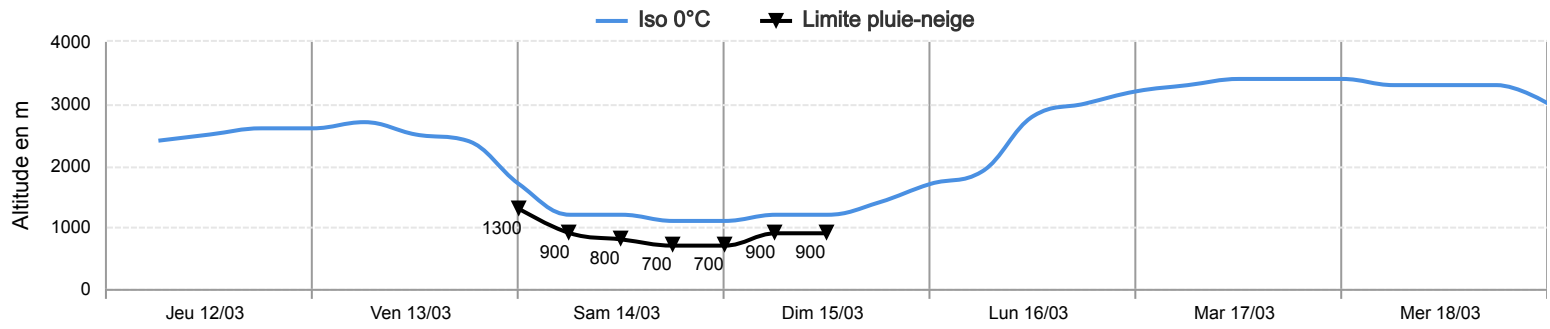

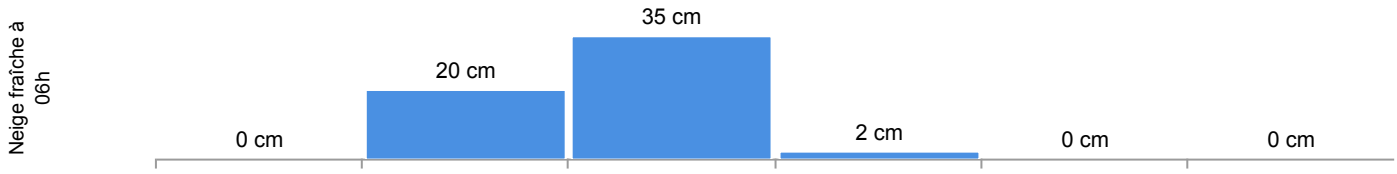

Risque d'avalanche	jeu. 12/03	ven. 13/03	sam. 14/03	dim. 15/03	lun. 16/03	mar. 17/03	mer. 18/03
	2	1	3	3	3	2	2

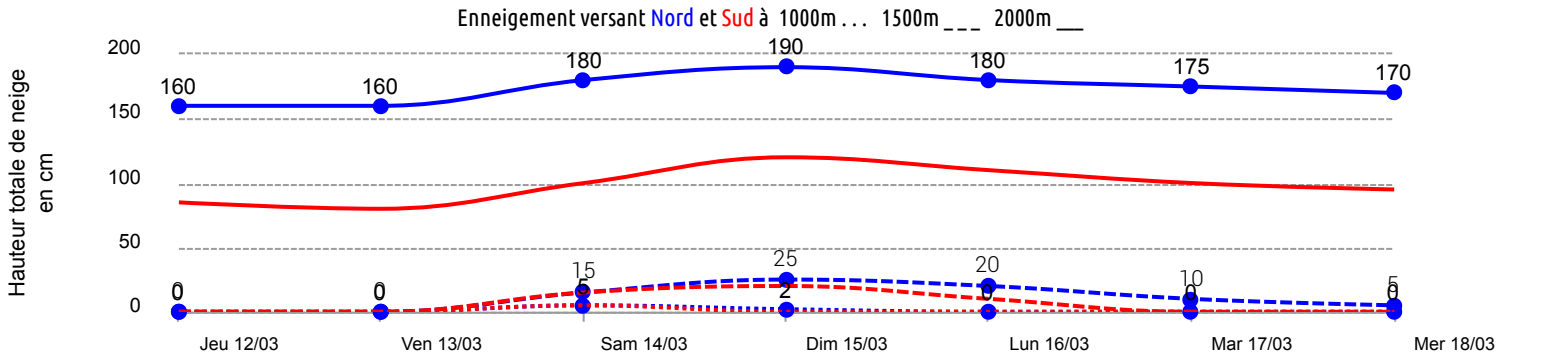

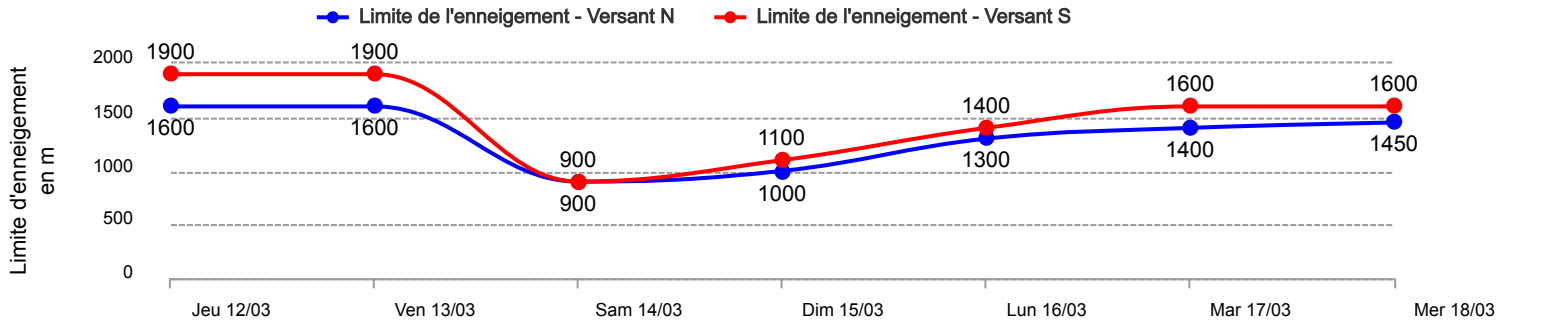

Pour consulter la vigilance en cours, veuillez vous rendre sur le site https://vigilance.meteofrance.fr/fr

Météo-France - 73 avenue de Paris, 94165 Saint-Mandé cedex - Contact : contact@meteo.fr

Rédigé par Météo-France avec la contribution des observateurs du réseau nivo-météorologiques. Partenariat : ANMSM (Maires de Stations de Montagne), DSF (Domaines Skiables de France), ADSP (Directeurs de Pistes et de la Sécurité des Stations de Sports d'Hiver) et autres acteurs de la montagne.

Bulletin neige & avalanches par téléphone au
0 892 68 10 20
Service 0,35 € / min + prix appel