Bulletin d'estimation du risque d'avalanche
(valable en dehors des pistes balisées et ouvertes)

MASSIF : Thabor

Rédigé le mercredi 18 mars 2026 à 16h

Estimation des risques pour le : JEUDI 19 MARS

PLAQUES DANS LA NEIGE RÉCENTE VENTÉE

3

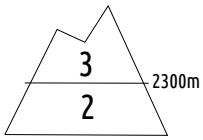

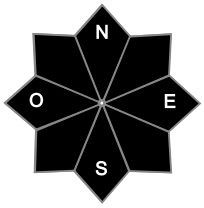

Au-dessus de 2300m indice de risque marqué, plus bas indice limité.

Départs spontanés : rares avalanches de plaque le matin, rares départs en neige humide au soleil

Déclenchements provoqués : avalanches de plaques.

Indices de risque : 5 très fort - 4 fort - 3 marqué - 2 limité - 1 faible -- En noir : les pentes les plus dangereuses

Stabilité du manteau neigeux

Situation avalancheuse typique : neige ventée

Déclenchements provoqués : plaques à vent en place, de rares nouvelles en formation en début de journée avec le vent d'est encore sensible. Ces instabilités se situent dans les zones d'accumulation de neige, souvent derrière les crêtes et ruptures de pentes, parfois assez loin. Elles sont présentes principalement au dessus de 2300 m environ, possibles en toutes orientations mais plus fréquentes en versants est, nord et ouest. Elles peuvent être déclenchées facilement au passage d'un skieur, et provoquer des avalanches de taille petite à moyenne (1 à 2) en général.
Bien que difficile à déclencher, une rare grande avalanche n'est pas exclue, par exemple si la surcharge d'une avalanche de surface vient déstabiliser une couche fragile persistante enfouie en profondeur dans le manteau neigeux.
En dessous de 2300 m, quelques plaques peu volumineuses sont toutefois possibles.

Départs spontanés :
- Rares départs en plaques encore possibles en début de journée, par surcharge liée au transport de la neige par le vent d'est. Devenant peu probables en cours de journée avec l'affaiblissement du vent. De taille petite à moyenne.
- Rares départs ponctuels de neige s'humidifiant en pentes raides ensoleillées au fil de la journée. Départs généralement de petite taille.

Qualité de la neige

L'enneigement est proche des normales pour une mi-mars.
Hauteurs de neige observées vers 2500 m : 175 cm dans le vallon du Chardonnet, 125 cm à la nivôse des Rochilles, 83 cm à la Nivôse du Galibier.

Limite d'enneigement skiable : vers 1400/1500 m en ubacs, 1700/1900 m en adrets pas trop raides.

État de la neige de surface : après un bon regel nocturne en versants ensoleillés, reprise d'une humidification superficielle en journée. Au-dessus de 2300/2400 m, neige récente souvent travaillée par le vent, encore localement poudreuse en ubacs restés abrités.

Aperçu météo pour le jeudi 19 mars

nuit	matin	après-midi	soir

Temps sec et ensoleillé. Vent d'est encore sensible en début de journée.

Pluie-Neige				
Iso 0 °C	1 500 m	2 000 m	2 300 m	1 900 m
Vent 2000 m	20 km/h	15 km/h	15 km/h	10 km/h
Vent 3000 m	55 km/h	50 km/h	30 km/h	10 km/h

Épaisseur de neige hors-piste

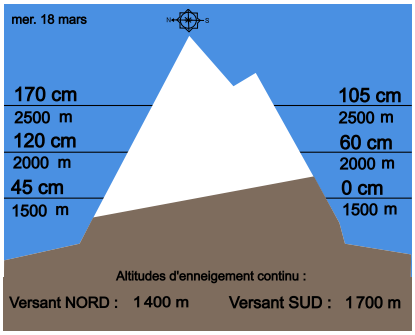

Précipitations à 1800 m

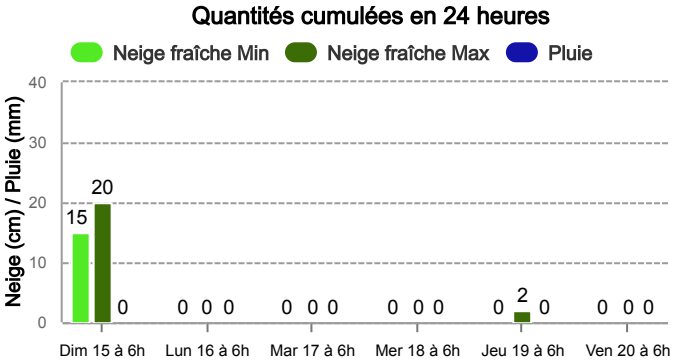

Tendance du vendredi 20 mars

2

Indice de risque limité

risque en baisse avec des conditions météorologiques calmes et ensoleillées, favorisant la stabilisation des plaques en place.

Pour consulter la vigilance en cours, veuillez vous rendre sur le site https://vigilance.meteofrance.fr/fr

Météo-France - 73 avenue de Paris, 94165 Saint-Mandé cedex - Contact : contact@meteo.fr

Rédigé par Météo-France avec la contribution des observateurs du réseau nivo-météorologiques. Partenariat : ANMSM (Maires de Stations de Montagne), DSF (Domaines Skiables de France), ADSP (Directeurs de Pistes et de la Sécurité des Stations de Sports d'Hiver) et autres acteurs de la montagne.

Bulletin neige & avalanches par téléphone au
0 892 68 10 20 Service 0,35 € / min + prix appel

RÉPUBLIQUE FRANÇAISE
Liberté Égalité Fraternité

METEO FRANCE
À VOS CÔTÉS, DANS UN CLIMAT QUI CHANGE

Bulletin d'estimation du risque d'avalanche

(valable en dehors des pistes balisées et ouvertes)

MASSIF : Thabor

Rédigé le mercredi 18 mars 2026 à 16h

Conditions nivo-météo des 7 derniers jours

	jeu. 12/03				ven. 13/03				sam. 14/03				dim. 15/03				lun. 16/03				mar. 17/03				mer. 18/03			
	03h	09h	15h	21h	03h	09h	15h	21h	03h	09h	15h	21h	03h	09h	15h	21h	03h	09h	15h	21h	03h	09h	15h	21h	03h	09h	15h	21h
Météo																												
Vent (km/h)	40	30	20	10	10	10	15	20	50	30	5	15	20	45	40	10	30	40	50	40	35	20	25	25	40	50	70	65
à 3000m																												
Vent (km/h)	20	20	15	10	10	10	15	10	5	5	10	20	10	20	15	5	10	30	40	25	20	15	20	15	20	30	40	20
à 2000m																												

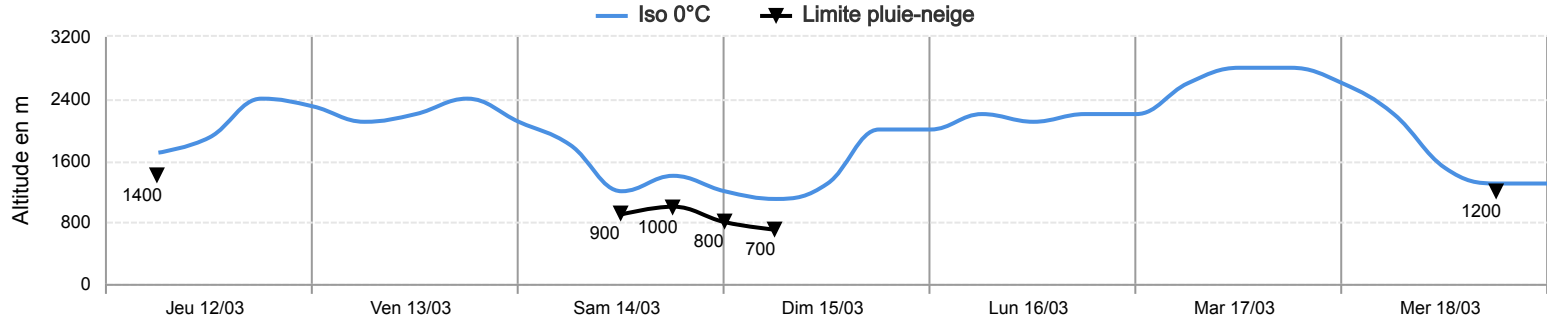

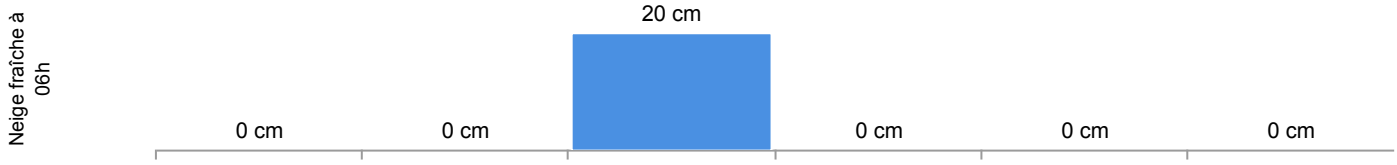

Risque d'avalanche	jeu. 12/03	ven. 13/03	sam. 14/03	dim. 15/03	lun. 16/03	mar. 17/03	mer. 18/03
	2	2	3	3	3	3	3

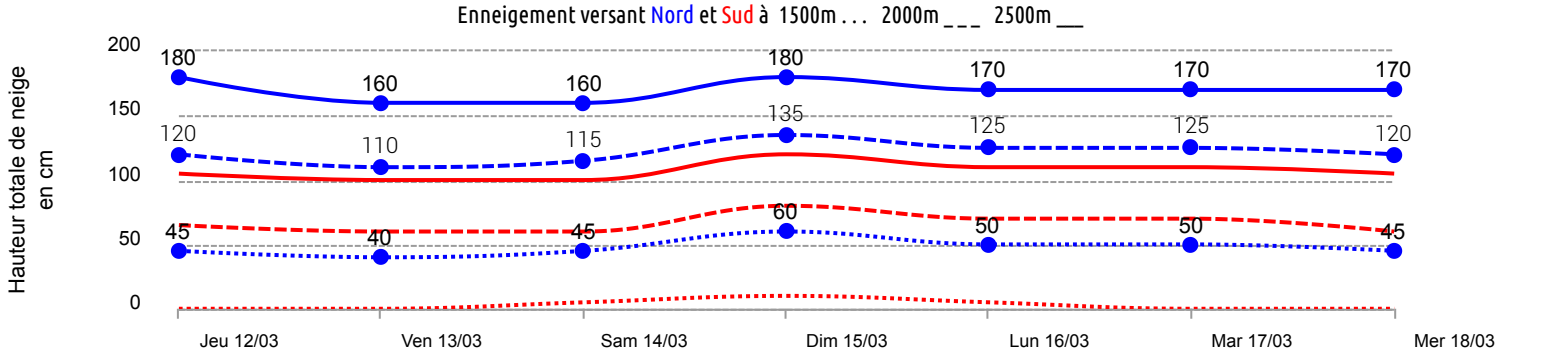

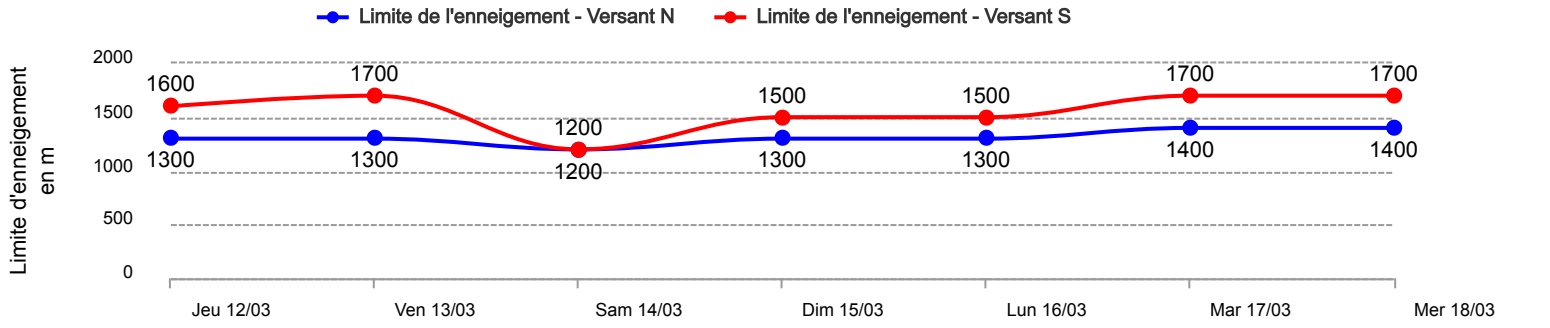

Pour consulter la vigilance en cours, veuillez vous rendre sur le site https://vigilance.meteofrance.fr/fr

Météo-France - 73 avenue de Paris, 94165 Saint-Mandé cedex - Contact : contact@meteo.fr

Rédigé par Météo-France avec la contribution des observateurs du réseau nivo-météorologiques. Partenariat : ANMSM (Maires de Stations de Montagne), DSF (Domaines Skiables de France), ADSP (Directeurs de Pistes et de la Sécurité des Stations de Sports d'Hiver) et autres acteurs de la montagne.

Bulletin neige & avalanches par téléphone au
0 892 68 10 20
Service 0,35 € / min + prix appel