Bulletin d'estimation du risque d'avalanche
(valable en dehors des pistes balisées et ouvertes)

MASSIF : Vanoise

Rédigé le mercredi 18 mars 2026 à 16h

Estimation des risques pour le : JEUDI 19 MARS

NOMBREUSES STRUCTURES DE PLAQUE DANS LA NEIGE VENTEE.

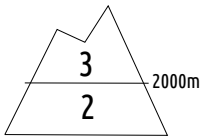

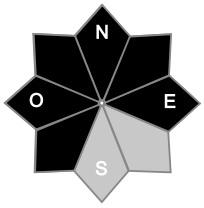

Au-dessus de 2000m indice de risque marqué, plus bas indice limité.

Départs spontanés : rares. Petites coulées au Soleil.

Déclenchements provoqués : nombreuses plaques assez réactives.

Indices de risque : 5 très fort - 4 fort - 3 marqué - 2 limité - 1 faible -- En noir : les pentes les plus dangereuses

Stabilité du manteau neigeux

Situation avalancheuse typique : neige ventée

Déclenchements provoqués : des plaques sont en place suite au coup de vent d'Est de mercredi. On les trouve autant aux abords des crêtes qu'en pied de pente/fond de vallon. Les cassures sont irrégulières mais peuvent aisément dépasser les 50 cm. Avalanches de taille 2 (moyenne) fréquentes. **Facteur aggravant :** en versant NO, N et NE au-delà de 2200 m, la neige récente s'est localement déposée sur une fine couche de grains anguleux, ce qui tend à augmenter le volume de neige mobilisable, et donc la taille des avalanches.
Observables : accumulations identifiables visuellement, test du bâton (neige ferme surmontant de la neige meuble).

Départs spontanés : rares. Le retour du Soleil favorise les coulées de neige humide dans les versants raides qui auraient "trop chauffés". Dans de rares cas, une boulette peut déclencher en cascade une plaque à vent installée en contrebas, avalanche moyenne (taille 2) alors possible.

Qualité de la neige

Enneigement : globalement très bon pour la saison.

Limite skiable : encore skiable dès 1100/1200 m dans les prairies orientées nord, plutôt 1500/1600 m en sud pas trop raide.

Qualité de la neige :
- en versants ombragés, crouté sous 1800/2000 m. Au-dessus, la neige a été très travaillée par le vent. Les champs de poudre se font rares. Elle est souvent densifiée, cartonnée voire carrément dure près des crêtes.
- en versants ensoleillés, très bon regel au réveil. Neige croutée le matin qui décaille tranquillement au fil des heures. La neige devient alors lourde et collante. Il n'y a qu'en plein Sud que les conditions se rapprochent de celles de printemps.

Aperçu météo pour le jeudi 19 mars

nuit	matin	après-midi	soir

Belles conditions printanières.

Pluie-Neige				
Iso 0 °C	2 000 m	2 100 m	2 200 m	2 100 m
Vent 2500 m	30 km/h	15 km/h	10 km/h	10 km/h
Vent 3500 m	40 km/h	20 km/h	15 km/h	15 km/h

Épaisseur de neige hors-piste

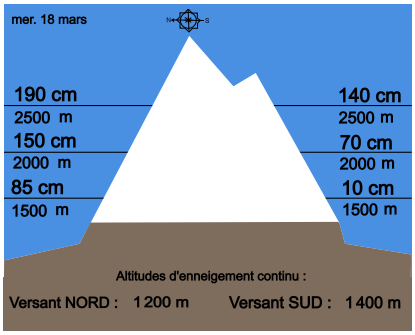

Précipitations à 1800 m

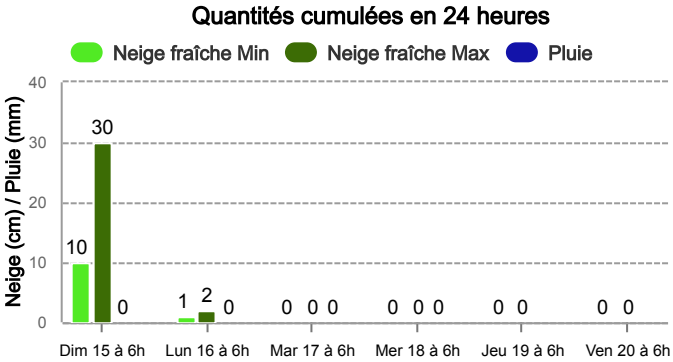

Tendance du vendredi 20 mars

Indice de risque limité

Grâce à une stabilisation relativement efficace, le nombre de plaques déclenchables à l'échelle du massif baisse rapidement. Un risque limité s'envisage pour vendredi.

Pour consulter la vigilance en cours, veuillez vous rendre sur le site https://vigilance.meteofrance.fr/fr

Météo-France - 73 avenue de Paris, 94165 Saint-Mandé cedex - Contact : contact@meteo.fr

Rédigé par Météo-France avec la contribution des observateurs du réseau nivo-météorologiques. Partenariat : ANMSM (Maires de Stations de Montagne), DSF (Domaines Skiables de France), ADSP (Directeurs de Pistes et de la Sécurité des Stations de Sports d'Hiver) et autres acteurs de la montagne.

Bulletin neige & avalanches par téléphone au
0 892 68 10 20 Service 0,35 € / min + prix appel

RÉPUBLIQUE FRANÇAISE
Liberté Égalité Fraternité

METEO FRANCE
À VOS CÔTÉS, DANS UN CLIMAT QUI CHANGE

Bulletin d'estimation du risque d'avalanche

(valable en dehors des pistes balisées et ouvertes)

MASSIF : Vanoise

Rédigé le mercredi 18 mars 2026 à 16h

Conditions nivo-météo des 7 derniers jours

	jeu. 12/03				ven. 13/03				sam. 14/03				dim. 15/03				lun. 16/03				mar. 17/03				mer. 18/03			
	03h	09h	15h	21h	03h	09h	15h	21h	03h	09h	15h	21h	03h	09h	15h	21h	03h	09h	15h	21h	03h	09h	15h	21h	03h	09h	15h	21h
Météo																												
Vent (km/h)	45	30	30	25	20	25	35	65	50	15	35	40	30	40	20	15	30	40	40	30	30	30	30	30	35	45	60	50
à 3500m																												
Vent (km/h)	30	15	15	10	10	15	20	40	30	5	20	25	15	25	10	5	10	20	25	15	10	10	15	15	20	30	50	40
à 2500m																												

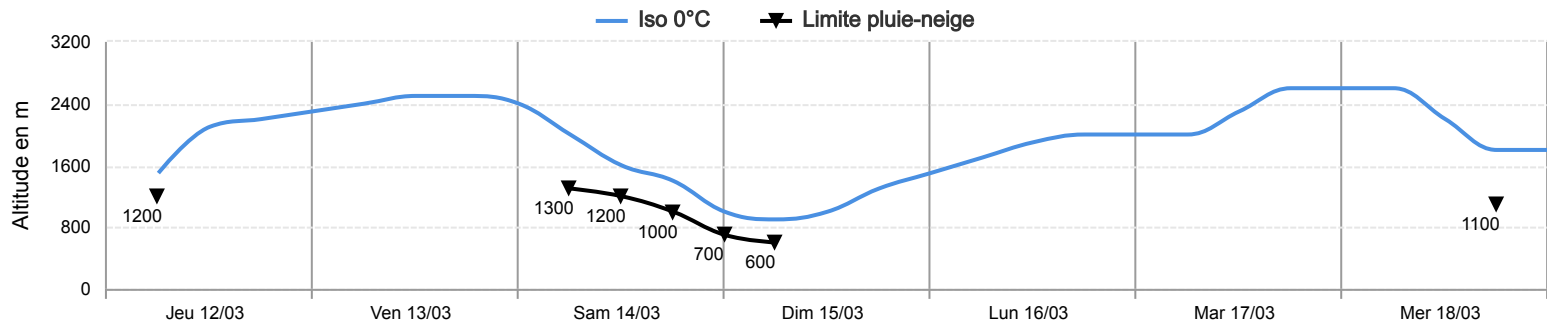

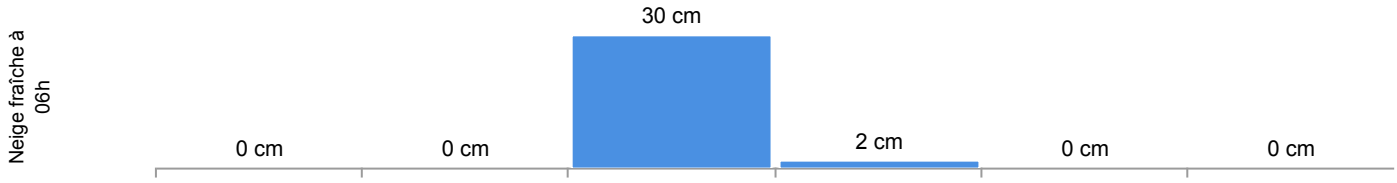

Risque d'avalanche	jeu. 12/03	ven. 13/03	sam. 14/03	dim. 15/03	lun. 16/03	mar. 17/03	mer. 18/03
	2	2	3	3	3	2	3

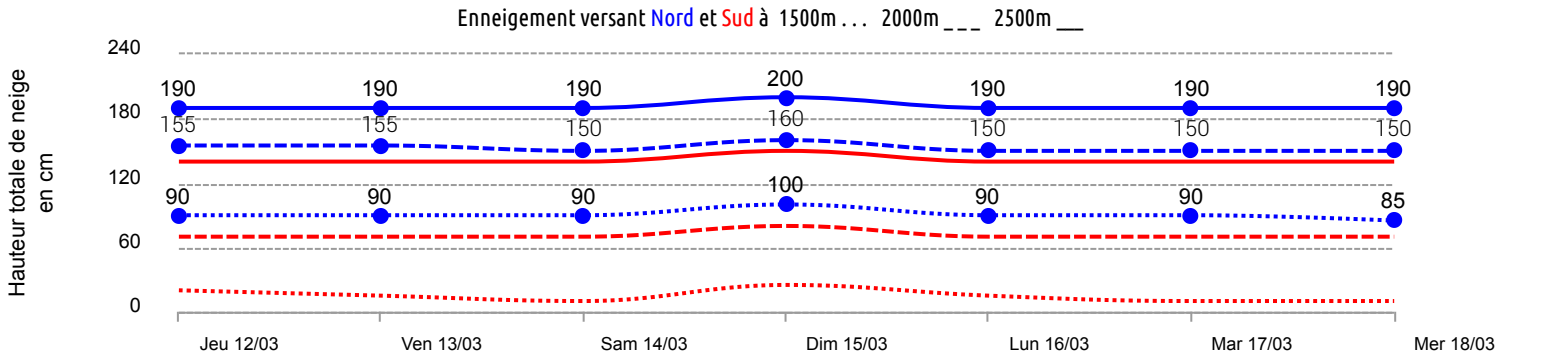

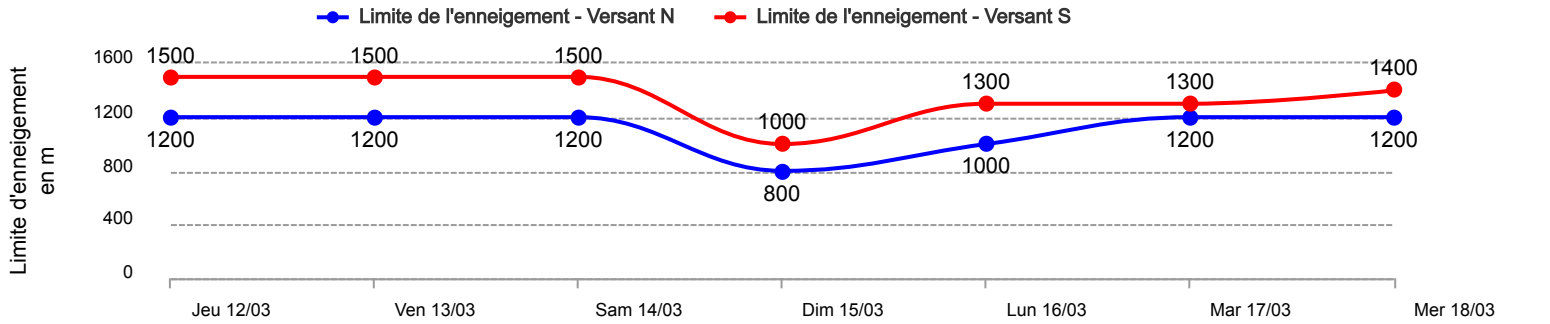

Pour consulter la vigilance en cours, veuillez vous rendre sur le site https://vigilance.meteofrance.fr/fr

Météo-France - 73 avenue de Paris, 94165 Saint-Mandé cedex - Contact : contact@meteo.fr

Rédigé par Météo-France avec la contribution des observateurs du réseau nivo-météorologiques. Partenariat : ANMSM (Maires de Stations de Montagne), DSF (Domaines Skiables de France), ADSP (Directeurs de Pistes et de la Sécurité des Stations de Sports d'Hiver) et autres acteurs de la montagne.

Bulletin neige & avalanches par téléphone au
0 892 68 10 20 Service 0,35 € / min + prix appel