GOBIERNO DE ESPAÑA
VICEPRESIDENCIA TERCERA DEL GOBIERNO
MINISTERIO PARA LA TRANSICIÓN ECOLÓGICA Y EL RETO DEMOGRÁFICO

Boletín de información nivológica y de peligro de aludes

Pirineo Navarro y Aragonés

aemet Agencia Estatal de Meteorología

jueves, 19 de marzo de 2026

Pronóstico hasta las 24 horas del viernes, día 20 de marzo

(Válido fuera de pistas de esquí balizadas y abiertas)

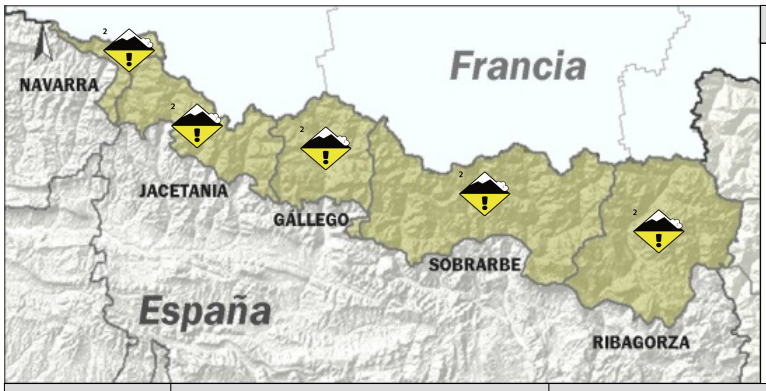

Problemas de aludes

Nieve húmeda

Capas débiles persistentes

Macizo	Peligro	Problemas de aludes, cota, orientación, tamaño	Innivación observada (m)
Navarra	2 Limitado	Nieve húmeda: 2	2026-03-19: Cota más baja caras N
Jacetania	2 Limitado	Nieve húmeda: 2; Capas débiles persistentes: 2 (2400)	2026-03-19: Cota más baja caras N
Gállego	2 Limitado	Nieve húmeda: 2; Capas débiles persistentes: 2 (2400)	2026-03-19: Cota más baja caras N
Sobrarbe	2 Limitado	Nieve húmeda: 2; Capas débiles persistentes: 2 (2400)	2026-03-19: Cota más baja caras N

AEMET. Se autoriza la reproducción de su contenido citando la fuente.

Boletín de información nivológica y de peligro de aludes

Pirineo Navarro y Aragonés

Ribagorza	**Limitado**	**Nieve húmeda** 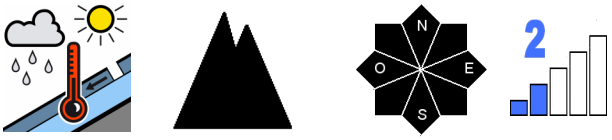 **Capas débiles persistentes** 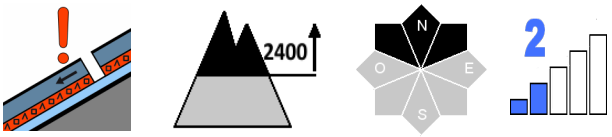	2026-03-19 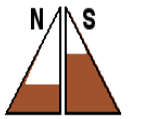 Cota más baja caras N

Estado del manto y observaciones recientes

Las temperaturas casi primaverales de estos días están favoreciendo la fusión y compactación de la nieve, con unos espesores que han ido menguando progresivamente; así, durante las últimas 24 horas, se han perdido de 2 a 6 cm adicionales en los diferentes puntos de observación. Pese a ello el manto sigue presentando continuidad desde medianías, a mayor altitud en la solanas, donde la insolación lo ha erosionado con relativa facilidad, aflorando la roca en una superficie cada vez más extensa. Los espesores rondan los 70 a 140 cm en torno a 1.800 metros y van aumentando conforme ascendemos, de tal manera que pueden superarse en algunas áreas los 180 a 200 cm en cota 2.100.

La nieve se encuentra muy humedecida en zonas medias y bajas. En cotas altas hallamos nieve húmeda superficial en las solanas que está sometida al ciclo de fusión diurna y rehielo nocturno; en las umbrías predomina la nieve más seca, venteada y encostrada, pudiendo existir estratos débiles en el interior del manto localizados a no demasiada profundidad.

Evolución del manto y peligro de aludes para el viernes, día 20

Situación de nieve húmeda. En cotas altas, capas débiles persistentes y placas de viento.

Las heladas nocturnas favorecerán la formación de costras de rehielo sobre la superficie del manto a primeras horas, lo que facilitará que la nieve se mantenga compacta y estable. Según transcurra la mañana, con el aumento de la insolación, esta costra tenderá a fundirse y la nieve se irá reblandeciendo progresivamente, lo que podrá dar lugar a purgas de nieve vieja húmeda en pendientes con suficiente inclinación, siendo más probables en áreas de solana, pero no se descartan en el resto de orientaciones. En general serían de tamaño pequeño o mediano, aunque es posible que, localmente, en laderas herbosas o de roca lisa, pueda haber algún deslizamiento basal que adquiera mayor magnitud al arrastrar gran cantidad de nieve.

En umbrías de cotas altas persisten estratos débiles en el interior del manto sobre los cuales pueden descansar antiguas placas de viento, sobre todo en las cercanías de crestas y collados. Estas estructuras son susceptibles de fracturarse ante una sobrecarga débil, como es el paso de un esquiador, dando lugar a aludes de dimensiones medianas, sin poder descartarse que, de manera muy local, puedan adquirir tamaño grande, suficiente como para enterrar a un grupo de personas, por lo que se recomienda tomar precauciones durante el tránsito por la zona.

AEMET. Se autoriza la reproducción de su contenido citando la fuente.

Predicción meteorológica para el viernes, día 20

Poco nuboso o despejado, con bancos de nubes bajas a primeras horas, localmente asociadas a brumas y nieblas, tendiendo a aumentar la nubosidad de tipo medio y alto al final del día. Temperaturas mínimas en ligero o moderado descenso en zonas bajas y con pocos cambios en medianías y cumbres. Las máximas experimentarán un ligero o moderado ascenso en toda el área. Heladas débiles, que podrán ser moderadas en cotas altas. Vientos flojos o moderados de componentes este y sur, con intervalos de intensidad fuerte en cotas altas y zonas expuestas del Pirineo navarro.

Datos en la atmósfera libre:

Altitud de la isoterma de 0 ºC: 2.600 m
Altitud de la isoterma de -10 ºC: 4.200 m

Viento a 1500 m: SE 30 km/h
Viento a 3000 m: SE 20 km/h

Evolución para el sábado día 21

Nivel de peligro con pocos cambios.

(Información elaborada a partir de los datos recibidos de los refugios de Linza, Panticosa, Bachimaña, Góriz, Pineta, Estós, Angel Orús, La Renclusa, Cap de Llauset y Belagua, de las estaciones de esquí de Formigal y Panticosa (lagos) y de Ordesa Pradera)

Escala europea de peligro de aludes

Débil | Limitado | Notable | Fuerte | Muy Fuerte

Problemas de aludes

Nieve reciente | Placas de viento | Capas débiles persistentes | Nieve húmeda | Deslizamientos basales | Sin problema evidente

Nota1: Se recuerda que, siempre que haya nieve, la ausencia total de peligro no existe. Hay que tener presente que en circunstancias desfavorables, con aludes de tamaño 1 (alud pequeño o colada) y tamaño 2 (alud mediano), se pueden sufrir severos daños personales.

Nota2: Los BPA se elaboran en base a información meteorológica así como al estado del manto nivoso a través de sondeos puntuales. Se advierte a los usuarios de la variabilidad de esta información al extrapolarla a zonas extensas de montaña. Por ello, AEMET no se hace responsable de su uso para la toma de decisiones que conciernen a la seguridad personal, ni de los riesgos físicos o materiales de ellas derivadas.

AEMET. Se autoriza la reproducción de su contenido citando la fuente.