Freitag 20.03.2026

Veröffentlicht am 19.03.2026 um 17:00

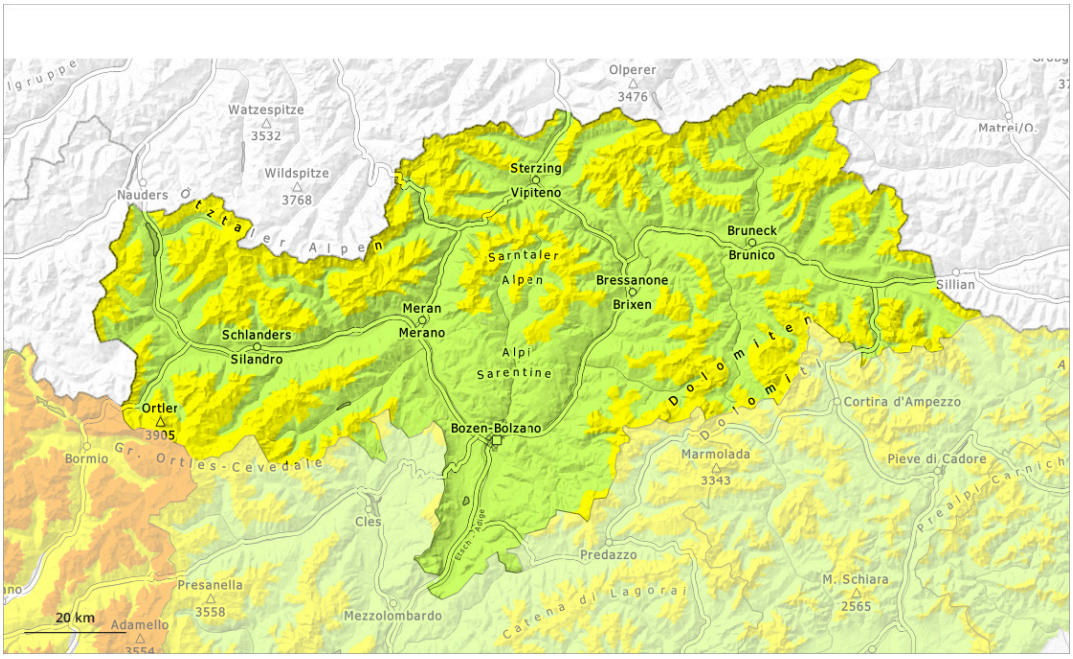

1	2	3	4	5
gering	mäßig	erheblich	groß	sehr groß

Gefahrenstufe 2 - Mäßig

2200m

Tendenz: Lawinengefahr bleibt gleich
am Samstag, den 21.03.2026

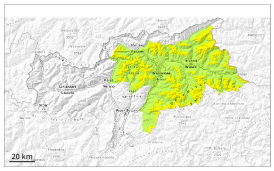

Triebschnee

2200m

Altschnee

2200m

Vorsicht vor frischem Triebschnee. Schwachen Altschnee beachten.

Frische und ältere Triebschneeansammlungen können vor allem an den Expositionen West über Nord bis Ost oberhalb von rund 2200 m noch ausgelöst werden. Dies teilweise schon durch einzelne Wintersportler. Solche Gefahrenstellen liegen in Rinnen, Mulden und hinter Geländekanten.

Lawinen können vereinzelt in bodennahen Schichten anreißen und mittlere Größe erreichen. Die Gefahrenstellen liegen vor allem an sehr steilen West-, Nord- und Osthängen oberhalb von rund 2200 m. Solche Gefahrenstellen sind selten aber kaum zu erkennen.

Schneedecke

Gefahrenmuster gm.6: lockerer schnee und wind | gm.7: schneearm neben schneereich

Mit starkem Wind aus wechselnden Richtungen entstanden Triebschneeansammlungen. Diese liegen oberhalb von rund 2200 m auf einer ungünstigen Altschneeoberfläche.

Im unteren Teil der Schneedecke sind an West-, Nord- und Osthängen störanfällige Schwachschichten vorhanden. Dies vor allem oberhalb von rund 2200 m.

Steile Sonnenhänge: Die Sonneneinstrahlung führt im Tagesverlauf zu einer allmählichen Anfeuchtung der Schneedecke.

Tendenz

Die Wetterbedingungen erlauben eine Stabilisierung der Triebschneeansammlungen. Die Sonneneinstrahlung führt im Tagesverlauf an sehr steilen Sonnenhängen zu einer Aufweichung der Schneedecke. Schwachen Altschnee beachten.

Gefahrenstufe 2 - Mäßig

2200m

Tendenz: Lawinengefahr bleibt gleich
am Samstag, den 21.03.2026

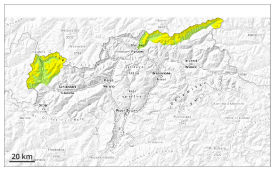

Triebschnee

2200m

Altschnee

2200m

Triebschnee und schwachen Altschnee beachten.

Die schon etwas älteren Triebschneeansammlungen können stellenweise leicht ausgelöst werden, besonders an sehr steilen West-, Nord- und Osthängen oberhalb von rund 2200 m. Gefahrenstellen liegen in Rinnen, Mulden und hinter Geländekanten. Sie sind für Geübte gut zu erkennen. Es sind kleine und vereinzelt mittlere Lawinen möglich.

Zudem können vereinzelt Lawinen in bodennahen Schichten anreißen. Solche Gefahrenstellen sind selten aber kaum zu erkennen. Ungünstig sind besonders Übergänge von wenig zu viel Schnee.

Schneedecke

Gefahrenmuster gm.6: lockerer schnee und wind | gm.7: schneearm neben schneereich

West-, Nord- und Osthänge oberhalb von rund 2200 m:
Triebschneeansammlungen liegen auf einer ungünstigen Altschneeoberfläche. Im unteren Teil der Schneedecke sind störanfällige Schwachschichten vorhanden.

Steile Sonnenhänge: Sonne und Wärme führen zu einer Anfeuchtung der Schneedecke.

Tendenz

Die Wetterbedingungen erlauben eine Stabilisierung der Triebschneeansammlungen. Die Sonneneinstrahlung führt im Tagesverlauf an sehr steilen Sonnenhängen zu einer Aufweichung der Schneedecke. Schwachen Altschnee beachten.

Gefahrenstufe 2 - Mäßig

2200m

Tendenz: Lawinengefahr bleibt gleich
am Samstag, den 21.03.2026

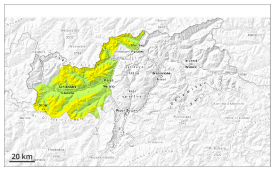

Triebschnee

2200m

Altschnee

2200m

Lawinen können teilweise in oberflächennahen Schichten ausgelöst werden. Schwachen Altschnee beachten.

Lawinen können teilweise in oberflächennahen Schichten der Schneedecke ausgelöst werden und mittlere Größe erreichen, besonders an sehr steilen Schattenhängen oberhalb von rund 2200 m sowie an sehr steilen Sonnenhängen oberhalb von rund 2500 m. Gefahrenstellen liegen in Rinnen, Mulden und hinter Geländekanten.

Zudem können vereinzelt Lawinen in bodennahen Schichten anreißen. Die Gefahrenstellen liegen vor allem an sehr steilen West-, Nord- und Osthängen oberhalb von rund 2200 m. Solche Gefahrenstellen sind selten aber kaum zu erkennen. Ungünstig sind besonders Übergänge von wenig zu viel Schnee. Lawinen können vereinzelt groß werden.

Schneedecke

Gefahrenmuster gm.6: lockerer schnee und wind | gm.7: schneearm neben schneereich

Oberhalb von rund 2200 m:
Der Neuschnee und die mit dem Wind entstandenen Triebschneeansammlungen liegen auf einer ungünstigen Altschneeoberfläche.
Im unteren Teil der Schneedecke sind an West-, Nord- und Osthängen störanfällige Schwachschichten vorhanden.

Steile Sonnenhänge: Die Sonneneinstrahlung führt zu einer Anfeuchtung der Schneedecke.

Tendenz

Die Wetterbedingungen erlauben eine allmähliche Stabilisierung der Triebschneeansammlungen. Die Sonneneinstrahlung führt im Tagesverlauf an sehr steilen Sonnenhängen zu einer Aufweichung der Schneedecke. Schwachen Altschnee beachten.

Gefahrenstufe 1 - Gering

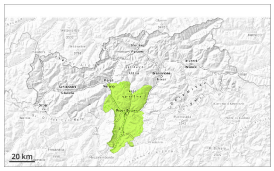

1

Tendenz: Lawinengefahr bleibt gleich
am Samstag, den 21.03.2026

Geringe Lawinengefahr.

Mit der tageszeitlichen Erwärmung sind einzelne feuchte Rutsche und Lawinen möglich, aber meist nur kleine, vor allem an extrem steilen Hängen bei Sonneneinstrahlung.
Trockene Lawinen können vor allem mit großer Belastung ausgelöst werden, sind aber meist klein.
Einzelne Gefahrenstellen liegen an steilen Schattenhängen in hohen Lagen.

Schneedecke

Gefahrenmuster gm.10: frühjahrssituation

Schattenhänge: In der Altschneedecke sind v.a. an Nordwest-, Nord- und Nordosthängen vereinzelt störanfällige Schwachschichten vorhanden.

Sonnenhänge: Die Altschneedecke ist feucht. Die Wetterbedingungen führen in mittleren und hohen Lagen zu einer Durchnässung der Schneedecke.

Tendenz

Geringe Lawinengefahr.