ICGC Institut Cartogràfic i Geològic de Catalunya

Servei Meteorològic de Catalunya meteo.cat

Boletín de peligro de aludes para el Pirineo de Catalunya
Del 19/03/2026 al 20/03/2026

(Válido fuera pistas de esquí y zonas no controladas)

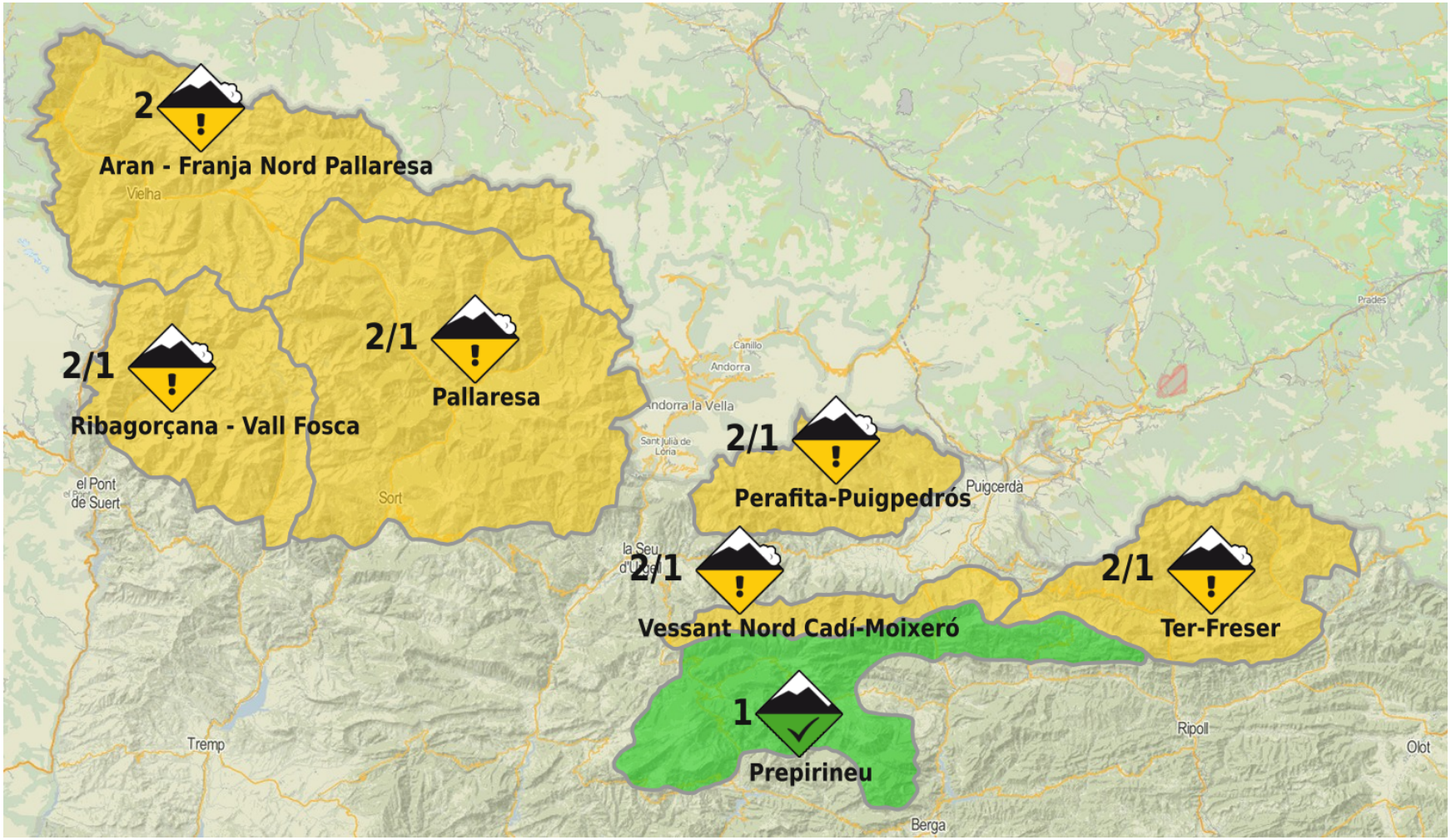

5 MUY FUERTE	4 FUERTE	3 NOTABLE	2 LIMITADO	1 DÉBIL

ICGC Institut Cartogràfic i Geològic de Catalunya

Servei Meteorològic de Catalunya meteo.cat

Boletín de peligro de aludes Aran - Franja Nord Pallaresa Del 19/03/2026 al 20/03/2026

(Válido fuera pistas de esquí y zonas no controladas)

LIMITADO (2).

Situación primaria

Capas débiles persistentes

Distribución

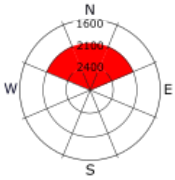

Tamaño

Origen

Tendencia

Situación secundaria

Nieve húmeda

Distribución

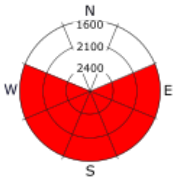

Tamaño

Origen

Tendencia

Estado del manto nivoso

Para el viernes encontraremos un manto más rehelado a primera hora. En umbrías el manto todavía presentará una estabilidad pobre, especialmente las placas antiguas que permanecen sobre facetas o escarcha. Deberemos estar atentos si al circular por el terreno se escuchan woumfs y vemos alguna grieta con propagaciones. En caso de romper y desencadenar una placa se podrán generar aludes de tamaño 2 (medio), con capacidad de enterrarnos, incluso, de tamaño 3 (grande), suficiente para enterrar a un grupo de montañeros, sobre todo en las laderas umbrías protegidas del viento y bajo collados y crestas. Con el viento del S y del E se habrá movido la nieve más reciente y se habrán formado placas de viento nuevas, de pequeño tamaño, bajo collados y crestas orientadas a Oeste y Norte. Son probables también aludes de nieve húmeda, a partir de mediodía, de hasta tamaño 2 (medio), en todas las cotas, en las solanas y hasta cota media, en umbrías. No se descarta algún deslizamiento basal.

Distribución del manto nivoso

Hay nieve por encima de unos 1.400-1-500 m en umbrías y 1.700 m en solanas. Los espesores a unos 2.200 m son ligeramente superiores a los normales en la Franja Nord de la Pallaresa y en la mitad sur de Arán donde rondan los 180-220 cm. En la mitad norte de Arán son los normales por estas fechas con unos 120-140 cm de espesor total.

Tendencia para las próximas 48-72h

Continuaremos con problemas por nieve húmeda a mediodía y por las capas débiles persistentes en umbrías. Peligro: SIN CAMBIOS

El próximo boletín será emitido el día 2026-03-20

5 MUY FUERTE	4 FUERTE	3 NOTABLE	2 LIMITADO	1 DÉBIL

EAWS EUROPEAN AVALANCHE WARNING SERVICES

ICGC Institut Cartogràfic i Geològic de Catalunya

Servei Meteorològic de Catalunya meteo.cat

Boletín de peligro de aludes Ribagorçana - Vall Fosca Del 19/03/2026 al 20/03/2026

(Válido fuera pistas de esquí y zonas no controladas)

LIMITADO (2), durante las horas centrales del día.
DÉBIL (1), a primera hora.

Situación primaria

Nieve húmeda

Distribución

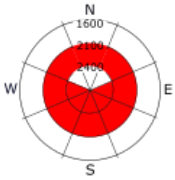

Tamaño

Origen

Tendencia

Situación secundaria

Capas débiles persistentes

Distribución

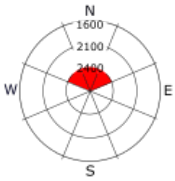

Tamaño

Origen

Tendencia

Estado del manto nivoso

Para el viernes esperamos una dinámica bastante primaveral, con una mañana con rehielo y una transformación de la nieve a mediodía a causa de la radiación. Con el humedecimiento del manto pueden caer aludes de fusión de forma natural que llegarán a tamaño 1 (pequeño), sin capacidad para enterrar a una persona. El terreno más afectado por aludes de fusión son las salidas de puntos oscuros (rocas y árboles) y las orientaciones este, sur y oeste. No se descartan tampoco a umbrías de cota media. Las placas de viento formadas durante el fin de semana permanecen sobre niveles débiles (facetas o nieve granulada) y pueden caer a nuestro paso. Los lugares peligrosos están bajo collados y cordales, por encima de 2.300-2.400 my también en las orientaciones umbrías resguardadas, entre 2200 y 2400 m. Las placas, en caso de romperse, podrán generar aludes de tamaño 2 (medio), con capacidad de enterrar a un montañero. Habrá que vigilar con los resbalones a primera hora, sobre todo en solanas.

Distribución del manto nivoso

Hay nieve en el suelo a 1.600 m en terreno umbrío, y por encima de unos 1.800 m en laderas soleadas. El manto es esquiable por encima de unos 1.800-1.900 m en umbrías. Los grosores alcanzan los 105-135 cm a unos 2.200 m. Estos valores son superiores a los normales para la época.

Tendencia para las próximas 48-72h

Seguiremos con el proceso de fusión-rehielo. Peligro: SIN CAMBIOS

El próximo boletín será emitido el día 2026-03-20

5 MUY FUERTE	4 FUERTE	3 NOTABLE	2 LIMITADO	1 DÉBIL

EAWS EUROPEAN AVALANCHE WARNING SERVICES

ICGC Institut Cartogràfic i Geològic de Catalunya

Servei Meteorològic de Catalunya

Boletín de peligro de aludes Pallaresa
Del 19/03/2026 al 20/03/2026

(Válido fuera pistas de esquí y zonas no controladas)

LIMITADO (2), durante las horas centrales del día.
DÉBIL (1), a primera hora.

Situación primaria

Nieve húmeda

Distribución

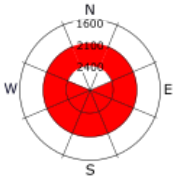

Tamaño

Origen

Tendencia

Situación secundaria

Capas débiles persistentes

Distribución

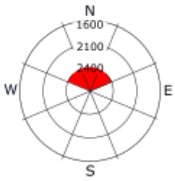

Tamaño

Origen

Tendencia

Estado del manto nivoso

Para el viernes esperamos una dinámica bastante primaveral, con una mañana con rehielo y una transformación de la nieve a mediodía a causa de la radiación. Con el humedecimiento del manto pueden caer aludes de fusión de forma natural que llegarán a tamaño pequeño, sin capacidad para enterrarnos. El terreno más afectado por aludes de fusión son las salidas de puntos oscuros (rocas y árboles) y las orientaciones E, S y O. No se descartan tampoco a umbrías de cota media. Las placas de viento formadas durante el fin de semana permanecen sobre niveles débiles (facetas o nieve granulada). Los lugares más delicados los encontraremos en el norte del sector (límite con el Aran), bajo collados y cordales, por encima de 2.300 m y también en las orientaciones umbrías resguardadas entre 2200 y 2400 m. Las placas, en caso de romperse, podrán generar aludes de tamaño medio, con capacidad de enterrar a un montañero. Habrá que vigilar con los resbalones a primera hora, sobre todo en solanas.

Distribución del manto nivoso

Hay nieve en el suelo a 1.600 m en N, ya 1.800-1.900 m en S. El manto es esquiable por encima de unos 1.800-1.900 m en umbrías. Los espesores alcanzan los 115-155 cm en cotas medias, variable según los efectos del viento.

Tendencia para las próximas 48-72h

Seguiremos con el proceso de fusión-rehielo. Peligro: SIN CAMBIOS

El próximo boletín será emitido el día 2026-03-20

5 MUY FUERTE	4 FUERTE	3 NOTABLE	2 LIMITADO	1 DÉBIL

EAWS EUROPEAN AVALANCHE WARNING SERVICES

ICGC Institut Cartogràfic i Geològic de Catalunya

Servei Meteorològic de Catalunya

Boletín de peligro de aludes Perafita-Puigpedrós Del 19/03/2026 al 20/03/2026

(Válido fuera pistas de esquí y zonas no controladas)

LIMITADO (2), durante las horas centrales del dia.
DÉBIL (1), a primera hora.

Situación primaria

Nieve húmeda

Distribución

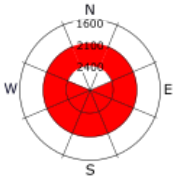

Tamaño

Origen

Tendencia

Estado del manto nivoso

El viernes veremos una dinámica primaveral en el manto, con presencia de rehielo a primera hora y una transformación de la nieve por la radiación solar, a partir de mediodía. Con el humedecimiento del manto pueden caer aludes de fusión de forma natural que llegarán a tamaño 1 (pequeño), sin capacidad para enterrarnos. El terreno más afectado por aludes de fusión son las salidas de puntos oscuros (rocas y árboles) y las orientaciones este, sur y oeste. No se descartan tampoco a umbrías de cota media. Localmente, en el límite norte del sector con Andorra, podremos encontrar todavía alguna placa antigua sobre niveles débiles (facetas o nieve granulada) que con un gran esfuerzo podría caer a nuestro paso. Los lugares más delicados están a umbrías, bajo collados y cordales, por encima de 2.400 m. Las placas, en caso de romperse, podrán generar aludes de tamaño 2 (medio), con capacidad de enterrar a un montañero. Habrá que vigilar con los resbalones a causa de un manto endurecido y rehelado.

Distribución del manto nivoso

En umbrías hay nieve por encima de 1.400-1.500 m, y en las solanas está presente por encima de 1.700 m. Los espesores, aunque irregulares, rondan los 85-105 cm en cotas medias. Son grosores por encima de los habituales para la época.

Tendencia para las próximas 48-72h

Continuaremos con las capas débiles persistentes en umbrías. Peligro: SIN CAMBIOS

El próximo boletín será emitido el día 2026-03-20

5 MUY FUERTE	4 FUERTE	3 NOTABLE	2 LIMITADO	1 DÉBIL

EAWS EUROPEAN AVALANCHE WARNING SERVICES

ICGC Institut Cartogràfic i Geològic de Catalunya

Servei Meteorològic de Catalunya

Boletín de peligro de aludes
Vessant Nord Cadí-Moixeró
Del 19/03/2026 al 20/03/2026

(Válido fuera pistas de esquí y zonas no controladas)

LIMITADO (2), durante las horas centrales del día por encima de los 2.200 m.
DÉBIL (1) en el resto.

Situación primaria

Nieve húmeda

Distribución

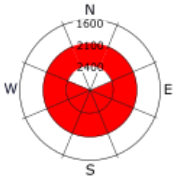

Tamaño

Origen

Tendencia

Estado del manto nivoso
El viernes se espera más rehielo y un manto endurecido a primera hora. Con el paso de las horas el humedecimiento del manto irá avanzando y pueden caer aludes de fusión de forma natural y también a nuestro paso, al ablandarse las costras) que llegarán a tamaño 1(pequeño), sin capacidad para enterrar a una persona, excepto en terreno trampa donde habrá que evitar pasar mientras la nieve no rehiele. Las orientaciones más peligrosas son las orientadas a Este, Sur, Oeste y las umbrías de cota media. El terreno más afectado por aludes de fusión son las zonas de salida de puntos oscuros como rocas y árboles. Habrá que vigilar los resbalones, sobre todo en lo alto de las Canals y bajo collados y crestas más elevadas, entre 2200-2400 m.

Distribución del manto nivoso
En umbrías hay presencia discontinua de nieve por encima de 1.600 m y es esquiable por encima de 1.900 m. Los grosores están alrededor de 160-180 cm a 2.200 m. Estos valores son muy excedentarios para la época del año.

Tendencia para las próximas 48-72h
Seguiremos con dinámica primaveral, con fusión-rehielo. Peligro: SIN CAMBIOS.

El próximo boletín será emitido el día 2026-03-20

5 MUY FUERTE	4 FUERTE	3 NOTABLE	2 LIMITADO	1 DÉBIL

EAWS EUROPEAN AVALANCHE WARNING SERVICES

ICGC Institut Cartogràfic i Geològic de Catalunya

Servei Meteorològic de Catalunya

Boletín de peligro de aludes Prepirineu
Del 19/03/2026 al 20/03/2026

(Válido fuera pistas de esquí y zonas no controladas)

DÉBIL (1).

Situación primaria

Nieve húmeda

Distribución

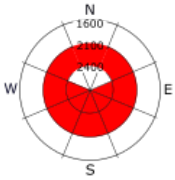

Tamaño

Origen

Tendencia

Estado del manto nivoso

El manto se muestra bastante asentado y endurecido internamente, con presencia de costras duras, grano fino y algunas formas mixtas. Para el viernes se espera más rehielo, después de una madrugada serena, y el manto se mostrará asentado. Con el humedecimiento, a partir de mediodía, debido a la transformación de la nieve por la radiación solar, no se descarta la caída de algún alud húmedo, pequeño, que no tendrá capacidad para enterrar a una persona, excepto en terreno trampa donde habrá que evitar pasar mientras la nieve no regele. Las orientaciones más sensibles a la caída de aludes de nieve húmeda son las orientadas a Este, Sur y Oeste, así como las umbrías de cota media. Habrá que vigilar con los resbalones, sobre todo por la mañana.

Distribución del manto nivoso

En umbrías hay nieve por encima de 1.600-1700 m. En solanas la nieve está presente por encima de 1.800-1.900 m. Los espesores, aunque irregulares, rondan los 65-85 cm en cotas medias.

Tendencia para las próximas 48-72h

Seguiremos con dinámica primaveral, con fusión-rehielo. Peligro: SIN CAMBIOS.

El próximo boletín será emitido el día 2026-03-20

5 MUY FUERTE	4 FUERTE	3 NOTABLE	2 LIMITADO	1 DÉBIL

EAWS EUROPEAN AVALANCHE WARNING SERVICES

ICGC Institut Cartogràfic i Geològic de Catalunya

Servei Meteorològic de Catalunya

Boletín de peligro de aludes Ter-Freser
Del 19/03/2026 al 20/03/2026

(Válido fuera pistas de esquí y zonas no controladas)

LIMITADO (2), durante las horas centrales del día.
DÉBIL (1), a primera hora.

Situación primaria

Nieve húmeda

Distribución

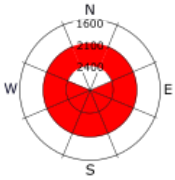

Tamaño

Origen

Tendencia

Estado del manto nivoso
Para el viernes se espera más rehielo, después de una madrugada serena. A primera hora el manto se mostrará asentado y endurecido superficialmente, pero el humedecimiento avanzará con el paso de las horas debido a la radiación solar. En solanas o en umbrías de cota media, en terreno con fuerte inclinación, pueden caer aludes de fusión de forma natural que llegarán a tamaño 1(pequeño), sin capacidad para enterrar a una persona. También es posible encontrar alguna placa antigua, formada durante el fin de semana, donde el viento no haya deflactado las laderas y encima de algún nivel débil que podría caer a nuestro paso, con una fuerte sobrecarga. Las encontraremos bajo collados y cordales por encima de 2.400 m, en orientaciones que van de E hacia S y, aisladamente, en umbrías resguardadas como N, NE y NW entre 2.200-2.400 m. En caso de romperse alguna placa se generarán aludes de hasta tamaño medio (con capacidad de enterrar a una persona).

Distribución del manto nivoso
Hay nieve en el suelo por encima de 1.700 m. El manto es esquiable a umbrías a partir de unos 1.700 m. Los grosores son muy excedentarios para la época del año y en lugares no afectados por el viento oscilan entre 85-105 cm a unos 2.000 my más de 150 cm por encima de 2.400 m.

Tendencia para las próximas 48-72h
Seguiremos con dinámica primaveral, con fusión-rehielo. Peligro: SIN CAMBIOS.

El próximo boletín será emitido el día 2026-03-20

5 MUY FUERTE	4 FUERTE	3 NOTABLE	2 LIMITADO	1 DÉBIL

EAWS EUROPEAN AVALANCHE WARNING SERVICES