# PREALPI

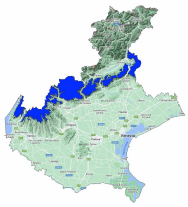

Bollettino Valanghe N. 375/2026 del 19/03/2026 ore 14.00
Validità 48 ore prossima emissione 20/03/2026
**A cura del Servizio METEOMONT dell'ARMA dei CARABINIERI**
**In collaborazione con Servizio Meteorologico dell'Aeronautica militare**

## SITUAZIONE alle 14:00 del 19/03/2026

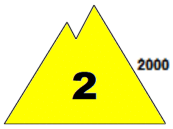


**SITUAZIONE TIPO: neve a debole coesione e vento.**

**SITUAZIONE TIPO: situazione primaverile.**

| Quota neve (mslm) | Nord | Sud |
|---|---|---|
| | 1100 - 1500 | 1500 - 1900 |

| Altezza Neve (cm) | Neve al suolo | Neve Fresca | Quota (mslm) |
|---|---|---|---|
| | 100 | 000 | 1828 |
| | 54 | 000 | 1460 |

**VALANGHE OSSERVATE: Nessuna valanga.**

## PREVISIONI 20/03/2026

## GRADO DI PERICOLO: MODERATO 2

## SITUAZIONE TIPO: neve a debole coesione e vento.

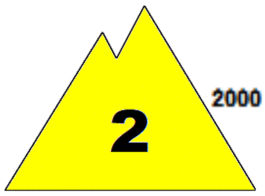


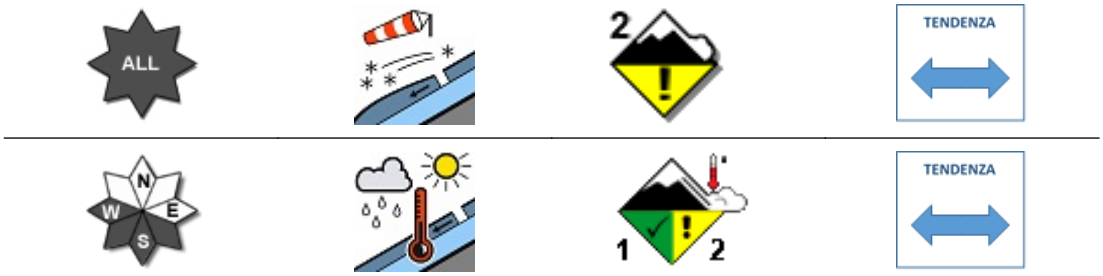


## SITUAZIONE TIPO: situazione primaverile.

**MANTO NEVOSO: La stabilità del manto nevoso è scarsa su alcuni punti (aree) per tutte le esposizioni al di sopra di 2000 mslm, possibili valanghe di dimensioni medie.**
**La stabilità del manto nevoso è scarsa su alcuni punti (aree) per versanti al sole al di sotto di 2000 mslm, possibili valanghe di dimensioni medie.**

## AVVERTENZE

A seguito dell'attività eolica registrata sono da evitare le zone di accumulo, conche, canaloni, cambi di pendenza e pendii sotto vento in genere.

## SCALA EUROPEA DEL GRADO DI PERICOLO VALANGHE

5 - MOLTO FORTE | 4 - FORTE | 3 - MARCATO | 2 - MODERATO | 1 - DEBOLE | NO NEVE | NO INFO

## LEGENDA PROBLEMA

NEVE FRESCA | LASTRONI DA VENTO | STRATI DEBOLI PERSISTENTI | NEVE BAGNATA | SLITTAMENTO | CORNICI | NESSUN PROBLEMA VALANGHIVO EVIDENTE | NO_INFO

**Bollettino realizzato su scala sinottica-regionale (standard EAWS). La sua valutazione non può escludere in alcun modo la necessità di una seria e capace valutazione locale del pericolo (singolo pendio) che può essere anche sensibilmente diverso. Le previsioni meteorologiche sono relative all'orario UTC (per l'Italia +1 in inverno e +2 in estate).**

MINISTERO DELLA DIFESA

meteomont
Servizio Nazionale di previsione neve e valanghe

EAWS EUROPEAN AVALANCHE WARNING SERVICES

CARABINIERI

In collaborazione con: arpav

# PREALPI

## PREVISIONE METEO

| Quota | | 20/03/2026 h6:00 | 20/03/2026 h12:00 | 20/03/2026 h18:00 |
|---|---|---|---|---|
| 1000 | Venti | 02 Nodi da N-Est | 02 Nodi da Ovest | 01 Nodi da Sud |
| | Temperature | +02 °C | +04 °C | +04 °C |
| | Temp.percepita | 2 °C | 4 °C | 4 °C |
| 2000 | Venti | 03 Nodi da N-Est | 03 Nodi da Nord | 04 Nodi da N-Est |
| | Temperature | -02 °C | -02 °C | +00 °C |
| | Temp.percepita | -4 °C | -4 °C | -3 °C |
| 3000 | Venti | 06 Nodi da N-Est | 07 Nodi da Nord | 08 Nodi da N-Est |
| | Temperature | -08 °C | -06 °C | -06 °C |
| | Temp.percepita | -13 °C | -11 °C | -12 °C |
| Zero termico | | 1300-1500 m. | 1400-1600 m. | 1800-2000 m. |
| Fenomeno | | — | — | — |
| Stato del cielo | | | | |

## LEGENDA FENOMENI

— Assenza Fenomeni · Nebbia · Foschia · Pioggia debole · Pioggia moderata · Pioggia forte · Temporali

Nevicata debole · Nevicata moderata · Nevicata forte

## STATO DEL CIELO

Sereno · Poco nuvoloso · Nuvoloso · Molto nuvoloso · Coperto

## Parametri meteonivometrici registrati presso i campi di rilevamento il 19/03/2026.

| Località | Comune | Quota (m.s.l.m.) | Altezza neve (cm) | Neve caduta nelle 24 ore (cm) | Temp. Min (°C) | Temp. Max (°C) | Condizioni del tempo |
|---|---|---|---|---|---|---|---|
| PIAN CANSIGLIO | Tambre (BL) | 1025 | 0 | 0 | -5 | +9 | Assenza di precipitazioni |
| GALLIO - BUSA FONDA | Gallio (VI) | 1460 | 54 | 0 | -6 | +7 | Assenza di precipitazioni |
| MONTI LESSINI - MALGA SAN GIORGIO | Bosco Chiesanuova (VR) | 1461 | 32 | 0 | -4 | +6 | Assenza di precipitazioni |
| MONTE BALDO | Malcesine (VR) | 1828 | 100 | 0 | -6 | +5 | Assenza di precipitazioni |

(*) Rilievi fuori campo

**L'INFORMAZIONE E' PREVENZIONE - LEGGI L'ATTUALE GRADO DI PERICOLO VALANGHE!**

**IL CAPO DEL CENTRO NAZIONALE METEOMONT**
**(Ten. Col. RFI Emanuela Gini)**
**FIRMA AUTOGRAFA OMESSA AI SENSI**
**DELL'ART.3 DEL D.LGS N.39/1993**